Pericolo valanghe

aggiornato al 13.4.2026, 08:00

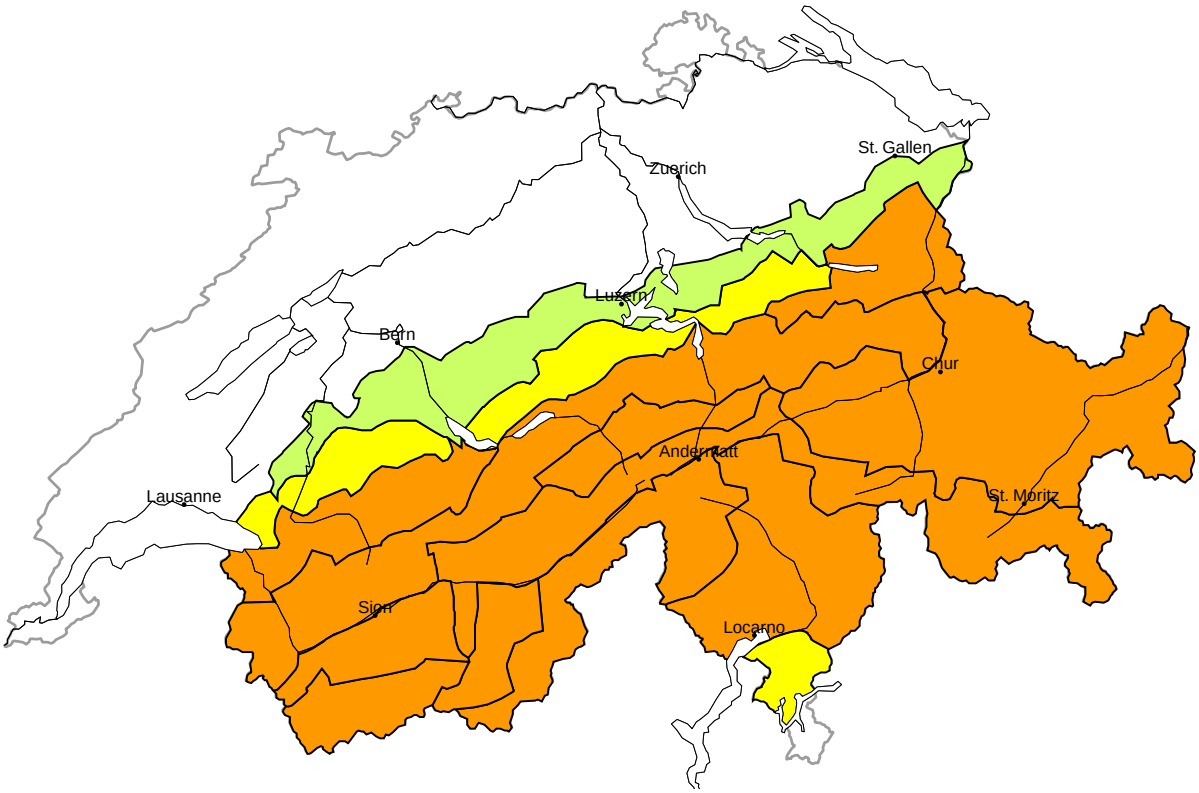

regione A

Marcato (3+)

Neve fresca, Strati deboli persistenti

Punti pericolosi

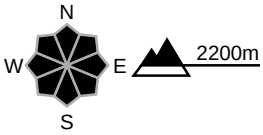

Descrizione del pericolo

Cadrà meno neve del previsto.
La neve fresca e la neve ventata sono instabili in quota. Nel corso della giornata sono possibili sempre più numerose valanghe asciutte spontanee. Le valanghe asciutte possono in parte coinvolgere il manto di neve vecchia e raggiungere grandi dimensioni. Esse possono trascinare la neve vecchia bagnata e avanzare sino all'aperta campagna. Le escursioni richiedono molta esperienza nella valutazione del pericolo di valanghe e cautela.

Marcato (3)

Neve bagnata

Con la pioggia, sono previste numerose valanghe bagnate, specialmente sui pendii ripidi esposti a ovest, nord ed est al di sotto dei 2200 m circa. Le valanghe bagnate possono in parte trascinare l'intero manto nevoso e raggiungere grandi dimensioni. Per le escursioni, le condizioni sono critiche.

Scala del pericolo 1 debole | 2 moderato | 3 marcato | 4 forte | 5 molto forte

regione B

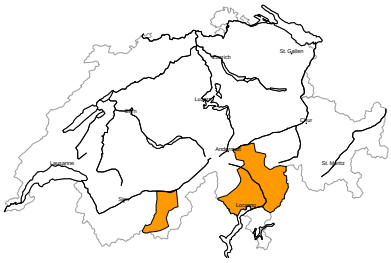

Marcato (3=)

Neve fresca, Strati deboli persistenti

Punti pericolosi

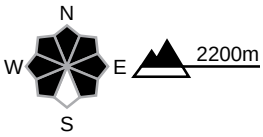

Descrizione del pericolo
La neve fresca e la neve ventata sono instabili in quota. Le valanghe asciutte possono anche coinvolgere il manto di neve vecchia e raggiungere grandi dimensioni. Nel corso della giornata sono possibili isolate valanghe spontanee. Le escursioni e le discese fuori pista richiedono esperienza nella valutazione del pericolo di valanghe e attenzione.

Marcato (3)

Neve bagnata

Con la pioggia, sono previste numerose valanghe bagnate, specialmente sui pendii ripidi esposti a ovest, nord ed est al di sotto dei 2200 m circa. Le valanghe bagnate possono in parte trascinare l'intero manto nevoso e raggiungere grandi dimensioni. Per le escursioni, le condizioni sono critiche.

regione C

Marcato (3-)

Lastroni da vento, Strati deboli persistenti

Punti pericolosi

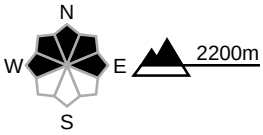

Descrizione del pericolo
Con neve fresca e vento proveniente da sud si formeranno accumuli di neve ventata instabili. Un singolo appassionato di sport invernali può provocare il distacco di valanghe. In alcuni punti, le valanghe asciutte possono anche subire un distacco nella neve vecchia e raggiungere grandi dimensioni a livello isolato. Le escursioni richiedono esperienza nella valutazione del pericolo di valanghe.

Marcato (3)

Neve bagnata

La superficie del manto nevoso non riuscirà praticamente quasi a rigelarsi e si ammorbidirà rapidamente. Sono previste valanghe bagnate e per scivolamento di neve. Ciò soprattutto sui pendii ripidi esposti a est, sud e ovest tra i 2000 e i 2800 m circa, come pure sui pendii ripidi esposti a nord al di sotto dei 2400 m circa. Inoltre, in alcuni punti le valanghe bagnate possono subire un distacco in seguito al passaggio di persone. Le valanghe possono raggiungere grandi dimensioni.
Per le escursioni, le condizioni sono critiche.

regione D

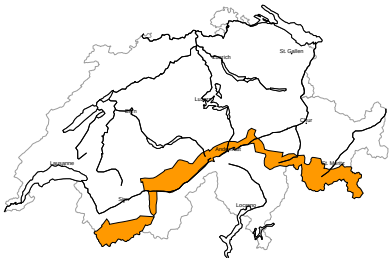

Marcato (3-)

Lastroni da vento, Strati deboli persistenti

Punti pericolosi

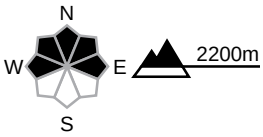

Descrizione del pericolo
Con neve fresca e vento proveniente da sud si formeranno accumuli di neve ventata instabili. Un singolo appassionato di sport invernali può provocare il distacco di valanghe. In alcuni punti, le valanghe asciutte possono anche subire un distacco nella neve vecchia e raggiungere grandi dimensioni a livello isolato. Le escursioni richiedono esperienza nella valutazione del pericolo di valanghe.

Marcato (3)

Neve bagnata
Con la pioggia, sono previste numerose valanghe bagnate, specialmente sui pendii ripidi esposti a ovest, nord ed est al di sotto dei 2200 m circa. Le valanghe bagnate possono in parte trascinare l'intero manto nevoso e raggiungere grandi dimensioni. Per le escursioni, le condizioni sono critiche.

regione E

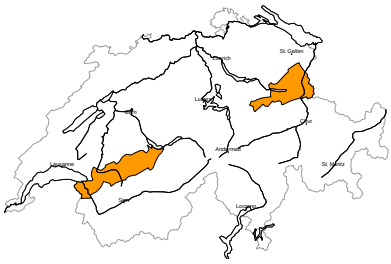

Marcato (3)

Neve bagnata
La superficie del manto nevoso non riuscirà praticamente quasi a rigelarsi e si ammorbidirà rapidamente. Sono previste valanghe bagnate e per scivolamento di neve. Ciò soprattutto sui pendii ripidi esposti a est, sud e ovest tra i 2000 e i 2800 m circa, come pure sui pendii ripidi esposti a nord al di sotto dei 2400 m circa. Inoltre, in alcuni punti le valanghe bagnate possono subire un distacco in seguito al passaggio di persone. Le valanghe possono raggiungere grandi dimensioni.
Per le escursioni, le condizioni sono critiche.

Debole (1)

Nessun problema valanghivo evidente

Punti pericolosi

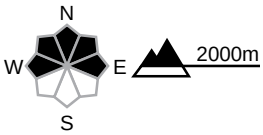

Descrizione del pericolo
Non si prevedono praticamente più valanghe asciutte. Punti pericolosi molto isolati si trovano soprattutto sui pendii ripidi estremi ombreggiati in quota.

regione F

Marcato (3)

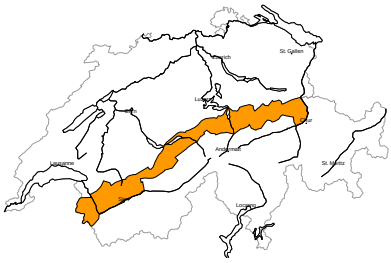

Neve bagnata

La superficie del manto nevoso non riuscirà praticamente quasi a rigelarsi e si ammorbidirà rapidamente. Sono previste valanghe bagnate e per scivolamento di neve. Ciò soprattutto sui pendii ripidi esposti a est, sud e ovest tra i 2000 e i 2800 m circa, come pure sui pendii ripidi esposti a nord al di sotto dei 2400 m circa. Inoltre, in alcuni punti le valanghe bagnate possono subire un distacco in seguito al passaggio di persone. Le valanghe possono raggiungere grandi dimensioni.
Per le escursioni, le condizioni sono critiche.

Moderato (2=)

Lastroni da vento

Punti pericolosi

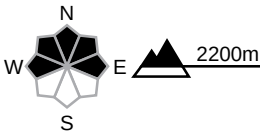

Descrizione del pericolo
Con vento proveniente da sud localmente si formeranno accumuli di neve ventata per lo più di piccole dimensioni. Questi ultimi si trovano soprattutto nelle zone in prossimità delle creste, nelle conche e nei canaloni. Le valanghe possono in alcuni punti distaccarsi in seguito al passaggio di un singolo appassionato di sport invernali e raggiungere dimensioni medie.
Si raccomanda una prudente scelta dell'itinerario.

regione G

Marcato (3)

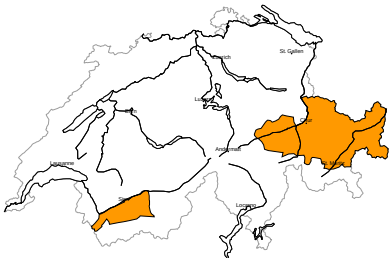

Neve bagnata

La superficie del manto nevoso non riuscirà praticamente quasi a rigelarsi. A partire dalla mattinata sono possibili valanghe bagnate. Ciò soprattutto sui pendii soleggiati ripidi tra i 2000 e i 3000 m circa, come pure sui pendii ripidi esposti a nord al di sotto dei 2400 m circa. Le valanghe bagnate possono subire un distacco in seguito al passaggio di persone. Isolati rumori di "whum" sono possibili segnali di pericolo. Le valanghe possono raggiungere grandi dimensioni.
Le condizioni per le escursioni sono critiche.

Moderato (2=)

Lastroni da vento, Strati deboli persistenti

Punti pericolosi

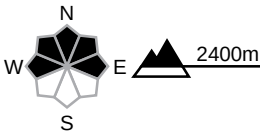

Descrizione del pericolo
In alcuni punti, le valanghe asciutte possono subire un distacco nella neve vecchia e raggiungere grandi dimensioni a livello isolato. Questi punti pericolosi sono difficilmente individuabili anche da parte dell'escursionista esperto. Attenzione nelle zone scarsamente innevate nelle zone escursionistiche poco frequentate.
Con vento proveniente da sud localmente si formeranno accumuli di neve ventata di dimensioni piuttosto piccole.
Si raccomanda una prudente scelta dell'itinerario.

regione H

Moderato (2)

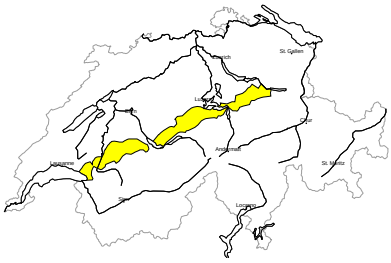

Neve bagnata

Sono possibili valanghe bagnate e per scivolamento di neve, anche di medie dimensioni. I punti pericolosi si trovano soprattutto sui pendii esposti a ovest, nord ed est.
È importante una prudente scelta dell'itinerario.

Debole (1)

Nessun problema valanghivo evidente

Punti pericolosi

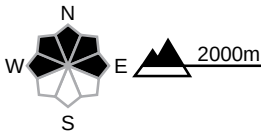

Descrizione del pericolo
Non si prevedono praticamente più valanghe asciutte. Punti pericolosi molto isolati si trovano soprattutto sui pendii ripidi estremi ombreggiati in quota.

regione I

Moderato (2)

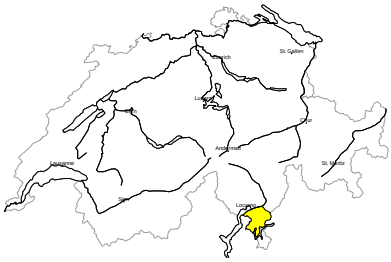

Neve bagnata

Con la pioggia, sono possibili valanghe bagnate, specialmente sui pendii ripidi esposti a ovest, nord ed est. Le valanghe possono raggiungere dimensioni medie a livello isolato.
Già una valanga di piccole dimensioni può provocare il trascinamento e la caduta di persone.

regione J

Debole (1)

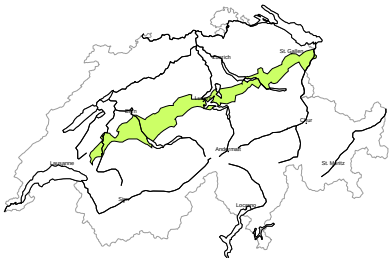

Neve bagnata

Sui pendii erbosi ripidi, sono possibili isolate colate bagnate. Attenzione al pericolo di trascinamento e di caduta.

Manto nevoso e meteo

aggiornato al 12.4.2026, 17:00

Manto nevoso

Con il tempo mite, le notti in parte coperte e la pioggia a tratti, nel corso della settimana che volge al termine è ulteriormente progredita l'umidificazione del manto nevoso. Sui pendii esposti a sud il manto nevoso è completamente umidificato fino ai 3000 m circa, su quelli esposti a est e a ovest fino a una fascia compresa fra i 2500 e i 2700 m. Sui pendii esposti a nord è completamente umidificato al di sotto dei 2000 m, mentre tra i 2000 e i 2400 m l'umidificazione sta progredendo.
Con le previste nevicate, a tratti intense nelle regioni meridionali, si formeranno in quota grandi accumuli di neve ventata. Specialmente sui pendii esposti a nord, le valanghe spontanee potranno in alcuni casi coinvolgere l'intero manto nevoso, soprattutto nelle zone più colpite dalle precipitazioni nel Vallese, ma a livello isolato anche nelle altre regioni. Saranno inoltre possibili distacchi di valanghe nella neve fresca e ventata in seguito al passaggio di persone.
Con la pioggia, si prevede un progressivo aumento delle valanghe bagnate e per scivolamento di neve.

Retrospettiva meteo fino a domenica

Il cielo è stato per lo più nuvoloso con deboli rovesci nelle Prealpi. Il limite delle nevicate era collocato intorno ai 2000 m. Nei Grigioni ci sono state parziali schiarite.

Neve fresca
-

Temperatura
Sul mezzogiorno a 2000 m compresa tra +3 °C nelle regioni settentrionali e in Ticino e +6 °C nelle regioni alpine interne

Vento
Da debole a moderato, nel corso della giornata sulla cresta settentrionale delle Alpi da moderato a forte, proveniente dai quadranti meridionali

Previsioni meteo fino a lunedì

Domenica sera, nelle regioni meridionali inizieranno nuove precipitazioni, che si intensificheranno nella notte fra domenica e lunedì e risulteranno localmente molto abbondanti nelle regioni meridionali. Le precipitazioni si estenderanno anche nelle regioni settentrionali, dove tuttavia saranno più deboli. Il limite delle nevicate si collocherà tra i 1800 e i 2000 m; fino a lunedì mattina, nelle zone più colpite dalle precipitazioni nella parte altovallesana della cresta principale delle Alpi scenderà poi fino a una fascia compresa fra i 1500 e i 1700 m.

Neve fresca
Fino a lunedì pomeriggio, al di sopra di una fascia compresa fra i 2200 e i 2400 m:
- Regione del Monte Rosa, valle di Saas, zona del Sempione: dai 60 agli 80 cm
- Restante parte altovallesana della cresta principale delle Alpi, Ticino nord occidentale: dai 40 ai 60 cm
- Restante cresta principale delle Alpi dal Gran San Bernardo al passo del Lucomagno, cresta settentrionale delle Alpi dalla Lötschental alla Reuss, Valle Maggia inferiore, Leventina: dai 20 ai 40 cm
- Restante Vallese, restante cresta settentrionale delle Alpi a ovest del Tödi, cresta principale delle Alpi dal passo del Lucomagno fino alla zona del Bernina: dai 15 ai 30 cm
- Altrove: pochi centimetri o tempo asciutto

Temperatura
Sul mezzogiorno a 2000 m di +2 °C nelle regioni occidentali e meridionali e +4 °C in quelle orientali

Vento
Nella notte fra domenica e lunedì, in alta montagna forte, altrimenti da moderato a forte proveniente da sud a sud est, in attenuazione nel pomeriggio

Tendenza

Martedì
Il tempo sarà molto nuvoloso con deboli precipitazioni. Nelle regioni settentrionali il limite delle nevicate si collocherà tra i 1500 e i 1800 m, in quelle meridionali tra i 1800 e i 2000 m. Nel corso della giornata ci saranno schiarite soprattutto nel Vallese e nelle regioni meridionali. Il vento proveniente da nord est sarà da debole a moderato.
Nelle regioni meridionali il pericolo di valanghe asciutte diminuirà. In quota le condizioni per le escursioni rimarranno tuttavia critiche. Nelle regioni settentrionali il pericolo di valanghe asciutte non subirà variazioni degne di nota. In tutte le regioni saranno possibili valanghe bagnate, soprattutto sui pendii esposti a ovest, a nord e a est situati al di sotto dei 2400 m circa. Nelle regioni interessate da apporti di neve fresca, con l'irraggiamento si prevedono in quota valanghe di neve a debole coesione che coinvolgeranno la neve fresca e alle quote di media montagna scaricamenti di neve umida e valanghe per scivolamento di neve.

Mercoledì
Il tempo sarà piuttosto soleggiato, con possibilità di isolati deboli rovesci nel corso della giornata. La soglia dello zero termico salirà fino ai 2800 m. Il vento sarà per lo più debole. Il pericolo di valanghe asciutte diminuirà, mentre quello di valanghe bagnate aumenterà nel corso della giornata.