GOBIERNO DE ESPAÑA
VICEPRESIDENCIA TERCERA DEL GOBIERNO
MINISTERIO PARA LA TRANSICIÓN ECOLÓGICA Y EL RETO DEMOGRÁFICO

Boletín de información nivológica y de peligro de aludes

Pirineo Catalán

aemet Agencia Estatal de Meteorología

martes, 14 de abril de 2026

Pronóstico hasta las 24 horas del miércoles, día 15 de abril

(Válido fuera de pistas de esquí balizadas y abiertas)

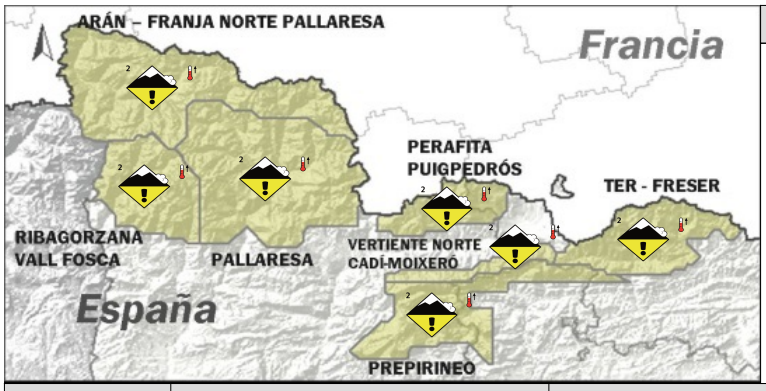

Problemas de aludes

Placas de viento

Nieve húmeda

Macizo	Peligro	Problemas de aludes, cota, orientación, tamaño	Innivación observada (m)
Arán - Franja norte Pallaresa	2 / 2 / 1→2 / 1800 / Durante el día **Limitado**	**Placas de viento**: 1800, N E S O, 2 **Nieve húmeda**: 1500, N E S O, 2	2026-04-14 N S Cotas medias
Ribagorzana - Vall Fosca	2 / 2 / 1 / 2200 **Limitado**	**Placas de viento**: 2400, N E S O, 2 **Nieve húmeda**: 2100, N E S O, 1	2026-04-14 N S Cotas medias
Pallaresa	2 / 2 / 1 / 2200 **Limitado**	**Placas de viento**: 2400, N E S O, 2 **Nieve húmeda**: 2100, N E S O, 1	2026-04-14 N S Cotas medias

AEMET. Se autoriza la reproducción de su contenido citando la fuente.

Boletín de información nivológica y de peligro de aludes

Pirineo Catalán

Perafita - Puigpedrós	2 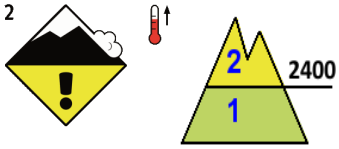 **Limitado**	**Placas de viento** **Nieve húmeda** 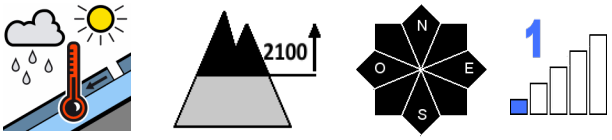	2026-04-14 Cotas medias
Ter - Freser	2 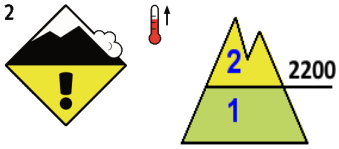 **Limitado**	**Placas de viento** **Nieve húmeda** 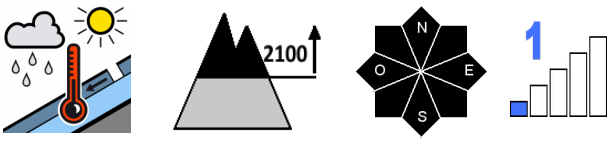	2026-04-14 Cotas medias
Vertiente norte Cadí - Moixeró	2 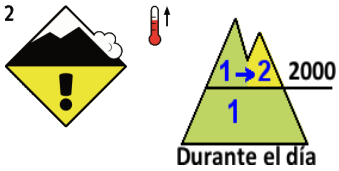 **Limitado**	**Placas de viento** **Nieve húmeda** 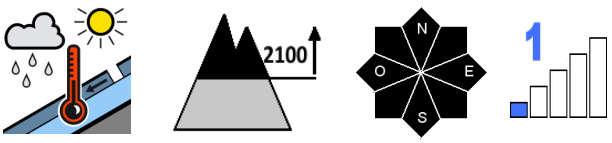	2026-04-14 Cotas medias
Prepirineo	2 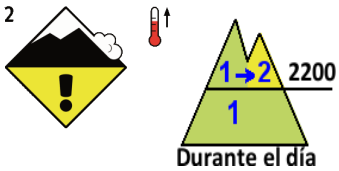 **Limitado**	**Placas de viento** **Nieve húmeda** 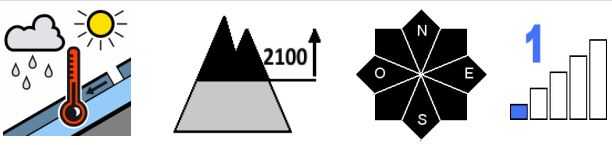	2026-04-14 Cotas medias

Estado del manto y observaciones recientes

Durante las últimas 24 h se han registrado nevadas débiles en el Arán-F.N.Pallaresa, 4-9 l/m2. En el resto de sectores se registran perdidas de espesores en torno a 4-10 cm, con alguna nevada muy débil y ventisca en Vallter 2000.

La nieve reciente se ha depositado sobre un manto muy húmedo y de perfil primaveral por el ambiente cálido de la semana pasada. Las nevadas del fin de semana, y estas últimas por nubosidad de retención en el norte, vinieron acompañadas de vientos intensos de componente sur girando a norte que formaron en cotas altas placas de viento en todas las orientaciones.

AEMET. Se autoriza la reproducción de su contenido citando la fuente.

Hay nieve esquiable por encima de 1800-2000 m en umbrías y de 2100-2300 m en solanas. Los espesores son excedentarios para la época en la mayoría de sectores: 194 cm en Lac Redón a 2247 m en el Arán-F.N.Pallaresa, 154 cm en Cadí Nord a 2143 m en el V.N Cadí-Moixeró, 115 cm en Vallter 2000 y 76 cm en el Port del Comte a 2316 m en el Prepirineo.

Evolución del manto y peligro de aludes para el miércoles, día 15

Problemas de nieve húmeda y, en cotas altas, de placas de viento.

Mañana miércoles, tras un rehielo nocturno efectivo, podrán formarse costras que sustenten el manto a primeras horas. No obstante, a consecuencia del aumento de la temperatura diurna y la radiación solar, en el transcurso de la jornada se esperan purgas y aludes de nieve húmeda, más probables en solanas y a partir del mediodía, e incluso se podrían producir deslizamientos basales en terrenos herbosos o de roca lisa. Por lo general serán pequeños (riesgo de caída), localmente medianos (capaz de enterrar a una persona).

En cotas altas, principalmente cerca de crestas y collados, se formaron placas de viento durante las recientes nevadas que pueden engrosarse por el transporte de nieve reciente con el viento del norte. Aunque se estabilizan rápidamente en laderas soleadas, pueden mantenerse aún frágiles en las umbrías. Su ruptura accidental podrá desencadenar aludes pequeños o localmente medianos.

Predicción meteorológica para el miércoles, día 15

Poco nuboso o despejado aumentando a nuboso con nubes bajas por la tarde en el Arán y divisoria fronteriza.
No se descartan precipitaciones débiles a últimas horas en el Arán y Franja Norte Pallaresa, con la cota de nieve en 2200-2400 metros.
Temperaturas mínimas en ascenso en el área occidental y sin cambios o en ligero ascenso en la oriental. Máximas en notable ascenso. Heladas débiles o localmente moderadas en cotas altas.
Viento flojo o moderado de componente norte.

Datos en la atmósfera libre:

Altitud de la isoterma de 0 ºC: 3200 m
Altitud de la isoterma de -10 ºC: 4900 m

Viento a 1500 m: N 10 km/h
Viento a 3000 m: N 30 km/h

Evolución para el jueves día 16

Nivel de peligro sin cambios.

Escala europea de peligro de aludes

Débil | Limitado | Notable | Fuerte | Muy Fuerte

Problemas de aludes

Nieve reciente | Placas de viento | Capas débiles persistentes | Nieve húmeda | Deslizamientos basales | Sin problema evidente

AEMET. Se autoriza la reproducción de su contenido citando la fuente.

Nota1: Se recuerda que, siempre que haya nieve, la ausencia total de peligro no existe. Hay que tener presente que en circunstancias desfavorables, con aludes de tamaño 1 (alud pequeño o colada) y tamaño 2 (alud mediano), se pueden sufrir severos daños personales.

Nota2: Los BPA se elaboran en base a información meteorológica así como al estado del manto nivoso a través de sondeos puntuales. Se advierte a los usuarios de la variabilidad de esta información al extrapolarla a zonas extensas de montaña. Por ello, AEMET no se hace responsable de su uso para la toma de decisiones que conciernen a la seguridad personal, ni de los riesgos físicos o materiales de ellas derivadas.

AEMET. Se autoriza la reproducción de su contenido citando la fuente.