GOBIERNO DE ESPAÑA
VICEPRESIDENCIA TERCERA DEL GOBIERNO
MINISTERIO PARA LA TRANSICIÓN ECOLÓGICA Y EL RETO DEMOGRÁFICO

Boletín de información nivológica y de peligro de aludes

Pirineo Navarro y Aragonés

aemet Agencia Estatal de Meteorología

martes, 14 de abril de 2026

Pronóstico hasta las 24 horas del miércoles, día 15 de abril

(Válido fuera de pistas de esquí balizadas y abiertas)

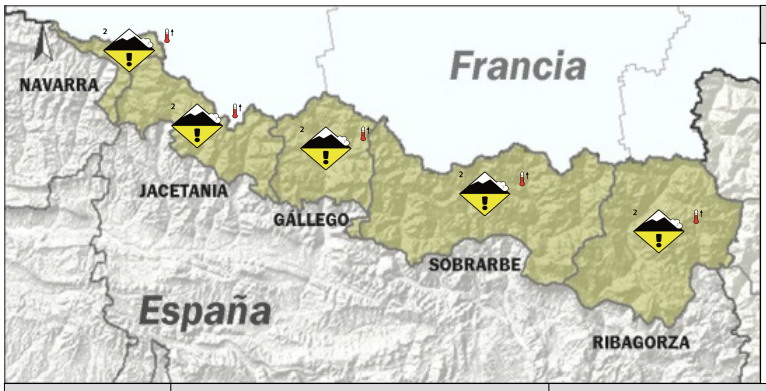

Problemas de aludes

Placas de viento

Nieve húmeda

Macizo	Peligro	Problemas de aludes, cota, orientación, tamaño	Innivación observada (m)
Navarra	2 2 / 1→2 2200 Durante el día **Limitado**	**Placas de viento** 2200 N O E S 2 **Nieve húmeda** N O E S 2	2026-04-14 N S Cotas medias
Jacetania	2 2 / 1→2 2200 Durante el día **Limitado**	**Placas de viento** 2200 N O E S 2 **Nieve húmeda** N O E S 2	2026-04-14 N S Cotas medias
Gállego	2 2 / 1→2 2200 Durante el día **Limitado**	**Placas de viento** 2200 N O E S 2 **Nieve húmeda** N O E S 2	2026-04-14 N S Cotas medias

AEMET. Se autoriza la reproducción de su contenido citando la fuente.

Boletín de información nivológica y de peligro de aludes

Pirineo Navarro y Aragonés

Sobrarbe	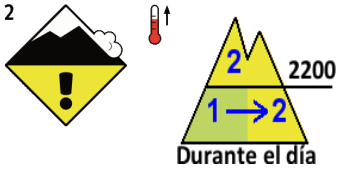 **Limitado**	**Placas de viento** **Nieve húmeda** 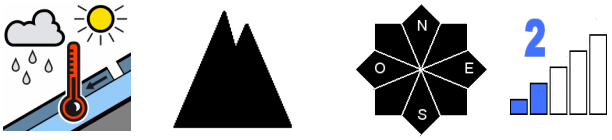	2026-04-14
Ribagorza	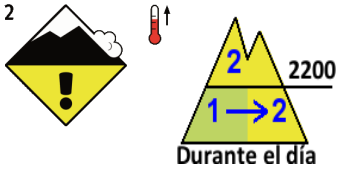 **Limitado**	**Placas de viento** 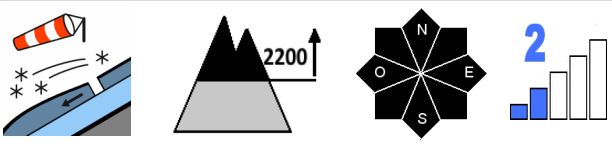 **Nieve húmeda** 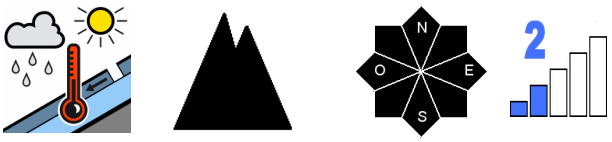	2026-04-14

Estado del manto y observaciones recientes

Durante las últimas 24 h se han registrado algunas precipitaciones débiles: 3 l/m2 en Belagua en forma de nieve-lluvia a 1400 m, 6 l/m2 en Linza en forma de nieve a 1300 m y 4 l/m2 en Bachimaña a 2200 m con ventisca. En el Sobrarbe y la Ribagorza se registran perdidas de espesores de 5-7 cm, con nieve-lluvia muy débil en Estós a 1900 m y ventisca en Ángel Orús a 2100 m.
La nieve reciente se ha depositado sobre un manto muy húmedo y de perfil primaveral por el ambiente cálido de la semana pasada. Las nevadas del fin de semana, y estas últimas por nubosidad de retención en el norte, vinieron acompañadas de vientos intensos de componente sur girando a norte que formaron en cotas altas placas de viento en todas las orientaciones.
Comienza el manto continuo en cotas medias, con espesores elevados para la época : 160 cm en Llano de la Contienda a 1749 m en el sector navarro, 118 cm en La Raca a 2276 m en la Jacetania, 146 cm en Respomuso a 2145 m en el Alto Gállego, 68 cm en Góriz a 2195 m en el Sobrarbe y 175 cm en la Renclusa a 2140 m en la Ribagorza.
En las últimas 24 h se han observado varios aludes medianos en el Alto Gállego con salida a 2500-3000 m en orientación NW.

Evolución del manto y peligro de aludes para el miércoles, día 15

Problemas de nieve húmeda y, en cotas altas, de placas de viento.

Mañana miércoles, tras un rehielo nocturno efectivo, podrán formarse costras que sustenten el manto a primeras horas. No obstante, a consecuencia del aumento de la temperatura diurna y la radiación solar, en el transcurso de la jornada se esperan purgas y aludes de nieve húmeda, más probables en solanas y a partir del mediodía, e incluso se podrían producir deslizamientos basales en terrenos herbosos o de roca lisa. Por lo general serán pequeños (riesgo de caída), localmente medianos (capaz de enterrar a una persona).

AEMET. Se autoriza la reproducción de su contenido citando la fuente.

En cotas altas, principalmente cerca de crestas y collados, se formaron placas de viento durante las recientes nevadas que pueden engrosarse por el transporte de nieve reciente con el viento del norte. Aunque se estabilizan rápidamente en laderas soleadas, pueden mantenerse aún frágiles en las umbrías. Su ruptura accidental podrá desencadenar aludes pequeños o localmente medianos.

Predicción meteorológica para el miércoles, día 15

Pirineo navarro:
Poco nuboso o despejado aumentando por la tarde a intervalos nubosos con nubes bajas. No se descartan precipitaciones débiles en la divisoria fronteriza a últimas horas, con la cota de nieve en torno a 2200 metros. Temperaturas en ascenso, localmente notable. Heladas débiles en cumbres de Larra. Viento moderado de componente norte.
Pirineo aragonés:
Poco nuboso o despejado aumentando a nuboso con nubes bajas por la tarde en la divisoria fronteriza. No se descartan precipitaciones débiles en la divisoria fronteriza por la tarde y últimas horas, con la cota de nieve en torno a 2200-2400 metros. Temperaturas en ascenso localmente notable, más acusado de las máximas. Heladas débiles en cotas altas. Viento flojo o moderado de componente norte.

Datos en la atmósfera libre:

Altitud de la isoterma de 0 ºC: 3200 m
Altitud de la isoterma de -10 ºC: 4900 m

Viento a 1500 m: N 10 km/h
Viento a 3000 m: NW 20 km/h

Evolución para el jueves día 16

Nivel de peligro sin cambios.

(Información elaborada a partir de los datos recibidos de los refugios de Linza, Lizara, Respomuso, Panticosa, Bachimaña, Góriz, Pineta, Estós, Angel Orús, La Renclusa, Cap de Llauset y Belagua, de las estaciones de esquí de Formigal y Panticosa (lagos) y de Ordesa Pradera)

Escala europea de peligro de aludes

Débil | Limitado | Notable | Fuerte | Muy Fuerte

Problemas de aludes

Nieve reciente | Placas de viento | Capas débiles persistentes | Nieve húmeda | Deslizamientos basales | Sin problema evidente

Nota1: Se recuerda que, siempre que haya nieve, la ausencia total de peligro no existe. Hay que tener presente que en circunstancias desfavorables, con aludes de tamaño 1 (alud pequeño o colada) y tamaño 2 (alud mediano), se pueden sufrir severos daños personales.

Nota2: Los BPA se elaboran en base a información meteorológica así como al estado del manto nivoso a través de sondeos puntuales. Se advierte a los usuarios de la variabilidad de esta información al extrapolarla a zonas extensas de montaña. Por ello, AEMET no se hace responsable de su uso para la toma de decisiones que conciernen a la seguridad personal, ni de los riesgos físicos o materiales de ellas derivadas.

AEMET. Se autoriza la reproducción de su contenido citando la fuente.