Mittwoch 15.04.2026

Veröffentlicht am 14.04.2026 um 17:00

Vormittag

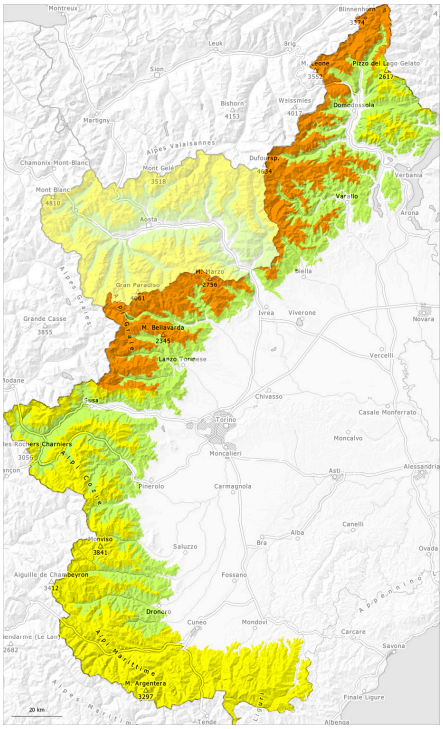

Nachmittag

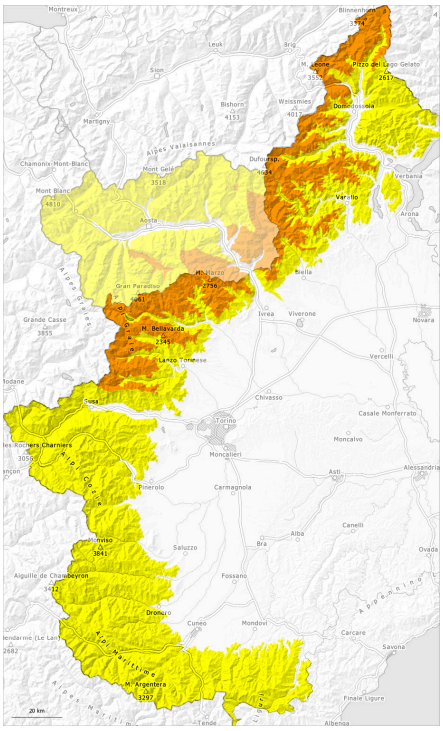

1	2	3	4	5
gering	mäßig	erheblich	groß	sehr groß

Gefahrenstufe 3 - Erheblich

AM:

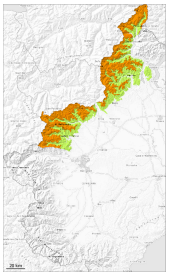

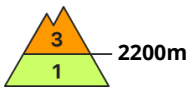

Tendenz: Lawinengefahr nimmt ab
am Donnerstag, den 16.04.2026

Triebschnee

2200m

PM:

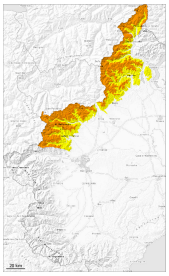

Tendenz: Lawinengefahr nimmt ab
am Donnerstag, den 16.04.2026

Triebschnee

2200m

Nassschnee

2600m

Neu- und Triebschnee in der Höhe. Vor allem aber nimmt die Gefahr von feuchten und nassen Lawinen im Tagesverlauf zu.

Der obere Teil der Schneedecke ist instabil.

Oberhalb von rund 2200 m: Mit Neuschnee und Nordostwind entstanden in den letzten zwei Tagen in Kamm- und Passlagen teils störanfällige Triebschneeansammlungen. Lawinen können in oberflächennahen Schichten ausgelöst werden und vor allem an sehr steilen Schattenhängen groß werden.

V.a. an sehr steilen Grashängen und an felsdurchsetzten Hängen sind mit der Anfeuchtung mittlere und vereinzelt große nasse Lawinen im Tagesverlauf möglich.

Spontane Lawinen und Durchbrechen in den Altschnee sind Hinweise für die hohe Gefahr.

Schneedecke

Gefahrenmuster gm.6: lockerer schnee und wind | gm.10: frühjahrssituation

In den letzten zwei Tagen fielen oberhalb von rund 2000 m verbreitet 40 bis 60 cm Schnee, lokal auch mehr. Gestern wurden oberhalb von rund 2500 m zahlreiche kleine und mittlere Lawinen beobachtet. In hohen Lagen sind mehrere teils große Staublawinen abgegangen.
Klare Nacht: Die Schneeoberfläche ist tragfähig gefroren, dies auch in tiefen und mittleren Lagen.

Schattenhänge sowie hohe Lagen: Neu- und Triebschnee liegen verbreitet auf einer harten Kruste.

Sonne und Wärme führen im Tagesverlauf zu einer allmählichen Anfeuchtung der Schneedecke. Dies vor allem an steilen Ost-, Süd- und Westhängen unterhalb von rund 2700 m sowie an Nordhängen unterhalb von rund 2400 m.

Unterhalb von rund 2500 m liegt an Südhängen kein Schnee.

Die Schneedecke ist gut verfestigt, mit einer Schmelzharschkruste an der Oberfläche. Dies besonders an allen Expositionen unterhalb von rund 2300 m.

Tendenz

Es ist mild. Nach klarer Nacht allgemein günstige Verhältnisse, dann steigt die Gefahr von Nass- und Gleitschneelawinen an.

Mit starken Temperaturschwankungen und Sonneneinstrahlung stabilisieren sich die Triebschneeansammlungen in den nächsten Tagen.

Gefahrenstufe 2 - Mäßig

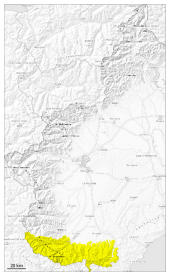

2

Tendenz: Lawinengefahr bleibt gleich
am Donnerstag, den 16.04.2026

Nassschnee

Die Gefahr von Nass- und Gleitschneelawinen besteht schon am Morgen.

Die Schneeoberfläche gefriert nur knapp und ist schon am Morgen aufgeweicht, auch in mittleren und hohen Lagen bei bedeckter Nacht.

Die spontane Aktivität von feuchten und nassen Lawinen nimmt am Vormittag rasch zu.
In tiefen und mittleren Lagen und an sehr steilen Grashängen sind mit der Durchnässung mittlere und vereinzelt große Gleitschneelawinen und feuchte Rutsche möglich.

Der nasse Neuschnee und die während dem Schneefall entstandenen, kleinen Triebschneeansammlungen können von einzelnen Wintersportlern ausgelöst werden. Spontane Lawinen und Durchbrechen in den Altschnee sind Hinweise für den schwachen Schneedeckenaufbau.

Touren und Hüttenaufstiege sollten sehr früh gestartet und beendet werden.

Schneedecke

Gefahrenmuster gm.10: frühjahrssituation gm.2: gleitschnee

In den letzten zwei Tagen fielen oberhalb von rund 2000 m 5 bis 15 cm Schnee, lokal auch mehr.

Der Schneeregen führte am Dienstag unterhalb von rund 2200 m zu einer massiven Anfeuchtung der Schneedecke. Härtere Schneeschichten liegen stellenweise auf einer nassen Altschneedecke.

Tendenz

Es ist sehr mild.
Die Schneeoberfläche gefriert nur in hohen Lagen tragfähig und weicht rasch auf.
Die frühlingshaften Wetterbedingungen führen ab dem Vormittag verbreitet zu einem Festigkeitsverlust innerhalb der Schneedecke.

Gefahrenstufe 2 - Mäßig

AM:

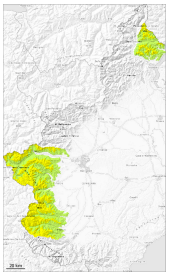

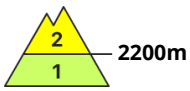

Tendenz: Lawinengefahr bleibt gleich
am Donnerstag, den 16.04.2026

Triebschnee

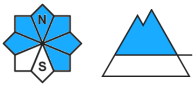

PM:

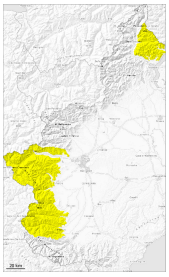

Tendenz: Lawinengefahr bleibt gleich
am Donnerstag, den 16.04.2026

Triebschnee

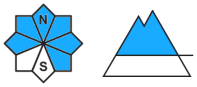

Nassschnee

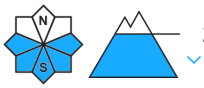

Die Gefahr von feuchten und nassen Lawinen steigt im Tagesverlauf an.

Der Neuschnee und die während dem Schneefall entstandenen, meist kleinen Triebschneeansammlungen können von einzelnen Wintersportlern ausgelöst werden. Dies vor allem an sehr steilen Hängen in hohen Lagen und im Hochgebirge sowie an Felswandfüßen und hinter Geländekanten.

V.a. an sehr steilen Hängen sind mit der Durchnässung kleine und mittlere Gleitschneelawinen und feuchte Rutsche möglich.

Touren und Hüttenaufstiege sollten früh gestartet und rechtzeitig beendet werden.

Schneedecke

Gefahrenmuster gm.6: lockerer schnee und wind | gm.10: frühjahrssituation

In den letzten zwei Tagen fielen gebietsweise oberhalb von rund 2100 m 15 bis 30 cm Schnee, lokal auch weniger.
Die Schneeoberfläche ist tragfähig gefroren und weicht schon am Vormittag auf, dies auch in tiefen und mittleren Lagen. Sonne und Wärme führen ab dem Morgen unterhalb von rund 2300 m zu einer zunehmenden Anfeuchtung der Schneedecke. Dies vor allem an steilen Ost-, Süd- und Westhängen unterhalb von rund 2700 m sowie an Nordhängen unterhalb von rund 2400 m.

Unterhalb von rund 2200 m liegt an Südhängen kein Schnee.

Die Schneedecke ist gut verfestigt, mit einer Schmelzharschkruste an der Oberfläche, besonders an Schattenhängen oberhalb von rund 1800 m sowie an allen Expositionen unterhalb von rund 2300 m.

Tendenz

Es ist mild.
Nach klarer Nacht allgemein günstige Verhältnisse, dann steigt die Gefahr von Nass- und Gleitschneelawinen an.