Mittwoch 15.04.2026

Veröffentlicht am 14.04.2026 um 17:00

Vormittag

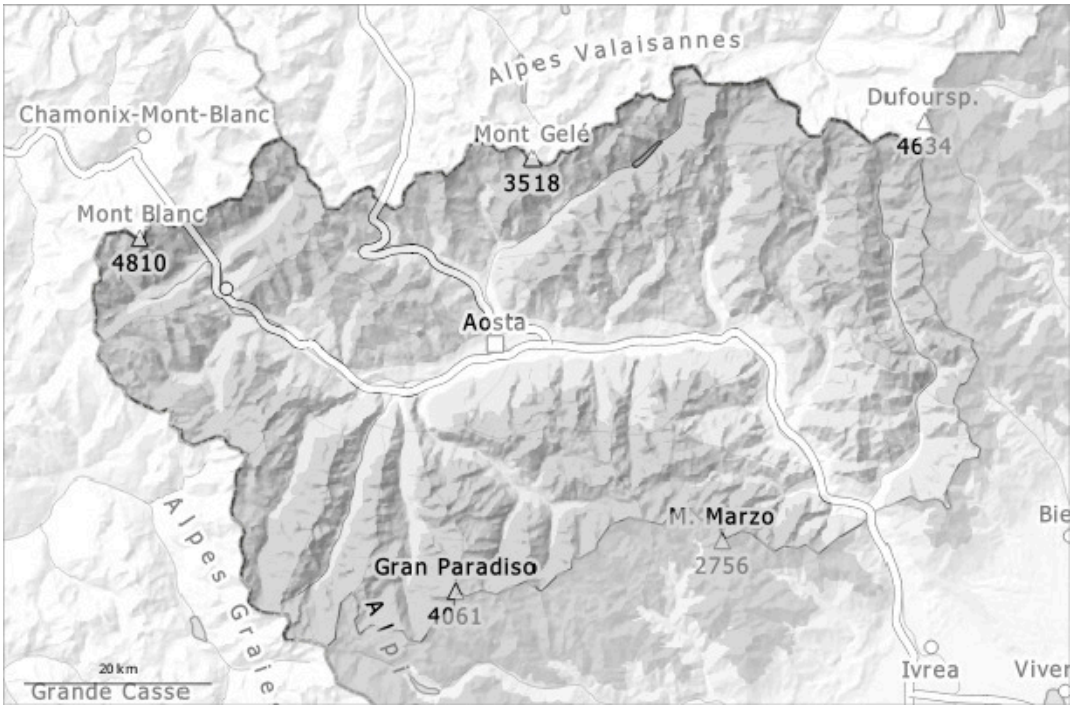

Nachmittag

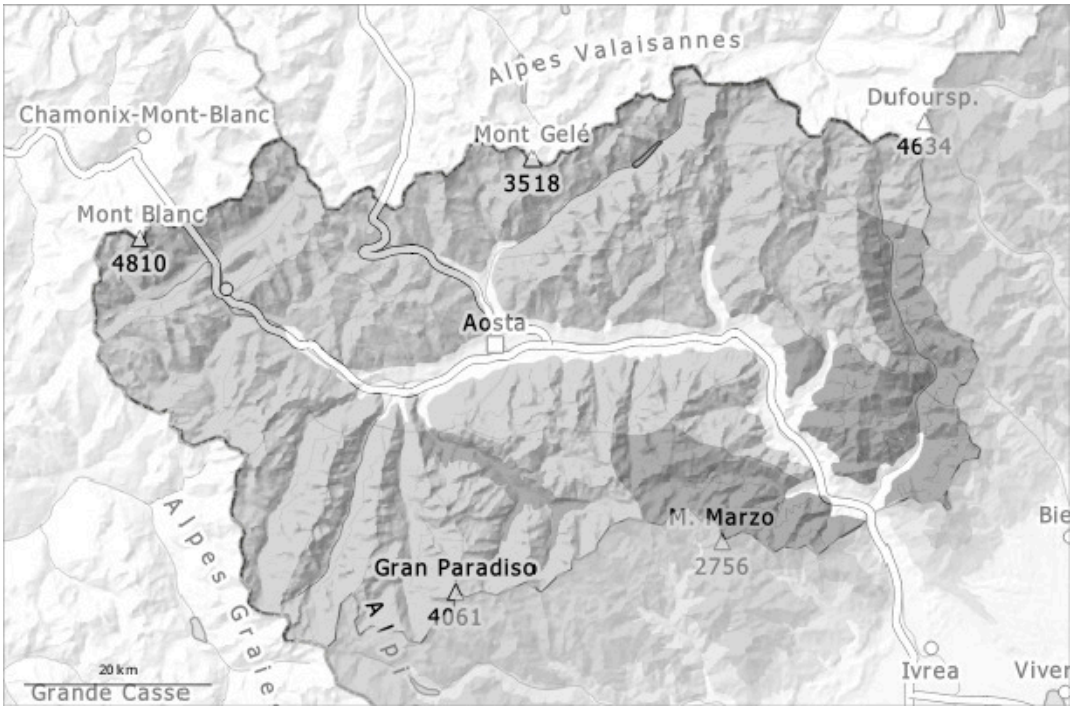

1	2	3	4	5
gering	mäßig	erheblich	groß	sehr groß

Gefahrenstufe 3 - Erheblich

AM:

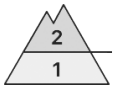

2600m

Tendenz: Lawinengefahr nimmt ab
am Donnerstag, den 16.04.2026

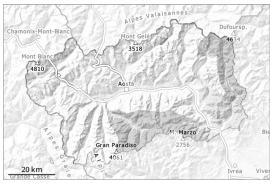

Triebschnee

2600m

Nassschnee

2500m

PM:

2800m

Tendenz: Lawinengefahr nimmt ab
am Donnerstag, den 16.04.2026

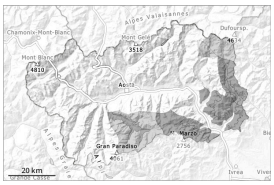

Nassschnee

2800m

Neuschnee

2600m

Die Gefahr von feuchten und nassen Lawinen steigt im Tagesverlauf an.

Für Skitouren sind die Verhältnisse mehrheitlich günstig. Die Schneeoberfläche gefriert tragfähig und weicht im Tagesverlauf auf.
Lokal kann es in der Nacht bewölkt sein; in diesem Fall wird die Lawinengefahr bereits am Morgen auf 2 – mäßig steigen, da Die Schneeoberfläche gefriert nur knapp und ist schon am Morgen aufgeweicht. Dann werden die Bedingungen im Mittelgebirge bereits teilweise ungünstig sein.
Die spontane Aktivität von feuchten und nassen Lawinen nimmt am Vormittag allmählich zu. In tiefen und mittleren Lagen und an sehr steilen Hängen sind kleine und mittlere feuchte Rutsche und Lawinen zu erwarten.

Mit Neuschnee und teils mäßigem Südostwind entstanden teils störanfällige Triebschneeansammlungen. Sie entstanden in hohen Lagen und im Hochgebirge.

Schneedecke

Gefahrenmuster gm.10: frühjahrssituation

Kälter als erwartet: Die Schneeoberfläche ist tragfähig gefroren. Seit Sonntag fielen oberhalb von rund 2300 m 20 bis 40 cm Schnee, lokal auch mehr. Neu- und Triebschnee liegen auf einer nassen

Altschneedecke.
In höheren Lagen nimmt die Schneedecke ab und wird ungleichmäßig; in mittleren Höhenlagen, die weniger vom Wind betroffen sind, ist sie besser. Unterhalb von rund 1900 m liegt kaum Schnee.
In der Schneedecke sind v.a. an steilen Schattenhängen Schwachschichten vorhanden.

Tendenz

Mit der tageszeitlichen Erwärmung und der Sonneneinstrahlung sind weiterhin feuchte und nasse Lawinen möglich. Sonne und Wärme führen zu einer Setzung der Schneedecke. Touren und Hüttenaufstiege sollten rechtzeitig beendet werden.

Gefahrenstufe 2 - Mäßig

AM:

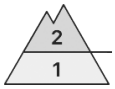

2600m

Tendenz: Lawinengefahr nimmt ab
am Donnerstag, den 16.04.2026

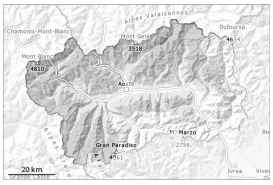

Neuschnee

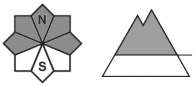

2600m

Nassschnee

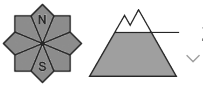

2500m

PM:

Tendenz: Lawinengefahr nimmt ab
am Donnerstag, den 16.04.2026

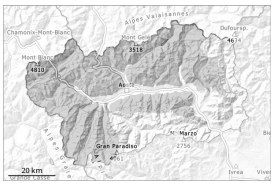

Nassschnee

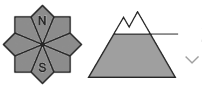

2800m

Neuschnee

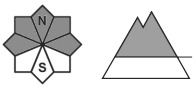

2600m

Die Gefahr von feuchten und nassen Lawinen steigt im Tagesverlauf an.

Die Schneeoberfläche gefriert tragfähig und weicht im Tagesverlauf auf.
Lokal kann es in der Nacht bewölkt sein; in diesem Fall wird die Lawinengefahr bereits am Morgen auf 2 – mäßig steigen, da Die Schneeoberfläche gefriert nur knapp und ist schon am Morgen aufgeweicht. Dann werden die Bedingungen im Mittelgebirge bereits teilweise ungünstig sein.
Die spontane Aktivität von feuchten und nassen Lawinen nimmt am Vormittag allmählich zu. In tiefen und mittleren Lagen und an sehr steilen Hängen sind kleine und vereinzelt mittlere feuchte Rutsche und Lawinen zu erwarten.
Für Touren und Variantenabfahrten sind die Verhältnisse meist günstig.
Mit Neuschnee und teils mäßigem Südostwind entstanden teils störanfällige Triebschneeansammlungen. Sie entstanden in hohen Lagen und im Hochgebirge. Für Skitouren sind die Verhältnisse mehrheitlich günstig.

Schneedecke

Gefahrenmuster gm.10: frühjahrssituation

Kälter als erwartet: Die Schneeoberfläche ist tragfähig gefroren. Neu- und Triebschnee liegen auf einer nassen Altschneedecke.

In höheren Lagen nimmt die Schneedecke ab und wird ungleichmäßig; in mittleren Höhenlagen, die weniger vom Wind betroffen sind, ist sie besser. Unterhalb von rund 1900 m liegt kaum Schnee.
In der Schneedecke sind v.a. an steilen Schattenhängen Schwachschichten vorhanden.

Tendenz

Mit der tageszeitlichen Erwärmung und der Sonneneinstrahlung sind weiterhin feuchte und nasse Lawinen möglich. Sonne und Wärme führen zu einer Setzung der Schneedecke. Touren und Hüttenaufstiege sollten rechtzeitig beendet werden.