Mittwoch 15.04.2026

Veröffentlicht am 14.04.2026 um 17:00

Vormittag

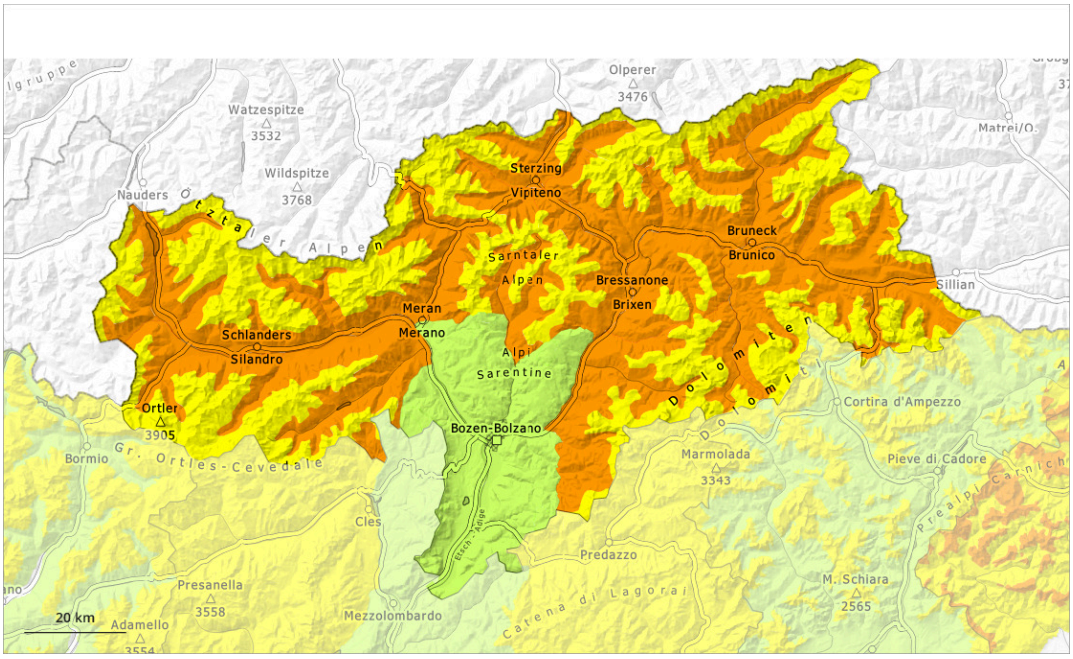

Nachmittag

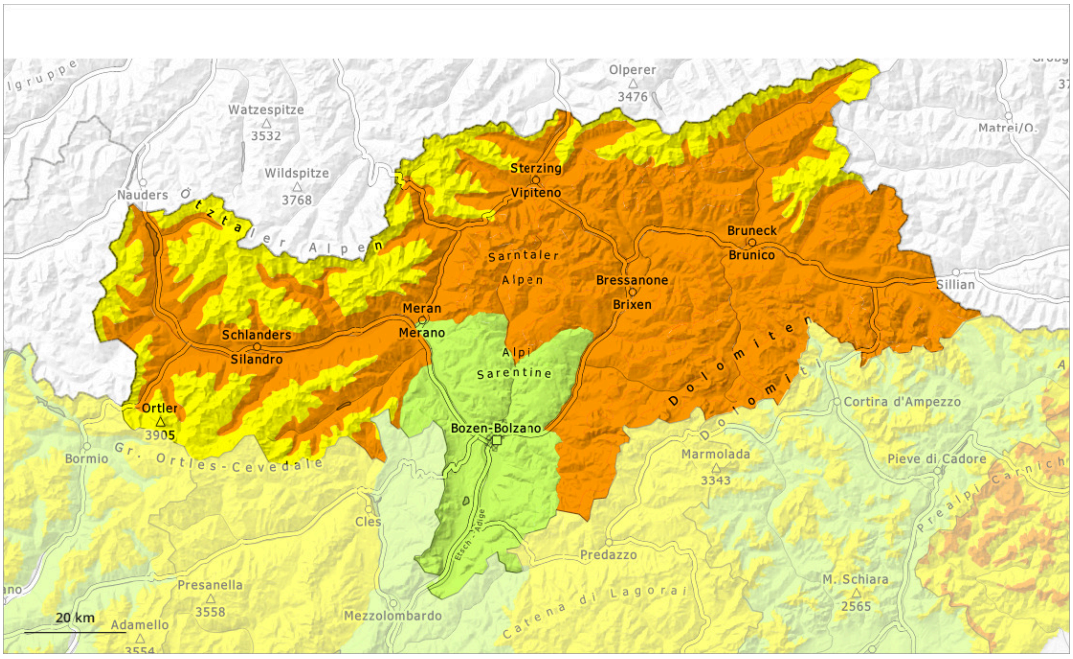

1	2	3	4	5
gering	mäßig	erheblich	groß	sehr groß

Gefahrenstufe 3 - Erheblich

AM:

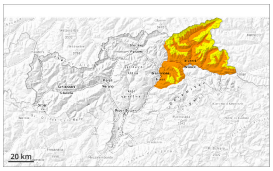

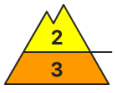

Tendenz: Lawinengefahr bleibt gleich
am Donnerstag, den 16.04.2026

Nassschnee

Altschnee

PM:

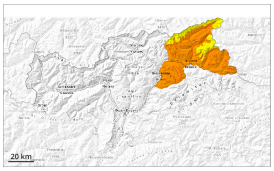

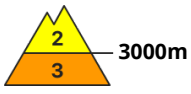

Tendenz: Lawinengefahr bleibt gleich
am Donnerstag, den 16.04.2026

Nassschnee

Altschnee

Die Gefahr von feuchten und nassen Lawinen besteht schon am Morgen. Anstieg der Gefahr im Tagesverlauf.

Feuchte und nasse Lawinen können durch Personen ausgelöst werden, besonders an sehr steilen West-, Nord- und Osthängen unterhalb von rund 2500 m. Mit der tageszeitlichen Erwärmung und der Sonneneinstrahlung steigt die Gefahr von nassen Lawinen im Tagesverlauf etwas an. Es sind einzelne spontane Lawinen möglich. Lawinen können besonders an steilen Schattenhängen im schwachen Altschnee anreißen und vereinzelt groß werden.

Einzelne Gefahrenstellen für trockene Lawinen liegen an sehr steilen Schattenhängen oberhalb von rund 2500 m. Solche Gefahrenstellen sind schwer zu erkennen. Ungünstig sind besonders Übergänge von wenig zu viel Schnee.

Schneedecke

Gefahrenmuster gm.10: frühjahrssituation | gm.1: bodennahe schwachschicht

Die Schneeoberfläche kühlt in der bedeckten Nacht kaum ab. Sonne und Wärme führen im Tagesverlauf unterhalb von rund 3000 m zu einer zunehmenden Durchnässung der Schneedecke. Die hohe Luftfeuchtigkeit führt am Nachmittag auch an steilen Schattenhängen zu einem Festigkeitsverlust

innerhalb der Schneedecke.
Steile West-, Nord- und Osthänge oberhalb von rund 2500 m: Im unteren Teil der Altschneedecke sind kantig aufgebaute Schwachschichten vorhanden.

Tendenz

Die Tourenverhältnisse bleiben frühlingshaft. Die Schneeoberfläche gefriert nur knapp und weicht rasch auf. Mit der tageszeitlichen Erwärmung und der Sonneneinstrahlung steigt die Gefahr von nassen Lawinen im Tagesverlauf an.

Gefahrenstufe 3 - Erheblich

AM:

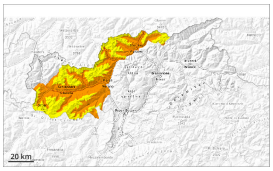

2500m

Tendenz: Lawinengefahr bleibt gleich
am Donnerstag, den 16.04.2026

Nassschnee

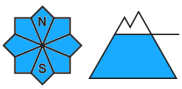

2500m

Triebschnee

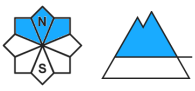

2800m

Altschnee

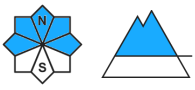

2500m

PM:

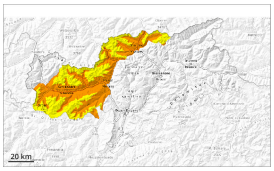

3000m

Tendenz: Lawinengefahr bleibt gleich
am Donnerstag, den 16.04.2026

Nassschnee

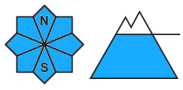

3000m

Triebschnee

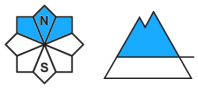

3000m

Altschnee

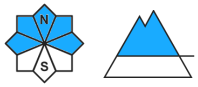

2500m

Anstieg der Gefahr von nassen Lawinen mit der tageszeitlichen Erwärmung und der Sonneneinstrahlung. Triebschnee im Hochgebirge.

Mit der tageszeitlichen Erwärmung und der Sonneneinstrahlung steigt die Gefahr von nassen Lawinen am Morgen rasch an. Lawinen können stellenweise von einzelnen Wintersportlern ausgelöst werden. An sehr steilen Sonnenhängen sind mit der Anfeuchtung kleine und mittlere feuchte Lockerschneelawinen zu erwarten. Lawinen können die durchnässte Schneedecke mitreißen und vereinzelt groß werden, besonders in den Gebieten mit viel Neuschnee.

Es sind am Nachmittag nasse Schneebrettlawinen zu erwarten, v.a. an steilen Schattenhängen zwischen etwa 2200 und 2600 m. Lawinen können besonders dort im schwachen Altschnee anreißen und teils groß werden. Dies vereinzelt auch im häufig befahrenen Variantengelände. Die Lawinen können in steilen

Rinnen bis ins Grüne vorstoßen.

Die frischen Triebschneeansammlungen können teilweise von einzelnen Wintersportlern ausgelöst werden, v.a. in Kammlagen, Rinnen und Mulden im Hochgebirge. Lawinen können sehr vereinzelt in tiefe Schichten durchreißen und groß werden.

Schneedecke

Gefahrenmuster gm.10: frühjahrssituation gm.1: bodennahe schwachschicht

Die Schneeoberfläche kühlt in der bedeckten Nacht kaum ab. Sonne und Wärme führen im Tagesverlauf unterhalb von rund 3000 m zu einer zunehmenden Durchnässung der Schneedecke. Die hohe Luftfeuchtigkeit führt am Nachmittag auch an steilen Schattenhängen zu einem Festigkeitsverlust innerhalb der Schneedecke.
West-, Nord- und Osthänge oberhalb von rund 2200 m: Der untere Teil der Schneedecke ist aufbauend umgewandelt.
Seit Montag fielen oberhalb von rund 2500 m 10 bis 20 cm Schnee, lokal auch mehr. Im Hochgebirge entstanden meist kleine Triebschneeansammlungen.

Tendenz

Die Tourenverhältnisse bleiben frühlingshaft. Die Schneeoberfläche gefriert nur knapp und weicht rasch auf. Mit der tageszeitlichen Erwärmung und der Sonneneinstrahlung steigt die Gefahr von nassen Lawinen im Tagesverlauf an.

Gefahrenstufe 3 - Erheblich

AM:

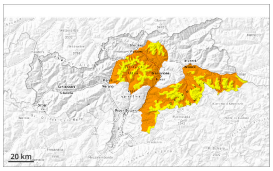

2500m

Tendenz: Lawinengefahr bleibt gleich
am Donnerstag, den 16.04.2026

Nassschnee

Altschnee

PM:

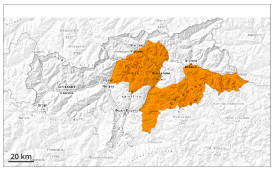

3000m

Tendenz: Lawinengefahr bleibt gleich
am Donnerstag, den 16.04.2026

Nassschnee

Altschnee

Die Gefahr von feuchten und nassen Lawinen besteht schon am Morgen. Anstieg der Gefahr im Tagesverlauf.

Feuchte und nasse Lawinen können durch Personen ausgelöst werden, besonders an sehr steilen West-, Nord- und Osthängen unterhalb von rund 2500 m. Mit der tageszeitlichen Erwärmung und der Sonneneinstrahlung steigt die Gefahr von nassen Lawinen im Tagesverlauf etwas an. Es sind einzelne spontane Lawinen möglich. Lawinen können besonders an steilen Schattenhängen im schwachen Altschnee anreißen und vereinzelt groß werden.

Einzelne Gefahrenstellen für trockene Lawinen liegen an sehr steilen Schattenhängen oberhalb von rund 2500 m. Solche Gefahrenstellen sind schwer zu erkennen. Ungünstig sind besonders Übergänge von wenig zu viel Schnee.
Zudem sind die frischen Triebschneeansammlungen teils störanfällig, besonders an steilen Schattenhängen in den Gebieten mit viel Neuschnee. An extrem steilen Sonnenhängen sind mit der tageszeitlichen Erwärmung und der Sonneneinstrahlung kleine und vereinzelt mittlere feuchte Lockerschneelawinen möglich, besonders in den Gebieten mit viel Neuschnee.

Schneedecke

Gefahrenmuster gm.10: frühjahrssituation gm.1: bodennahe schwachschicht

Die Schneeoberfläche kühlt in der bedeckten Nacht kaum ab. Sonne und Wärme führen im Tagesverlauf unterhalb von rund 3000 m zu einer zunehmenden Durchnässung der Schneedecke. Die hohe Luftfeuchtigkeit führt am Nachmittag auch an steilen Schattenhängen zu einem Festigkeitsverlust innerhalb der Schneedecke.
Steile West-, Nord- und Osthänge oberhalb von rund 2500 m: Im unteren Teil der Altschneedecke sind kantig aufgebaute Schwachschichten vorhanden.

Tendenz

Die Tourenverhältnisse bleiben frühlingshaft. Die Schneeoberfläche gefriert nur knapp und weicht rasch auf. Mit der tageszeitlichen Erwärmung und der Sonneneinstrahlung steigt die Gefahr von nassen Lawinen im Tagesverlauf an.

Gefahrenstufe 3 - Erheblich

AM:

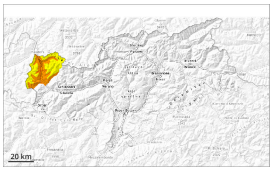

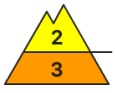

Tendenz: Lawinengefahr bleibt gleich
am Donnerstag, den 16.04.2026

Nassschnee

Altschnee

PM:

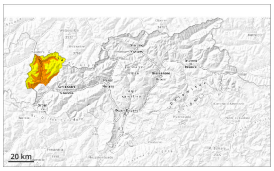

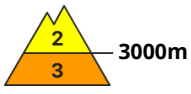

Tendenz: Lawinengefahr bleibt gleich
am Donnerstag, den 16.04.2026

Nassschnee

Altschnee

Die Gefahr von feuchten und nassen Lawinen besteht schon am Morgen. Anstieg der Gefahr im Tagesverlauf.

Mit der tageszeitlichen Erwärmung und der Sonneneinstrahlung steigt die Gefahr von nassen Lawinen am Morgen rasch an. Feuchte und nasse Lawinen können stellenweise von einzelnen Wintersportlern ausgelöst werden. Es sind einzelne meist kleine Lockerschneelawinen zu erwarten. Vorsicht vor allem an sehr steilen Hängen unterhalb von rund 2500 m sowie an sehr steilen Sonnenhängen in der Höhe.
Mit der Durchnässung nimmt die Anzahl der Gefahrenstellen im Tagesverlauf zu. Es sind am Nachmittag vermehrt nasse Schneebrettlawinen zu erwarten. Vorsicht vor allem an steilen Schattenhängen zwischen etwa 2200 und 2600 m. Nasse Lawinen können besonders dort im schwachen Altschnee anreißen und groß werden. Dies vereinzelt auch im häufig befahrenen Variantengelände. Die Lawinen können in steilen Rinnen bis ins Grüne vorstoßen.

Einzelne Gefahrenstellen für trockene Lawinen liegen an sehr steilen Schattenhängen oberhalb von rund 2500 m. Solche Gefahrenstellen sind schwer zu erkennen. Ungünstig sind besonders Übergänge von wenig zu viel Schnee. Die kleinen Triebschneeansammlungen sollten an kammnahen Schattenhängen im Hochgebirge vorsichtig beurteilt werden.

Schneedecke

Gefahrenmuster gm.10: frühjahrssituation gm.1: bodennahe schwachschicht

Die Schneeoberfläche kühlt in der bedeckten Nacht kaum ab. Damit gefriert die Schneedecke nur knapp. Sonne und Wärme führen im Tagesverlauf unterhalb von rund 3000 m zu einer zunehmenden Durchnässung der Schneedecke. Die hohe Luftfeuchtigkeit führt am Nachmittag auch an steilen Schattenhängen zu einem Festigkeitsverlust innerhalb der Schneedecke.
West-, Nord- und Osthänge oberhalb von rund 2200 m: Der untere Teil der Schneedecke ist aufbauend umgewandelt.

Tendenz

Die Tourenverhältnisse bleiben frühlingshaft. Die Schneeoberfläche gefriert nur knapp und weicht rasch auf. Mit der tageszeitlichen Erwärmung und der Sonneneinstrahlung steigt die Gefahr von nassen Lawinen im Tagesverlauf deutlich an. Spontane nasse Lawinen sind weiterhin zu erwarten.

Gefahrenstufe 1 - Gering

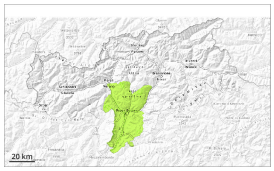

1

Tendenz: Lawinengefahr bleibt gleich
am Donnerstag, den 16.04.2026

Nassschnee

2000m

Nassschnee beachten.

Es sind nur noch vereinzelt nasse Lawinen möglich. Vorsicht an extrem steilen Schattenhängen. Lawinen sind sehr vereinzelt mittelgroß.

Schneedecke

Gefahrenmuster gm.10: frühjahrssituation | gm.1: bodennahe schwachschicht

Die Schneeoberfläche gefriert kaum und ist schon am Morgen aufgeweicht.

Tendenz

Geringe Lawinengefahr.