Mercoledì 15.04.2026

Pubblicato il 14.04.2026 alle ore 17:00

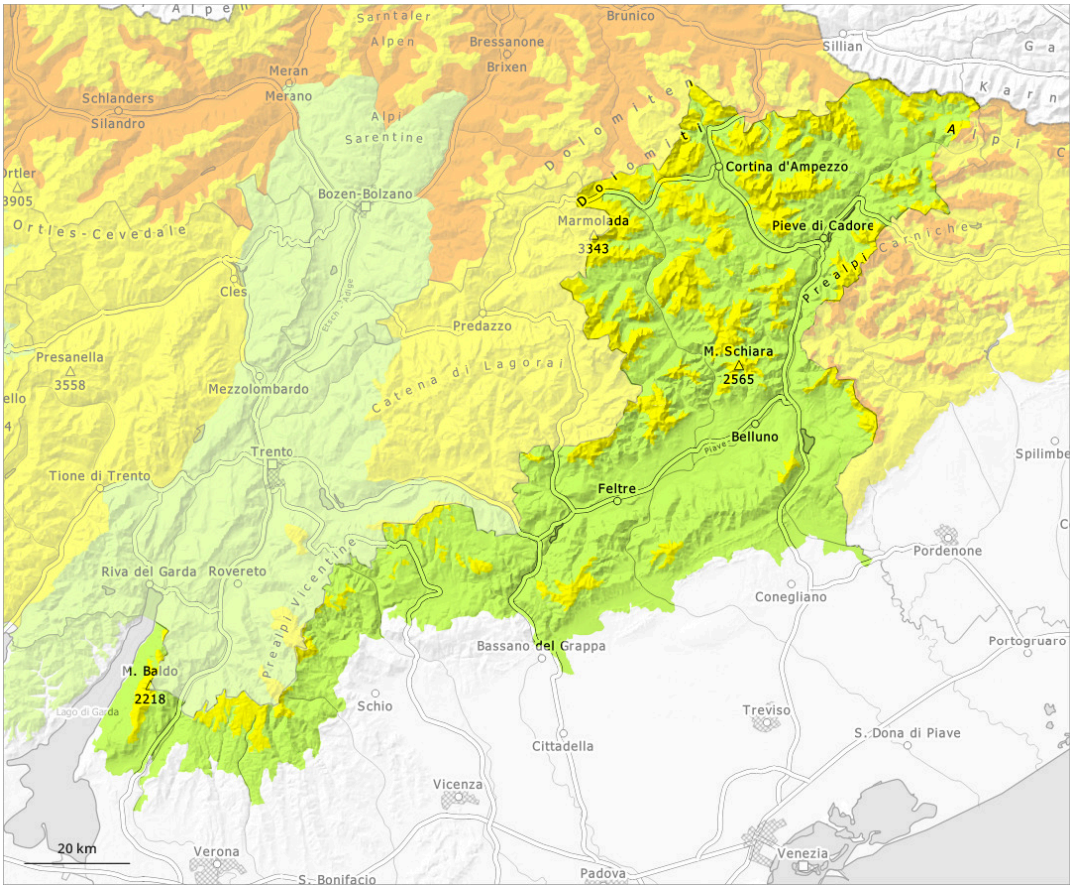

1	2	3	4	5
debole	moderato	marcato	forte	molto forte

Grado di pericolo 2 - Moderato

Limite del bosco

Tendenza: pericolo valanghe stabile
per Giovedì il 16.04.2026

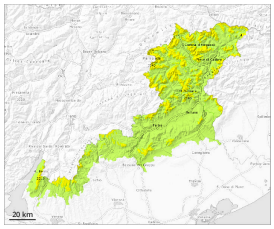

Neve bagnata

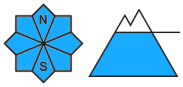

Limite del bosco

Neve bagnata

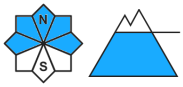

2500m

Lastrone da vento

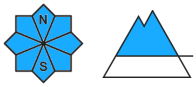

2500m

Strati deboli persistenti

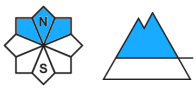

2000m

Neve bagnata e neve slittante sono la principale fonte di pericolo.

A livello locale sono caduti sino a 20 cm di neve al di sopra dei 2600 m circa, localmente anche meno. A livello locale, è caduta pioggia sino ai 2300 m.
I punti pericolosi sono frequenti e con il cattivo tempo appena individuabili. I punti pericolosi per valanghe bagnate si trovano specialmente sulle scarpate al di sotto dei 2500 m circa. Soprattutto dai bacini di alimentazione non ancora completamente scaricati le valanghe bagnate possono raggiungere dimensioni grandi. La neve fresca dovrebbe essere valutata con attenzione a tutte le esposizioni al di sopra dei 2500 m circa. Soprattutto sui pendii molto ripidi e ai piedi di pareti rocciose e dietro ai cambi di pendenza sono possibili valanghe di piccole e, a livello isolato, di medie dimensioni. Particolarmente pericolosi sono i punti alla base di pareti rocciose, (--).
Con neve fresca e vento forte proveniente da sud est principalmente al di sopra dei 2500 m circa si sono formati estesi accumuli di neve ventata. I punti pericolosi si trovano soprattutto nei punti in prossimità delle creste, nelle conche e nei canaloni esposti da nord ovest a nord sino a nord est al di sopra dei 2500 m circa. Particolarmente pericolosi sono i punti di passaggio da poca a molta neve, dove nel manto di neve vecchia sono presenti strati deboli. Le valanghe possono coinvolgere il manto di neve vecchia e raggiungere dimensioni medie.
In alcune regioni aumento del pericolo di valanghe umide e bagnate.

Manto nevoso

Situazione tipo st.3: pioggia su neve st.1: strato debole persistente basale

Sui pendii esposti a nord ovest, nord e nord est, all'interno del manto nevoso si trovano insidiosi strati fragili.
La pioggia mista a neve ha causato soprattutto sui pendii ripidi al di sotto dei 2200 m circa diffusamente una destabilizzazione all'interno del manto nevoso.