ICGC Institut Cartogràfic i Geològic de Catalunya

Servei Meteorològic de Catalunya meteo.cat

Boletín de peligro de aludes para el Pirineo de Catalunya
Del 14/04/2026 al 15/04/2026

(Válido fuera pistas de esquí y zonas no controladas)

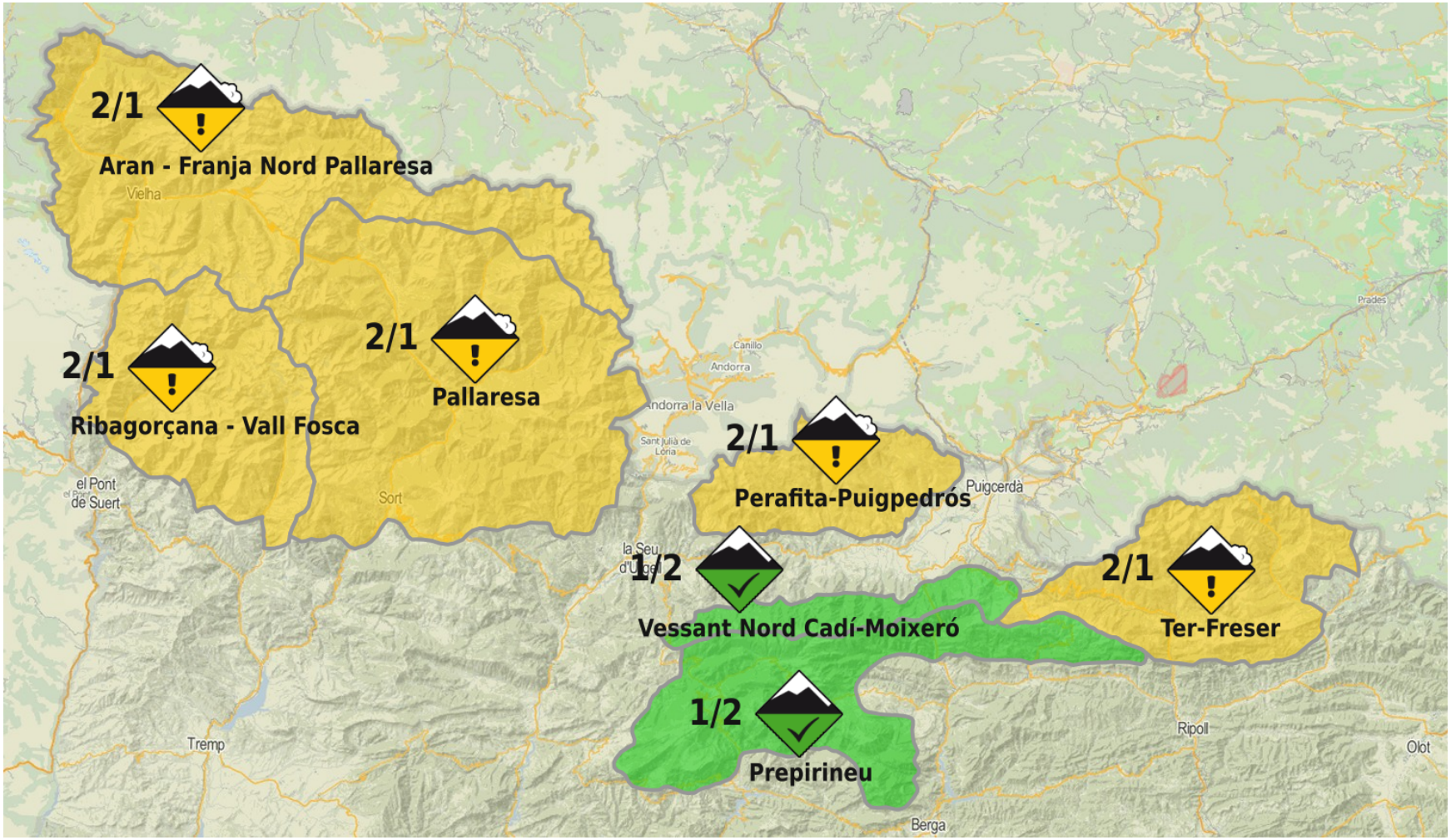

5 MUY FUERTE	4 FUERTE	3 NOTABLE	2 LIMITADO	1 DÉBIL

ICGC Institut Cartogràfic i Geològic de Catalunya

Servei Meteorològic de Catalunya

Boletín de peligro de aludes Aran - Franja Nord Pallaresa Del 14/04/2026 al 15/04/2026

(Válido fuera pistas de esquí y zonas no controladas)

LIMITADO (2) por encima de 2.200 m. DÉBIL (1).

Situación primaria

Nieve venteada

Distribución

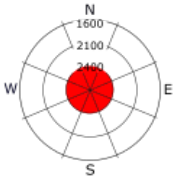

Tamaño

Origen

Tendencia

Situación secundaria

Nieve húmeda

Distribución

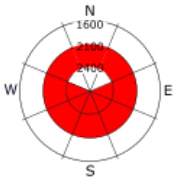

Tamaño

Origen

Tendencia

Estado del manto nivoso

La retención de norte ha dejado en la madrugada del martes unos 5-8 cm de nieve seca y fría. Se añaden a los 10-15 cm del fin de semana por encima de 2.200 a 2.300 m. El martes ha aumentado el viento de N y se están formando nuevas placas de viento en cotas altas. Se esperan algunos aludes de placa de tamaño 1 (pequeño), localmente de hasta tamaño 2 (mediano, suficiente para cubrir a una persona) por encima de 2.200 m en cualquier orientación, sobre todo en la Franja Norte de la Pallaresa. Internamente el manto se está endureciendo por rehielo. En las horas centrales del día pueden caer aludes de fusión junto a sectores rocosos soleados, por lo general de tamaño 2 (mediano). El miércoles por la mañana encontraremos un manto rehelado, aún con algo de nieve seca en superficie en las cotas más altas umbrías, con tendencia a irse humedeciendo por el fuerte aumento de las temperaturas. Recuerde llevar material para evitar resbalones (crampones, piolet, casco).

Distribución del manto nivoso

Hay nieve en el suelo con continuidad por encima de 1.800-1.900 m en umbrías y de 2.000 m en solanas. Los espesores a unos 2.200 m rondan los 140-220 cm. Los valores están muy por encima de los normales por la época.

Tendencia para las próximas 48-72h

El manto se irá humedeciendo progresivamente, tanto por el aumento de temperaturas como el crecimiento de nubes de tarde con alguna niebla en las cimas. Por la mañana la estabilidad será alta por rehielo nocturno. Evolución del peligro: SIN CAMBIOS.

El próximo boletín será emitido el día 2026-04-15

5 MUY FUERTE	4 FUERTE	3 NOTABLE	2 LIMITADO	1 DÉBIL

EAWS EUROPEAN AVALANCHE WARNING SERVICES

ICGC Institut Cartogràfic i Geològic de Catalunya

Servei Meteorològic de Catalunya meteo.cat

Boletín de peligro de aludes Ribagorçana - Vall Fosca Del 14/04/2026 al 15/04/2026

(Válido fuera pistas de esquí y zonas no controladas)

LIMITADO (2) por encima de 2.200 m. DÉBIL (1).

Situación primaria

Nieve venteada

Distribución

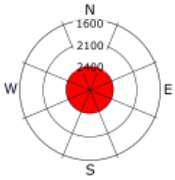

Tamaño

Origen

Tendencia

Situación secundaria

Nieve húmeda

Distribución

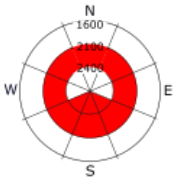

Tamaño

Origen

Tendencia

Estado del manto nivoso

La última nevada es del fin de semana; dejó un grosor de unos 10-15 cm por encima de 2.200-2.300 m. El martes ha aumentado el viento de N y se están formando nuevas placas de viento en cotas altas. Se espera algún alud de placa de hasta tamaño 2 (mediano, suficiente para cubrir a una persona) por encima de 2.200 m en cualquier orientación. Internamente el manto se está endureciendo por rehielo. En las horas centrales del día puede caer algún alud de fusión junto a sectores rocosos soleados, por lo general de tamaño 1 (pequeño). El miércoles por la mañana encontraremos un manto rehelado, aún con algo de nieve seca en superficie en las cotas más altas umbrías, con tendencia a irse humedeciendo por el fuerte aumento de las temperaturas. Recuerde llevar material para evitar resbalones (crampones, piolet, casco).

Distribución del manto nivoso

Hay nieve por encima de 1.800-2.000 m pero esquiable en N por encima de 1.900 my de 2.300 m en S. Prácticamente no han variado los grosores de nieve en el suelo. Alcanzan los 80-100 cm a unos 2.200 m, con frecuentes deflaciones y acumulaciones por encima del nivel del bosque. Estos valores están algo por debajo de los normales para la época.

Tendencia para las próximas 48-72h

El manto se irá humedeciendo progresivamente, tanto por el aumento de temperaturas como el crecimiento de nubes de tarde con alguna niebla en las cimas. Por la mañana la estabilidad será alta por rehielo nocturno. Evolución del peligro: SIN CAMBIOS.

El próximo boletín será emitido el día 2026-04-15

5 MUY FUERTE	4 FUERTE	3 NOTABLE	2 LIMITADO	1 DÉBIL

EAWS EUROPEAN AVALANCHE WARNING SERVICES

ICGC Institut Cartogràfic i Geològic de Catalunya

Servei Meteorològic de Catalunya

Boletín de peligro de aludes Pallaresa
Del 14/04/2026 al 15/04/2026

(Válido fuera pistas de esquí y zonas no controladas)

LIMITADO (2) por encima de 2.200 m. DÉBIL (1).

Situación primaria

Nieve venteada

Distribución

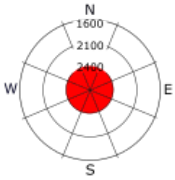

Tamaño

Origen

Tendencia

Situación secundaria

Nieve húmeda

Distribución

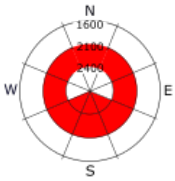

Tamaño

Origen

Tendencia

Estado del manto nivoso

La última nevada es del fin de semana; dejó un grosor de unos 10-15 cm por encima de 2.200-2.300 m. El martes ha aumentado el viento de N y se están formando nuevas placas de viento en cotas altas. Se espera algún alud de placa de hasta tamaño 2 (mediano, suficiente para cubrir a una persona) por encima de 2.200 m en cualquier orientación. Internamente el manto se está endureciendo por rehielo. En las horas centrales del día puede caer algún alud de fusión junto a sectores rocosos soleados, por lo general de tamaño 1 (pequeño). El miércoles por la mañana encontraremos un manto rehelado, aún con algo de nieve seca en superficie en las cotas más altas umbrías, con tendencia a irse humedeciendo por el fuerte aumento de las temperaturas. Recuerde llevar material para evitar resbalones (crampones, piolet, casco).

Distribución del manto nivoso

Hay nieve por encima de 1.800-2.000 m pero esquiable en N por encima de 1.900 my de 2.300 m en S. Prácticamente no han variado los grosores de nieve en el suelo. Alcanzan los 80-100 cm a unos 2.200 m, con frecuentes deflaciones y acumulaciones por encima del nivel del bosque.

Tendencia para las próximas 48-72h

El manto se irá humedeciendo progresivamente, tanto por el aumento de temperaturas como el crecimiento de nubes de tarde con alguna niebla en las cimas. Por la mañana la estabilidad será alta por rehielo nocturno. Evolución del peligro: SIN CAMBIOS.

El próximo boletín será emitido el día 2026-04-15

5 MUY FUERTE	4 FUERTE	3 NOTABLE	2 LIMITADO	1 DÉBIL

EAWS EUROPEAN AVALANCHE WARNING SERVICES

ICGC Institut Cartogràfic i Geològic de Catalunya

meteo.cat Servei Meteorològic de Catalunya

Boletín de peligro de aludes Perafita-Puigpedrós Del 14/04/2026 al 15/04/2026

(Válido fuera pistas de esquí y zonas no controladas)

LIMITADO (2) por encima de 2.400 m. DÉBIL (1).

Situación primaria

Nieve venteada

Distribución

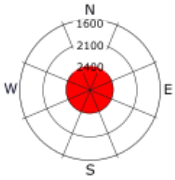

Tamaño

Origen

Tendencia

Situación secundaria

Nieve húmeda

Distribución

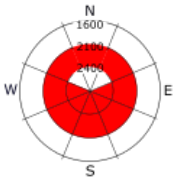

Tamaño

Origen

Tendencia

Estado del manto nivoso

La última nevada es del fin de semana; dejó un grosor de unos 10 cm por encima de 2.200-2.300 m. El martes ha aumentado el viento de N y se están formando nuevas placas de viento en cotas altas. Se espera algún alud de placa de hasta tamaño 1 (pequeña, suficiente para arrastrarnos) por encima de 2.400 m en cualquier orientación. Internamente el manto se está endureciendo por rehielo. En las horas centrales del día puede caer algún alud de fusión junto a sectores rocosos soleados, por lo general de tamaño 1 (pequeño). El miércoles por la mañana encontraremos un manto rehelado, aún con algo de nieve seca en superficie en las cotas más altas umbrías, con tendencia a irse humedeciendo por el fuerte aumento de las temperaturas. Recuerde llevar material para evitar resbalones (crampones, piolet, casco).

Distribución del manto nivoso

Hay nieve por encima de 1.800 a 2.000 m. Prácticamente no han variado los grosores de nieve en el suelo. Alcanzan los 50-90 cm a unos 2.300 m, con frecuentes deflaciones y acumulaciones por encima del nivel del bosque. Estos valores son los normales para la época.

Tendencia para las próximas 48-72h

El manto se irá humedeciendo progresivamente, tanto por el aumento de temperaturas como el crecimiento de nubes de tarde con alguna niebla en las cimas. Por la mañana la estabilidad será alta por rehielo nocturno. Evolución del peligro: SIN CAMBIOS.

El próximo boletín será emitido el día 2026-04-15

5 MUY FUERTE	4 FUERTE	3 NOTABLE	2 LIMITADO	1 DÉBIL

EAWS EUROPEAN AVALANCHE WARNING SERVICES

ICGC Institut Cartogràfic i Geològic de Catalunya

Servei Meteorològic de Catalunya

Boletín de peligro de aludes Vessant Nord Cadí-Moixeró Del 14/04/2026 al 15/04/2026

(Válido fuera pistas de esquí y zonas no controladas)

DÉBIL (1) LIMITADO (2) al mediodía y por encima de 2.000 m.

Situación primaria

Nieve húmeda

Distribución

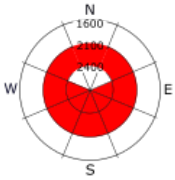

Tamaño

Origen

Tendencia

Situación secundaria

Nieve venteada

Distribución

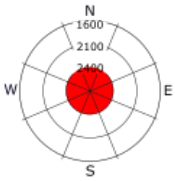

Tamaño

Origen

Tendencia

Estado del manto nivoso

La última nevada es del fin de semana; dejó un grosor de unos 10-15 cm por encima de 2.200-2.300 m. Todavía se espera algún alud de placa de tamaño 1 (pequeña, suficiente para arrastrarnos) en lo alto de las canales, especialmente en orientaciones de NW a NE. Internamente el manto se está endureciendo por rehielo. En las horas centrales del día puede caer algún alud de fusión junto a sectores rocosos soleados, por lo general de tamaño 1 (pequeño). El miércoles por la mañana encontraremos un manto rehelado, aún con algo de nieve seca en superficie en las cotas más altas umbrías, con tendencia a irse humedeciendo por el fuerte aumento de las temperaturas. Recuerde llevar material para evitar resbalones (crampones, piolet, casco).

Distribución del manto nivoso

Hay nieve por encima de 1.800 m en N y de 2.000 m en S. Prácticamente no han variado los grosores de nieve en el suelo. Alcanzan los 130-150 cm a unos 2.200 m, con frecuentes deflaciones y acumulaciones por encima del nivel del bosque. Estos valores están muy por encima de los normales para la época.

Tendencia para las próximas 48-72h

El manto se irá humedeciendo progresivamente, tanto por el aumento de temperaturas como el crecimiento de nubes de tarde con alguna niebla en las cimas. Por la mañana la estabilidad será alta por rehielo nocturno. Evolución del peligro: SIN CAMBIOS.

El próximo boletín será emitido el día 2026-04-15

5 MUY FUERTE	4 FUERTE	3 NOTABLE	2 LIMITADO	1 DÉBIL

EAWS EUROPEAN AVALANCHE WARNING SERVICES

ICGC Institut Cartogràfic i Geològic de Catalunya

Servei Meteorològic de Catalunya

Boletín de peligro de aludes Prepirineu
Del 14/04/2026 al 15/04/2026

(Válido fuera pistas de esquí y zonas no controladas)

DÉBIL (1) LIMITADO (2) al mediodía y por encima de 2.200 m.

Situación primaria

Nieve húmeda

Distribución

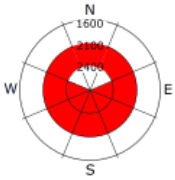

Tamaño

Origen

Tendencia

Situación secundaria

Nieve venteada

Distribución

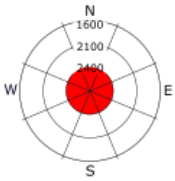

Tamaño

Origen

Tendencia

Estado del manto nivoso

La última nevada es del fin de semana; dejó un grosor de unos 5-10 cm por encima de 2.200-2.300 m. El martes por la mañana todavía se mueve algo de nieve por viento de N. Se espera algún alud de placa de tamaño 1 (pequeña, suficiente para arrastrarnos) por encima de 2.200 m, especialmente en orientaciones de NW a NE. Internamente el manto se está endureciendo por rehielo. En las horas centrales del día puede caer algún alud de fusión junto a sectores rocosos soleados, por lo general de tamaño 1 (pequeño). El miércoles por la mañana encontraremos un manto rehelado, aún con algo de nieve seca en superficie en las cotas más altas umbrías, con tendencia a irse humedeciendo por el fuerte aumento de las temperaturas. Recuerde llevar material para evitar resbalones (crampones, piolet, casco).

Distribución del manto nivoso

Hay nieve por encima de 1.900 m en N y de 2.000-2.100 m en S. Prácticamente no han variado los grosores de nieve en el suelo. Alcanzan los 60-80 cm a unos 2.200 m, con frecuentes deflaciones y acumulaciones por encima del nivel del bosque.

Tendencia para las próximas 48-72h

El manto se irá humedeciendo progresivamente, tanto por el aumento de temperaturas como el crecimiento de nubes de tarde con alguna niebla en las cimas. Por la mañana la estabilidad será alta por rehielo nocturno. Evolución del peligro: SIN CAMBIOS.

El próximo boletín será emitido el día 2026-04-15

5 MUY FUERTE	4 FUERTE	3 NOTABLE	2 LIMITADO	1 DÉBIL

EAWS EUROPEAN AVALANCHE WARNING SERVICES

ICGC Institut Cartogràfic i Geològic de Catalunya

Servei Meteorològic de Catalunya meteo.cat

Boletín de peligro de aludes Ter-Freser
Del 14/04/2026 al 15/04/2026

(Válido fuera pistas de esquí y zonas no controladas)

LIMITADO (2) por encima de 2.200 m. DÉBIL (1).

Situación primaria

Nieve venteada

Distribución

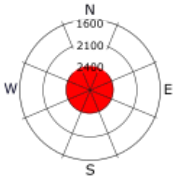

Tamaño

Origen

Tendencia

Situación secundaria

Nieve húmeda

Distribución

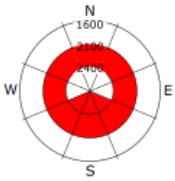

Tamaño

Origen

Tendencia

Estado del manto nivoso

La última nevada es del fin de semana; dejó un grosor de unos 10 cm por encima de 2.200-2.300 m. El martes ha aumentado el viento de N y se están formando nuevas placas de viento en cotas altas. Se espera algún alud de placa de tamaño 1 (pequeña, suficiente para arrastrarnos) por encima de 2.200 m en cualquier orientación. Internamente el manto se está endureciendo por rehielo. En las horas centrales del día puede caer algún alud de fusión junto a sectores rocosos soleados, por lo general de tamaño 1 (pequeño). El miércoles por la mañana encontraremos un manto rehelado, aún con algo de nieve seca en superficie en las cotas más altas umbrías, con tendencia a irse humedeciendo por el fuerte aumento de las temperaturas. Recuerde llevar material para evitar resbalones (crampones, piolet, casco).

Distribución del manto nivoso

Hay nieve por encima de 1.800 m en N y de 1.900 m en S. Prácticamente no han variado los grosores de nieve en el suelo. Alcanzan los 50-80 cm a unos 2.200 m, y más de 130-190 cm por encima de 2.400 m, con frecuentes deflaciones y acumulaciones por encima del nivel del bosque. Estos valores están por encima de la media para la época.

Tendencia para las próximas 48-72h

El manto se irá humedeciendo progresivamente, tanto por el aumento de temperaturas como el crecimiento de nubes de tarde con alguna niebla en las cimas. Por la mañana la estabilidad será alta por rehielo nocturno. Evolución del peligro: SIN CAMBIOS.

El próximo boletín será emitido el día 2026-04-15

5 MUY FUERTE	4 FUERTE	3 NOTABLE	2 LIMITADO	1 DÉBIL

EAWS EUROPEAN AVALANCHE WARNING SERVICES