BUTLLETÍ DEL PERILL D'ALLAUS DEL PRINCIPAT D'ANDORRA

Préparé le 14/04/2026 16:00
Prochaine mise à jour le 15/04/2026 à 16h

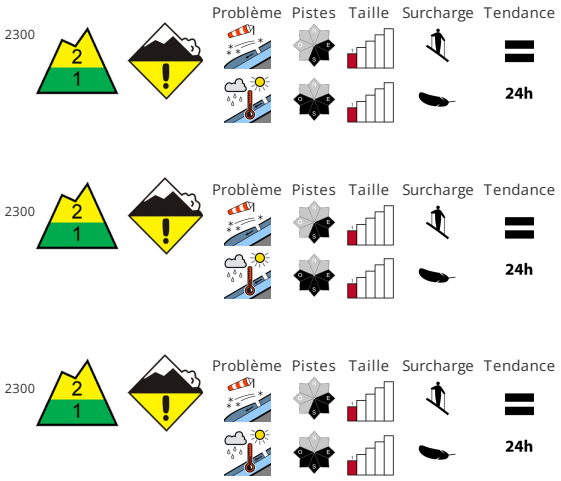

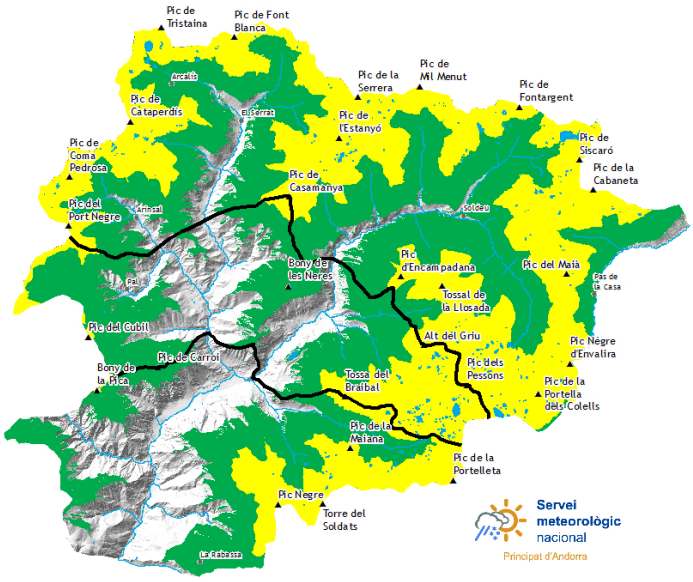

STABILITÉ DU MANTEAU NEIGEUX

Les accumulations de neige soufflée en partie grosses constituent le danger principal. Elles sont en partie épaisses et en partie facilement déclenchables surtout à leur périphérie. Des avalanches et coulées humides sont ils sont à attendre avec le réchauffement diurne et le rayonnement solaire. Les avalanches peuvent se déclencher spontanément et atteindre une taille moyenne.. En outre, des avalanches de glissement isolées sont possibles.. Les endroits dangereux sont facilement identifiables..

QUALITÈ DE LA NEIGE

On trouve suivant l'influence du vent des hauteurs de neiges très différentes. Le rayonnement solaire en cours de journée entraîne sur les pentes au soleil une humidification croissante du manteau neigeux. Les zones présentant des fissures de glissement doivent être évitées.. Sur la croûte glacée il existe également dans des terrains moyennement raides un risque de chute.. Ceci surtout en dessous d'environ 2300 m.

EPAISSEUR DE NEIGE HORS PISTE

Zone nord		Epaisseur de neige		
Nival manteau		1500m	2000m	2500m
N	1600 m	0 cm	150 cm	250 cm
S	1800 m	0 cm	100 cm	180 cm

Zone centre		Epaisseur de neige		
Nival manteau		1500m	2000m	2500m
N	1600 m	0 cm	120 cm	160 cm
S	1800 m	0 cm	60 cm	120 cm

Zone sud		Epaisseur de neige		
Nival manteau		1500m	2000m	2500m
N	1600 m	0 cm	120 cm	160 cm
S	1800 m	0 cm	60 cm	120 cm

Govern d'Andorra

Aquest butlletí ha estat elaborat seguint les normes i recomanacions de l'**European Avalanche Warning Services**, del qual el **Servei meteorològic Nacional** n'és membre

BUTLLETÍ DEL PERILL D'ALLAUS DEL PRINCIPAT D'ANDORRA

Servei meteorològic nacional
Principat d'Andorra

Des informations détaillées par espace naturel protégé

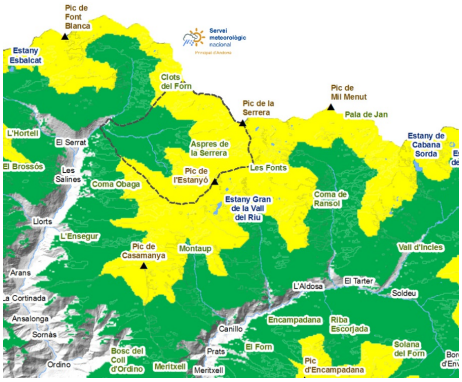

SORTENY

Le soleil humidifie progressivement la neige sur le versant sud, mais il fait encore froid au nord. À basse altitude, le vent a exposé la vieille neige tachée par la boue de la pluie du dimanche matin et elle a gelé. Les ascensions sont techniques à moyenne altitude à cause de la glace. À haute altitude, il est recommandé d'éviter les accumulations de neige venteuses et de rouler sur la neige plus dure et plus brune. , , , , , , ,

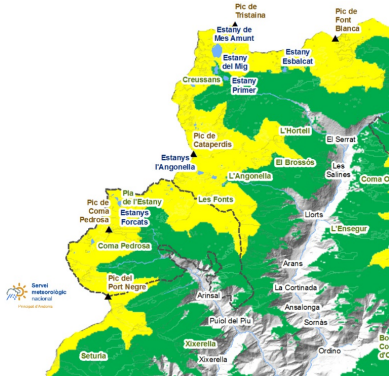

COMAPEDROSA

La neige sera humide sur les versants sud et les basses altitudes, mais le matin nous la trouverons très dure. Des purges de neige mouillée descendront sur les pentes les plus raides. Au petit matin, avec la neige encore dure, il sera plus difficile et technique de parcourir les moyennes altitudes à vélo que les hautes altitudes, où la neige est plus récente. , , , , , ,

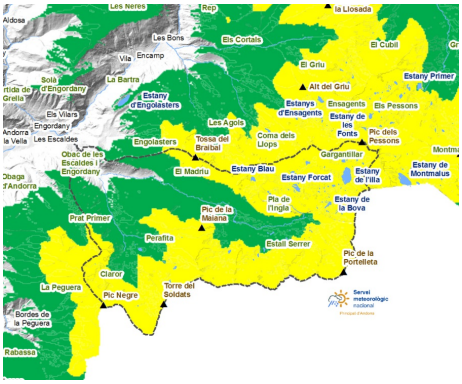

MADRIU-PERAFITA-CLAROR

Le soleil va stabiliser le manteau avec son compactage, mais en journée on s'attend à des purges sur les versants sud. Il sera plus sécuritaire de rouler sur la neige dure et brune pour éviter les plaques de vent. , , ,

Govern d'Andorra

EAWS
EUROPEAN AVALANCHE WARNING SERVICES

Aquest butlletí ha estat elaborat seguint les normes i recomanacions de l'**European Avalanche Warning Services**, del qual el **Servei meteorològic Nacional** n'és membre

BUTLLETÍ DEL PERILL D'ALLAUS DEL PRINCIPAT D'ANDORRA

Servei meteorològic nacional
Principat d'Andorra

Couche de neige fraiche des derniers jours (De 24 h mesurée à 06:00 h UTC)

	10/04/2026	11/04/2026	12/04/2026	13/04/2026
FEDA (Central)	0 cm	0 cm	0 cm	0 cm
Engolasters - FEDA	0 cm	0 cm	0 cm	0 cm
Bony de les Neres	0 cm	0 cm	4 cm	0 cm
Sorteny	0 cm	0 cm	0 cm	0 cm
Les Fonts d'Arinsal	0 cm	0 cm	11 cm	0 cm
Aixàs	0 cm	0 cm	0 cm	0 cm
Perafita	0 cm	0 cm	10 cm	0 cm
Tossa Espiolets	0 cm	0 cm	8 cm	1 cm
Grau Roig - FEDA	0 cm	0 cm	3 cm	2 cm
Fontverd	0 cm	0 cm	4 cm	0 cm
Coll Ordino	0 cm	0 cm	2 cm	0 cm
Ransol - FEDA	0 cm	0 cm	0 cm	0 cm
Setúria	0 cm	0 cm	5 cm	0 cm
Caborreu	0 cm	0 cm	0 cm	0 cm
La Solana	0 cm	0 cm	10 cm	4 cm
Coll Pa	0 cm	0 cm	17 cm	0 cm
Envalira Antenes	0 cm	0 cm	0 cm	1 cm
Vall del Riu FEDA	0 cm	0 cm	0 cm	0 cm