Bulletin d'estimation du risque d'avalanche
(valable en dehors des pistes balisées et ouvertes)

MASSIF : Renoso Incudine

Rédigé le mardi 14 avril 2026 à 07h

Estimation des risques pour le : MARDI 14 AVRIL

DÉPARTS EN NEIGE HUMIDE AVEC LES PLUIES

3

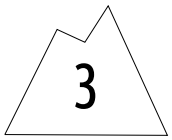

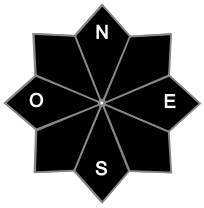

Indice de risque marqué.

Départs spontanés : Avalanches de neige humide

Déclenchements provoqués : Peu probables

Indices de risque : 5 très fort - 4 fort - 3 marqué - 2 limité - 1 faible -- En noir : les pentes les plus dangereuses

Stabilité du manteau neigeux

Situation avalancheuse typique : neige humide

Départs spontanés : Des avalanches en neige humide sont probables. Avec les fortes pluies de lundi et celles attendues mardi, l'humidification s'est faite en profondeur, dans toutes les orientations. Une couche sans cohésion identifiée en profondeur durant toute la saison peut être touchée par l'eau liquide. Ces avalanches sont le plus souvent de taille moyenne (taille 2) mais quelques avalanches de grande taille emportant tout le manteau sont possibles. Les versants raides d'un large secteur nord jusqu'ici épargnés sont aussi concernés.

Déclenchements provoqués : Un randonneur peut tout de même provoquer un départ ponctuel en surface dans la neige humide en coupant une pente raide déjà bien humidifiée.

Autres : Présence de corniches, susceptibles de rompre à cause des conditions printanières. Persistance de surfaces dures et glacées.

Qualité de la neige

Qualification de l'enneigement : L'enneigement est encore très bon pour la saison. On relève plus de 3 m de neige à Ghisoni au-dessus du lac de Bastani.

Limite d'enneigement skiable : vers 1400/1500 m Nord, 1700/1800 m en sud.

État de la neige : Regel nocturne correct en versants nord en altitude, médiocre en moyenne montagne. Rapide humidification avec les pluies avec une neige pourrie sous 2100m environ.

Au-dessus de 2100 m en nord, surface du manteau neigeux assez hétérogène alternance de neige dure et travaillée par le vent, de neige colorée par le sable décaillant à peine l'après-midi et présence d'une vieille neige récente, dense. Entre lundi et mardi, il peut tomber localement 10 à 20 cm de neige au-dessus de 2100/2200 m souvent de la neige roulée ou une neige lourde et humide.

Aperçu météo pour le mardi 14 avril

	nuit	matin	après-midi	soir
	Temps instable, averses fréquentes.			
Pluie-Neige	2 300 m	2 300 m	2 400 m	
Iso 0 °C	2 600 m	2 600 m	2 700 m	2 800 m
Vent 1500 m	15 km/h	15 km/h	20 km/h	25 km/h
Vent 2000 m	5 km/h	5 km/h	5 km/h	15 km/h

Épaisseur de neige hors-piste

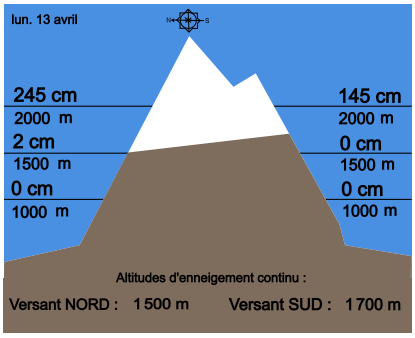

Précipitations à 1800 m

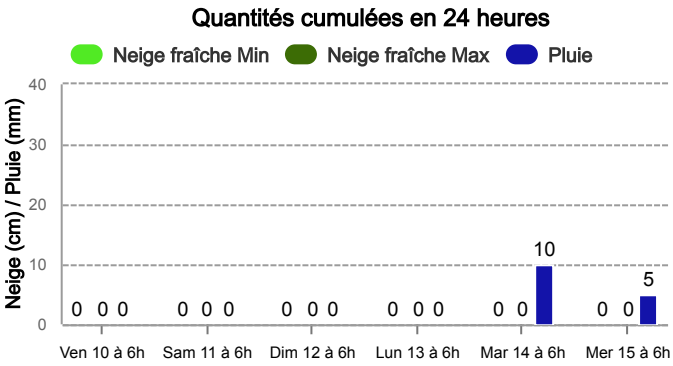

Tendance du mercredi 15 avril

Indice de risque limité

Stationnaire ou en baisse avec le retour de la douceur.

Pour consulter la vigilance en cours, veuillez vous rendre sur le site https://vigilance.meteofrance.fr/fr

Météo-France - 73 avenue de Paris, 94165 Saint-Mandé cedex - Contact : contact@meteo.fr

Rédigé par Météo-France avec la contribution des observateurs du réseau nivo-météorologiques. Partenariat : ANMSM (Maires de Stations de Montagne), DSF (Domaines Skiables de France), ADSP (Directeurs de Pistes et de la Sécurité des Stations de Sports d'Hiver) et autres acteurs de la montagne.

Bulletin neige & avalanches par téléphone au 0 892 68 10 20 Service 0,35 € / min + prix appel

RÉPUBLIQUE FRANÇAISE
Liberté Égalité Fraternité

METEO FRANCE
À VOS CÔTÉS, DANS UN CLIMAT QUI CHANGE

Bulletin d'estimation du risque d'avalanche

(valable en dehors des pistes balisées et ouvertes)

MASSIF : Renoso Incudine

Rédigé le mardi 14 avril 2026 à 07h

Conditions nivo-météo des 7 derniers jours

	mar. 07/04				mer. 08/04				jeu. 09/04				ven. 10/04				sam. 11/04				dim. 12/04				lun. 13/04			
	03h	09h	15h	21h	03h	09h	15h	21h	03h	09h	15h	21h	03h	09h	15h	21h	03h	09h	15h	21h	03h	09h	15h	21h	03h	09h	15h	21h
Météo																												
Vent (km/h)	25	20	15	10	10	15	20	15	15	20	35	35	35	25	40	50	30	25	25	15	10	30	15	45	70	20	10	10
à 2000m																												
Vent (km/h)	20	15	25	15	15	10	20	10	15	20	35	30	30	25	25	30	20	20	20	10	15	40	30	35	55	40	25	15
à 1500m																												

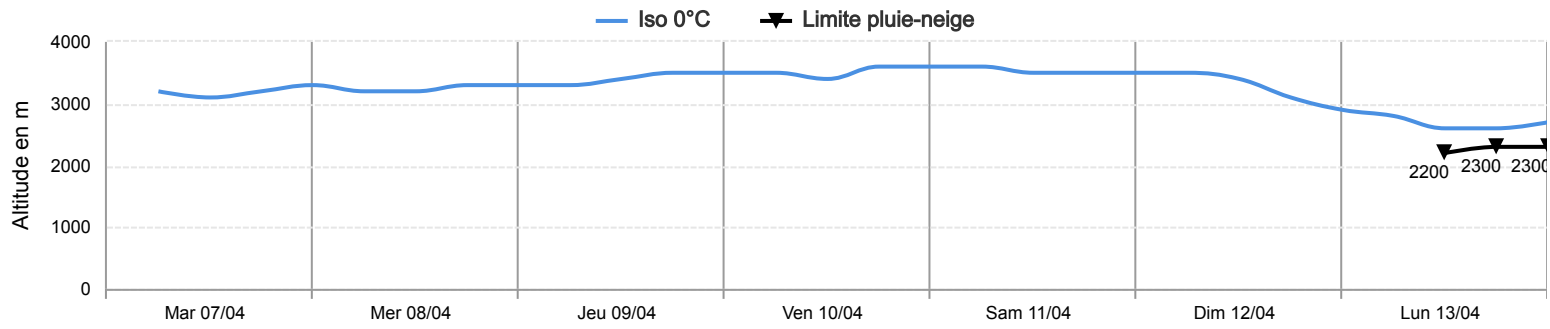

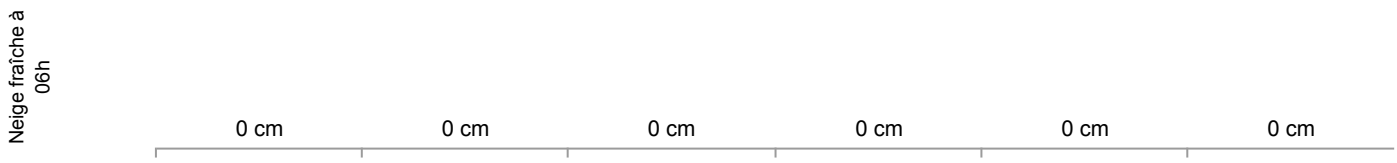

Risque d'avalanche	mar. 07/04	mer. 08/04	jeu. 09/04	ven. 10/04	sam. 11/04	dim. 12/04	lun. 13/04
		2	2	2	2	2	2

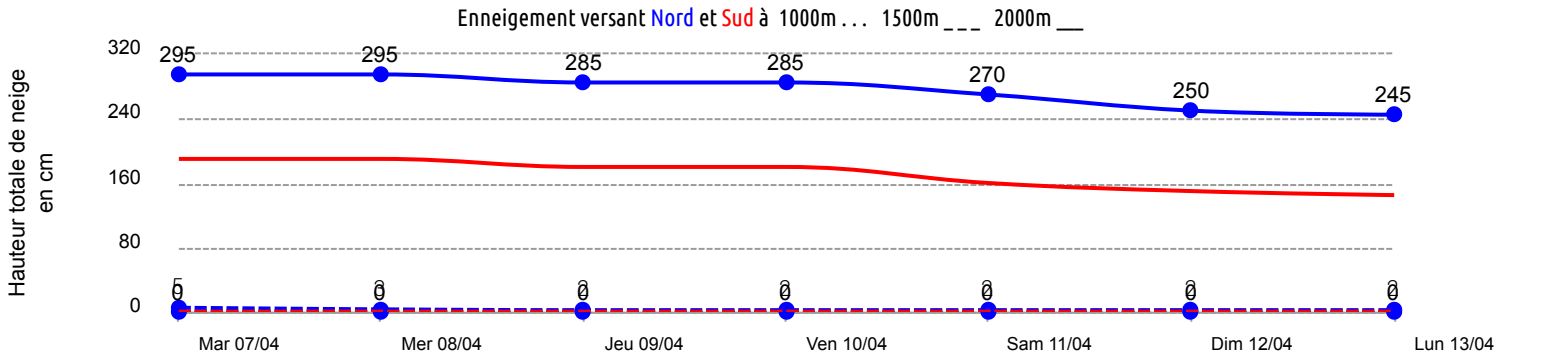

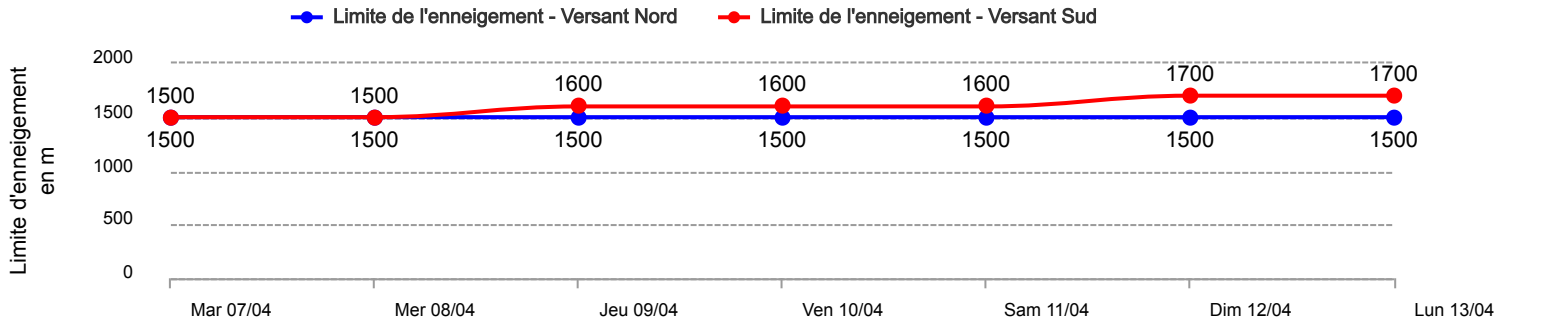

Pour consulter la vigilance en cours, veuillez vous rendre sur le site https://vigilance.meteofrance.fr/fr

Météo-France - 73 avenue de Paris, 94165 Saint-Mandé cedex - Contact : contact@meteo.fr

Rédigé par Météo-France avec la contribution des observateurs du réseau nivo-météorologiques. Partenariat : ANMSM (Maires de Stations de Montagne), DSF (Domaines Skiables de France), ADSP (Directeurs de Pistes et de la Sécurité des Stations de Sports d'Hiver) et autres acteurs de la montagne.

Bulletin neige & avalanches par téléphone au
0 892 68 10 20 Service 0,35 € / min + prix appel