GOBIERNO DE ESPAÑA
VICEPRESIDENCIA TERCERA DEL GOBIERNO
MINISTERIO PARA LA TRANSICIÓN ECOLÓGICA Y EL RETO DEMOGRÁFICO

Boletín de información nivológica y de peligro de aludes

Pirineo Catalán

aemet Agencia Estatal de Meteorología

miércoles, 15 de abril de 2026

Pronóstico hasta las 24 horas del jueves, día 16 de abril

(Válido fuera de pistas de esquí balizadas y abiertas)

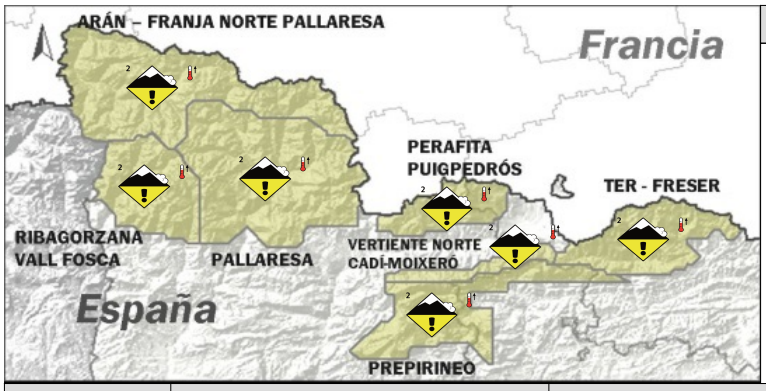

Problemas de aludes

Placas de viento

Nieve húmeda

Macizo	Peligro	Problemas de aludes, cota, orientación, tamaño	Innivación observada (m)
Arán - Franja norte Pallaresa	2 Limitado	Placas de viento: 2400, N O E S, 1 Nieve húmeda: N O E S, 2	2026-04-15 N S Cota más baja caras N
Ribagorzana - Vall Fosca	2 Limitado	Placas de viento: 2400, N O E S, 1 Nieve húmeda: N O E S, 1	2026-04-15 N S Cota más baja caras N
Pallaresa	2 Limitado	Placas de viento: 2400, N O E S, 1 Nieve húmeda: N O E S, 1	2026-04-15 N S Cota más baja caras N

AEMET. Se autoriza la reproducción de su contenido citando la fuente.

Boletín de información nivológica y de peligro de aludes

Pirineo Catalán

Perafita - Puigpedrós	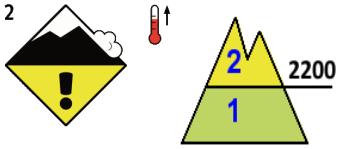 **Limitado**	**Placas de viento** 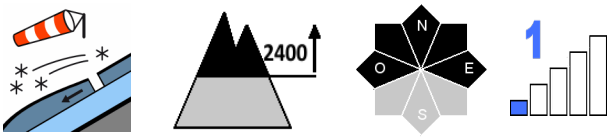 **Nieve húmeda** 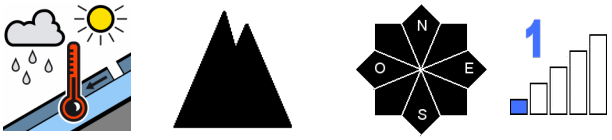	2026-04-15 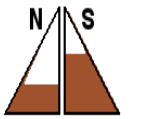 Cota más baja caras N
Ter - Freser	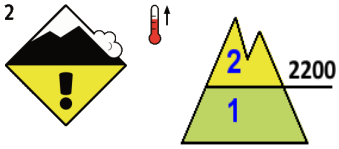 **Limitado**	**Placas de viento** 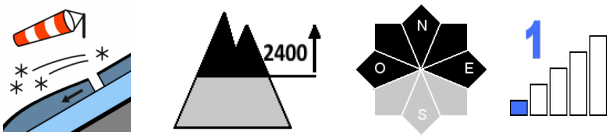 **Nieve húmeda** 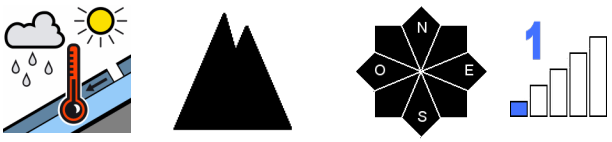	2026-04-15 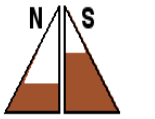 Cota más baja caras N
Vertiente norte Cadí - Moixeró	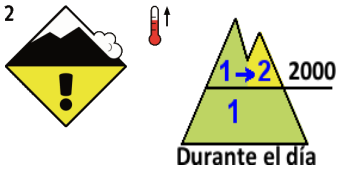 **Limitado**	**Placas de viento** **Nieve húmeda** 	2026-04-15 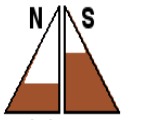 Cota más baja caras N
Prepirineo	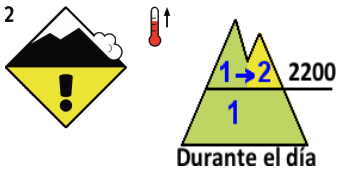 **Limitado**	**Placas de viento** 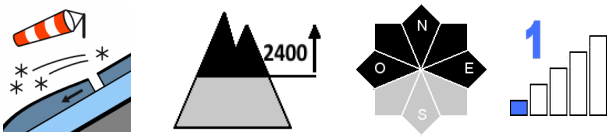 **Nieve húmeda** 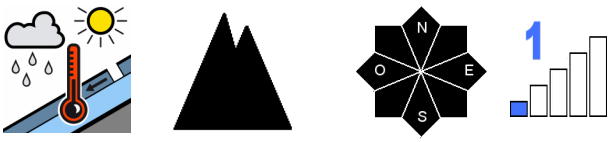	2026-04-15 Cota más baja caras N

Estado del manto y observaciones recientes

Las nevadas y el frío del fin de semana han dado paso a días de cielos despejados, mayor insolación y ascenso de las temperaturas. Los espesores van menguando algunos centímetros al día, y la cubierta de nieve es más o menos continua a partir de los 1800-1900 metros en umbrías, 2000-2100 metros en solanas. Los espesores se van incrementando a medida que ascendemos, estando muy por encima de lo que cabría esperar a estas alturas de la temporada. A unos 2200 metros se pueden encontrar entre 120 y 220 cm, aún más en ventisqueros, hoyas y otras zonas propensas a la acumulación.

AEMET. Se autoriza la reproducción de su contenido citando la fuente.

El manto es de tipo primaveral, está humedecido y en proceso de fusión. Hoy ha amanecido bien encostrado pero ha transformado rápido con la insolación. En superficie hay una capa de algunos centímetros de nieve reciente más o menos evolucionada del último episodio sobre un manto de nieve vieja. Las placas de viento que se formaron el fin de semana y con los vientos fuertes del norte que soplaron ayer, no son gruesas pero pueden permanecer frágiles en cotas altas y especialmente en umbrías a resguardo del viento y cerca de crestas y collados.

Evolución del manto y peligro de aludes para el jueves, día 16

Problema de nieve húmeda y deslizamientos basales. Problema de placas de viento en cotas altas.

Mañana continuará el ascenso de las temperaturas y el rehielo será menos efectivo. Desde por la mañana, aunque más probablemente a partir de mediodía, y sobre todo en cotas altas de solanas y medianías de umbrías se esperan purgas (riesgo de caída) o aludes medianos (capaz de enterrar a una persona) de nieve húmeda. También podrán darse deslizamientos basales en áreas herbosas o de roca lisa de tamaño generalmente mediano.

Por encima de unos 2400 metros, en zonas de acumulación de las umbrías y cerca de crestas y collados, las placas de viento se podrán mantener aún algo frágiles. Ante una sobrecarga débil (paso de un esquiador) podrán desencadenarse y provocar aludes de tamaño pequeño o más raramente mediano.

Predicción meteorológica para el jueves, día 16

Intervalos de nubes bajas matinales tendiendo a poco nuboso, con algunas nubes de evolución diurna en horas centrales. No se esperan precipitaciones. Temperaturas en ascenso, más acusado de las mínimas. Heladas débiles en las cumbres de mayor altitud. Viento flojo de dirección variable, con intervalos moderados del noroeste en cotas altas.

Datos en la atmósfera libre:

Altitud de la isoterma de 0 ºC: 3200 m
Altitud de la isoterma de -10 ºC: 4800 m

Viento a 1500 m: SW 10 km/h
Viento a 3000 m: NW 20 km/h

Evolución para el viernes día 17

Nivel de peligro con pocos cambios.

Escala europea de peligro de aludes

Débil Limitado Notable Fuerte Muy Fuerte

Problemas de aludes

Nieve reciente Placas de viento Capas débiles persistentes Nieve húmeda Deslizamientos basales Sin problema evidente

AEMET. Se autoriza la reproducción de su contenido citando la fuente.

Nota1: Se recuerda que, siempre que haya nieve, la ausencia total de peligro no existe. Hay que tener presente que en circunstancias desfavorables, con aludes de tamaño 1 (alud pequeño o colada) y tamaño 2 (alud mediano), se pueden sufrir severos daños personales.

Nota2: Los BPA se elaboran en base a información meteorológica así como al estado del manto nivoso a través de sondeos puntuales. Se advierte a los usuarios de la variabilidad de esta información al extrapolarla a zonas extensas de montaña. Por ello, AEMET no se hace responsable de su uso para la toma de decisiones que conciernen a la seguridad personal, ni de los riesgos físicos o materiales de ellas derivadas.

AEMET. Se autoriza la reproducción de su contenido citando la fuente.