GOBIERNO DE ESPAÑA
VICEPRESIDENCIA TERCERA DEL GOBIERNO
MINISTERIO PARA LA TRANSICIÓN ECOLÓGICA Y EL RETO DEMOGRÁFICO

Boletín de información nivológica y de peligro de aludes

Pirineo Navarro y Aragonés

aemet Agencia Estatal de Meteorología

miércoles, 15 de abril de 2026

Pronóstico hasta las 24 horas del jueves, día 16 de abril

(Válido fuera de pistas de esquí balizadas y abiertas)

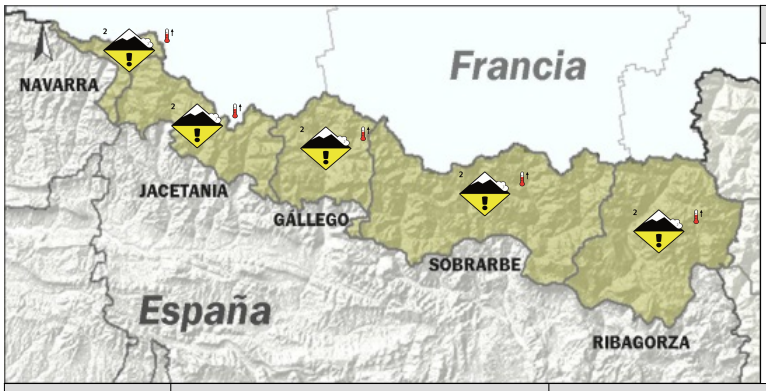

Problemas de aludes

Placas de viento

Nieve húmeda

Macizo	Peligro	Problemas de aludes, cota, orientación, tamaño	Innivación observada (m)
Navarra	2 / 2 Limitado	Placas de viento: 2400; N O E S; 1 Nieve húmeda: N O E S; 2	2026-04-15 N S Cota más baja caras N
Jacetania	2 / 2 Limitado	Placas de viento: 2400; N O E S; 1 Nieve húmeda: N O E S; 2	2026-04-15 N S Cota más baja caras N
Gállego	2 / 2 Limitado	Placas de viento: 2400; N O E S; 1 Nieve húmeda: N O E S; 2	2026-04-15 N S Cota más baja caras N

AEMET. Se autoriza la reproducción de su contenido citando la fuente.

Boletín de información nivológica y de peligro de aludes

Pirineo Navarro y Aragonés

Sobrarbe	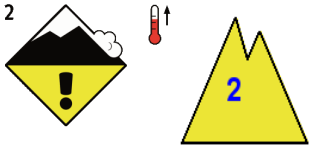 **Limitado**	**Placas de viento** 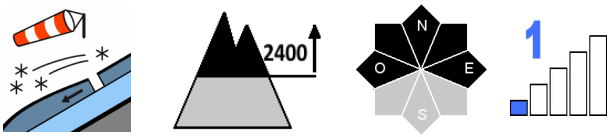 **Nieve húmeda** 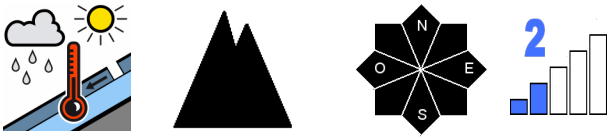	2026-04-15 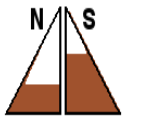 Cota más baja caras N
Ribagorza	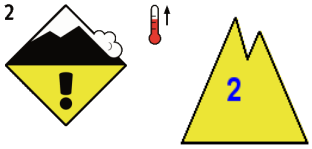 **Limitado**	**Placas de viento** **Nieve húmeda** 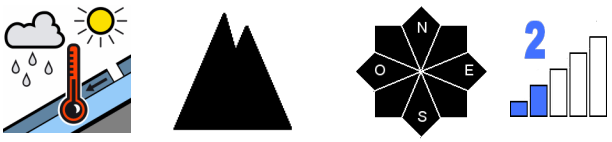	2026-04-15 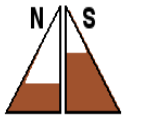 Cota más baja caras N

Estado del manto y observaciones recientes

Las nevadas y el frío del fin de semana han dado paso a días de cielos despejados, mayor insolación y ascenso de las temperaturas. Los espesores van menguando algunos centímetros al día, y la cubierta de nieve es más o menos continua a partir de los 1700-1900 metros en umbrías, 1900-2100 metros en solanas. Los espesores se van incrementando a medida que ascendemos, estando muy por encima de lo que cabría esperar a estas alturas de la temporada. A unos 2200 metros se pueden encontrar entre 60 y 170 cm, aún más en ventisqueros, hoyas y otras zonas propensas a la acumulación.

El manto es de tipo primaveral, está humedecido y en proceso de fusión. Hoy ha amanecido bien encostrado pero ha transformado rápido con la insolación. En superficie hay una capa de algunos centímetros de nieve reciente más o menos evolucionada del último episodio sobre un manto de nieve vieja. Las placas de viento que se formaron el fin de semana y con los vientos fuertes del norte que soplaron ayer, no son gruesas pero pueden permanecer frágiles en cotas altas y especialmente en umbrías a resguardo del viento y cerca de crestas y collados.

Evolución del manto y peligro de aludes para el jueves, día 16

Problema de nieve húmeda y deslizamientos basales. Problema de placas de viento en cotas altas.

Mañana continuará el ascenso de las temperaturas y el rehielo será menos efectivo. Desde por la mañana, aunque más probablemente a partir de mediodía, y sobre todo en cotas altas de solanas y medianías de umbrías se esperan purgas (riesgo de caída) o aludes medianos (capaz de enterrar a una persona) de nieve húmeda. También podrán darse deslizamientos basales en áreas herbosas o de roca lisa de tamaño generalmente mediano.

AEMET. Se autoriza la reproducción de su contenido citando la fuente.

Por encima de unos 2400 metros, en zonas de acumulación de las umbrías y cerca de crestas y collados, las placas de viento se podrán mantener aún algo frágiles. Ante una sobrecarga débil (paso de un esquiador) podrán desencadenarse y provocar aludes de tamaño pequeño o más raramente mediano.

Predicción meteorológica para el jueves, día 16

Intervalos de nubes bajas matinales tendiendo a poco nuboso, con algunas nubes de evolución diurna en horas centrales. No se esperan precipitaciones. Temperaturas mínimas con pocos cambios y máximas en ascenso ligero o moderado. Heladas débiles en las cumbres de mayor altitud. Viento flojo de dirección variable.

Datos en la atmósfera libre:

Altitud de la isoterma de 0 ºC: 3200 m
Altitud de la isoterma de -10 ºC: 4900 m

Viento a 1500 m: SW 10 km/h
Viento a 3000 m: W 20 km/h

Evolución para el viernes día 17

Nivel de peligro con pocos cambios.

(Información elaborada a partir de los datos recibidos de los refugios de Linza, Lizara, Respomuso, Panticosa, Bachimaña, Góriz, Pineta, Estós, Angel Orús, La Renclusa, Cap de Llauset y Belagua, de las estaciones de esquí de Formigal y Panticosa (lagos) y de Ordesa Pradera)

Escala europea de peligro de aludes

Débil | Limitado | Notable | Fuerte | Muy Fuerte

Problemas de aludes

Nieve reciente | Placas de viento | Capas débiles persistentes | Nieve húmeda | Deslizamientos basales | Sin problema evidente

Nota1: Se recuerda que, siempre que haya nieve, la ausencia total de peligro no existe. Hay que tener presente que en circunstancias desfavorables, con aludes de tamaño 1 (alud pequeño o colada) y tamaño 2 (alud mediano), se pueden sufrir severos daños personales.

Nota2: Los BPA se elaboran en base a información meteorológica así como al estado del manto nivoso a través de sondeos puntuales. Se advierte a los usuarios de la variabilidad de esta información al extrapolarla a zonas extensas de montaña. Por ello, AEMET no se hace responsable de su uso para la toma de decisiones que conciernen a la seguridad personal, ni de los riesgos físicos o materiales de ellas derivadas.

AEMET. Se autoriza la reproducción de su contenido citando la fuente.