Donnerstag 16.04.2026

Veröffentlicht am 15.04.2026 um 17:00

Vormittag

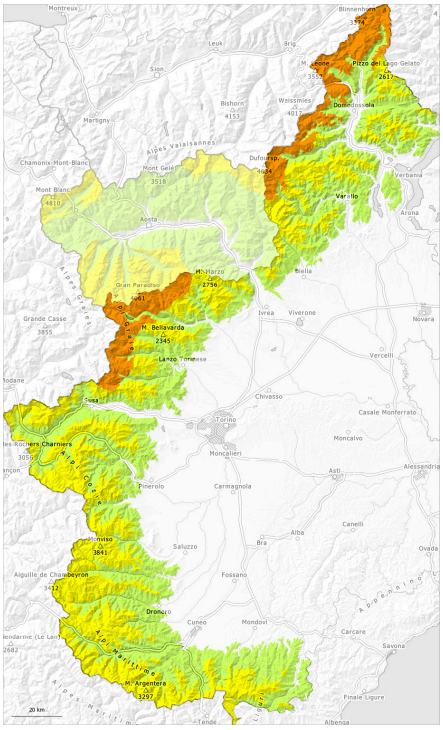

Nachmittag

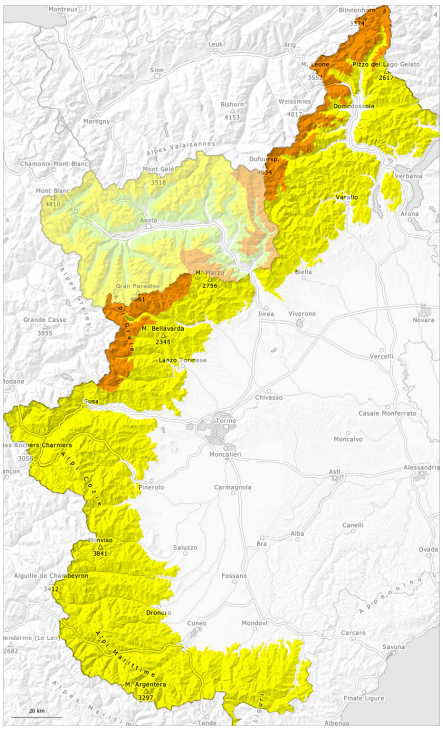

1	2	3	4	5
gering	mäßig	erheblich	groß	sehr groß

Gefahrenstufe 3 - Erheblich

AM:

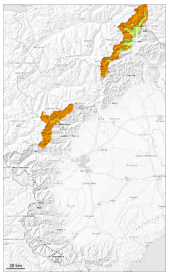

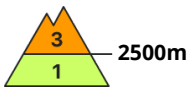

Tendenz: Lawinengefahr bleibt gleich
am Freitag, den 17.04.2026

Triebschnee

2500m

PM:

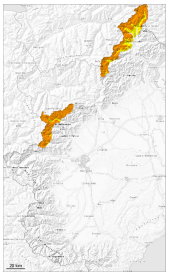

Tendenz: Lawinengefahr bleibt gleich
am Freitag, den 17.04.2026

Triebschnee

2500m

Nassschnee

2800m

Neu- und Triebschnee in der Höhe. Vor allem aber nimmt die Gefahr von feuchten und nassen Lawinen im Tagesverlauf zu.

Oberhalb von rund 2500 m: Mit Neuschnee und Nordostwind entstanden in den letzten drei Tagen in Kamm- und Passlagen teils störanfällige Triebschneeansammlungen. Lawinen können in oberflächennahen Schichten ausgelöst werden und vor allem an sehr steilen Schattenhängen groß werden.

V.a. an sehr steilen Grashängen und an felsdurchsetzten Hängen sind mit der Anfeuchtung mittlere und vereinzelt große nasse Lawinen im Tagesverlauf möglich. Spontane Lawinen und Durchbrechen in den Altschnee sind Hinweise für den ungünstigen Schneedeckenaufbau.
Touren sollten früh gestartet und beendet werden.

Schneedecke

Gefahrenmuster gm.6: lockerer schnee und wind | gm.10: frühjahrssituation

Seit Sonntag fielen oberhalb von rund 2000 m verbreitet 40 bis 60 cm Schnee, lokal auch mehr. In den letzten zwei Tagen wurden oberhalb von rund 2500 m zahlreiche kleine und mittlere Lawinen beobachtet. In hohen Lagen sind mehrere teils große Staublawinen abgegangen.

Schattenhänge sowie hohe Lagen: Neu- und Triebschnee liegen verbreitet auf einer harten Kruste.

Klare Nacht: Die Schneeoberfläche ist tragfähig gefroren. Sonne und Wärme führen im Tagesverlauf zu einer raschen Anfeuchtung der Schneedecke. Dies vor allem an steilen Ost-, Süd- und Westhängen in

mittleren und hohen Lagen sowie an Nordhängen unterhalb von rund 2400 m.
Unterhalb von rund 2500 m liegt an Südhängen nur wenig Schnee.

Tendenz

Es ist mild. Nach klarer Nacht allgemein günstige Verhältnisse, dann steigt die Gefahr von Nass- und Gleitschneelawinen an.

Mit starken Temperaturschwankungen und Sonneneinstrahlung stabilisieren sich die Triebschneeansammlungen in den nächsten Tagen.

Gefahrenstufe 2 - Mäßig

AM:

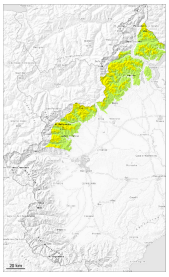

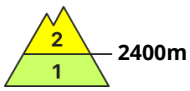

Tendenz: Lawinengefahr bleibt gleich
am Freitag, den 17.04.2026

Triebschnee

2400m

PM:

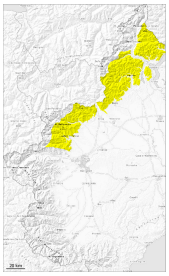

Tendenz: Lawinengefahr bleibt gleich
am Freitag, den 17.04.2026

Triebschnee

2400m

Nassschnee

2700m

Die Gefahr von feuchten und nassen Lawinen steigt im Tagesverlauf an.

Mit Neuschnee und Nordostwind entstanden in den letzten drei Tagen in Kamm- und Passlagen teils störanfällige Triebschneeansammlungen. Diese können vor allem mit großer Belastung ausgelöst werden und mittlere Größe erreichen. Dies vor allem an sehr steilen Hängen sowie an Felswandfüßen und hinter Geländekanten.

V.a. an sehr steilen Hängen sind mit der tageszeitlichen Erwärmung und der Sonneneinstrahlung kleine und mittlere Gleitschneelawinen und feuchte Rutsche möglich.

Spontane Lawinen und Durchbrechen in den Altschnee sind Hinweise für den schwachen Schneedeckenaufbau. Touren sollten früh gestartet und rechtzeitig beendet werden.

Schneedecke

Gefahrenmuster gm.6: lockerer schnee und wind | gm.10: frühjahrssituation

Seit Sonntag fielen oberhalb von rund 2000 m verbreitet 40 bis 60 cm Schnee, lokal auch mehr. Seit Dienstag wurden oberhalb von rund 2500 m mehrere kleine und mittlere Lawinen beobachtet.

Klare Nacht: Die Schneeoberfläche ist tragfähig gefroren. Sonne und Wärme führen im Tagesverlauf zu einer raschen Anfeuchtung der Schneedecke. Dies vor allem an steilen Ost-, Süd- und Westhängen in mittleren und hohen Lagen sowie an Nordhängen unterhalb von rund 2400 m.
Unterhalb von rund 2400 m liegt an Südhängen nur wenig Schnee.

Tendenz

Es ist mild.
Nach klarer Nacht allgemein günstige Verhältnisse, dann steigt die Gefahr von Nass- und Gleitschneelawinen an.

Gefahrenstufe 2 - Mäßig

AM:

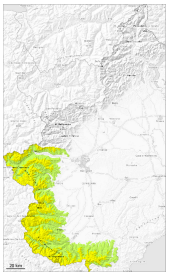

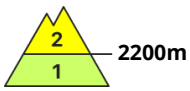

Tendenz: Lawinengefahr bleibt gleich
am Freitag, den 17.04.2026

Triebschnee

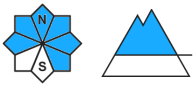

PM:

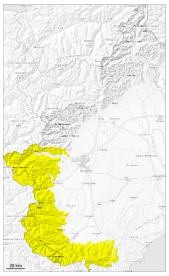

Tendenz: Lawinengefahr bleibt gleich
am Freitag, den 17.04.2026

Triebschnee

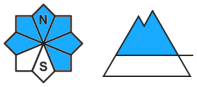

Nassschnee

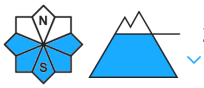

Die Gefahr von feuchten und nassen Lawinen steigt im Tagesverlauf an.

Der Neuschnee und die während dem Schneefall entstandenen, meist kleinen Triebschneeansammlungen können in hohen Lagen vor allem mit großer Zusatzbelastung ausgelöst werden. Dies vor allem an sehr steilen Hängen sowie an Felswandfüßen und hinter Geländekanten.

V.a. an sehr steilen Hängen sind mit der tageszeitlichen Erwärmung und der Sonneneinstrahlung kleine und mittlere Gleitschneelawinen und feuchte Rutsche möglich.

Spontane Lawinen und Durchbrechen in den Altschnee sind Hinweise für den schwachen Schneedeckenaufbau. Touren sollten früh gestartet und rechtzeitig beendet werden.

Schneedecke

Gefahrenmuster gm.6: lockerer schnee und wind | gm.10: frühjahrssituation

Seit Sonntag fielen oberhalb von rund 2100 m verbreitet 5 bis 30 cm Schnee. Der Schneeregen führte am Dienstag unterhalb von rund 2200 m zu einer Anfeuchtung der Schneedecke.
Die Schneeoberfläche ist tragfähig gefroren und weicht schon am Vormittag auf. Dies vor allem an steilen Ost-, Süd- und Westhängen unterhalb von rund 2700 m sowie an Nordhängen unterhalb von rund 2400 m.

Unterhalb von rund 2200 m liegt an Südhängen kein Schnee.

Tendenz

Es ist mild.
Nach klarer Nacht allgemein günstige Verhältnisse, dann steigt die Gefahr von Nass- und Gleitschneelawinen an.