# Donnerstag 16.04.2026

Veröffentlicht am 15.04.2026 um 17:00

## Vormittag

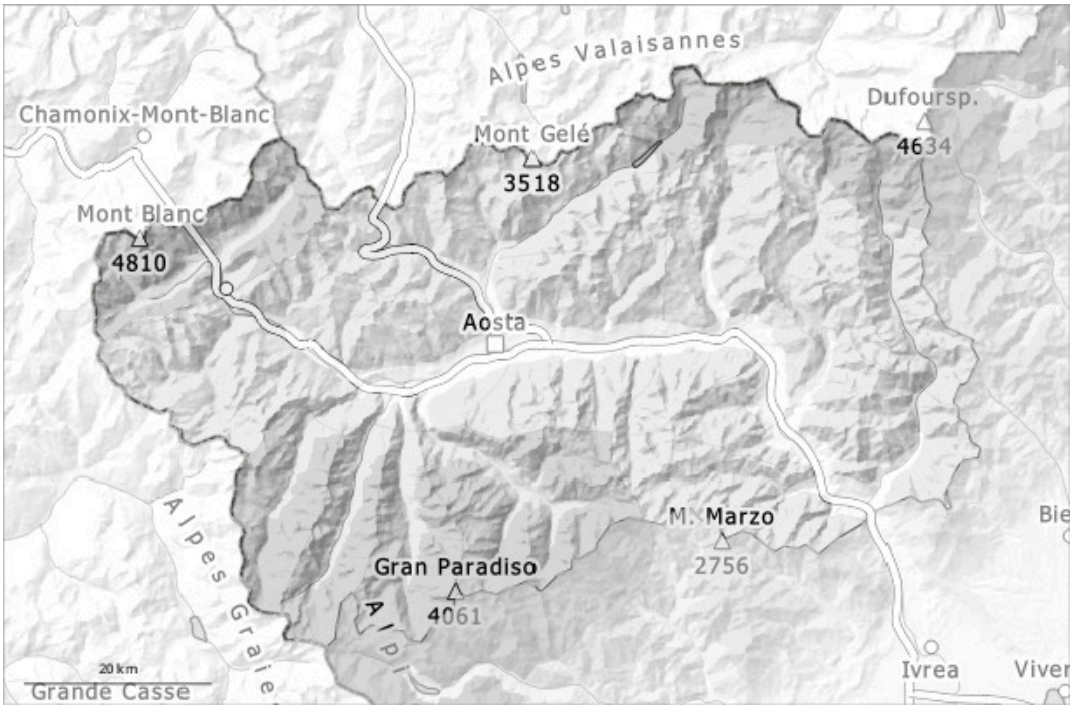


## Nachmittag

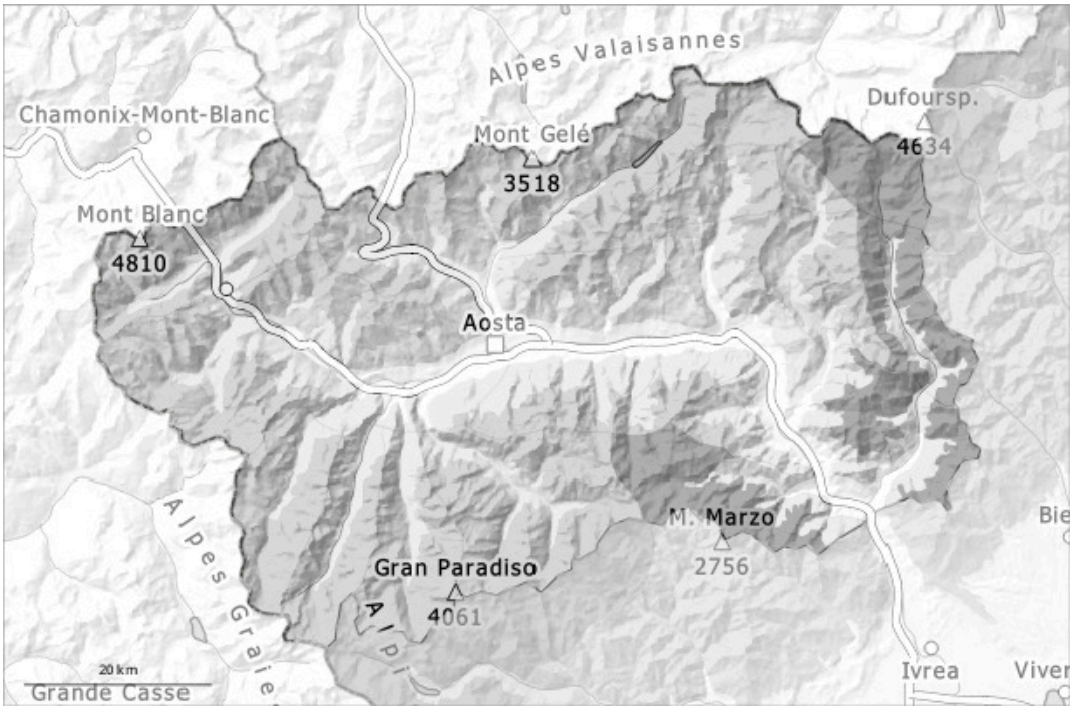


| 1 | 2 | 3 | 4 | 5 |
|---|---|---|---|---|
| gering | mäßig | erheblich | groß | sehr groß |

## Gefahrenstufe 3 - Erheblich

### AM:

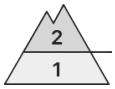


2700m

**Tendenz: Lawinengefahr nimmt ab**
am Freitag, den 17.04.2026

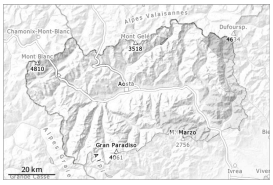

Triebschnee

2700m

Nassschnee

2500m

### PM:

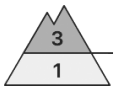


2200m

**Tendenz: Lawinengefahr nimmt ab**
am Freitag, den 17.04.2026

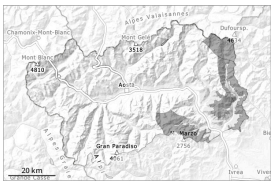

Nassschnee

3000m
2200m

Triebschnee

2700m

## Die Gefahr von feuchten und nassen Lawinen ist schon am Morgen erhöht. Dies bei bedeckter Nacht.

Morgen: Für Skitouren sind die Verhältnisse mehrheitlich günstig.
Bei nächtlicher Bewölkung in Verbindung mit warmer Luft wird die Lawinengefahr bereits am Morgen mäßig sein, da Die Schneeoberfläche gefriert nur knapp. Dann werden die Bedingungen im Mittelgebirge bereits teilweise ungünstig sein.
Die spontane Aktivität von feuchten und nassen Lawinen nimmt am Vormittag schnell zu. Vor allem aus noch nicht entladenen Einzugsgebieten und an sehr steilen Hängen sind weiterhin mittlere und vereinzelt große spontane nasse Lawinen zu erwarten.
Touren und Hüttenaufstiege sollten rechtzeitig beendet werden.
Mit Neuschnee und teils mäßigem Südostwind entstanden am Montag teils störanfällige Triebschneeansammlungen. Sie entstanden in hohen Lagen und im Hochgebirge.

## Schneedecke

**Gefahrenmuster** gm.10: frühjahrssituation

Die Schneeoberfläche ist kaum gefroren. Am Montag fielen oberhalb von rund 2300 m 20 bis 40 cm Schnee, lokal auch mehr. Neu- und Triebschnee liegen auf einer nassen Altschneedecke.

In höheren Lagen nimmt die Schneedecke ab und wird ungleichmäßig; in mittleren Höhenlagen, die weniger vom Wind betroffen sind, ist sie besser. Unterhalb von rund 1900 m liegt kaum Schnee.
In der Schneedecke sind v.a. an steilen Schattenhängen Schwachschichten vorhanden.

## Tendenz

Die frühlingshaften Wetterbedingungen führen zu einer Setzung der Schneedecke. Mit der Anfeuchtung sind weiterhin feuchte und nasse Lawinen möglich.

## Gefahrenstufe 2 - Mäßig

### AM:

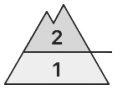


**2900m**

**Tendenz: Lawinengefahr nimmt ab**
am Freitag, den 17.04.2026

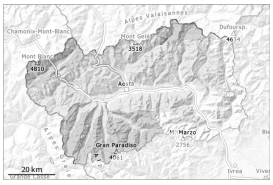

Triebschnee

**2900m**

Nassschnee

**2500m**

### PM:

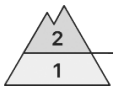


**2200m**

**Tendenz: Lawinengefahr nimmt ab**
am Freitag, den 17.04.2026

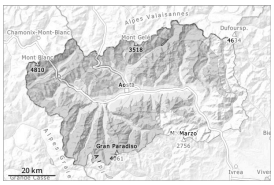

Nassschnee

**3000m**
**2200m**

Triebschnee

**2900m**

## Die Gefahr von feuchten und nassen Lawinen steigt bereits am Vormittag an.

Für Skitouren sind die Verhältnisse mehrheitlich günstig.
Die Schneeoberfläche gefriert nicht tragfähig und weicht schon am Vormittag auf.
Bei nächtlicher Bewölkung in Verbindung mit warmer Luft wird die Lawinengefahr bereits am Morgen mäßig sein, da Die Schneeoberfläche kühlt in der bedeckten Nacht kaum ab. Dann werden die Bedingungen im Mittelgebirge bereits teilweise ungünstig sein.
Die spontane Aktivität von feuchten und nassen Lawinen nimmt am Vormittag allmählich zu. Aus noch nicht entladenen Einzugsgebieten und an sehr steilen Hängen sind weiterhin kleine und vereinzelt mittlere feuchte Rutsche und Lawinen möglich.
Touren und Hüttenaufstiege sollten rechtzeitig beendet werden.
Mit Neuschnee und teils mäßigem Südostwind entstanden am Montag meist kleine Triebschneeansammlungen. Sie entstanden in hohen Lagen und im Hochgebirge.

## Schneedecke

**Gefahrenmuster** gm.10: frühjahrssituation

Kälter als erwartet: Die Schneeoberfläche ist tragfähig gefroren. Neu- und Triebschnee liegen auf einer

nassen Altschneedecke.
In höheren Lagen nimmt die Schneedecke ab und wird ungleichmäßig; in mittleren Höhenlagen, die weniger vom Wind betroffen sind, ist sie besser. Unterhalb von rund 1900 m liegt kaum Schnee.
In der Schneedecke sind v.a. an steilen Schattenhängen Schwachschichten vorhanden.

## Tendenz

Mit der tageszeitlichen Erwärmung und der Sonneneinstrahlung sind weiterhin feuchte und nasse Lawinen möglich. Sonne und Wärme führen zu einer Setzung der Schneedecke.