Donnerstag 16.04.2026

Veröffentlicht am 15.04.2026 um 17:00

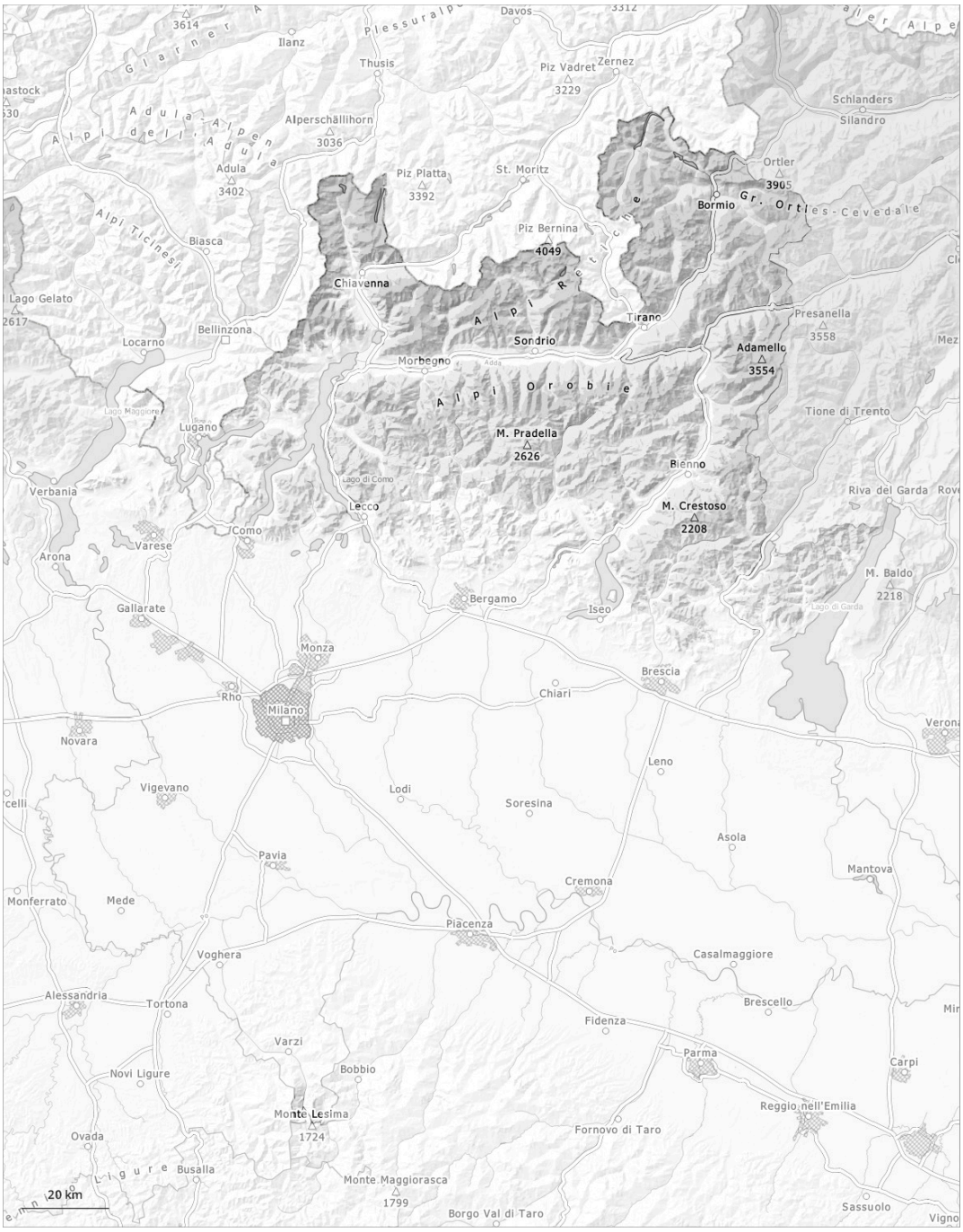

1	2	3	4	5
gering	mäßig	erheblich	groß	sehr groß

Gefahrenstufe 2 - Mäßig

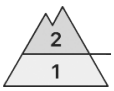

Waldgrenze

Tendenz: Lawinengefahr bleibt gleich
am Freitag, den 17.04.2026

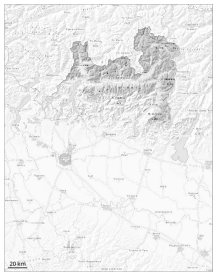

Nassschnee

Waldgrenze

Altschnee

Waldgrenze

Nassschnee

Waldgrenze

Es ist verbreitet teils bewölkt.
Erwärmung.

Die Gefahrenstellen für trockene Lawinen liegen an steilen Schattenhängen oberhalb von rund 2500 m.
Mit der tageszeitlichen Erwärmung und der Sonneneinstrahlung steigt die Auslösebereitschaft von nassen Lawinen v.a. an steilen Schattenhängen unterhalb von rund 2500 m an.
Mittlere Lawinen sind möglich.

Schneedecke

Gefahrenmuster gm.6: lockerer schnee und wind | gm.10: frühjahrssituation

Die Schneeoberfläche weicht schon am Vormittag auf.
In den letzten Tagen fiel verbreitet Schnee oberhalb von rund 2400 m.
Mit Wind entstanden im Hochgebirge meist dünne Triebschneeansammlungen.
Steile Schattenhänge oberhalb von rund 2500 m: Im unteren Teil der Altschneedecke sind kantig aufgebaute Schwachschichten vorhanden.
Unterhalb von rund 2000 m liegt für Schneesport meist zu wenig Schnee.

Gefahrenstufe 1 - Gering

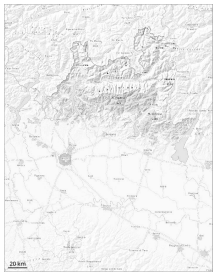

1

Tendenz: Lawinengefahr bleibt gleich
am Freitag, den 17.04.2026

Nassschnee

N S

1800m

Es ist verbreitet teils bewölkt.
Erwärmung.

Die Schneeoberfläche ist kaum gefroren und ist schon am Morgen aufgeweicht.
Die Lawinen sind vereinzelt klein.

Schneedecke

Gefahrenmuster gm.10: frühjahrssituation

Mit milden Temperaturen verfestigte sich die Schneedecke. Mit der tageszeitlichen Erwärmung steigt die Gefahr von feuchten und nassen Lawinen an.