Donnerstag 16.04.2026

Veröffentlicht am 15.04.2026 um 17:00

Vormittag

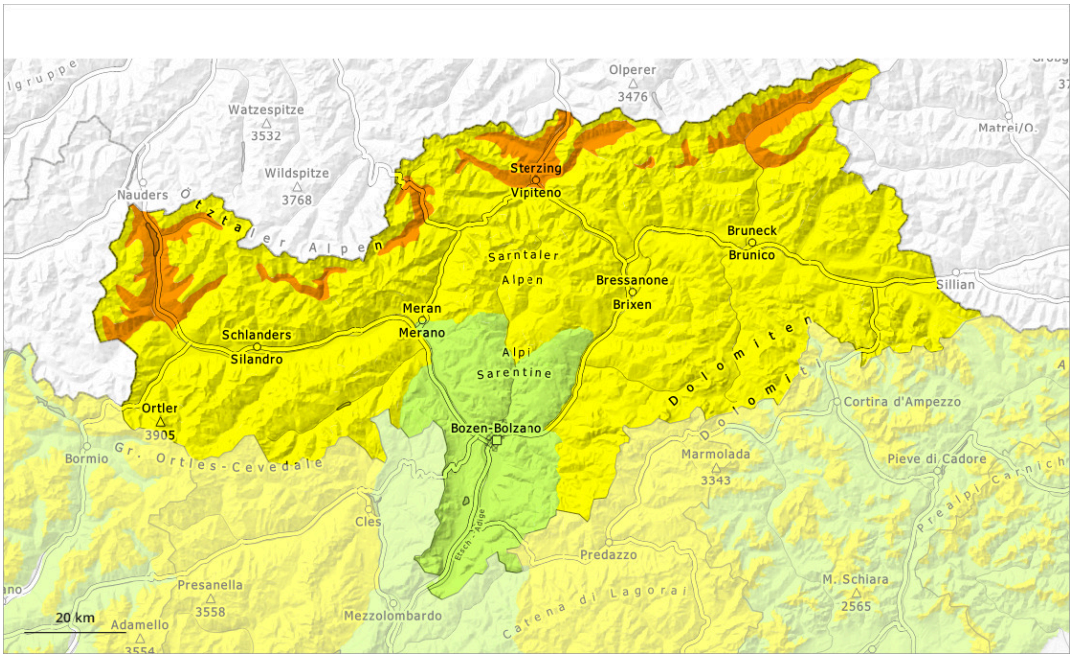

Nachmittag

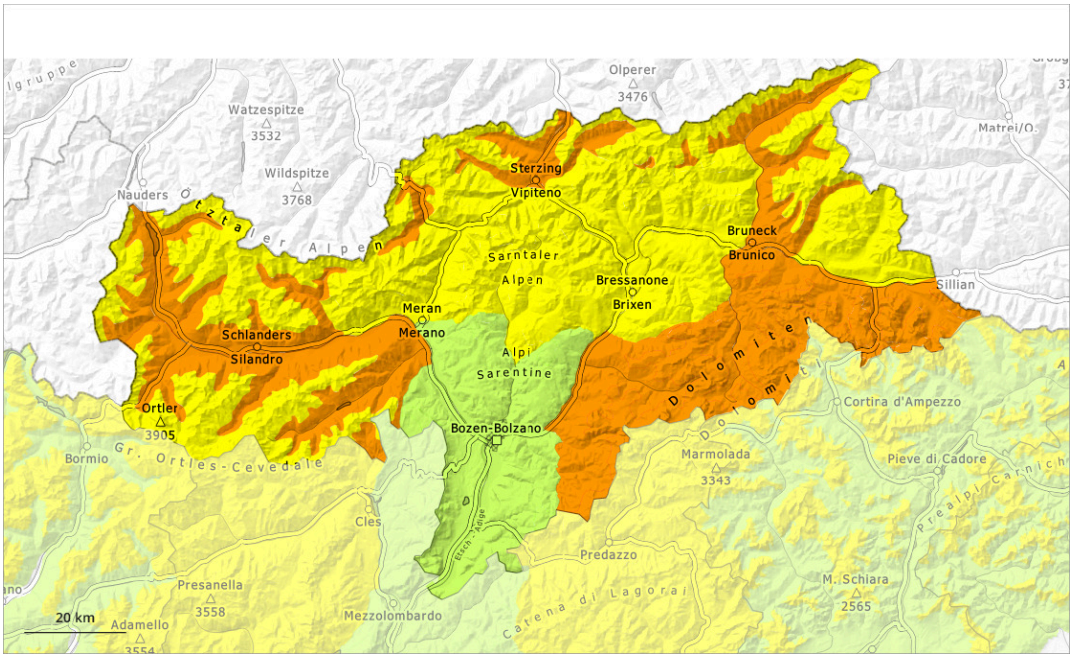

1	2	3	4	5
gering	mäßig	erheblich	groß	sehr groß

Gefahrenstufe 3 - Erheblich

AM:

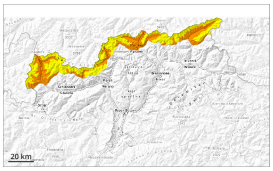

2500m

Tendenz: Lawinengefahr bleibt gleich
am Freitag, den 17.04.2026

Nassschnee

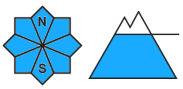

2500m

Altschnee

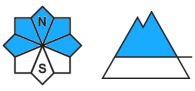

2500m

PM:

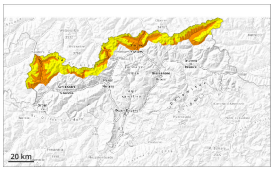

2800m

Tendenz: Lawinengefahr bleibt gleich
am Freitag, den 17.04.2026

Nassschnee

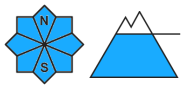

2800m

Altschnee

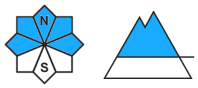

2500m

Ungünstige Lawinensituation. Nassschnee ist die Hauptgefahr.

Mit der tageszeitlichen Erwärmung und der Sonneneinstrahlung steigt die Gefahr von nassen Lawinen am Morgen rasch an. Feuchte und nasse Lawinen können stellenweise von einzelnen Wintersportlern ausgelöst werden. Vorsicht vor allem an sehr steilen Hängen unterhalb von rund 2500 m.
Mit der Durchnässung nimmt die Anzahl der Gefahrenstellen im Tagesverlauf zu. Es sind am Nachmittag vermehrt nasse Schneebrettlawinen zu erwarten. Vorsicht vor allem an steilen Schattenhängen zwischen etwa 2200 und 2600 m. Nasse Lawinen können besonders dort bis in tiefe Schichten durchreißen und groß werden. Dies vereinzelt auch im häufig befahrenen Variantengelände. Die Lawinen können in steilen Rinnen bis ins Grüne vorstoßen.

Einzelne Gefahrenstellen für trockene Lawinen liegen an sehr steilen Schattenhängen oberhalb von rund 2500 m. Solche Gefahrenstellen sind schwer zu erkennen. Ungünstig sind besonders Übergänge von wenig zu viel Schnee.

Schneedecke

Gefahrenmuster gm.10: frühjahrssituation | gm.1: bodennahe schwachschicht

Die nächtliche Abstrahlung ist stark eingeschränkt. Damit gefriert die Schneedecke nur knapp. Sonne und

Wärme führen im Tagesverlauf unterhalb von rund 2800 m zu einer zunehmenden Durchnässung der Schneedecke. Die hohe Luftfeuchtigkeit führt am Nachmittag auch an steilen Schattenhängen zu einem Festigkeitsverlust innerhalb der Schneedecke.
West-, Nord- und Osthänge oberhalb von rund 2200 m: Der untere Teil der Schneedecke ist aufbauend umgewandelt.

Tendenz

Die nächtliche Abstrahlung ist recht gut. Die Tourenverhältnisse sind am Morgen in der Höhe recht günstig. Mit der tageszeitlichen Erwärmung und der Sonneneinstrahlung steigt die Gefahr von nassen Lawinen im Tagesverlauf an.

Gefahrenstufe 3 - Erheblich

AM:

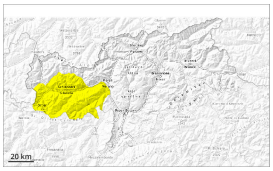

Tendenz: Lawinengefahr bleibt gleich
am Freitag, den 17.04.2026

Nassschnee

Altschnee

PM:

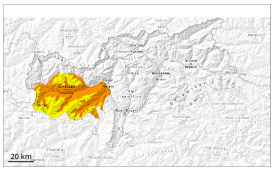

Tendenz: Lawinengefahr bleibt gleich
am Freitag, den 17.04.2026

Nassschnee

Altschnee

Anstieg der Gefahr von nassen Lawinen im Tagesverlauf.

Mit der tageszeitlichen Erwärmung und der Sonneneinstrahlung steigt die Gefahr von nassen Lawinen an. Es sind im Tagesverlauf einzelne spontane Lawinen möglich. Dies an Schattenhängen unterhalb von rund 2500 m sowie an Sonnenhängen in der Höhe. Lawinen können besonders an steilen Schattenhängen im schwachen Altschnee anreißen und vereinzelt groß werden.

Zudem können trockene Lawinen durch Personen ausgelöst werden, besonders an sehr steilen West-, Nord- und Osthängen oberhalb von rund 2500 m. Ungünstig sind besonders Übergänge von wenig zu viel Schnee. Die Gefahrenstellen sind schwer zu erkennen.
Die nicht mehr ganz frischen Triebschneeansammlungen können vor allem an sehr steilen Schattenhängen im Hochgebirge vereinzelt von einzelnen Wintersportlern ausgelöst werden.

Schneedecke

Gefahrenmuster gm.10: frühjahrssituation | gm.1: bodennahe schwachschicht

Die Schneeoberfläche gefriert nur in hohen Lagen tragfähig und weicht schon am Vormittag auf. Sonne und Wärme führen unterhalb von rund 3000 m zu einer zunehmenden Durchnässung der Schneedecke. Die hohe Luftfeuchtigkeit führt am Nachmittag auch an steilen Schattenhängen zu einem Festigkeitsverlust

innerhalb der Schneedecke.
Steile West-, Nord- und Osthänge: Im unteren Teil der Altschneedecke sind in der Höhe kantig aufgebaute Schwachschichten vorhanden.

Tendenz

Die nächtliche Abstrahlung ist gut. Die Tourenverhältnisse sind am Morgen in der Höhe mehrheitlich günstig. Mit der tageszeitlichen Erwärmung und der Sonneneinstrahlung steigt die Gefahr von nassen Lawinen im Tagesverlauf an.

Gefahrenstufe 3 - Erheblich

AM:

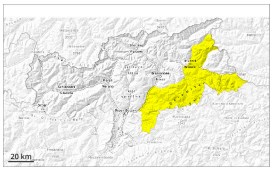

Tendenz: Lawinengefahr bleibt gleich
am Freitag, den 17.04.2026

Nassschnee

Altschnee

PM:

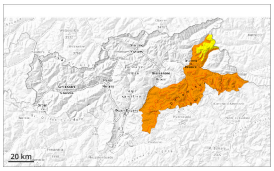

Tendenz: Lawinengefahr bleibt gleich
am Freitag, den 17.04.2026

Nassschnee

Altschnee

Anstieg der Gefahr von nassen Lawinen im Tagesverlauf.

Mit der tageszeitlichen Erwärmung und der Sonneneinstrahlung steigt die Gefahr von nassen Lawinen an. Es sind im Tagesverlauf einzelne spontane Lawinen möglich. Dies an Schattenhängen unterhalb von rund 2500 m sowie an Sonnenhängen in der Höhe. Lawinen können besonders an steilen Schattenhängen im schwachen Altschnee anreißen und vereinzelt groß werden.

Zudem können trockene Lawinen durch Personen ausgelöst werden, besonders an sehr steilen West-, Nord- und Osthängen oberhalb von rund 2500 m. Ungünstig sind besonders Übergänge von wenig zu viel Schnee. Die Gefahrenstellen sind schwer zu erkennen.

Schneedecke

Gefahrenmuster gm.10: frühjahrssituation | gm.1: bodennahe schwachschicht

Die Schneeoberfläche gefriert nur in hohen Lagen tragfähig und weicht schon am Vormittag auf. Sonne und Wärme führen unterhalb von rund 3000 m zu einer zunehmenden Durchnässung der Schneedecke. Die hohe Luftfeuchtigkeit führt am Nachmittag auch an steilen Schattenhängen zu einem Festigkeitsverlust innerhalb der Schneedecke.
Steile West-, Nord- und Osthänge: Im unteren Teil der Altschneedecke sind in der Höhe kantig aufgebaute

Schwachschichten vorhanden.

Tendenz

Die nächtliche Abstrahlung ist gut. Die Tourenverhältnisse sind am Morgen in der Höhe mehrheitlich günstig. Mit der tageszeitlichen Erwärmung und der Sonneneinstrahlung steigt die Gefahr von nassen Lawinen im Tagesverlauf an.

Gefahrenstufe 2 - Mäßig

AM:

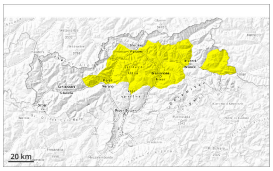

Tendenz: Lawinengefahr bleibt gleich
am Freitag, den 17.04.2026

Nassschnee

Altschnee

PM:

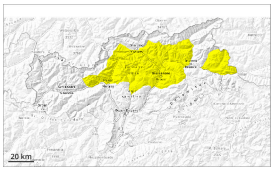

Tendenz: Lawinengefahr bleibt gleich
am Freitag, den 17.04.2026

Nassschnee

Altschnee

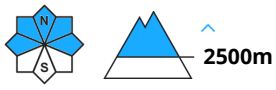

Anstieg der Gefahr von nassen Lawinen im Tagesverlauf.

Mit der tageszeitlichen Erwärmung und der Sonneneinstrahlung steigt die Gefahr von nassen Lawinen innerhalb der Gefahrenstufe an. Es sind im Tagesverlauf einzelne spontane Lawinen möglich. Dies an Schattenhängen unterhalb von rund 2500 m sowie an Sonnenhängen in der Höhe. Lawinen können besonders an steilen Schattenhängen im schwachen Altschnee anreißen und vereinzelt groß werden.

Zudem können trockene Lawinen durch Personen ausgelöst werden, besonders an sehr steilen West-, Nord- und Osthängen oberhalb von rund 2500 m. Ungünstig sind besonders Übergänge von wenig zu viel Schnee. Die Gefahrenstellen sind schwer zu erkennen.

Schneedecke

Gefahrenmuster gm.10: frühjahrssituation | gm.1: bodennahe schwachschicht

Die Schneeoberfläche gefriert nur in hohen Lagen tragfähig und weicht schon am Vormittag auf. Sonne und Wärme führen unterhalb von rund 3000 m zu einer zunehmenden Durchnässung der Schneedecke. Die hohe Luftfeuchtigkeit führt am Nachmittag auch an steilen Schattenhängen zu einem Festigkeitsverlust innerhalb der Schneedecke.
Steile West-, Nord- und Osthänge: Im unteren Teil der Altschneedecke sind in der Höhe kantig aufgebaute

Schwachschichten vorhanden.

Tendenz

Die nächtliche Abstrahlung ist gut. Die Tourenverhältnisse sind am Morgen in der Höhe mehrheitlich günstig. Mit der tageszeitlichen Erwärmung und der Sonneneinstrahlung steigt die Gefahr von nassen Lawinen im Tagesverlauf an.

Gefahrenstufe 1 - Gering

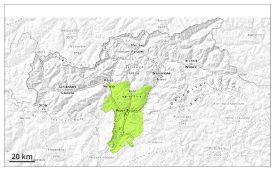

1

Tendenz: Lawinengefahr bleibt gleich
am Freitag, den 17.04.2026

Nassschnee

2000m

Nassschnee beachten.

Es sind nur noch vereinzelt nasse Lawinen möglich. Vorsicht an extrem steilen Schattenhängen. Lawinen sind sehr vereinzelt mittelgroß.

Schneedecke

Gefahrenmuster gm.10: frühjahrssituation | gm.1: bodennahe schwachschicht

Die Schneeoberfläche gefriert kaum und ist schon am Morgen aufgeweicht.

Tendenz

Geringe Lawinengefahr. Nassschnee beachten.