aineva.it

Donnerstag 16.04.2026

Veröffentlicht am 15.04.2026 um 17:00

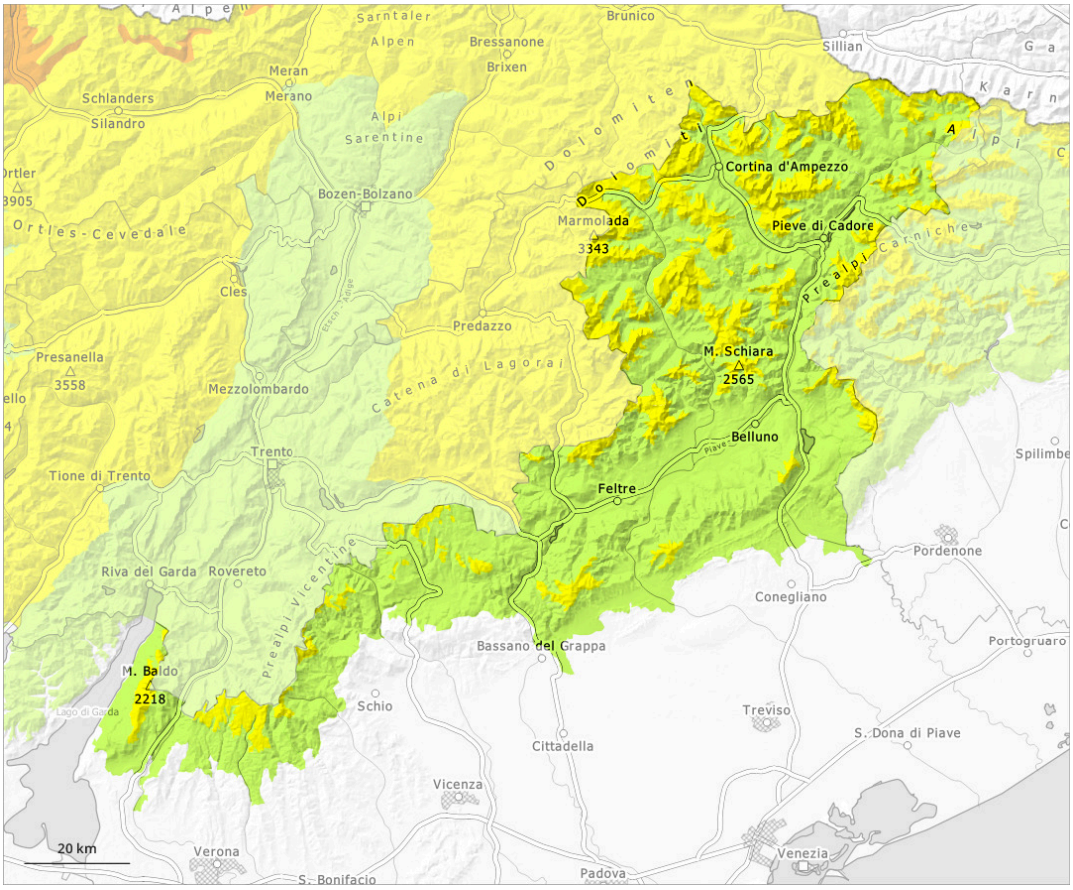

1	2	3	4	5
gering	mäßig	erheblich	groß	sehr groß

Gefahrenstufe 2 - Mäßig

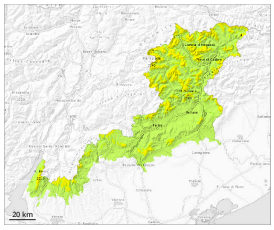

Waldgrenze

Tendenz: Lawinengefahr bleibt gleich
am Freitag, den 17.04.2026

Nassschnee

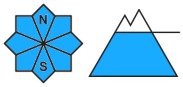

Waldgrenze

Nassschnee

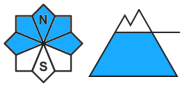

2700m

Triebschnee

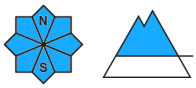

2500m

Vorsicht vor Nassschnee. Mit Erwärmung und Sonneneinstrahlung lokal teils heimtückische Lawinensituation.

Es fielen lokal oberhalb von rund 2600 m bis zu 20 cm Schnee, lokal auch weniger. Es fiel lokal Regen bis auf 2300 m.
Die Gefahrenstellen sind häufig und im Nebel kaum zu erkennen. Die Gefahrenstellen für nasse Lawinen liegen v.a. an Böschungen unterhalb von rund 2500 m. Die nassen Lawinen können vor allem aus noch nicht vollständig entladenen Einzugsgebieten groß werden. Der Neuschnee sollte an allen Expositionen oberhalb von rund 2500 m vorsichtig beurteilt werden. Vor allem an sehr steilen Hängen und an Felswandfüßen und hinter Geländekanten sind kleine und vereinzelt mittlere Lawinen möglich. Besonders gefährlich sind Felswandfüße.
Mit Neuschnee und Wind entstanden besonders oberhalb von rund 2500 m teils störanfällige Triebschneeansammlungen. Die Gefahrenstellen liegen vor allem in Kammlagen, Rinnen und Mulden der Expositionen Nordwest über Nord bis Nordost oberhalb von rund 2500 m. Besonders gefährlich sind Übergänge von wenig zu viel Schnee, wo Schwachstellen im Altschnee vorhanden sind.
Lokaler Anstieg der Gefahr von feuchten und nassen Lawinen.

Schneedecke

Gefahrenmuster gm.3: regen auf schnee | gm.1: bodennahe schwachschicht

In der Schneedecke sind an Nordwest-, Nord- und Nordosthängen heikle Schwachschichten vorhanden. Der Schneeregen führte vor allem an steilen Hängen unterhalb von rund 2200 m verbreitet zu einem Festigkeitsverlust innerhalb der Schneedecke. Der Neuschnee ist oberhalb von rund 2700 m locker. Die Triebschneeansammlungen sind oberhalb von rund 2700 m schlecht mit dem Altschnee verbunden.