ICGC Institut Cartogràfic i Geològic de Catalunya

Servei Meteorològic de Catalunya meteo.cat

Boletín de peligro de aludes para el Pirineo de Catalunya
Del 15/04/2026 al 16/04/2026

(Válido fuera pistas de esquí y zonas no controladas)

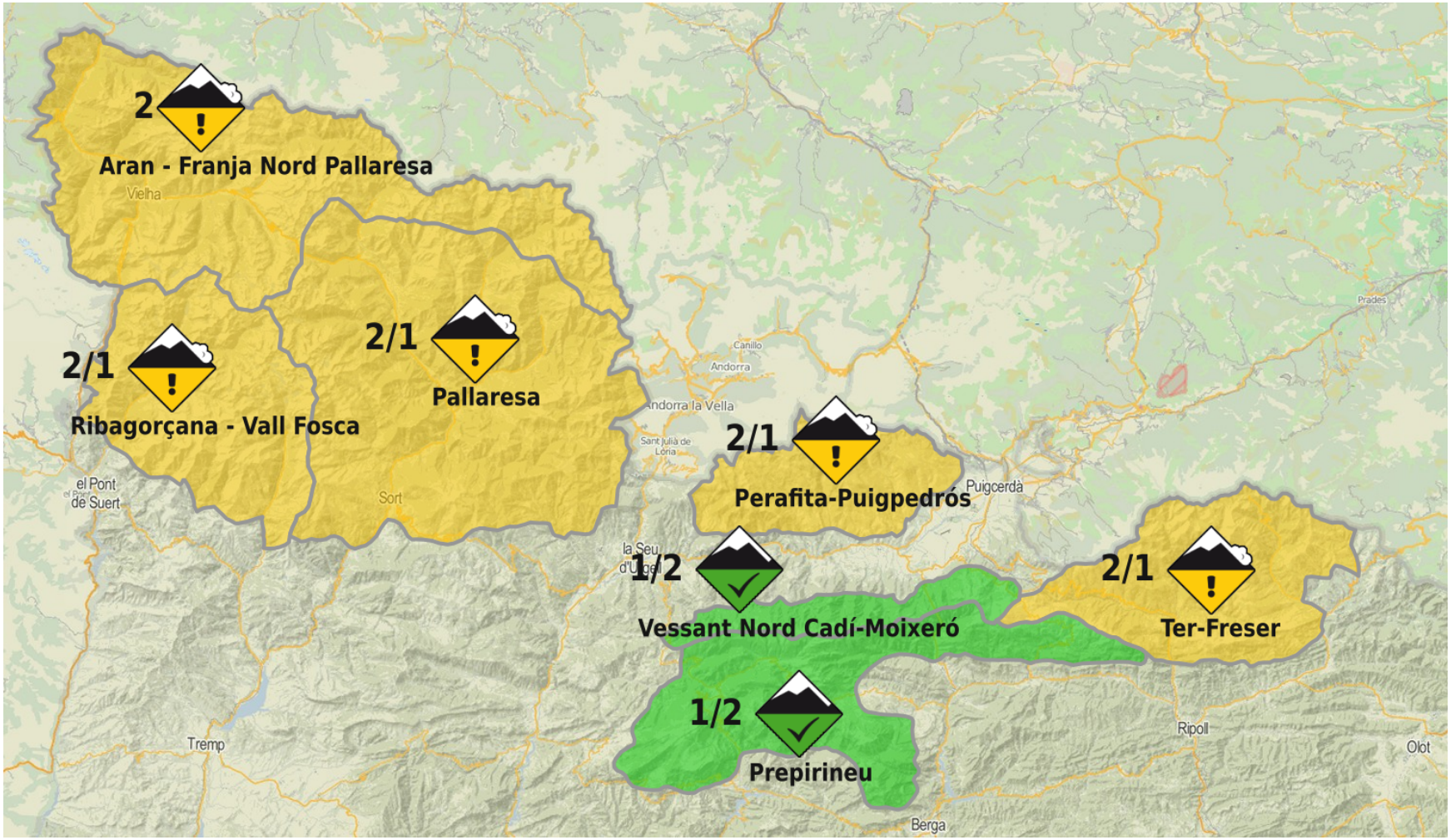

5 MUY FUERTE	4 FUERTE	3 NOTABLE	2 LIMITADO	1 DÉBIL

ICGC Institut Cartogràfic i Geològic de Catalunya

Servei Meteorològic de Catalunya

Boletín de peligro de aludes Aran - Franja Nord Pallaresa Del 15/04/2026 al 16/04/2026

(Válido fuera pistas de esquí y zonas no controladas)

Limitado (2)

Situación primaria

Nieve húmeda

Distribución

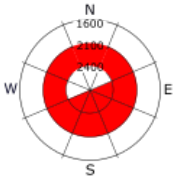

Tamaño

Origen

Tendencia

Situación secundaria

Nieve venteada

Distribución

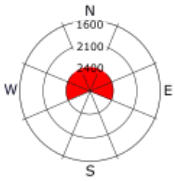

Tamaño

Origen

Tendencia

Estado del manto nivoso

Con la insolación y el ascenso térmico pasamos a una situación de nieve húmeda y de deslizamientos basales, aunque residualmente se mantienen placas de viento en umbrías. Son probables caídas naturales de aludes de fusión, sobretodo junto a puntos oscuros. En sectores herbosos se esperan caídas de deslizamientos basales. Estos aludes son más probables en las solanas por encima los 2200 m y hasta las cimas, pero también en N de cotas medias. Los aludes de fusión serán en general de tamaño 1 (pequeño), pudiendo alcanzar tamaño 2 (capacidad de enterrarnos). Los deslizamientos basales pueden alcanzar fácilmente el tamaño 2. De noche y madrugada puede rehelar favoreciendo ligeramente la estabilidad. Por otra parte, se mantienen placas de viento en las cotas más altas de sectores umbríos o residualmente en E y W muy altas. Las placas previstas serán por lo general de pequeño tamaño sin capacidad para enterrarnos excepto en terreno trampa, donde pueden causarnos daños mayores.

Distribución del manto nivoso

Hay nieve en el suelo con continuidad por encima de 1.800-1.900 m en umbrías y de 2.000 m en solanas. Los espesores a unos 2.200 m rondan los 140-220 cm. Los valores están muy por encima de los normales por la época.

Tendencia para las próximas 48-72h

Condiciones primaverales con posibilidad de chubascos viernes hasta cotas altas en forma de agua, que mantendrán el manto húmedo. Evolución del peligro: SIN CAMBIOS.

El próximo boletín será emitido el día 2026-04-16

5 MUY FUERTE	4 FUERTE	3 NOTABLE	2 LIMITADO	1 DÉBIL

EAWS EUROPEAN AVALANCHE WARNING SERVICES

ICGC Institut Cartogràfic i Geològic de Catalunya

Servei Meteorològic de Catalunya meteo.cat

Boletín de peligro de aludes Ribagorçana - Vall Fosca Del 15/04/2026 al 16/04/2026

(Válido fuera pistas de esquí y zonas no controladas)

Limitado (2) en las horas centrales del día Débil (1) en el resto

Situación primaria

Nieve húmeda

Distribución

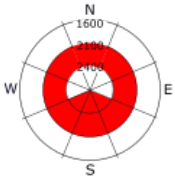

Tamaño

Origen

Tendencia

Situación secundaria

Nieve venteada

Distribución

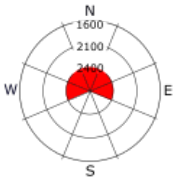

Tamaño

Origen

Tendencia

Estado del manto nivoso

El manto nivoso se transforma fácilmente a nieve húmeda por la insolación y el ascenso térmico. Son probables las caídas naturales de aludes de fusión, sobre todo junto a puntos oscuros como árboles y rocas y especialmente en las horas centrales del día. Estos aludes son más probables en las solanas por encima de los 2200 m y hasta las cimas, pero también en umbrías de cotas medias o que ya les dé el Sol. Serán en general de tamaño 1 (pequeño), puntualmente puede haber alguno que tenga capacidad de enterrarnos (tamaño mediano). Por la noche y madrugada encontraremos un manto rehelado. Habrá que tener cuidado con los resbalones. Por otra parte, se mantienen placas de viento en las cotas más altas de sectores umbríos o residualmente en E y W muy altas. Las placas previstas pueden caer accidentalmente a nuestro paso y serán por lo general de pequeño tamaño sin capacidad para enterrarnos pero muy peligrosas en terreno trampa donde pueden causar daños mayores.

Distribución del manto nivoso

Hay nieve por encima de 1.800-2.000 m pero esquiable en N por encima de 1.900 m y de 2.300 m en S. Se alcanzan los 80-100 cm a unos 2.200 m, con frecuentes deflaciones y acumulaciones por encima del nivel del bosque. Estos valores están ligeramente por debajo de los normales para la época.

Tendencia para las próximas 48-72h

Condiciones primaverales con posibilidad de chubascos viernes hasta cotas altas en forma de agua, que mantendrán el manto húmedo. Evolución del peligro: SIN CAMBIOS.

El próximo boletín será emitido el día 2026-04-16

5 MUY FUERTE	4 FUERTE	3 NOTABLE	2 LIMITADO	1 DÉBIL

EAWS EUROPEAN AVALANCHE WARNING SERVICES

ICGC Institut Cartogràfic i Geològic de Catalunya

meteo.cat Servei Meteorològic de Catalunya

Boletín de peligro de aludes Pallaresa
Del 15/04/2026 al 16/04/2026

(Válido fuera pistas de esquí y zonas no controladas)

Limitado (2) en las horas centrales del día Débil (1) en el resto

Situación primaria

Nieve húmeda

Distribución

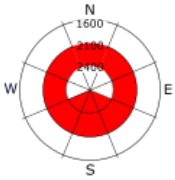

Tamaño

Origen

Tendencia

Situación secundaria

Nieve venteada

Distribución

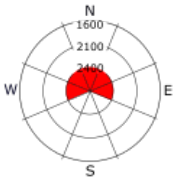

Tamaño

Origen

Tendencia

Estado del manto nivoso

El manto nivoso se transforma fácilmente a nieve húmeda por la insolación y el ascenso térmico. Son probables las caídas naturales de aludes de fusión, sobre todo junto a puntos oscuros como árboles y rocas y especialmente en las horas centrales del día. Estos aludes son más probables en las solanas por encima de los 2200 m y hasta las cimas, pero también en umbrías de cotas medias o que ya les dé el Sol. Serán en general de tamaño 1 (pequeño), puntualmente puede haber alguno que tenga capacidad de enterrarnos (tamaño mediano). Por la noche y madrugada encontraremos un manto rehelado. Habrá que tener cuidado con los resbalones. Por otra parte, se mantienen placas de viento en las cotas más altas de sectores umbríos o residualmente en E y W muy altas. Las placas previstas pueden caer accidentalmente a nuestro paso y serán por lo general de pequeño tamaño sin capacidad para enterrarnos pero muy peligrosas en terreno trampa donde pueden causar daños mayores.

Distribución del manto nivoso

Hay nieve por encima de 1.800-2.000 m pero esquiable en N por encima de 1.900 m y de 2.300 m en S. Se alcanzan los 80-100 cm a unos 2.200 m, con frecuentes deflaciones y acumulaciones por encima del nivel del bosque.

Tendencia para las próximas 48-72h

Condiciones primaverales con posibilidad de chubascos eel viernes hasta cotas altas en forma de agua, que mantendrán el manto húmedo. Evolución del peligro: SIN CAMBIOS.

El próximo boletín será emitido el día 2026-04-16

5 MUY FUERTE	4 FUERTE	3 NOTABLE	2 LIMITADO	1 DÉBIL

EAWS EUROPEAN AVALANCHE WARNING SERVICES

ICGC Institut Cartogràfic i Geològic de Catalunya

Servei Meteorològic de Catalunya

Boletín de peligro de aludes Perafita-Puigpedrós Del 15/04/2026 al 16/04/2026

(Válido fuera pistas de esquí y zonas no controladas)

Limitado (2) en las horas centrales del día Débil (1) en el resto

Situación primaria

Nieve húmeda

Distribución

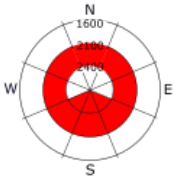

Tamaño

Origen

Tendencia

Situación secundaria

Nieve venteada

Distribución

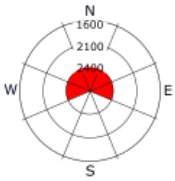

Tamaño

Origen

Tendencia

Estado del manto nivoso

El manto nivoso se transforma fácilmente a nieve húmeda por la insolación y el ascenso térmico. Son probables las caídas naturales de aludes de fusión, sobre todo junto a puntos oscuros como árboles y rocas y especialmente en las horas centrales del día. Estos aludes son más probables en las solanas por encima de los 2200 m y hasta las cimas, pero también en umbrías de cotas medias o que ya les dé el Sol. Serán en general de tamaño 1 (pequeño), puntualmente puede haber algun alud que tenga capacidad de enterrarnos (tamaño mediano). Por la noche y madrugada encontraremos un manto rehelado. Habrá que tener cuidado con los resbalones. Por otra parte, se mantienen placas de viento en las cotas más altas de sectores umbríos o residualmente en E y W muy altas. Las placas previstas pueden caer a nuestro paso y serán por lo general de tamaño pequeño sin capacidad para enterrarnos pero muy peligrosas en terreno trampa donde pueden causar daños mayores.

Distribución del manto nivoso

Hay nieve por encima de 1.800 a 2.000 m. Se alcanzan los 50-90 cm de grosor a unos 2.300 m, con frecuentes deflaciones y acumulaciones por encima del nivel del bosque. Estos valores son los normales para la época.

Tendencia para las próximas 48-72h

Condiciones primaverales con posibilidad de chubascos el viernes hasta cotas altas en forma de agua, que mantendrán el manto húmedo. Evolución del peligro: SIN CAMBIOS.

El próximo boletín será emitido el día 2026-04-16

5 MUY FUERTE	4 FUERTE	3 NOTABLE	2 LIMITADO	1 DÉBIL

EAWS EUROPEAN AVALANCHE WARNING SERVICES

ICGC Institut Cartogràfic i Geològic de Catalunya

Servei Meteorològic de Catalunya

Boletín de peligro de aludes Vessant Nord Cadí-Moixeró Del 15/04/2026 al 16/04/2026

(Válido fuera pistas de esquí y zonas no controladas)

Débil (1) excepto Limitado (2) al mediodía y por encima de 2.000 m.

Situación primaria

Nieve húmeda

Distribución

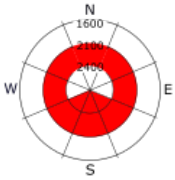

Tamaño

Origen

Tendencia

Situación secundaria

Nieve venteada

Distribución

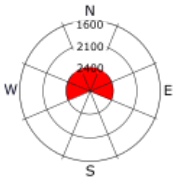

Tamaño

Origen

Tendencia

Estado del manto nivoso

El manto nivoso transforma rápidamente con el ascenso térmico y la insolación. Se prevé que caigan aludes naturales de nieve húmeda, especialmente en las horas centrales del día. Pueden caer fácilmente junto a sectores rocosos soleados y de árboles (puntos oscuros). Serán por lo general de tamaño 1 (pequeño), excepto en terreno trampa como las zonas de canales donde se puede sobre-acumular más espesor. Este problema de nieve húmeda afecta sobre todo a las solanas por encima de los 2200 m y hasta las cimas, pero también en umbrías de cotas medias o que ya les dé el Sol. Por la noche y madrugada encontraremos un manto rehelado. Habrá que tener cuidado con los resbalones. Por otra parte, se mantienen residualmente placas de viento en las cotas más altas de sectores umbrías y en E y W muy altas. Las placas previstas pueden caer a nuestro paso y serán por lo general de tamaño pequeño sin capacidad para enterrarnos pero muy peligrosas en terreno trampa donde pueden causar daños mayores.

Distribución del manto nivoso

Hay nieve por encima de 1.800 m en N y de 2.000 m en S. Prácticamente no han variado los grosores de nieve en el suelo. Alcanzan los 130-150 cm a unos 2.200 m, con frecuentes deflaciones y acumulaciones por encima del nivel del bosque. Estos valores están muy por encima de los normales para la época.

Tendencia para las próximas 48-72h

Condiciones primaverales con posibilidad de chubascos el viernes hasta cotas altas en forma de agua, que mantendrán el manto húmedo. Evolución del peligro: SIN CAMBIOS.

El próximo boletín será emitido el día 2026-04-16

5 MUY FUERTE	4 FUERTE	3 NOTABLE	2 LIMITADO	1 DÉBIL

EAWS EUROPEAN AVALANCHE WARNING SERVICES

ICGC Institut Cartogràfic i Geològic de Catalunya

meteo.cat Servei Meteorològic de Catalunya

Boletín de peligro de aludes Prepirineu
Del 15/04/2026 al 16/04/2026

(Válido fuera pistas de esquí y zonas no controladas)

Débil (1) excepto Limitado (2) en las horas centrales del día por encima de 2.200 m

Situación primaria

Nieve húmeda

Distribución

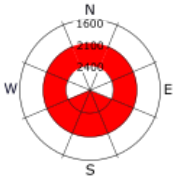

Tamaño

Origen

Tendencia

Situación secundaria

Nieve venteada

Distribución

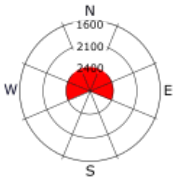

Tamaño

Origen

Tendencia

Estado del manto nivoso

El manto nivoso transforma rápidamente con el ascenso térmico y la insolación. Se prevé que caigan aludes de nieve húmeda, de forma natural, especialmente en las horas centrales del día. Pueden caer fácilmente junto a sectores rocosos soleados y de árboles (puntos oscuros). Serán por lo general de tamaño 1 (pequeño), excepto en terreno trampa donde se puede sobre-acumular más espesor. Este problema de nieve húmeda afecta sobre todo a las solanas por encima de los 2200 m y hasta las cimas, pero también a umbrías de cotas medias o que ya les dé el Sol. Por la noche y madrugada encontraremos un manto rehelado. Habrá que tener cuidado con los resbalones. Por otra parte, se mantienen residualmente placas de viento en las cotas más altas de sectores umbrías y en E y W muy altas. Las placas previstas pueden caer a nuestro paso y serán por lo general de tamaño pequeño sin capacidad para enterrarnos pero muy peligrosas en terreno trampa donde pueden causar daños mayores.

Distribución del manto nivoso

Hay nieve por encima de 1.900 m en N y de 2.000-2.100 m en S. Se alcanzan los 60-80 cm a unos 2.200 m, con frecuentes deflaciones y acumulaciones por encima del nivel del bosque.

Tendencia para las próximas 48-72h

Condiciones primaverales con posibilidad de chubascos el viernes hasta cotas altas en forma de agua, que mantendrán el manto húmedo. Evolución del peligro: SIN CAMBIOS.

El próximo boletín será emitido el día 2026-04-16

5 MUY FUERTE	4 FUERTE	3 NOTABLE	2 LIMITADO	1 DÉBIL

EAWS EUROPEAN AVALANCHE WARNING SERVICES

ICGC Institut Cartogràfic i Geològic de Catalunya

Servei Meteorològic de Catalunya meteo.cat

Boletín de peligro de aludes Ter-Freser
Del 15/04/2026 al 16/04/2026

(Válido fuera pistas de esquí y zonas no controladas)

LIMITADO (2) en las horas centrales del día DÉBIL (1) en el resto.

Situación primaria

Nieve húmeda

Distribución

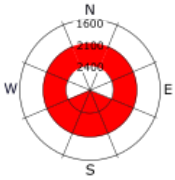

Tamaño

Origen

Tendencia

Situación secundaria

Nieve venteada

Distribución

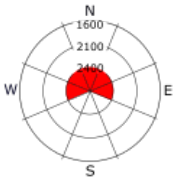

Tamaño

Origen

Tendencia

Estado del manto nivoso

El manto se transforma fácilmente a nieve húmeda por la insolación y el ascenso térmico. Son probables caídas naturales de aludes de fusión, sobre todo junto a puntos oscuros como árboles y rocas, especialmente en horas centrales del día. Estos aludes son más probables en las solanas por encima de 2200 m hasta las cimas, pero también en umbrías de cotas medias o que ya les dé el Sol. Serán en general de tamaño 1 (pequeño), puntualmente puede haber alguna que tenga capacidad de enterrarnos (tamaño mediano). Por la noche y madrugada encontraremos un manto rehelado. Habrá que tener cuidado con los resbalones. Por otra parte, se mantienen placas de viento en las cotas altas de sectores umbríos o residualmente en E y W muy altas. Cerca del sector ha habido algún desencadenamiento accidental. Las placas previstas pueden caer a nuestro paso y serán por lo general de pequeño tamaño sin capacidad para enterrarnos pero muy peligrosas en terreno trampa donde pueden causar daños mayores.

Distribución del manto nivoso

Hay nieve por encima de 1.800 m en N y de 1.900 m en S. Los espesores rondan los 50-80 cm a unos 2.200 m, y más de 130-190 cm por encima de 2.400 m, con frecuentes deflaciones y acumulaciones por encima del nivel del bosque. Estos valores están por encima de la media para la época

Tendencia para las próximas 48-72h

Condiciones primaverales con posibilidad de chubascos el viernes hasta cotas altas en forma de agua, que mantendrán el manto húmedo. Evolución del peligro: SIN CAMBIOS.

El próximo boletín será emitido el día 2026-04-16

5 MUY FUERTE	4 FUERTE	3 NOTABLE	2 LIMITADO	1 DÉBIL

EAWS EUROPEAN AVALANCHE WARNING SERVICES