BUTLLETÍ DEL PERILL D'ALLAUS DEL PRINCIPAT D'ANDORRA

Elaborat el 15/04/2026 16:00
Propera actualització 16/04/2026 a les 16h

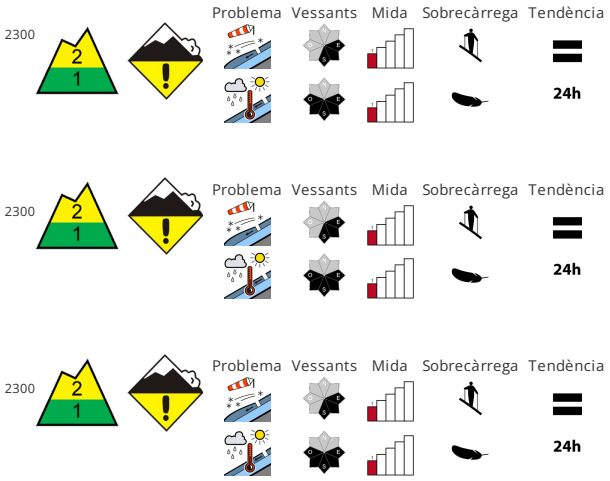

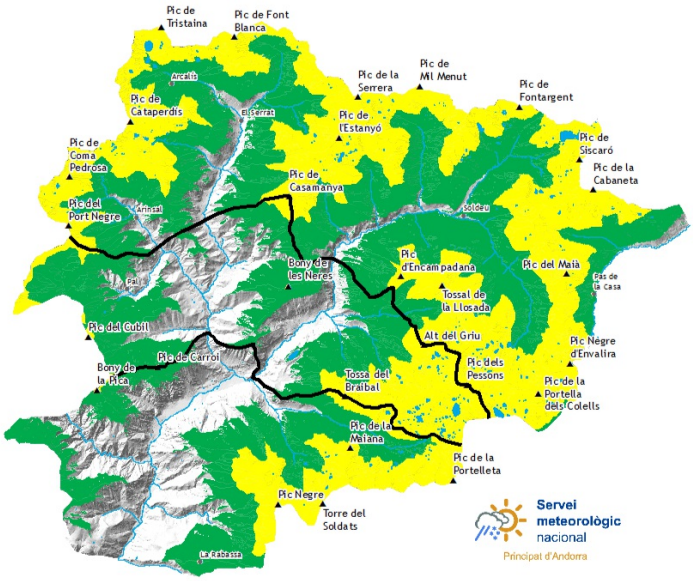

ESTABILITAT DEL MANTELL NIVAL

Les plaques de vent de mida més aviat petita representen la principal font de perill. Aquestes són en alguns casos gruixudes i en alguns casos poden desencadenar-se fàcilment sobretot als seus marges. Amb l'augment de la temperatura diürna i la radiació solar, són probables purgues i allaus de neu humida. Les allaus poden desencadenar-se de manera natural i, de manera aïllada, atènyer mida mitjana. A més, són possibles algunes allaus de lliscament basal. Els indrets perillosos són fàcils de reconèixer.

QUALITAT DE LA NEU

El refredament nocturn serà bo. A causa de la crosta de gel hi ha el perill de relliscar i caure fins i tot en vessants moderadament inclinats. Els gruixos de neu varien molt per la influència del vent. En el transcurs de la jornada la radiació solar causarà una progressiva humidificació del mantell de neu als vessants assolellats. Evitar les zones amb esquerdes de lliscament basal.

GRUIXOS DEL MANTELL NIVAL FORA DE PISTA

Zona nord		Gruix neu		
Mantell Nival		1500m	2000m	2500m
N	1600 m	0 cm	150 cm	250 cm
S	1800 m	0 cm	100 cm	180 cm

Zona centre		Gruix neu		
Mantell Nival		1500m	2000m	2500m
N	1600 m	0 cm	120 cm	160 cm
S	1800 m	0 cm	60 cm	120 cm

Zona sud		Gruix neu		
Mantell Nival		1500m	2000m	2500m
N	1600 m	0 cm	120 cm	160 cm
S	1800 m	0 cm	60 cm	120 cm

Govern d'Andorra

Aquest butlletí ha estat elaborat seguint les normes i recomanacions de l'**European Avalanche Warning Services**, del qual el **Servei meteorològic Nacional** n'és membre

BUTLLETÍ DEL PERILL D'ALLAUS DEL PRINCIPAT D'ANDORRA

Servei meteorològic nacional
Principat d'Andorra

Informació detallada per espais naturals protegits

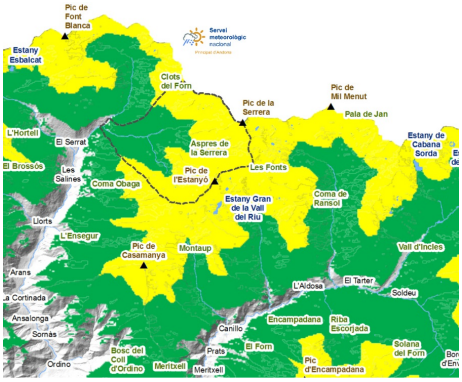

SORTENY

El sol va humidificant progressivament la neu als vessants sud, però als nord encara es manté freda. A cotes baixes el vent ha deixat a la vista la neu vella tacada pel fang de la pluja de diumenge al matí i aquesta s´ha regelat. Les pujades són tècniques a cotes mitges a causa del gel. A cotes altes, es recomana evitar les acumulacions de neu ventada i circular per la neu més dura i marró.

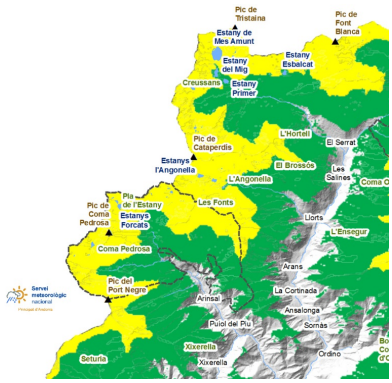

COMAPEDROSA

La neu s´humidificarà als vessants sud i cotes baixes, però al matí la trobarem ben dura. Als vessants més inclinats baixaran purgues de neu humida. A primera hora, amb la neu encara dura serà més difícil i tècnic circular per cotes mitges que per les cotes altes, on hi ha més neu recent.

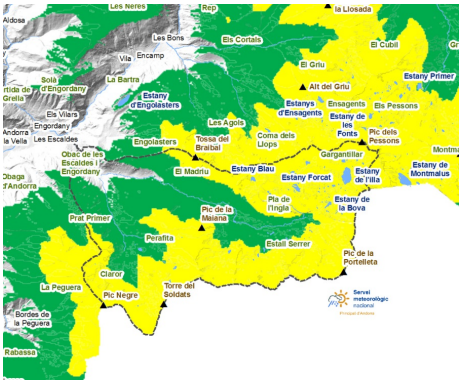

MADRIU-PERAFITA-CLAROR

El sol estabilitzarà el mantell amb la seva compactació, però durant el dia esperem purgues als vessants sud. Serà més segur circular per la neu marró i dura per evitar les plaques de vent.

Govern d'Andorra

EAWS
EUROPEAN AVALANCHE WARNING SERVICES

Aquest butlletí ha estat elaborat seguint les normes i recomanacions de l'**European Avalanche Warning Services**, del qual el **Servei meteorològic Nacional** n'és membre

BUTLLETÍ DEL PERILL D'ALLAUS DEL PRINCIPAT D'ANDORRA

Servei meteorològic nacional
Principat d'Andorra

Gruixos de neu nova dels darrers dies (de les últimes 24h mesurat a les 06:00h UTC)

	11/04/2026	12/04/2026	13/04/2026	14/04/2026
FEDA (Central)	0 cm	0 cm	0 cm	0 cm
Engolasters - FEDA	0 cm	0 cm	0 cm	0 cm
Bony de les Neres	0 cm	4 cm	0 cm	0 cm
Sorteny	0 cm	0 cm	0 cm	0 cm
Les Fonts d'Arinsal	0 cm	11 cm	0 cm	0 cm
Aixàs	0 cm	0 cm	0 cm	0 cm
Perafita	0 cm	10 cm	0 cm	0 cm
Tossa Espiolets	0 cm	8 cm	1 cm	0 cm
Grau Roig - FEDA	0 cm	3 cm	2 cm	0 cm
Fontverd	0 cm	4 cm	0 cm	0 cm
Coll Ordino	0 cm	2 cm	0 cm	0 cm
Ransol - FEDA	0 cm	0 cm	0 cm	0 cm
Setúria	0 cm	5 cm	0 cm	0 cm
Caborreu	0 cm	0 cm	0 cm	0 cm
La Solana	0 cm	10 cm	4 cm	0 cm
Coll Pa	0 cm	17 cm	0 cm	0 cm
Envalira Antenes	0 cm	0 cm	1 cm	0 cm
Vall del Riu FEDA	0 cm	0 cm	0 cm	0 cm