BUTLLETÍ DEL PERILL D'ALLAUS DEL PRINCIPAT D'ANDORRA

Elaborado el 15/04/2026 16:00
Proxima actualización 16/04/2026 a las 16h

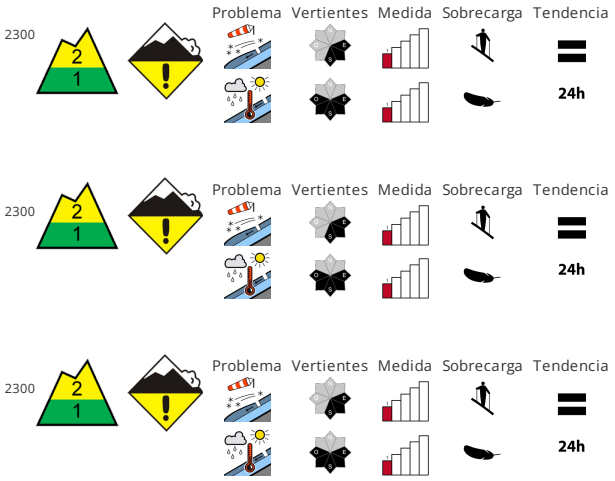

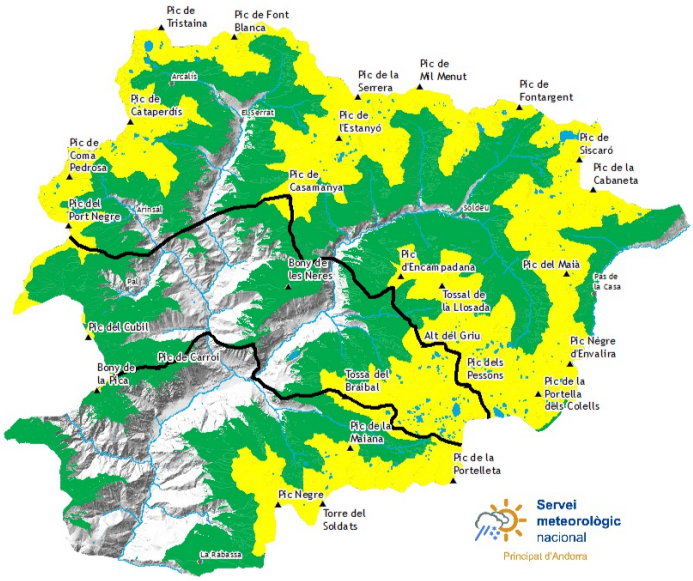

CALIDAD DE LA NIEVE

Las placas de viento de tamaño más bien pequeño representan la principal fuente de peligro. Estas en algunos casos son gruesas y en algunos casos pueden desencadenarse fácilmente sobre todo en los márgenes. Con la subida de la temperatura diurna y la radiación solar, son probables purgas y avalanchas de nieve húmeda. Los aludes pueden desencadenarse de manera natural y, de manera aislada, alcanzar un tamaño mediano. Además son posibles algunos aludes de deslizamiento basal. Los lugares peligrosos son resultan fáciles de reconocer.

ESTABILIDAD DEL MANTO NIVOSO

El enfriamiento nocturno será bueno. Debido a la costra de hielo hay el peligro de resbalar y caer incluso en laderas moderadamente inclinadas. Los espesores de nieve varían mucho por la influencia del viento. En el transcurso de la jornada la radiación solar causará una progresiva humidificación del manto de nieve en las laderas solanas. Evitar las zonas con grietas de deslizamiento basal.

ESPESORES DEL MANTO NIVOSO FUERA DE PISTA

Zona norte		Espesor nieve		
Manto Nival		1500m	2000m	2500m
N	1600 m	0 cm	150 cm	250 cm
S	1800 m	0 cm	100 cm	180 cm

zona centro		Espesor nieve		
Manto Nival		1500m	2000m	2500m
N	1600 m	0 cm	120 cm	160 cm
S	1800 m	0 cm	60 cm	120 cm

Zona sur		Espesor nieve		
Manto Nival		1500m	2000m	2500m
N	1600 m	0 cm	120 cm	160 cm
S	1800 m	0 cm	60 cm	120 cm

Govern d'Andorra

Aquest butlletí ha estat elaborat seguint les normes i recomanacions de l'**European Avalanche Warning Services**, del qual el **Servei meteorològic Nacional** n'és membre

BUTLLETÍ DEL PERILL D'ALLAUS DEL PRINCIPAT D'ANDORRA

Servei meteorològic nacional
Principat d'Andorra

Información detallada por espacios naturales protegidos

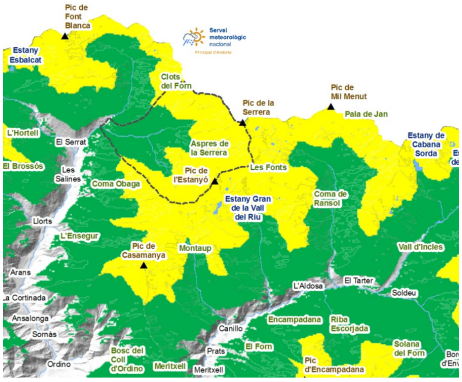

SORTENY

El sol va humidificando progresivamente la nieve en las vertientes sur, pero en el norte todavía se mantiene fría. En cotas bajas el viento ha dejado a la vista la nieve vieja manchada por el barro de la lluvia del domingo por la mañana y ésta se ha rehelado. Las subidas son técnicas en cotas medias a causa del hielo. En cotas altas, se recomienda evitar las acumulaciones de nieve venteada y circular por la nieve más dura y marrón.

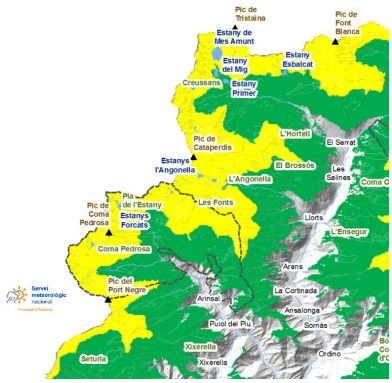

COMAPEDROSA

La nieve se humidificará en las vertientes sur y cotas bajas, pero por la mañana la encontraremos muy dura. En las vertientes más inclinadas bajarán purgas de nieve húmeda. A primera hora, con la nieve todavía dura será más difícil y técnico circular por cotas medias que por las cotas altas, en las que hay más nieve reciente.

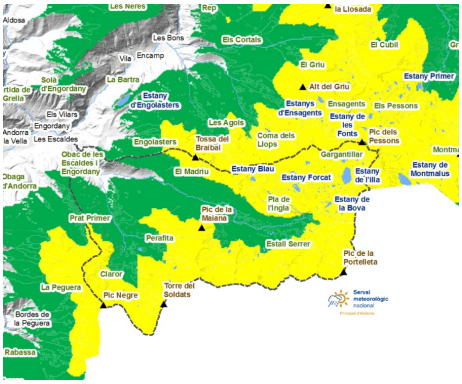

MADRIU-PERAFITA-CLAROR

El sol estabilizará el manto con su compactación, pero durante el día esperamos purgas en las vertientes sur. Será más seguro circular por la nieve parda y dura para evitar las placas de viento.

Govern d'Andorra

EAWS
EUROPEAN AVALANCHE WARNING SERVICES

Aquest butlletí ha estat elaborat seguint les normes i recomanacions de l'**European Avalanche Warning Services**, del qual el **Servei meteorològic Nacional** n'és membre

BUTLLETÍ DEL PERILL D'ALLAUS DEL PRINCIPAT D'ANDORRA

Servei meteorològic nacional
Principat d'Andorra

Espesores de nieve nueva de los últimos días (de las ultimas 24h mesurado a las 06:00h UTC)

	11/04/2026	12/04/2026	13/04/2026	14/04/2026
FEDA (Central)	0 cm	0 cm	0 cm	0 cm
Engolasters - FEDA	0 cm	0 cm	0 cm	0 cm
Bony de les Neres	0 cm	4 cm	0 cm	0 cm
Sorteny	0 cm	0 cm	0 cm	0 cm
Les Fonts d'Arinsal	0 cm	11 cm	0 cm	0 cm
Aixàs	0 cm	0 cm	0 cm	0 cm
Perafita	0 cm	10 cm	0 cm	0 cm
Tossa Espiolets	0 cm	8 cm	1 cm	0 cm
Grau Roig - FEDA	0 cm	3 cm	2 cm	0 cm
Fontverd	0 cm	4 cm	0 cm	0 cm
Coll Ordino	0 cm	2 cm	0 cm	0 cm
Ransol - FEDA	0 cm	0 cm	0 cm	0 cm
Setúria	0 cm	5 cm	0 cm	0 cm
Caborreu	0 cm	0 cm	0 cm	0 cm
La Solana	0 cm	10 cm	4 cm	0 cm
Coll Pa	0 cm	17 cm	0 cm	0 cm
Envalira Antenes	0 cm	0 cm	1 cm	0 cm
Vall del Riu FEDA	0 cm	0 cm	0 cm	0 cm