MINISTERO DELLA DIFESA

meteomont Servizio Nazionale di previsione neve e valanghe

EAWS EUROPEAN AVALANCHE WARNING SERVICES

CARABINIERI

In collaborazione con: arpav

# PREALPI

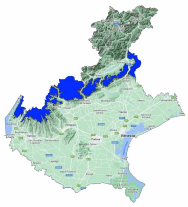

Bollettino Valanghe N. 402/2026 del 15/04/2026 ore 14.00
Validità 48 ore prossima emissione 16/04/2026

**A cura del Servizio METEOMONT dell'ARMA dei CARABINIERI**
**In collaborazione con Servizio Meteorologico dell'Aeronautica militare**

## SITUAZIONE alle 14:00 del 15/04/2026

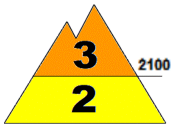


**SITUAZIONE TIPO: strato debole persistente basale.**




**SITUAZIONE TIPO: pioggia su neve.**

| | Nord | Sud |
|---|---|---|
| *Quota neve (mslm)* | *1500 - 1900* | *1700 - 2200* |

| | Neve al suolo | Neve Fresca | Quota (mslm) |
|---|---|---|---|
| *Altezza Neve (cm)* | *095* | *000* | *1680* |
| | *095* | *000* | *1680* |

**VALANGHE OSSERVATE: -.**

## PREVISIONI 16/04/2026

# GRADO DI PERICOLO: MARCATO 3

## SITUAZIONE TIPO: strato debole persistente basale.

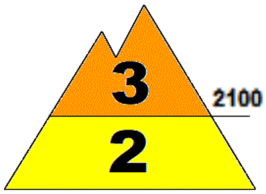


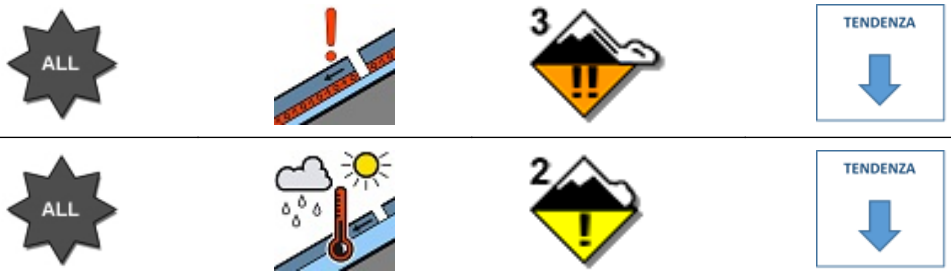


## SITUAZIONE TIPO: pioggia su neve.

**MANTO NEVOSO: La stabilità del manto nevoso è molto scarsa su alcuni punti (aree) per tutte le esposizioni al di sopra di 2100 mslm, possibili valanghe di dimensioni medie.**
**La stabilità del manto nevoso è scarsa su pochi punti (aree) per tutte le esposizioni al di sotto di 2100 mslm, possibili valanghe di dimensioni medie.**

## AVVERTENZE

In considerazione delle avverse condizioni meteorologiche in atto, le attività al di fuori delle piste battute e segnalate sono sconsigliate.

## SCALA EUROPEA DEL GRADO DI PERICOLO VALANGHE

## LEGENDA PROBLEMA

**Bollettino realizzato su scala sinottica-regionale (standard EAWS). La sua valutazione non può escludere in alcun modo la necessità di una seria e capace valutazione locale del pericolo (singolo pendio) che può essere anche sensibilmente diverso. Le previsioni meteorologiche sono relative all'orario UTC (per l'Italia +1 in inverno e +2 in estate).**

**Bollettino sottoposto a processi di: Acquisizione e controllo del C-Sifa e della rete di Osservatori e Esperti - Validazione del Previsore di turno - Certificazione della Sezione Meteomont.**

MINISTERO DELLA DIFESA

meteomont
Servizio Nazionale di previsione neve e valanghe

EAWS EUROPEAN AVALANCHE WARNING SERVICES

CARABINIERI

In collaborazione con: arpav

# PREALPI

## PREVISIONE METEO

| Quota | | 16/04/2026 h6:00 | 16/04/2026 h12:00 | 16/04/2026 h18:00 |
|---|---|---|---|---|
| 1000 | Venti | 02 Nodi da N-Est | 01 Nodi da Sud | 01 Nodi da S-Est |
| | Temperature | +10 °C | +14 °C | +13 °C |
| | Temp.percepita | 10 °C | 14 °C | 13 °C |
| 2000 | Venti | 02 Nodi da N-Est | 01 Nodi da Sud | 01 Nodi da Est |
| | Temperature | +05 °C | +06 °C | +07 °C |
| | Temp.percepita | 5 °C | 6 °C | 7 °C |
| 3000 | Venti | 01 Nodi da Nord | 02 Nodi da Nord | 02 Nodi da N-Est |
| | Temperature | -02 °C | -01 °C | -01 °C |
| | Temp.percepita | -2 °C | -1 °C | -1 °C |
| Zero termico | | 2500-2700 m. | 2700-2900 m. | 2800-3000 m. |
| Fenomeno | | — | | — |
| Stato del cielo | | | | |

## LEGENDA FENOMENI

Assenza Fenomeni · Nebbia · Foschia · Pioggia debole · Pioggia moderata · Pioggia forte · Temporali

Nevicata debole · Nevicata moderata · Nevicata forte

## STATO DEL CIELO

Sereno · Poco nuvoloso · Nuvoloso · Molto nuvoloso · Coperto

## Parametri meteonivometrici registrati presso i campi di rilevamento il 15/04/2026.

| Località | Comune | Quota (m.s.l.m.) | Altezza neve (cm) | Neve caduta nelle 24 ore (cm) | Temp. Min (°C) | Temp. Max (°C) | Condizioni del tempo |
|---|---|---|---|---|---|---|---|
| PIAN CANSIGLIO | Tambre (BL) | 1025 | 0 | 0 | +6 | +11 | Pioggia debole intermittente |
| GALLIO - BUSA FONDA | Gallio (VI) | 1460 | 0 | 0 | +3 | +9 | Assenza di precipitazioni |

(*) Rilievi fuori campo

**L'INFORMAZIONE E' PREVENZIONE - LEGGI L'ATTUALE GRADO DI PERICOLO VALANGHE!**

**IL CAPO DEL CENTRO NAZIONALE METEOMONT**
**(Ten. Col. RFI Emanuela Gini)**
**FIRMA AUTOGRAFA OMESSA AI SENSI**
**DELL'ART.3 DEL D.LGS N.39/1993**

Bollettino realizzato su scala sinottica-regionale (standard EAWS). La sua valutazione non può escludere in alcun modo la necessità di una seria e capace valutazione locale del pericolo (singolo pendio) che può essere anche sensibilmente diverso. Le previsioni meteorologiche sono relative all'orario UTC (per l'Italia +1 in inverno e +2 in estate).