RÉPUBLIQUE FRANÇAISE
Liberté Égalité Fraternité

METEO FRANCE
À VOS CÔTÉS, DANS UN CLIMAT QUI CHANGE

Bulletin d'estimation du risque d'avalanche
(valable en dehors des pistes balisées et ouvertes)
MASSIF : Beaufortain

Rédigé le mercredi 15 avril 2026 à 16h

Estimation des risques pour le : JEUDI 16 AVRIL

POURSUITE DE L'HUMIDIFICATION SOUS L'EFFET DU SOLEIL.

2

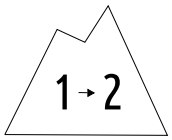

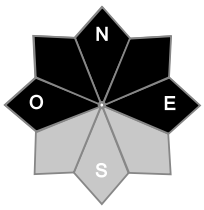

Indice de risque faible évoluant en limité.

Départs spontanés : rares départs en neige humide.

Déclenchements provoqués : petites coulées sous les skis dans la neige fortement humidifiée (pourrie).

Indices de risque : 5 très fort - 4 fort - 3 marqué - 2 limité - 1 faible -- En noir : les pentes les plus dangereuses

Stabilité du manteau neigeux

Situation avalancheuse typique : neige humide avalanches de fond

Départs spontanés : - Mer de nuages vers 2000 m la nuit jusqu'au matin : au dessus bon regel par ciel clair, risque réduit. Pas de regel dans les nuages, rares départs en neige humide, petite avalanche.
- **rares départs en neige humide** qui **suivent la course du soleil**, d'abord en versants NE, Est et ensuite Ouest et NO. Petites à moyennes avalanches.
Exceptionnellement, une cassure linéaire plus volumineuse peut partir si l'humidification atteint pour la première fois une couche fragile enfouie.
- **Rares avalanches de glissement** (plaques de fond) à toute heure sur terrains propices, notamment en Nord sous 2500/2600 m. Taille 2.

Déclenchements provoqués : avalanche de neige humide (pourrie) sous les skis en coupant une pente trop humidifiée au fil des heures.

Autres : chutes de corniches possibles.

Qualité de la neige

Enneigement : l'enneigement est revenu au niveau des normales suite à la chaleur des derniers jours, le chauffage et la présence des nuages accélèrent la fonte.

Limite skiable : vers 1300/1400 m en Nord, 1600/1700 m en Sud.

Qualité de la neige : La nuit et le matin sous la mer de nuages, pas de regel et neige pourrie.
Au dessus de la mer de nuages, bon regel et neige croûtée le matin, moquette au soleil devenant profondément pourrie après avoir trop chauffé. En secteur nord la neige devient collante après quelques heures.

Aperçu météo pour le jeudi 16 avril

	nuit	matin	après-midi	soir

Mer de nuages en vallée et ciel clair au dessus le matin, des cumulus de beau temps se développent en journée, températures en hausse.

Pluie-Neige				
Iso 0 °C	2 800 m	3 100 m	3 100 m	3 100 m
Vent 2000 m	↘ 5 km/h	↘ 10 km/h	↘ 15 km/h	↗ 5 km/h
Vent 3000 m	↓ 10 km/h	↓ 10 km/h	↘ 15 km/h	↗ 10 km/h

Épaisseur de neige hors-piste

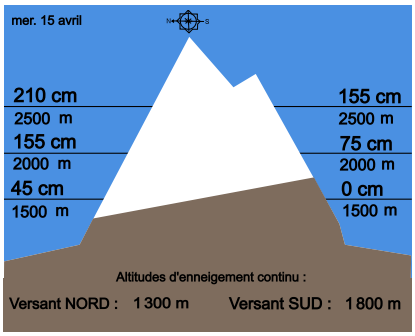

Précipitations à 1800 m

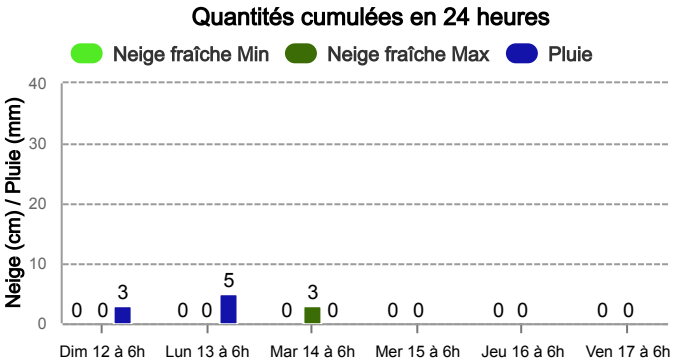

Tendance du vendredi 17 avril

2

Indice de risque limité

Toujours ensoleillé et trop doux, maintient l'activité en neige humide, risque faible évoluant en risque limité, stationnaire.

Pour consulter la vigilance en cours, veuillez vous rendre sur le site https://vigilance.meteofrance.fr/fr

Météo-France - 73 avenue de Paris, 94165 Saint-Mandé cedex - Contact : contact@meteo.fr

Rédigé par Météo-France avec la contribution des observateurs du réseau nivo-météorologiques. Partenariat : ANMSM (Maires de Stations de Montagne), DSF (Domaines Skiables de France), ADSP (Directeurs de Pistes et de la Sécurité des Stations de Sports d'Hiver) et autres acteurs de la montagne.

Bulletin neige & avalanches par téléphone au
0 892 68 10 20 Service 0,35 € / min + prix appel

RÉPUBLIQUE FRANÇAISE
Liberté Égalité Fraternité

METEO FRANCE
À VOS CÔTÉS, DANS UN CLIMAT QUI CHANGE

Bulletin d'estimation du risque d'avalanche
(valable en dehors des pistes balisées et ouvertes)
MASSIF : Beaufortain

Rédigé le mercredi 15 avril 2026 à 16h

Conditions nivo-météo des 7 derniers jours

	jeu. 09/04				ven. 10/04				sam. 11/04				dim. 12/04				lun. 13/04				mar. 14/04				mer. 15/04			
	03h	09h	15h	21h	03h	09h	15h	21h	03h	09h	15h	21h	03h	09h	15h	21h	03h	09h	15h	21h	03h	09h	15h	21h	03h	09h	15h	21h
Météo																												
Vent (km/h)	10	20	30	15	15	20	30	20	15	20	25	25	25	30	35	35	30	30	30	20	15	20	20	10	10	10	15	10
à 3000m																												
Vent (km/h)	5	15	25	10	10	15	25	10	10	10	15	15	15	15	20	20	20	25	25	10	10	15	15	5	5	10	15	5
à 2000m																												

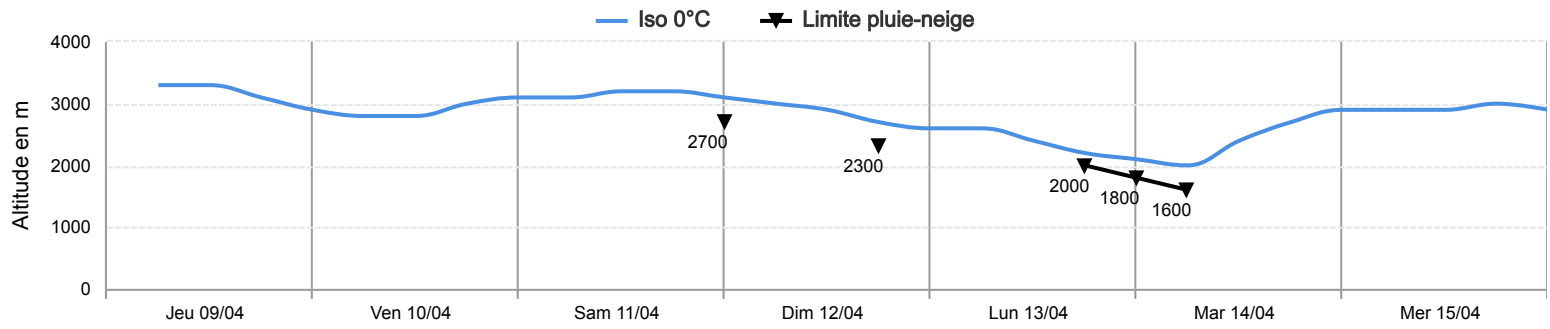

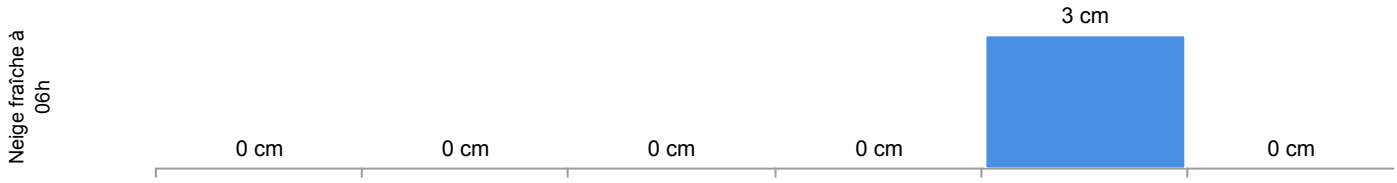

Risque d'avalanche	jeu. 09/04	ven. 10/04	sam. 11/04	dim. 12/04	lun. 13/04	mar. 14/04	mer. 15/04
	2	2	2	2	2	2	2

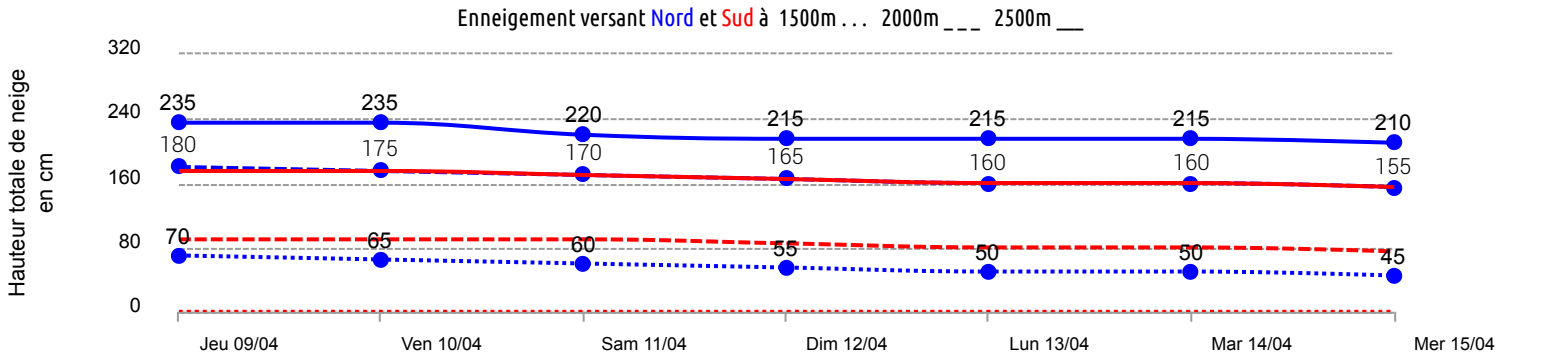

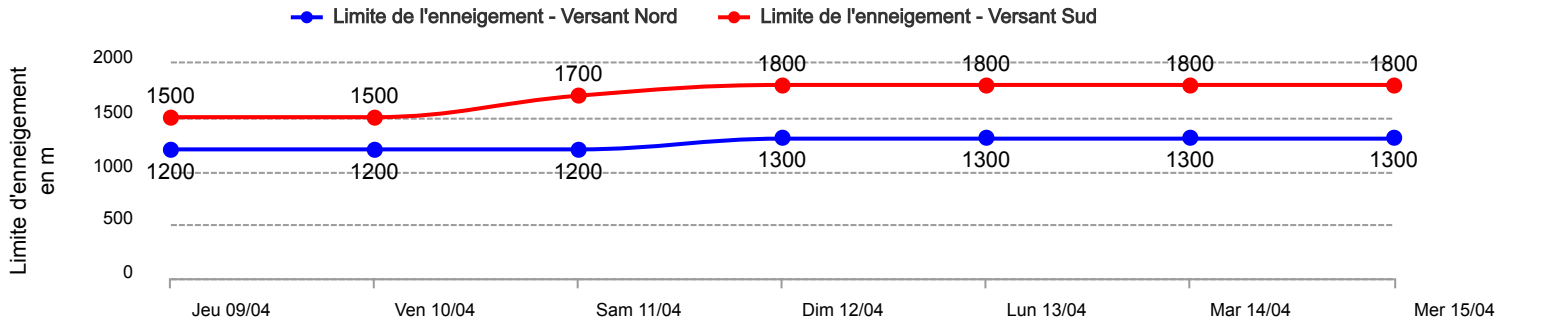

Pour consulter la vigilance en cours, veuillez vous rendre sur le site https://vigilance.meteofrance.fr/fr

Météo-France - 73 avenue de Paris, 94165 Saint-Mandé cedex - Contact : contact@meteo.fr

Bulletin neige & avalanches par téléphone au
0 892 68 10 20 Service 0,35 € / min + prix appel

Rédigé par Météo-France avec la contribution des observateurs du réseau nivo-météorologiques. Partenariat : ANMSM (Maires de Stations de Montagne), DSF (Domaines Skiables de France), ADSP (Directeurs de Pistes et de la Sécurité des Stations de Sports d'Hiver) et autres acteurs de la montagne.