# Bulletin d'estimation du risque d'avalanche

(valable en dehors des pistes balisées et ouvertes)

# MASSIF : Cerdagne Canigou

Rédigé le mercredi 15 avril 2026 à 16h

## Estimation des risques pour le : JEUDI 16 AVRIL

**REPRISE DE L'ACTIVITÉ EN NEIGE HUMIDE AVEC L'ENSOLEILLEMENT, RARES PLAQUES EN ALTITUDE.**

2

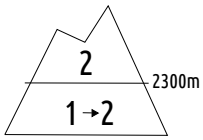


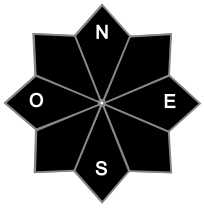


Au-dessus de 2300m indice de risque limité, plus bas indice faible évoluant en limité.

**Départs spontanés :** Départs plutôt ponctuels en neige humide

**Déclenchements provoqués :** Persistance de rares plaques en altitude

Indices de risque : 5 très fort - 4 fort - 3 marqué - 2 limité - 1 faible -- En noir : les pentes les plus dangereuses

## Stabilité du manteau neigeux

**Situation avalancheuse typique :** neige humide neige ventée

**Départs spontanés :**

- Peu probable en début de journée grâce à un regel efficace. Au fil de la journée, dans les pentes ensoleillées, des départs spontanés d'avalanches de taille petite à moyenne sont attendus avec la douceur et l'ensoleillement. Ces départs emportent la neige récente, et dans de rares cas des couches plus anciennes avec une éventuelle avalanche de moyenne, voire grande taille.
- Des reptations peuvent également être présentes, signes avant-coureurs de potentielles avalanches de glissement emportant l'ensemble du manteau neigeux.

**Déclenchements provoqués :**

- Avalanches de plaques, encore déclenchables par un pratiquant, plutôt au-dessus de 2300/2400m. Des accumulations en neige récente non encore humidifiée subsistent par endroits, plutôt à proximité des crêtes et dans les secteurs ombragés. Ces plaques peu épaisses et plus ou moins friables se sont formées ces derniers jours avec le vent de nord. Les accumulations de neige ventée reposent sur une couche de neige tombée sans vent. *Observables : signe de transport de neige par le vent avec de la neige de surface changeante, fissures devant les skis.*
- Par ailleurs, dans les secteurs en neige humide, un skieur coupant une pente raide pourra également déclencher une coulée sous ses skis.

**Autre :** Des corniches, parfois imposantes, sont en place et sont susceptibles de céder spontanément.

## Qualité de la neige

**Enneigement :**

Excellent enneigement pour avril, parmi les plus importants des 30 dernières années. Avec le redoux et le soleil, la limite skiable remonte progressivement (1600/1700 m en nord, et 1900/2000 m en sud). L'épaisseur de neige est rapidement conséquente avec par exemple 176 cm à 2160 m à la station du Canigou et plus encore en altitude (> 3m de neige).

**Qualité de la neige :**

Jeudi matin, manteau neigeux désormais en cycle printanier avec un bon regel portant sauf dans les zones de forêt. En journée, humidification dès le matin au soleil puis à toute altitude avec de la neige de plus en plus lourde et collante à basse altitude. Les cols et crêtes les plus hauts peuvent rester en neige dure voire glacée.

## Aperçu météo pour le jeudi 16 avril

| | nuit | matin | après-midi | soir |
|---|---|---|---|---|
| | | | | |

Belle journée douce et bien ensoleillée, quelques nuages possibles l'après-midi.

| Pluie-Neige | | | | |
|---|---|---|---|---|
| Iso 0 °C | 3 300 m | 3 300 m | 3 200 m | 3 500 m |
| Vent 2000 m | ↘ 20 km/h | ← 15 km/h | ↙ 20 km/h | ↘ 15 km/h |
| Vent 3000 m | ↘ 35 km/h | ↘ 30 km/h | ↘ 30 km/h | → 25 km/h |

## Épaisseur de neige hors-piste

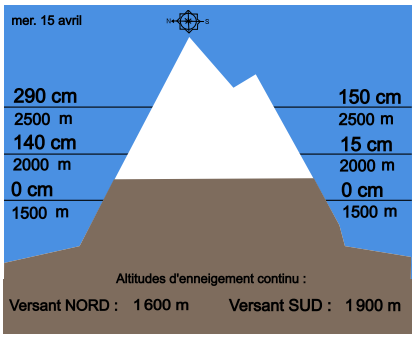


## Précipitations à 1800 m

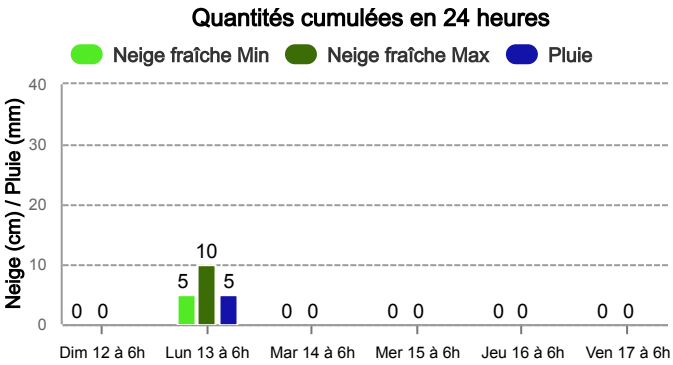


## Tendance du vendredi 17 avril

2

**Indice de risque limité**

Peu d'évolution avec un nouveau cycle gel-dégel et l'humidification progressive qui se poursuit.

Pour consulter la vigilance en cours, veuillez vous rendre sur le site https://vigilance.meteofrance.fr/fr

Météo-France - 73 avenue de Paris, 94165 Saint-Mandé cedex - Contact : contact@meteo.fr

Rédigé par Météo-France avec la contribution des observateurs du réseau nivo-météorologiques. Partenariat : ANMSM (Maires de Stations de Montagne), DSF (Domaines Skiables de France), ADSP (Directeurs de Pistes et de la Sécurité des Stations de Sports d'Hiver) et autres acteurs de la montagne.

Bulletin neige & avalanches par téléphone au 0 892 68 10 20 Service 0,35 € / min + prix appel

RÉPUBLIQUE FRANÇAISE
*Liberté Égalité Fraternité*

METEO FRANCE
À VOS CÔTÉS, DANS UN CLIMAT QUI CHANGE

# Bulletin d'estimation du risque d'avalanche
## (valable en dehors des pistes balisées et ouvertes)
# MASSIF : Cerdagne Canigou

Rédigé le mercredi 15 avril 2026 à 16h

## Conditions nivo-météo des 7 derniers jours

| | jeu. 09/04 | | | | ven. 10/04 | | | | sam. 11/04 | | | | dim. 12/04 | | | | lun. 13/04 | | | | mar. 14/04 | | | | mer. 15/04 | | | |
|---|---|---|---|---|---|---|---|---|---|---|---|---|---|---|---|---|---|---|---|---|---|---|---|---|---|---|---|---|
| | 03h | 09h | 15h | 21h | 03h | 09h | 15h | 21h | 03h | 09h | 15h | 21h | 03h | 09h | 15h | 21h | 03h | 09h | 15h | 21h | 03h | 09h | 15h | 21h | 03h | 09h | 15h | 21h |
| Météo | | | | | | | | | | | | | | | | | | | | | | | | | | | | |
| Vent (km/h) | 25 | 25 | 25 | 25 | 30 | 20 | 25 | 25 | 30 | 30 | 45 | 45 | 40 | 30 | 30 | 20 | 50 | 50 | 55 | 55 | 50 | 50 | 50 | 45 | 35 | 25 | 25 | 20 |
| à 3000m | | | | | | | | | | | | | | | | | | | | | | | | | | | | |
| Vent (km/h) | 15 | 15 | 15 | 15 | 20 | 15 | 20 | 15 | 20 | 20 | 35 | 35 | 25 | 20 | 20 | 15 | 35 | 30 | 30 | 25 | 25 | 25 | 25 | 20 | 20 | 15 | 15 | 10 |
| à 2000m | | | | | | | | | | | | | | | | | | | | | | | | | | | | |

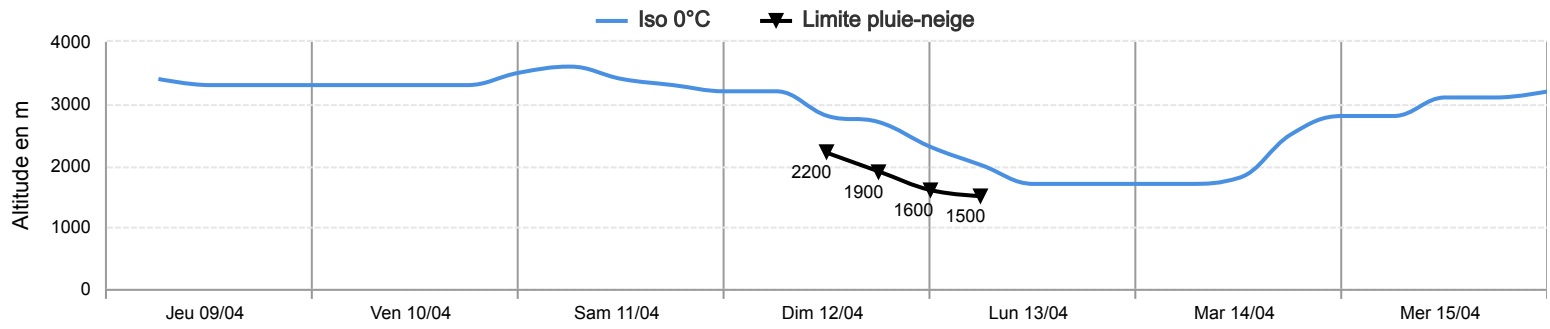


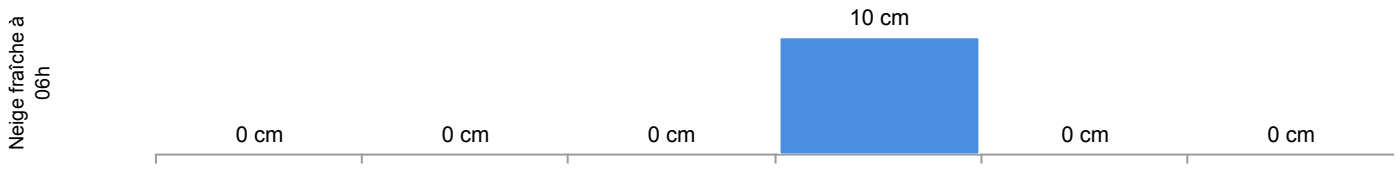


| Risque d'avalanche | jeu. 09/04 | ven. 10/04 | sam. 11/04 | dim. 12/04 | lun. 13/04 | mar. 14/04 | mer. 15/04 |
|---|---|---|---|---|---|---|---|
| | 2 | 2 | 2 | 2 | 2 | 2 | 2 |

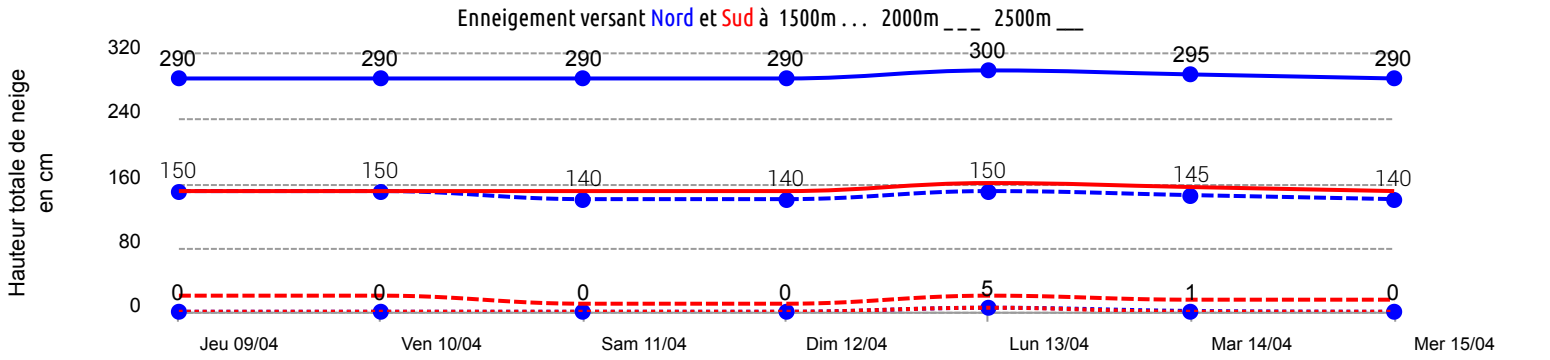


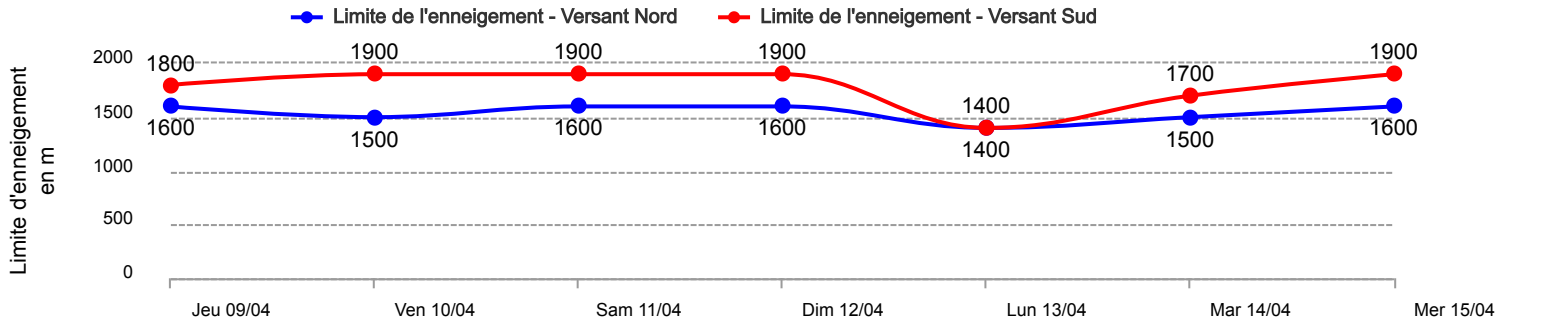


Pour consulter la vigilance en cours, veuillez vous rendre sur le site https://vigilance.meteofrance.fr/fr


**Météo-France - 73 avenue de Paris, 94165 Saint-Mandé cedex - Contact : contact@meteo.fr**


Rédigé par Météo-France avec la contribution des observateurs du réseau nivo-météorologiques. Partenariat : ANMSM (Maires de Stations de Montagne), DSF (Domaines Skiables de France), ADSP (Directeurs de Pistes et de la Sécurité des Stations de Sports d'Hiver) et autres acteurs de la montagne.

**Bulletin neige & avalanches par téléphone au**

**0 892 68 10 20** Service 0,35 € / min + prix appel