Bulletin d'estimation du risque d'avalanche
(valable en dehors des pistes balisées et ouvertes)

MASSIF : Chablais

Rédigé le mercredi 15 avril 2026 à 16h

Estimation des risques pour le : JEUDI 16 AVRIL

POURSUITE DE L'HUMIDIFICATION DU MANTEAU NEIGEUX

2

2

N O E S

Indice de risque limité.

Départs spontanés : Avalanches de neige humide

Déclenchements provoqués : Avalanches de neige humide

Indices de risque : 5 très fort - 4 fort - 3 marqué - 2 limité - 1 faible -- En noir : les pentes les plus dangereuses

Stabilité du manteau neigeux

Situation avalancheuse typique : neige humide — avalanches de fond

Départs spontanés :

* **avalanches de neige humide**, possibles dès le matin et de plus en plus nombreuses au fil du rayonnement solaire, en tous versants et plus nombreuses sous 2300 m. Taille 1 à 2 (petites à moyennes). Au-dessus de 2200 m, de petits départs ponctuels peuvent déclencher, en cascade, une plaque de plus grandes ampleurs. Rarement en taille 3 (grande).
Observables : enfoncement piéton important, boulettes, escargots
* quelques plaques de fond dans les zones herbeuses ou dalles rocheuses, à toute heure du jour ou de la nuit, en dessous de 2600 m. Taille 2.

Déclenchements provoqués :

Avalanches de neige humides dans les versants raides et chauffés par le soleil, facilement déclenchable par un skieur. Départ ponctuel pouvant parfois déclencher, en cascade, une petite plaque. Taille 1, rarement 2.

Qualité de la neige

Enneigement :

Pour la saison, l'enneigement est correct au-dessus de 2000 m, en dessous il est déficitaire.
On peut chausser les skis au-dessus de 1800 m en sud et 1500 m en nord.

Qualité de la neige ce jeudi matin :

* au-dessus des nuages bas (2300 m), neige de printemps avec un bon regel nocturne.
* en dessous de 2300 m, neige fortement humidifiée sans regel nocturne.

Aperçu météo pour le jeudi 16 avril

nuit	matin	après-midi	soir

Mer de nuages en dessous de 2300 m se dissipant rapidement en début de matinée. Cumulus dans les pentes l'après-midi.

Pluie-Neige				
Iso 0 °C	2 900 m	2 900 m	3 000 m	3 100 m
Vent 2000 m	10 km/h	10 km/h	5 km/h	10 km/h
Vent 2500 m	15 km/h	15 km/h	10 km/h	15 km/h

Épaisseur de neige hors-piste

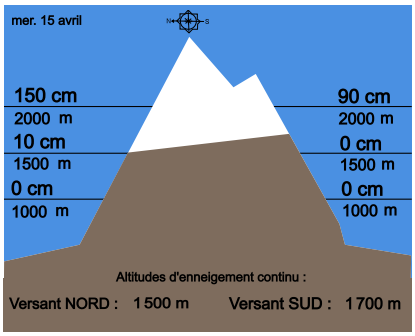

Précipitations à 1800 m

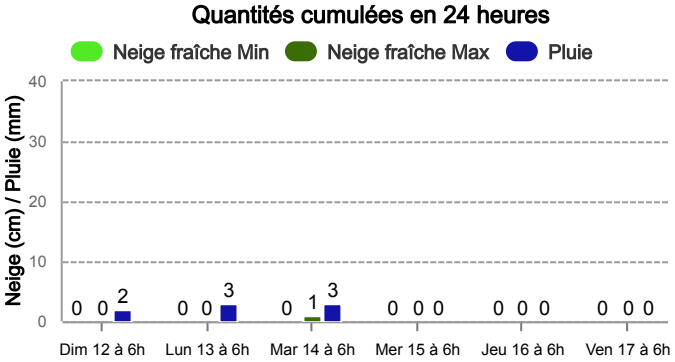

Tendance du vendredi 17 avril

2

Indice de risque limité

Vendredi : temps et ensoleillé, isotherme 0°C vers 3300 m.
Poursuite de l'humidification du manteau neigeux.

Pour consulter la vigilance en cours, veuillez vous rendre sur le site https://vigilance.meteofrance.fr/fr

Météo-France - 73 avenue de Paris, 94165 Saint-Mandé cedex - Contact : contact@meteo.fr

Rédigé par Météo-France avec la contribution des observateurs du réseau nivo-météorologiques. Partenariat : ANMSM (Maires de Stations de Montagne), DSF (Domaines Skiables de France), ADSP (Directeurs de Pistes et de la Sécurité des Stations de Sports d'Hiver) et autres acteurs de la montagne.

Bulletin neige & avalanches par téléphone au 0 892 68 10 20 Service 0,35 € / min + prix appel

RÉPUBLIQUE FRANÇAISE
Liberté Égalité Fraternité

METEO FRANCE
À VOS CÔTÉS, DANS UN CLIMAT QUI CHANGE

Bulletin d'estimation du risque d'avalanche

(valable en dehors des pistes balisées et ouvertes)

MASSIF : Chablais

Rédigé le mercredi 15 avril 2026 à 16h

Conditions nivo-météo des 7 derniers jours

	jeu. 09/04				ven. 10/04				sam. 11/04				dim. 12/04				lun. 13/04				mar. 14/04				mer. 15/04			
	03h	09h	15h	21h	03h	09h	15h	21h	03h	09h	15h	21h	03h	09h	15h	21h	03h	09h	15h	21h	03h	09h	15h	21h	03h	09h	15h	21h
Météo																												
Vent (km/h)	10	15	10	15	20	25	20	30	25	35	25	30	30	25	25	25	25	25	15	15	15	20	20	20	15	10	10	10
à 2500m																												
Vent (km/h)	5	10	5	5	10	15	15	25	20	30	20	20	20	20	15	15	10	15	10	10	20	25	15	15	10	5	5	5
à 2000m																												

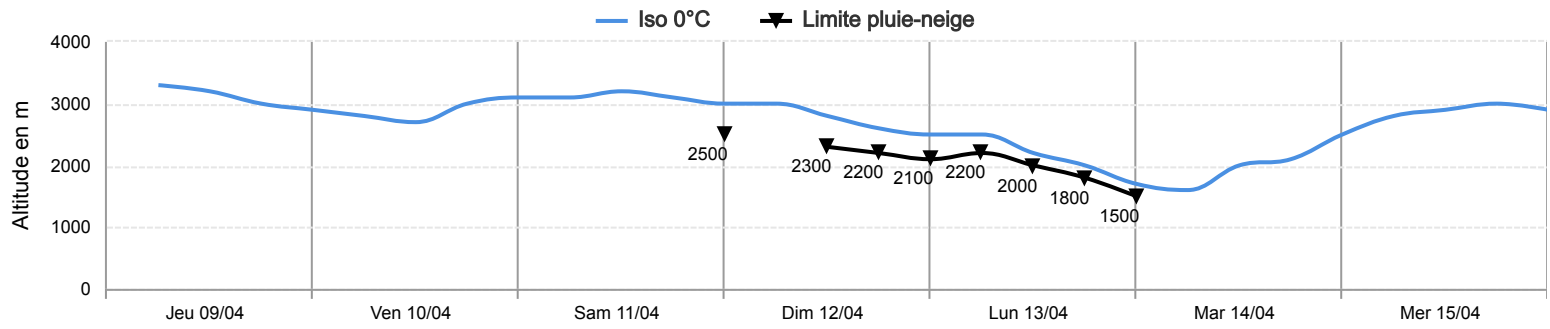

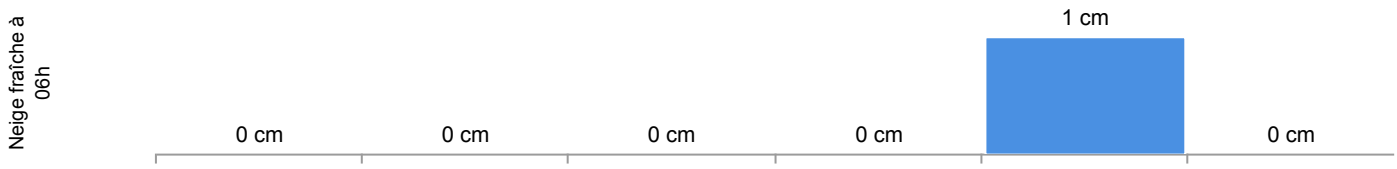

Risque d'avalanche	jeu. 09/04	ven. 10/04	sam. 11/04	dim. 12/04	lun. 13/04	mar. 14/04	mer. 15/04
	3	3	3	2	2	2	2

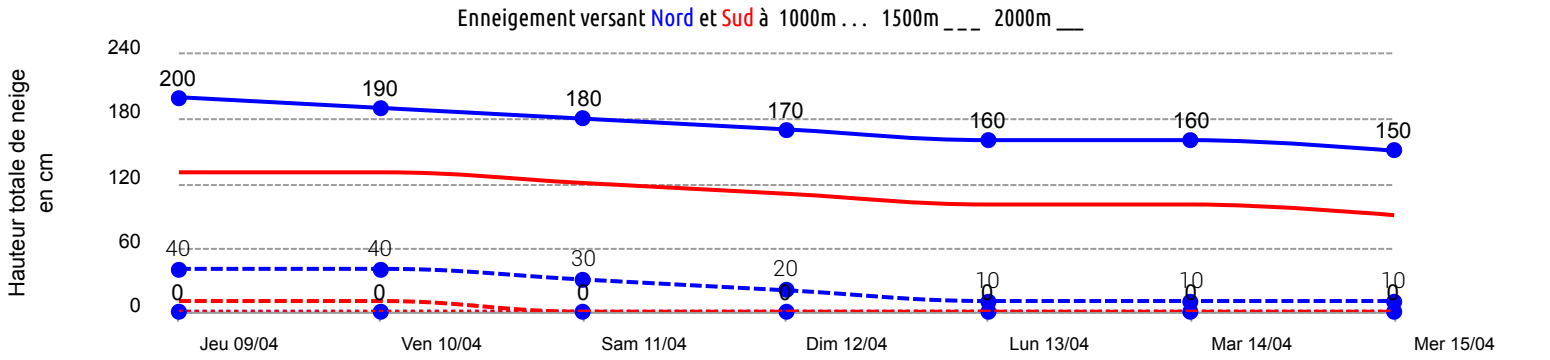

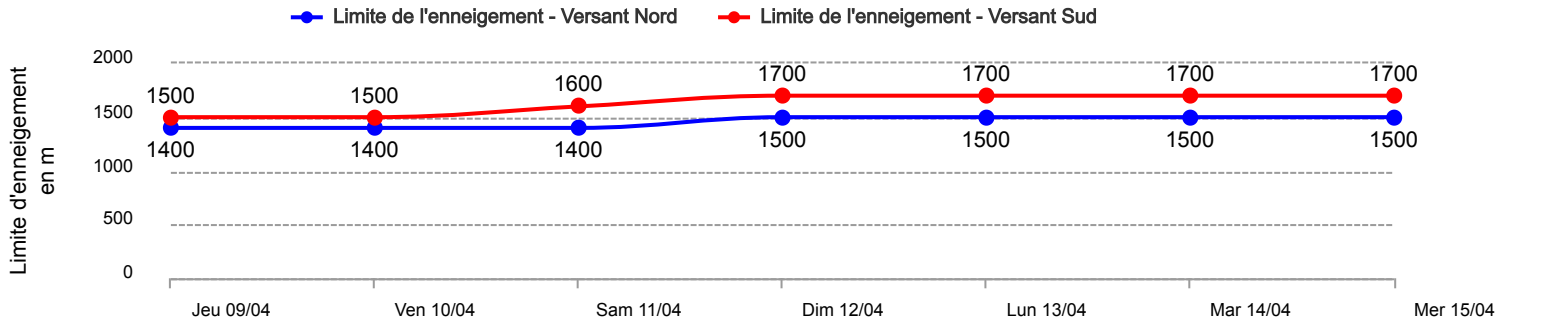

Pour consulter la vigilance en cours, veuillez vous rendre sur le site https://vigilance.meteofrance.fr/fr

Météo-France - 73 avenue de Paris, 94165 Saint-Mandé cedex - Contact : contact@meteo.fr

Rédigé par Météo-France avec la contribution des observateurs du réseau nivo-météorologiques. Partenariat : ANMSM (Maires de Stations de Montagne), DSF (Domaines Skiables de France), ADSP (Directeurs de Pistes et de la Sécurité des Stations de Sports d'Hiver) et autres acteurs de la montagne.

Bulletin neige & avalanches par téléphone au
0 892 68 10 20 Service 0,35 € / min + prix appel