Bulletin d'estimation du risque d'avalanche
(valable en dehors des pistes balisées et ouvertes)

MASSIF : Haut-Var Haut-Verdon

Rédigé le mercredi 15 avril 2026 à 16h

Estimation des risques pour le : JEUDI 16 AVRIL

MANTEAU NEIGEUX PRINTANIER

2

1 → 2

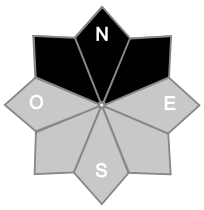

Indice de risque faible évoluant en limité.

Départs spontanés : avalanches en neige humide, plus volumineuses en ubacs d'altitude.

Déclenchements provoqués : départs en neige humide sous les skis, plus volumineux en ubacs d'altitude.

Indices de risque : 5 très fort - 4 fort - 3 marqué - 2 limité - 1 faible -- En noir : les pentes les plus dangereuses

Stabilité du manteau neigeux

Situation avalancheuse typique : neige humide — couche fragile persistante

Déclenchements provoqués :
- Des départs en neige humide sont possibles sous les skis en pentes raides ensoleillées, généralement de petite taille.
- Des couches fragiles persistantes enfouies à la base du manteau neigeux sont encore localement présentes en orientations nord-ouest, nord et nord-est d'altitude supérieure à 2300/2400 m environ. Avec l'humidification progressive du manteau neigeux, un skieur peut venir les solliciter, et provoquer une cassure linéaire déclenchant une avalanche de taille moyenne, voire une rare grande dans les secteurs encore bien enneigés.

Départs spontanés :
- Après un bon regel nocturne, reprise de l'humidification du manteau neigeux en cours de matinée, provoquant des départs de petite taille en général. Avalanches de taille moyenne avec cassure linéaire possibles dans quelques pentes d'orientations nord-ouest, nord et nord-est d'altitude au dessus de 2300 m environ, voire rare grande possible dans les secteurs encore bien enneigés, si une couche fragile persistante enfouie en profondeur s'humidifie pour la première fois.

Qualité de la neige

Enneigement proche des normales pour la saison.
Hauteurs de neige observées : vers 2000 m, 120 cm dans le vallon de Valdemars en Haut Verdon, 48 cm à la Sanguinière dans le Haut-Var.

Enneigement skiable généralement à partir de 1800 m en terrain favorable (routes forestières, terrains herbeux) et 2200/2300 m en adrets peu pentus.

État de la neige en surface : manteau neigeux printanier, avec un bon regel nocturne en général au dessus de 2000 m.

Aperçu météo pour le jeudi 16 avril

Temps ensoleillé et doux, quelques averses possibles l'après-midi.

	nuit	matin	après-midi	soir
Pluie-Neige	2 700 m			
Iso 0 °C	3 100 m	3 100 m	3 100 m	3 200 m
Vent 2000 m	↓ 10 km/h	↖ 10 km/h	↑ 20 km/h	← 5 km/h
Vent 3000 m	→ 15 km/h	↗ 10 km/h	→ 15 km/h	↗ 10 km/h

Épaisseur de neige hors-piste

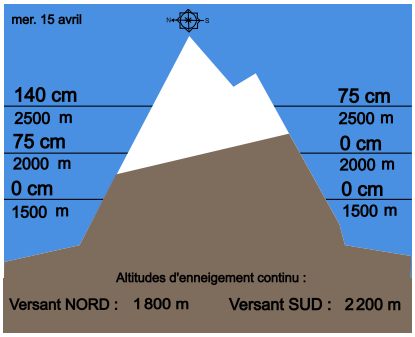

Précipitations à 1800 m

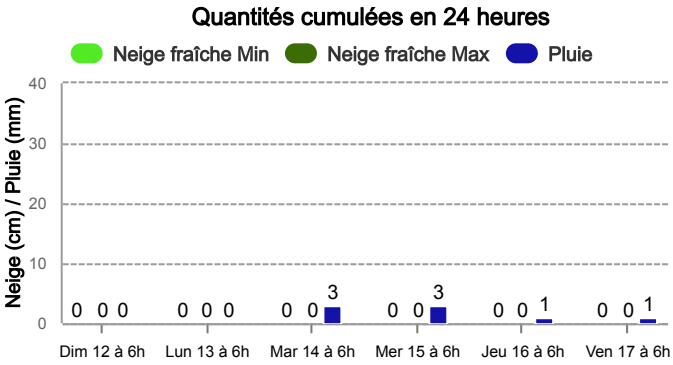

Tendance du vendredi 17 avril

2

Indice de risque limité

Poursuite de l'humidification du manteau neigeux avec des conditions ensoleillées et chaudes.

Pour consulter la vigilance en cours, veuillez vous rendre sur le site https://vigilance.meteofrance.fr/fr

Météo-France - 73 avenue de Paris, 94165 Saint-Mandé cedex - Contact : contact@meteo.fr

Rédigé par Météo-France avec la contribution des observateurs du réseau nivo-météorologiques. Partenariat : ANMSM (Maires de Stations de Montagne), DSF (Domaines Skiables de France), ADSP (Directeurs de Pistes et de la Sécurité des Stations de Sports d'Hiver) et autres acteurs de la montagne.

Bulletin neige & avalanches par téléphone au 0 892 68 10 20 Service 0,35 € / min + prix appel

RÉPUBLIQUE FRANÇAISE
Liberté Égalité Fraternité

METEO FRANCE
À VOS CÔTÉS, DANS UN CLIMAT QUI CHANGE

Bulletin d'estimation du risque d'avalanche

(valable en dehors des pistes balisées et ouvertes)

MASSIF : Haut-Var Haut-Verdon

Rédigé le mercredi 15 avril 2026 à 16h

Conditions nivo-météo des 7 derniers jours

	jeu. 09/04				ven. 10/04				sam. 11/04				dim. 12/04				lun. 13/04				mar. 14/04				mer. 15/04			
	03h	09h	15h	21h	03h	09h	15h	21h	03h	09h	15h	21h	03h	09h	15h	21h	03h	09h	15h	21h	03h	09h	15h	21h	03h	09h	15h	21h
Météo																												
Vent (km/h)	15	15	25	35	40	20	30	25	25	25	30	15	15	20	25	25	25	30	35	40	40	35	35	25	35	20	15	10
à 3000m	↓	↘	↘	↓	↓	↘	↘	↘	↘	↘	→	↑	↗	↑	↖	↖	↖	←	←	←	←	←	←	←	↙	↙	↘	↓
Vent (km/h)	5	10	20	20	20	15	25	15	20	15	20	10	10	15	25	35	35	25	25	25	25	30	25	20	25	15	20	10
à 2000m	↓	↖	↘	↓	↓	↘	↘	↘	↘	→	↗	↖	↖	←	↖	←	←	↙	↓	↓	↓	↓	↓	↓	↓	↙	←	↓

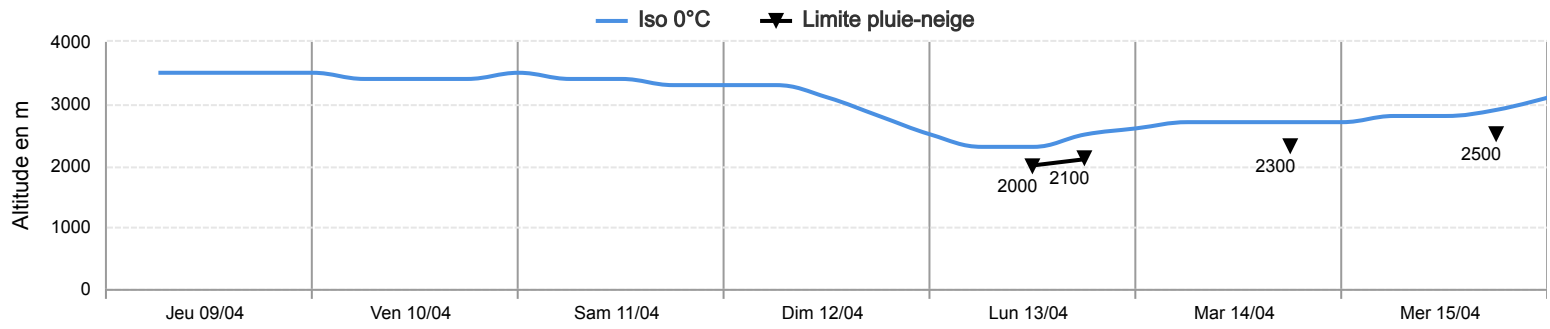

Neige fraîche à 06h

0 cm	0 cm	0 cm	0 cm	0 cm	0 cm

Risque d'avalanche	jeu. 09/04	ven. 10/04	sam. 11/04	dim. 12/04	lun. 13/04	mar. 14/04	mer. 15/04
	3	3	3	2	2	2	2

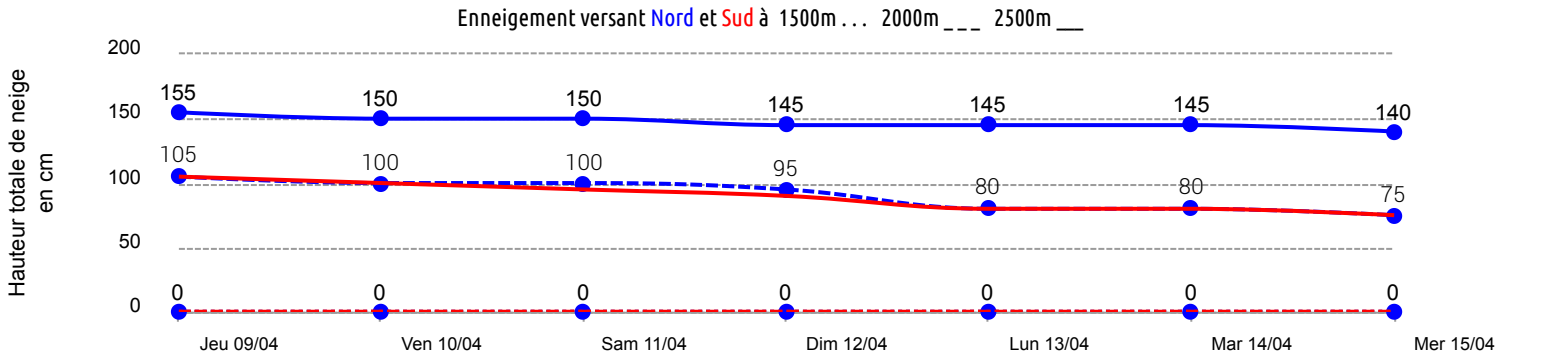

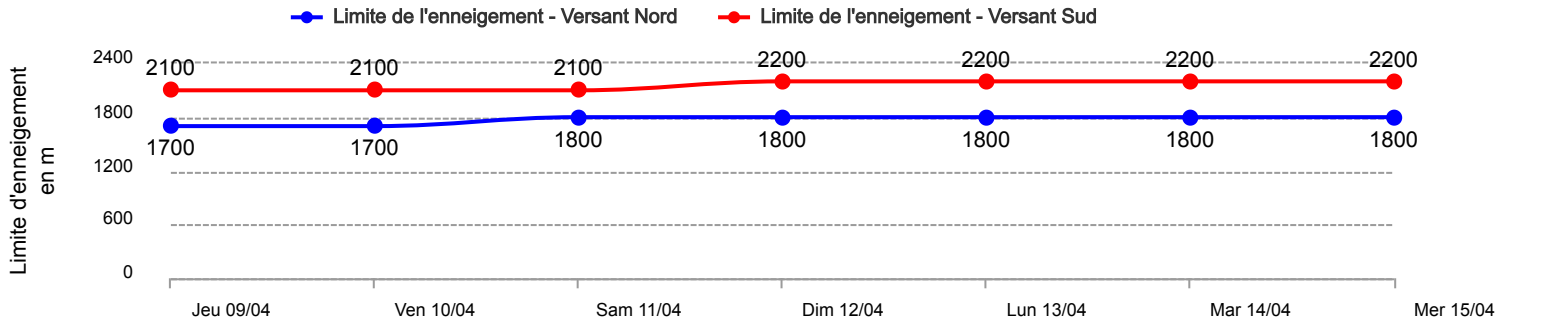

Pour consulter la vigilance en cours, veuillez vous rendre sur le site https://vigilance.meteofrance.fr/fr

Météo-France - 73 avenue de Paris, 94165 Saint-Mandé cedex - Contact : contact@meteo.fr

Bulletin neige & avalanches par téléphone au

0 892 68 10 20 Service 0,35 € / min + prix appel

Rédigé par Météo-France avec la contribution des observateurs du réseau nivo-météorologiques. Partenariat : ANMSM (Maires de Stations de Montagne), DSF (Domaines Skiables de France), ADSP (Directeurs de Pistes et de la Sécurité des Stations de Sports d'Hiver) et autres acteurs de la montagne.