Bulletin d'estimation du risque d'avalanche

(valable en dehors des pistes balisées et ouvertes)

MASSIF : Haute-Bigorre

Rédigé le mercredi 15 avril 2026 à 16h

Estimation des risques pour le : JEUDI 16 AVRIL

STRUCTURES DE PLAQUES EN ZONES OMBRAGÉES D'ALTITUDE, HUMIDIFICATION PARTOUT AILLEURS.

2

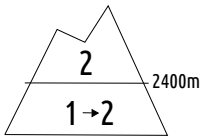

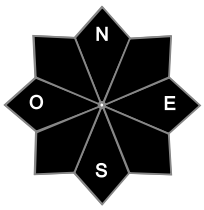

Plaques et soleil.

Au-dessus de 2400m indice de risque limité, plus bas indice faible évoluant en limité.

Départs spontanés : Dans la neige humide au fil de l'ensoleillement.

Déclenchements provoqués : Plaques dans les zones ombragées d'altitude, dans la neige humide ailleurs.

Indices de risque : 5 très fort - 4 fort - 3 marqué - 2 limité - 1 faible -- En noir : les pentes les plus dangereuses

Stabilité du manteau neigeux

Situation avalancheuse typique : neige humide neige ventée

Départs spontanés :
L'activité avalancheuse reste limitée tôt le matin par un bon regel. Puis, des départs ponctuels dans la neige humide sont attendus dans les pentes raides des versants au fil de la journée et de l'ensoleillement. De petites avalanches (taille 1), voire parfois des moyennes (taille 2) sont possibles d'abord des versants Est à Sud le matin, puis rapidement des versants Sud à Ouest dans la journée. De grandes avalanches (taille 3) restent possibles lors du départ d'une avalanche de fond, partant préférentiellement près des fissures et des reptations, notamment dans les zones d'accumulation les plus importantes.

Déclenchements provoqués :
Au-dessus de 2400m environ, des structures de plaques peuvent encore être en place dans les pentes raides des versants ombragés (versants Nord-Ouest, Nord et Nord-Est) issues des chutes de neige précédentes. Un simple skieur peut déclencher ces plaques, engendrant ainsi de petites avalanches (taille 1), parfois des moyennes (taille 2).
Partout ailleurs, un skieur peut déclencher des départs ponctuels dans la neige humide et dans les pentes raides des versants au fil de la journée et de l'ensoleillement. Un bon regel devrait limiter cette activité tôt le matin, mais concernera ensuite préférentiellement les versants Est à Sud le matin, puis les versants Sud à Ouest en journée. De petites avalanches (taille 1), parfois des moyennes (taille 2) sont possibles.

Autres :
Neige dure et glissante au petit matin. Avec la douceur ambiante, les corniches et pont de neige deviennent à nouveau très fragiles.

Qualité de la neige

Enneigement : L'enneigement est plutôt pour la saison, débutant vers 1600m en nord, 1950m environ en sud. Cette limite d'enneigement tend à remonter progressivement avec la douceur ambiante et le soleil.
État de la neige : Neige bien regelée le matin, s'humidifiant progressivement au fil de la journée et de la douceur ambiante. Au-dessus de 2300 à 2400m, dans les pentes raides des versants ombragés (du Nord-Ouest au Nord-Est), on trouve encore sur une bonne épaisseur de la neige sèche à meuble, reposant sur un fond dur à regelé.

Aperçu météo pour le jeudi 16 avril

nuit	matin	après-midi	soir

Grand soleil le matin, quelques développements nuageux sous 2000m l'après-midi et sans incidence. Temps sec et douceur.

Pluie-Neige				
Iso 0 °C	3 200 m	3 400 m	3 500 m	3 300 m
Vent 2000 m	↘ 5 km/h	↘ 5 km/h	↘ 5 km/h	↘ 5 km/h
Vent 3000 m	→ 15 km/h	→ 15 km/h	→ 10 km/h	→ 15 km/h

Épaisseur de neige hors-piste

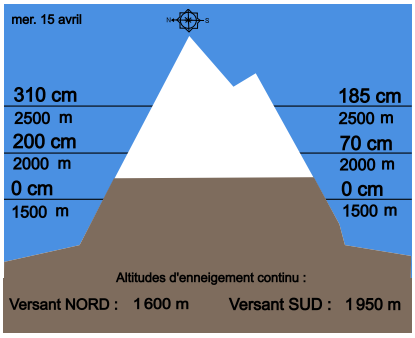

Précipitations à 1800 m

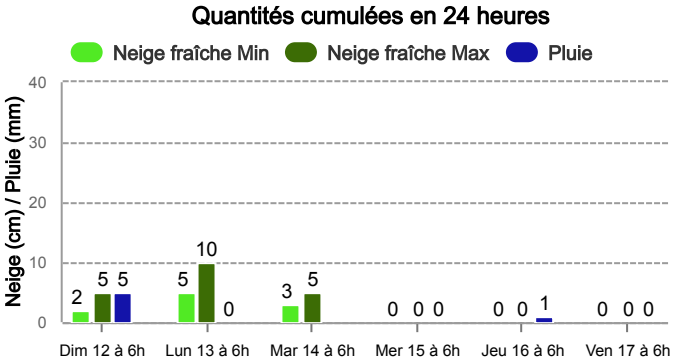

Tendance du vendredi 17 avril

2

Indice de risque limité

Risque stationnaire. Poursuite de l'humidification en profondeur avec la douceur ambiante, humidification progressive des plaques dans les versants ombragés d'altitude.

Pour consulter la vigilance en cours, veuillez vous rendre sur le site https://vigilance.meteofrance.fr/fr

Météo-France - 73 avenue de Paris, 94165 Saint-Mandé cedex - Contact : contact@meteo.fr

Rédigé par Météo-France avec la contribution des observateurs du réseau nivo-météorologiques. Partenariat : ANMSM (Maires de Stations de Montagne), DSF (Domaines Skiables de France), ADSP (Directeurs de Pistes et de la Sécurité des Stations de Sports d'Hiver) et autres acteurs de la montagne.

Bulletin neige & avalanches par téléphone au **0 892 68 10 20** Service 0,35 € / min + prix appel

RÉPUBLIQUE FRANÇAISE
Liberté Égalité Fraternité

METEO FRANCE
À VOS CÔTÉS, DANS UN CLIMAT QUI CHANGE

Bulletin d'estimation du risque d'avalanche

(valable en dehors des pistes balisées et ouvertes)

MASSIF : Haute-Bigorre

Rédigé le mercredi 15 avril 2026 à 16h

Conditions nivo-météo des 7 derniers jours

	jeu. 09/04				ven. 10/04				sam. 11/04				dim. 12/04				lun. 13/04				mar. 14/04				mer. 15/04			
	03h	09h	15h	21h	03h	09h	15h	21h	03h	09h	15h	21h	03h	09h	15h	21h	03h	09h	15h	21h	03h	09h	15h	21h	03h	09h	15h	21h
Météo																												
Vent (km/h)	20	20	15	10	20	35	35	45	50	45	35	60	30	25	20	30	55	45	35	30	50	55	45	30	30	15	15	15
à 3000m																												
Vent (km/h)	5	10	10	5	5	10	10	20	30	25	10	15	5	10	10	10	20	20	15	10	15	20	20	10	10	10	10	10
à 2000m																												

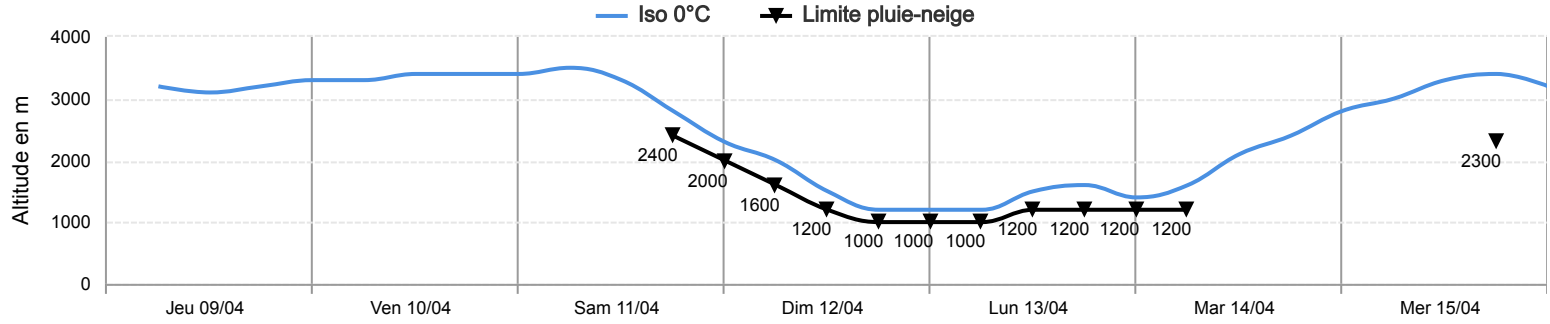

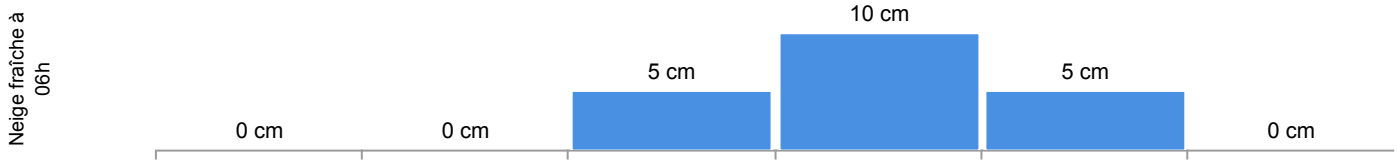

Risque d'avalanche	jeu. 09/04	ven. 10/04	sam. 11/04	dim. 12/04	lun. 13/04	mar. 14/04	mer. 15/04
	2	2	2	2	3	2	2

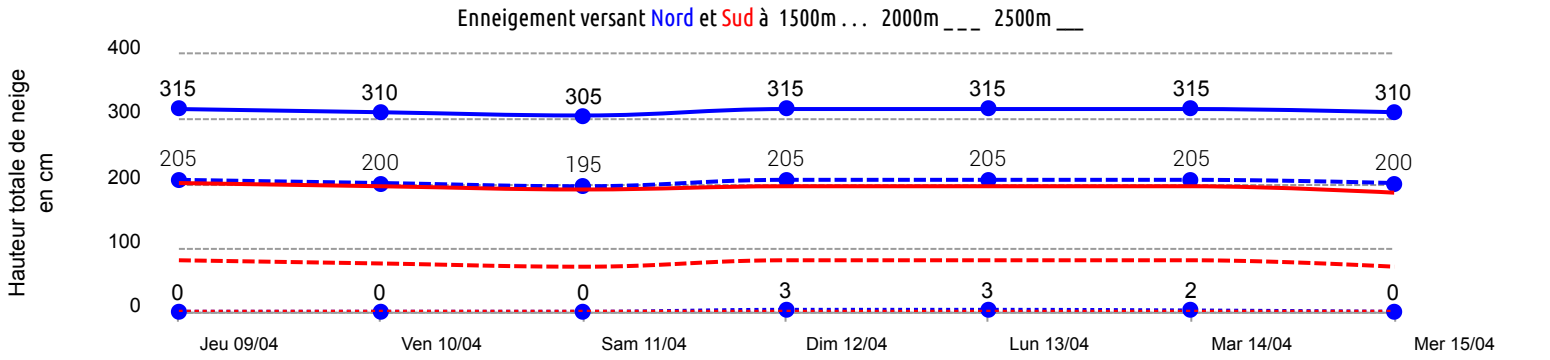

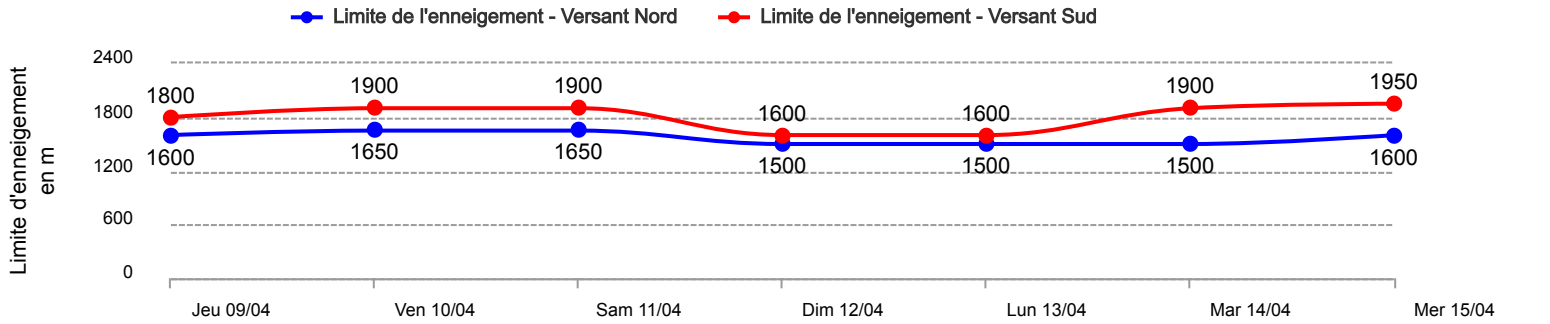

Pour consulter la vigilance en cours, veuillez vous rendre sur le site https://vigilance.meteofrance.fr/fr

Météo-France - 73 avenue de Paris, 94165 Saint-Mandé cedex - Contact : contact@meteo.fr

Bulletin neige & avalanches par téléphone au

0 892 68 10 20 Service 0,35 € / min + prix appel

Rédigé par Météo-France avec la contribution des observateurs du réseau nivo-météorologiques. Partenariat : ANMSM (Maires de Stations de Montagne), DSF (Domaines Skiables de France), ADSP (Directeurs de Pistes et de la Sécurité des Stations de Sports d'Hiver) et autres acteurs de la montagne.