RÉPUBLIQUE FRANÇAISE
Liberté Égalité Fraternité

METEO FRANCE
À VOS CÔTÉS, DANS UN CLIMAT QUI CHANGE

Bulletin d'estimation du risque d'avalanche
(valable en dehors des pistes balisées et ouvertes)
MASSIF : Haute-Maurienne

Rédigé le mercredi 15 avril 2026 à 16h

Estimation des risques pour le : JEUDI 16 AVRIL

POURSUITE DE L'HUMIDIFICATION SOUS L'EFFET DU SOLEIL. QUELQUES PLAQUES À LA FRONTIÈRE ITALIENNE.

2

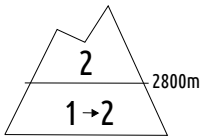

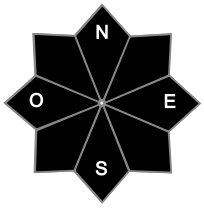

Au-dessus de 2800m indice de risque limité, plus bas indice faible évoluant en limité.

Départs spontanés : Quelques départs humides, plus nombreux au fil des heures.

Déclenchements provoqués : quelques plaques réactives en altitude et plaques d'aspect humide plus bas.

Indices de risque : 5 très fort - 4 fort - 3 marqué - 2 limité - 1 faible -- En noir : les pentes les plus dangereuses

Stabilité du manteau neigeux

Situation avalancheuse typique : neige fraîche neige humide

Départs spontanés : - Le matin le regel bon par ciel clair réduit et le risque de départs naturels au dessus des nuages matinaux .
- Quelques départs en neige humide, qui **suivent la course du soleil**. Ce sont principalement des **départs ponctuels (petites coulées humides)**, petites à moyennes avalanches.
Rare cassure **linéaire (plaque)**, **grande avalanche (taille 3),** si l'eau de fonte qui percole dans le manteau atteint les couches fragiles enfouies du début de saison. **Cette cassure linéaire semble plus probable en versants Est/Nord/Ouest, sous 2700 m**.
- **Rares avalanches de glissement** (plaques de fond) à toute heure sur terrains propices, notamment en Nord sous 2500/2600 m. Taille 2.

Déclenchements provoqués :
- En versants froids au dessus de 2800 m, quelques plaques encore réactives d'aspect poudreux sont en place, surtout près des crêtes et vers la frontière italienne. Elles deviennent moins réactives au fil des heures.
- En journée, avalanches de neige humide sous les skis en coupant une pente trop humidifiée au fil des heures. Exceptionnellement une petite coulée peut déclencher en cascade une cassure linéaire, grande avalanche, en sollicitant une couche fragile du début de saison.

Qualité de la neige

Enneigement : l'enneigement est revenu au niveau des normales suite à la chaleur des derniers jours, le chauffage et la présence des nuages accélèrent la fonte.

Limite skiable : vers 1500 m en Nord, 1800/1900 m en Sud.

Qualité de la neige : Bon regel le matin par ciel clair, neige croûtée dans une majorité de pente et d'orientation. Sous l'action du soleil la croûte s'humidifie progressivement, la neige botte facilement. En versants froids partir de 2800m, poudreuse dense.

Aperçu météo pour le jeudi 16 avril

	nuit	matin	après-midi	soir

Mer de nuages en vallée et ciel clair au dessus le matin, des cumulus de beau temps se développent en journée, températures en hausse.

Pluie-Neige				
Iso 0 °C	2 900 m	3 100 m	3 100 m	3 100 m
Vent 2500 m	↘ 5 km/h	↘ 5 km/h	→ 15 km/h	↗ 5 km/h
Vent 3500 m	↘ 15 km/h	↘ 10 km/h	↗ 15 km/h	→ 10 km/h

Épaisseur de neige hors-piste

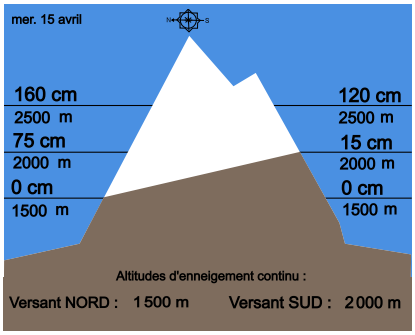

Précipitations à 1800 m

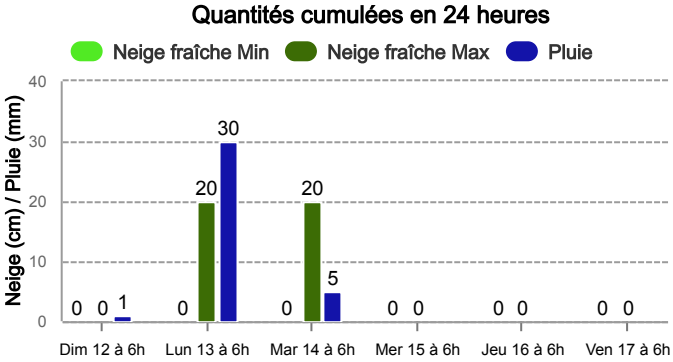

Tendance du vendredi 17 avril

2

Indice de risque limité

Toujours ensoleillé et trop doux, maintient l'activité en neige humide, risque faible évoluant en risque limité, stationnaire.

Pour consulter la vigilance en cours, veuillez vous rendre sur le site https://vigilance.meteofrance.fr/fr

Météo-France - 73 avenue de Paris, 94165 Saint-Mandé cedex - Contact : contact@meteo.fr

Rédigé par Météo-France avec la contribution des observateurs du réseau nivo-météorologiques. Partenariat : ANMSM (Maires de Stations de Montagne), DSF (Domaines Skiables de France), ADSP (Directeurs de Pistes et de la Sécurité des Stations de Sports d'Hiver) et autres acteurs de la montagne.

Bulletin neige & avalanches par téléphone au
0 892 68 10 20 Service 0,35 € / min + prix appel

RÉPUBLIQUE FRANÇAISE
Liberté Égalité Fraternité

METEO FRANCE
À VOS CÔTÉS, DANS UN CLIMAT QUI CHANGE

Bulletin d'estimation du risque d'avalanche

(valable en dehors des pistes balisées et ouvertes)

MASSIF : Haute-Maurienne

Rédigé le mercredi 15 avril 2026 à 16h

Conditions nivo-météo des 7 derniers jours

	jeu. 09/04				ven. 10/04				sam. 11/04				dim. 12/04				lun. 13/04				mar. 14/04				mer. 15/04			
	03h	09h	15h	21h	03h	09h	15h	21h	03h	09h	15h	21h	03h	09h	15h	21h	03h	09h	15h	21h	03h	09h	15h	21h	03h	09h	15h	21h
Météo																												
Vent (km/h)	10	15	30	45	20	25	35	20	30	30	25	25	25	30	40	40	40	35	25	25	20	25	25	15	10	10	15	10
à 3500m																												
Vent (km/h)	5	5	20	35	10	20	30	15	10	10	10	15	15	20	30	30	30	25	15	15	15	20	20	10	5	5	15	5
à 2500m																												

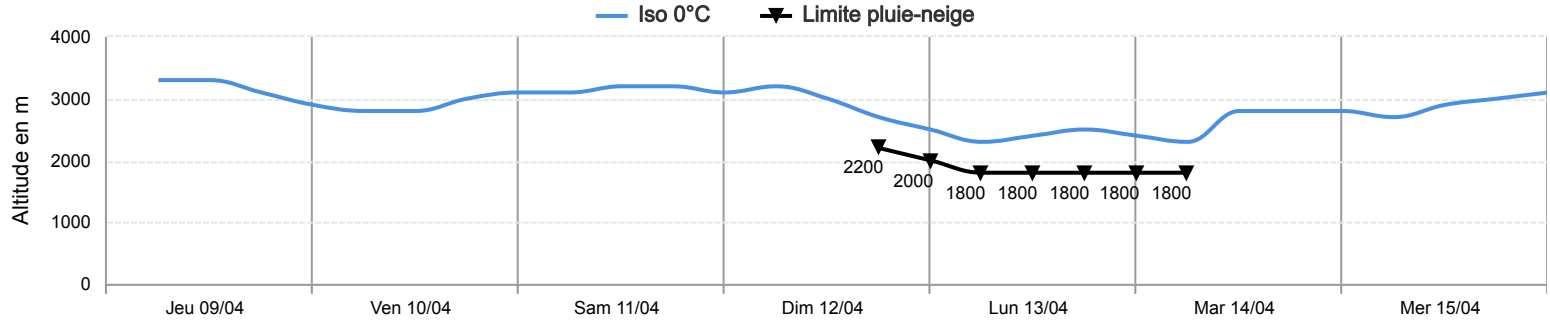

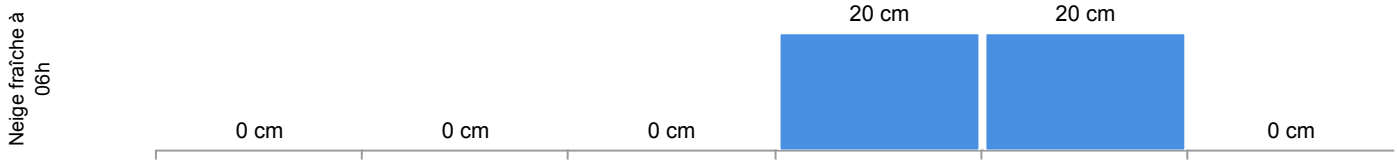

Risque d'avalanche	jeu. 09/04	ven. 10/04	sam. 11/04	dim. 12/04	lun. 13/04	mar. 14/04	mer. 15/04
	3	3	3	2	3	3	3

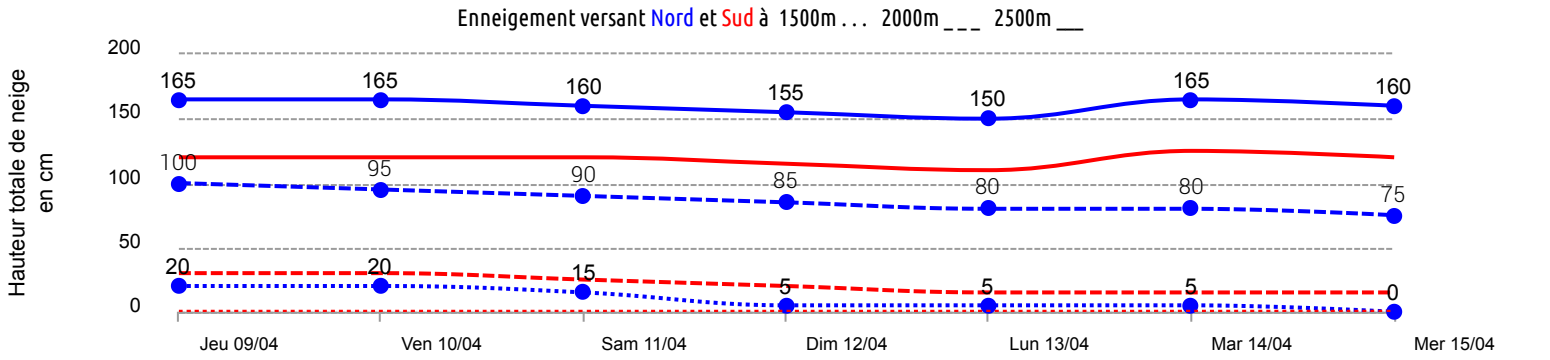

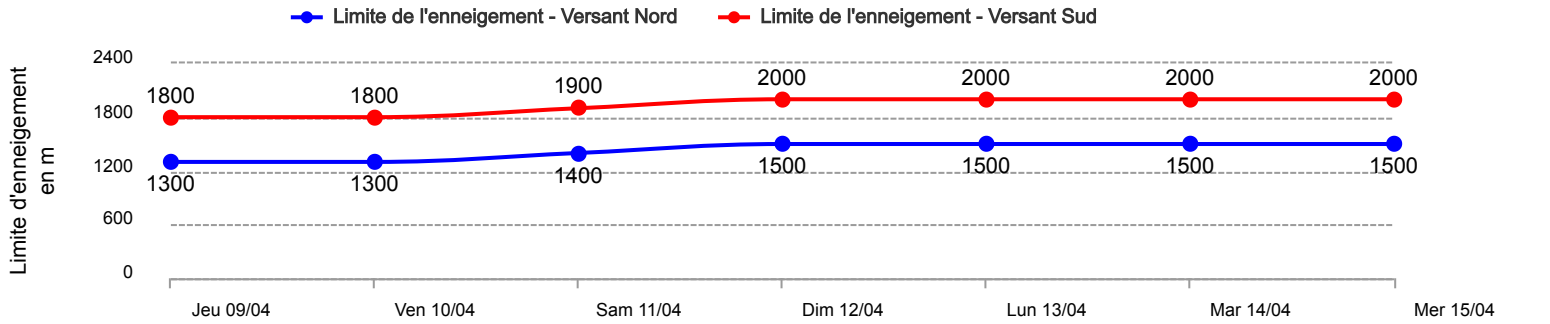

Pour consulter la vigilance en cours, veuillez vous rendre sur le site https://vigilance.meteofrance.fr/fr

Météo-France - 73 avenue de Paris, 94165 Saint-Mandé cedex - Contact : contact@meteo.fr

Rédigé par Météo-France avec la contribution des observateurs du réseau nivo-météorologiques. Partenariat : ANMSM (Maires de Stations de Montagne), DSF (Domaines Skiables de France), ADSP (Directeurs de Pistes et de la Sécurité des Stations de Sports d'Hiver) et autres acteurs de la montagne.

Bulletin neige & avalanches par téléphone au

0 892 68 10 20 Service 0,35 € / min + prix appel