RÉPUBLIQUE FRANÇAISE
Liberté Égalité Fraternité

METEO FRANCE
À VOS CÔTÉS, DANS UN CLIMAT QUI CHANGE

Bulletin d'estimation du risque d'avalanche
(valable en dehors des pistes balisées et ouvertes)
MASSIF : Mont-Blanc

Rédigé le mercredi 15 avril 2026 à 16h

Estimation des risques pour le : JEUDI 16 AVRIL

POURSUITE DE L'HUMIDIFICATION DU MANTEAU NEIGEUX

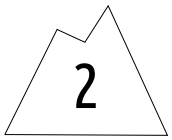

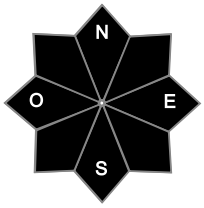

Indice de risque limité.

Départs spontanés : Avalanches de neige humide

Déclenchements provoqués : Avalanches de neige humide

Indices de risque : 5 très fort - 4 fort - 3 marqué - 2 limité - 1 faible -- En noir : les pentes les plus dangereuses

Stabilité du manteau neigeux

Situation avalancheuse typique : neige humide neige ventée

Départs spontanés :
* **avalanches de neige humide**, possibles dès le matin et de plus en plus nombreuses au fil du rayonnement solaire, en tous versants et plus nombreuses sous 2300 m. Taille 1 à 2 (petites à moyennes). Au-dessus de 2000 m, dans les ubacs, de petits départs ponctuels peuvent dans de rares cas déclencher, en cascade, une plaque de plus grandes ampleurs. Rarement en taille 3 (grande).
Observables : enfoncement piéton important, boulettes, escargots
* quelques plaques de fond dans les zones herbeuses ou dalles rocheuses, à toute heure du jour ou de la nuit, en dessous de 2600 m. Taille 2.

Déclenchements provoqués :
* Avalanches de neige humides sous 3800 m en sud et 2500 m en nord, dans les versants raides et chauffés par le soleil, facilement déclenchable par un skieur. Départ ponctuel pouvant parfois déclencher, en cascade, une petite plaque. Taille 1, rarement 2.
* Rares plaques à vent, dans la neige encore froide, en tous versants au-dessus de 3000 m, un peu plus nombreuses et épaisses vers la frontière italienne. Facile à déclencher. Taille 1 à 2.
Observables : vaguelettes, fissures sous les skis, accumulation de neige récente.
Facteur aggravant : présence d'une sous-couche fragile persistante, difficilement déclenchable à ski, mais plus facilement lors d'une avalanche en cascade ou une chute de sérac. Taille 2 à 3 (moyenne à grande) avec d'épaisses cassures.

Qualité de la neige

Enneigement :
Pour la saison, l'enneigement est correct, au-dessus de 3000 m, en dessous il est légèrement déficitaire.
On peut chausser les skis au-dessus de 1800 m en sud et 1500 m en nord.

Qualité de la neige ce jeudi matin :
* au-dessus des nuages bas (2300 m), neige de printemps avec un bon regel nocturne.
* en dessous de 2300 m, neige fortement humidifiée sans regel nocturne.
* au-dessus de 2800 m en nord et 3800 m en sud, 10/30 cm de neige récente encore froide, travaillée par le vent au-dessus de 4000 m, reposant sur un fond dur.

Aperçu météo pour le jeudi 16 avril

nuit	matin	après-midi	soir
2300 m			

Mer de nuages en dessous de 2300 m se dissipant rapidement en début de matinée. Cumulus dans les pentes l'après-midi.

Pluie-Neige				
Iso 0 °C	2 900 m	2 900 m	3 000 m	3 100 m
Vent 2000 m	5 km/h	5 km/h	5 km/h	5 km/h
Vent 4000 m	30 km/h	20 km/h	20 km/h	20 km/h

Épaisseur de neige hors-piste

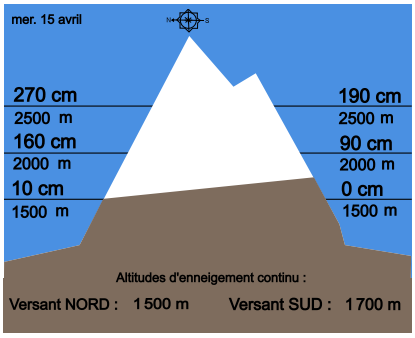

Précipitations à 1800 m

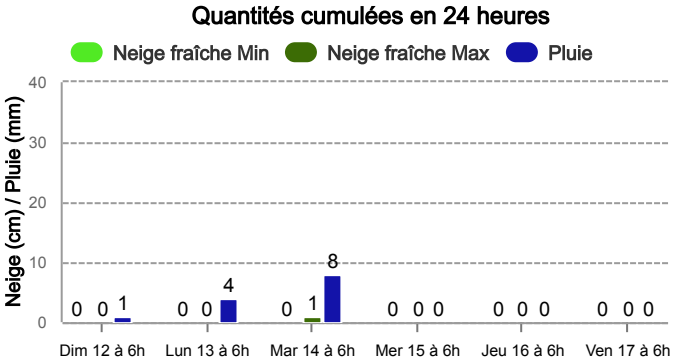

Tendance du vendredi 17 avril

Indice de risque limité

Vendredi : temps et ensoleillé, isotherme 0°C vers 3300 m.
Poursuite de l'humidification du manteau neigeux.

Pour consulter la vigilance en cours, veuillez vous rendre sur le site https://vigilance.meteofrance.fr/fr

Météo-France - 73 avenue de Paris, 94165 Saint-Mandé cedex - Contact : contact@meteo.fr

Rédigé par Météo-France avec la contribution des observateurs du réseau nivo-météorologiques. Partenariat : ANMSM (Maires de Stations de Montagne), DSF (Domaines Skiables de France), ADSP (Directeurs de Pistes et de la Sécurité des Stations de Sports d'Hiver) et autres acteurs de la montagne.

Bulletin neige & avalanches par téléphone au
0 892 68 10 20 Service 0,35 € / min + prix appel

RÉPUBLIQUE FRANÇAISE
Liberté Égalité Fraternité

METEO FRANCE
À VOS CÔTÉS, DANS UN CLIMAT QUI CHANGE

Bulletin d'estimation du risque d'avalanche

(valable en dehors des pistes balisées et ouvertes)

MASSIF : Mont-Blanc

Rédigé le mercredi 15 avril 2026 à 16h

Conditions nivo-météo des 7 derniers jours

	jeu. 09/04				ven. 10/04				sam. 11/04				dim. 12/04				lun. 13/04				mar. 14/04				mer. 15/04			
	03h	09h	15h	21h	03h	09h	15h	21h	03h	09h	15h	21h	03h	09h	15h	21h	03h	09h	15h	21h	03h	09h	15h	21h	03h	09h	15h	21h
Météo																												
Vent (km/h)	15	30	30	45	50	60	55	60	60	60	50	60	60	55	60	50	45	40	30	30	25	15	20	20	10	20	10	20
à 4000m																												
Vent (km/h)	5	5	5	5	15	20	20	20	20	20	25	20	20	15	20	15	10	5	5	10	20	25	15	10	15	5	5	5
à 2000m																												

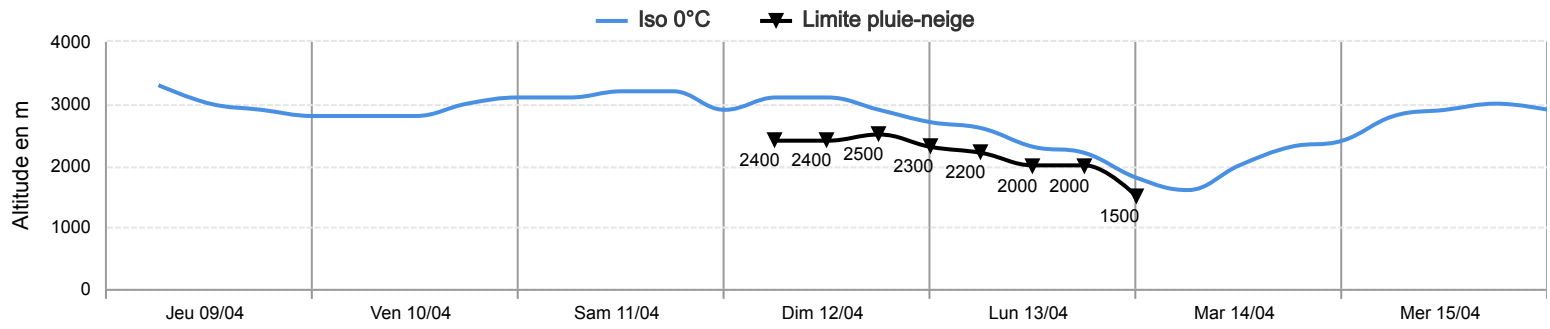

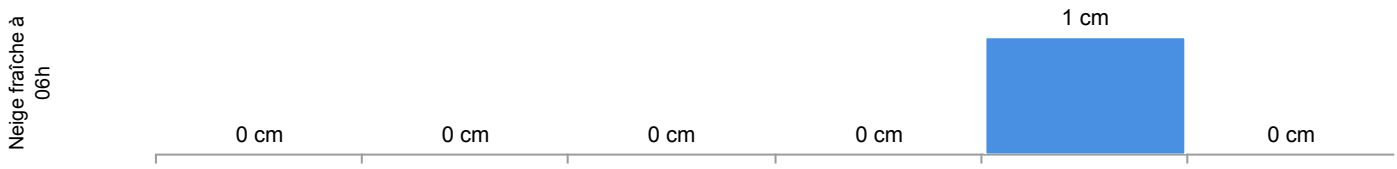

Risque d'avalanche	jeu. 09/04	ven. 10/04	sam. 11/04	dim. 12/04	lun. 13/04	mar. 14/04	mer. 15/04
	3	3	3	2	2	2	2

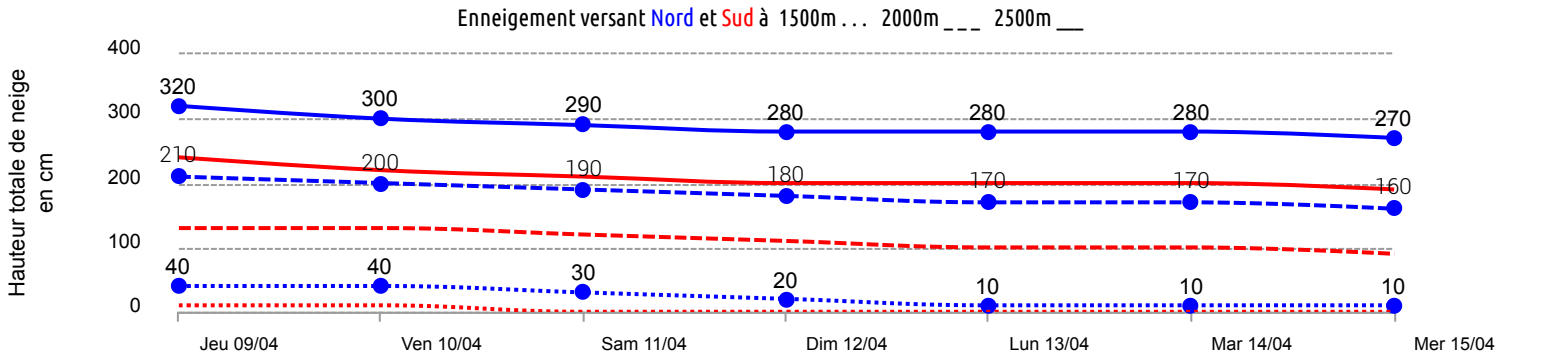

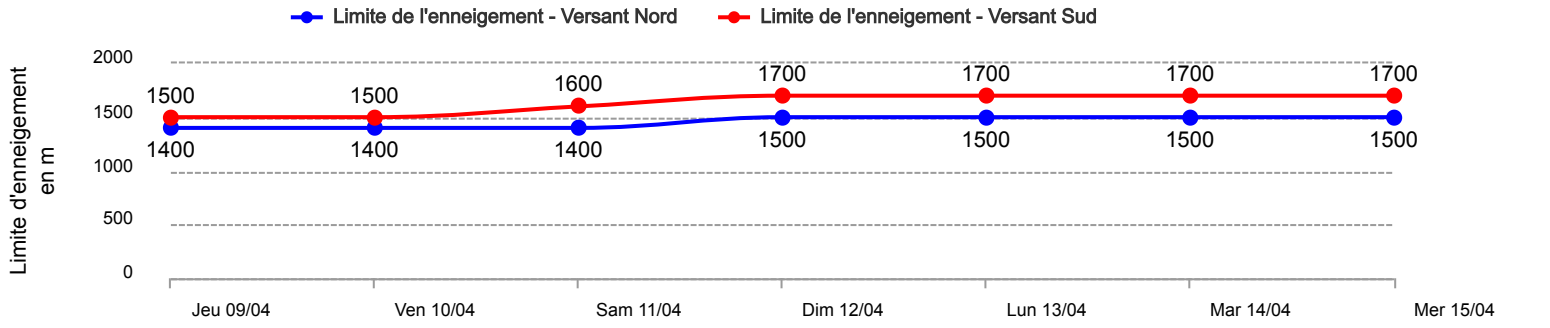

Pour consulter la vigilance en cours, veuillez vous rendre sur le site https://vigilance.meteofrance.fr/fr

Météo-France - 73 avenue de Paris, 94165 Saint-Mandé cedex - Contact : contact@meteo.fr

Rédigé par Météo-France avec la contribution des observateurs du réseau nivo-météorologiques. Partenariat : ANMSM (Maires de Stations de Montagne), DSF (Domaines Skiables de France), ADSP (Directeurs de Pistes et de la Sécurité des Stations de Sports d'Hiver) et autres acteurs de la montagne.

Bulletin neige & avalanches par téléphone au
0 892 68 10 20 Service 0,35 € / min + prix appel