Bulletin d'estimation du risque d'avalanche

(valable en dehors des pistes balisées et ouvertes)

MASSIF : Oisans

Rédigé le mercredi 15 avril 2026 à 16h

Estimation des risques pour le : JEUDI 16 AVRIL

POURSUITE DE L'HUMIDIFICATION, MÊME EN NORD : AVALANCHES HUMIDES POSSIBLES, TRÈS LOCALEMENT VOLUMINEUSES.

2

1 → 2

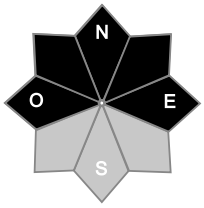

humidification

Indice de risque faible évoluant en limité.

Départs spontanés : Avalanches humides de taille 1 à 2, plus rarement de taille 3 avec départ linéaire non exclu. Plutôt en journée au soleil, mais possibles aussi sous les nuages. Rare avalanche de glissement en pente raide herbeuse.

Déclenchements provoqués : Peu probables ou sous les skis en neige très humide. Très rare plaque en Nord vers les hauts sommets du massif.

Indices de risque : 5 très fort - 4 fort - 3 marqué - 2 limité - 1 faible -- En noir : les pentes les plus dangereuses

Stabilité du manteau neigeux

Situation avalancheuse typique : neige humide — avalanches de fond

Départs spontanés : Au-dessus de la mer de nuages encore présente localement jusqu'à jeudi matin, ils sont assez peu probables au lever du jour avec le bon regel attendu sous ciel dégagé, mais plus bas si la nébulosité est forte, le regel nocturne est souvent absent et la neige poursuit son humidification. Ainsi, des avalanches de neige humide sont possibles à toute heure sous les nuages, puis au fil de la journée également dans les versants bien exposés au soleil et/ou sous les cumulus. Généralement de taille 1 à 2 (petite à moyenne), on ne peut cependant exclure une rare taille 3 (grande) dans un versant d'un large Nord. Dans certaines pentes herbeuses / secteurs de reptation, une avalanche de glissement n'est pas exclue à tout moment de la journée ou de la nuit. Enfin vers les hautes crêtes, un effondrement spontané de corniche n'est pas exclu. A noter que si les faces d'un large Sud sont également très humides, elles sont en neige plus dense/transformée, et le risque d'avalanche volumineuse y est moindre.

Déclenchements provoqués : - Le principal risque pour le pratiquant est de faire couler la neige humide sous les skis, dans une pente raide où la neige est humidifiée jusqu'en profondeur.
- Très ponctuellement vers le coeur des Ecrins, en versant Nord de très haute montagne (plutôt au-dessus de 3000/3200 m), de très rares plaques difficiles à déclencher pourraient encore être présentes dans quelques accumulations de neige récente qui ne serait pas encore humidifiée ou suffisamment tassée.

Autres : Bon regel par endroits le matin en altitude là où le ciel aura été dégagé, avec une neige parfois croutée. En journée neige très humide à "soupe" selon le versant/l'altitude, ski parfois difficile...

Qualité de la neige

Qualification de l'enneigement : L'enneigement s'est dégradé depuis une dizaine de jours mais reste assez important en faces peu ensoleillées et en combes d'altitude....
Limites skiables : Vers 1600m au Nord à 1900/2300m au soleil suivant l'exposition, la raideur de la pente...

Qualité de la neige jeudi : Neige humide, souvent croûtée au petit matin sauf dans la mer de nuages où le regel est souvent absent. La neige poursuit son humidification en profondeur, dans les versants exposés au soleil, mais aussi dans tous les versants concernés par des nuages (effet "cocotte-minute" sous les cumulus de l'après-midi). En Sud, neige de printemps déjà très densifiée.

Aperçu météo pour le jeudi 16 avril

	nuit	matin	après-midi	soir
	2000 m			

Mer de nuages possible jusqu'en matinée de mercredi, se dissipant ensuite. Bourgeonnement de cumulus l'après-midi.

Pluie-Neige				
Iso 0 °C	3100 m	3100 m	3200 m	3200 m
Vent 2500 m	← 5 km/h	↘ 5 km/h	↘ 5 km/h	↖ 5 km/h
Vent 3500 m	↓ 10 km/h	↗ 10 km/h	↗ 10 km/h	↗ 5 km/h

Épaisseur de neige hors-piste

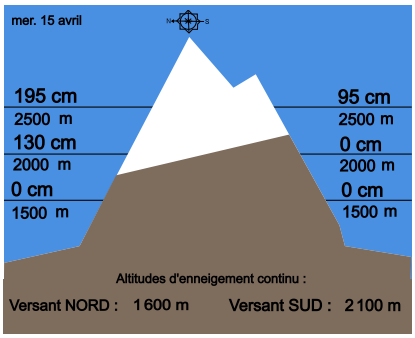

Précipitations à 1800 m

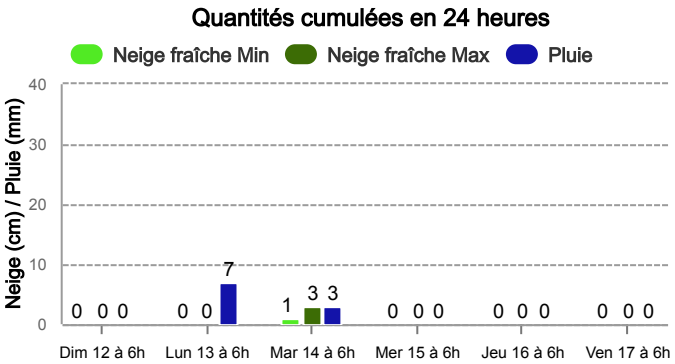

Tendance du vendredi 17 avril

2

Indice de risque limité

Vendredi, risque sans grande évolution. Assez bon regel nocturne (ciel dégagé), et nouvelle journée très douce et ensoleillée avec quelques voiles par moments et des cumulus l'après-midi. Isotherme 0°C vers 3300m.

Pour consulter la vigilance en cours, veuillez vous rendre sur le site https://vigilance.meteofrance.fr/fr

Météo-France - 73 avenue de Paris, 94165 Saint-Mandé cedex - Contact : contact@meteo.fr

Rédigé par Météo-France avec la contribution des observateurs du réseau nivo-météorologiques. Partenariat : ANMSM (Maires de Stations de Montagne), DSF (Domaines Skiables de France), ADSP (Directeurs de Pistes et de la Sécurité des Stations de Sports d'Hiver) et autres acteurs de la montagne.

Bulletin neige & avalanches par téléphone au 0 892 68 10 20 Service 0,35 € / min + prix appel

RÉPUBLIQUE FRANÇAISE
Liberté Égalité Fraternité

METEO FRANCE
À VOS CÔTÉS, DANS UN CLIMAT QUI CHANGE

Bulletin d'estimation du risque d'avalanche
(valable en dehors des pistes balisées et ouvertes)

MASSIF : Oisans

Rédigé le mercredi 15 avril 2026 à 16h

Conditions nivo-météo des 7 derniers jours

	jeu. 09/04				ven. 10/04				sam. 11/04				dim. 12/04				lun. 13/04				mar. 14/04				mer. 15/04			
	03h	09h	15h	21h	03h	09h	15h	21h	03h	09h	15h	21h	03h	09h	15h	21h	03h	09h	15h	21h	03h	09h	15h	21h	03h	09h	15h	21h
Météo																												
Vent (km/h)	5	10	10	20	20	15	10	10	25	25	20	25	25	30	30	30	40	45	30	20	20	15	15	20	15	10	10	10
à 3500m																												
Vent (km/h)	5	0	5	5	5	0	5	5	10	10	15	15	15	15	20	20	25	30	10	15	10	10	10	10	5	5	5	5
à 2500m																												

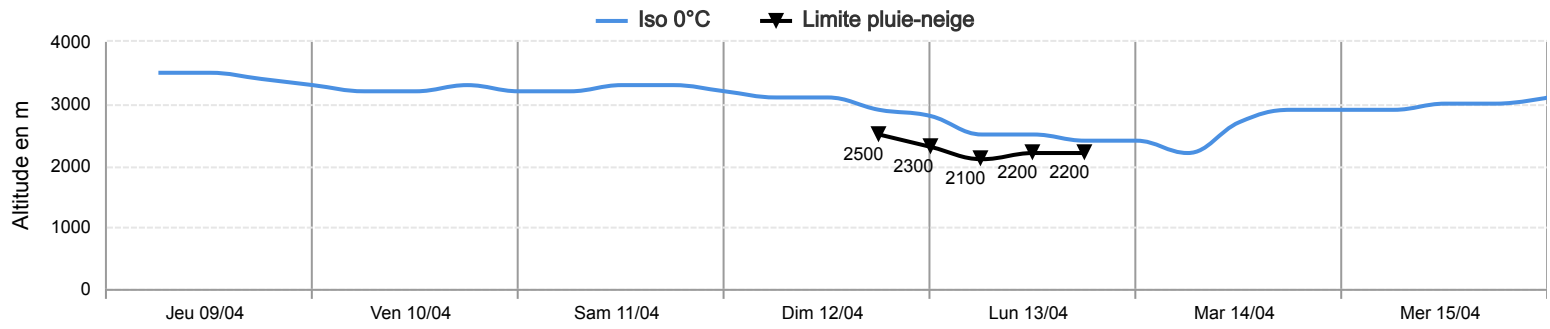

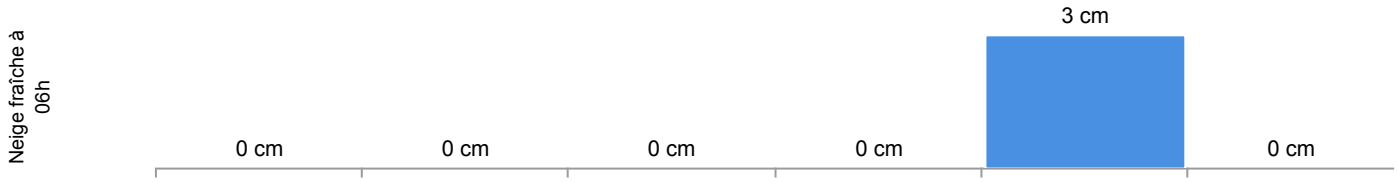

Risque d'avalanche	jeu. 09/04	ven. 10/04	sam. 11/04	dim. 12/04	lun. 13/04	mar. 14/04	mer. 15/04
	2	2	2	2	2	2	2

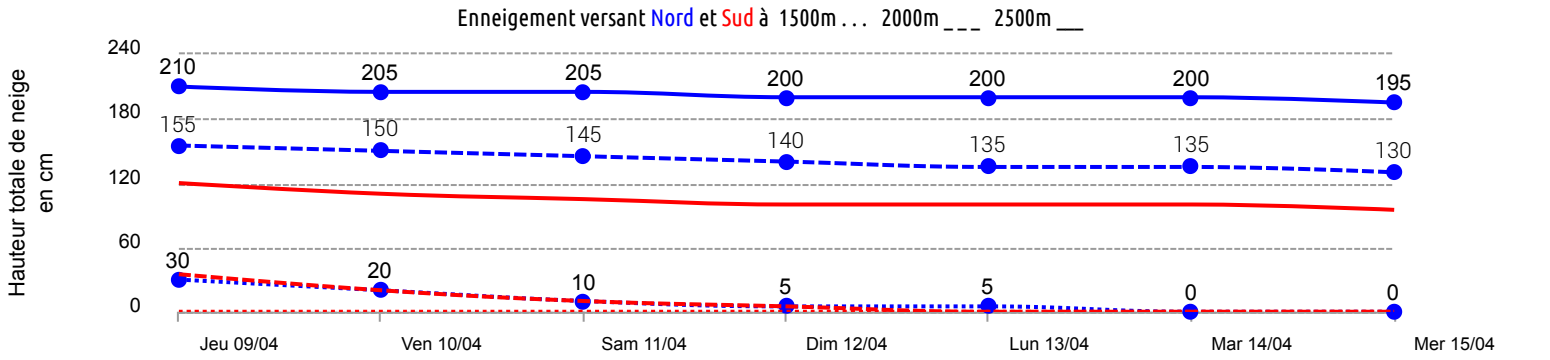

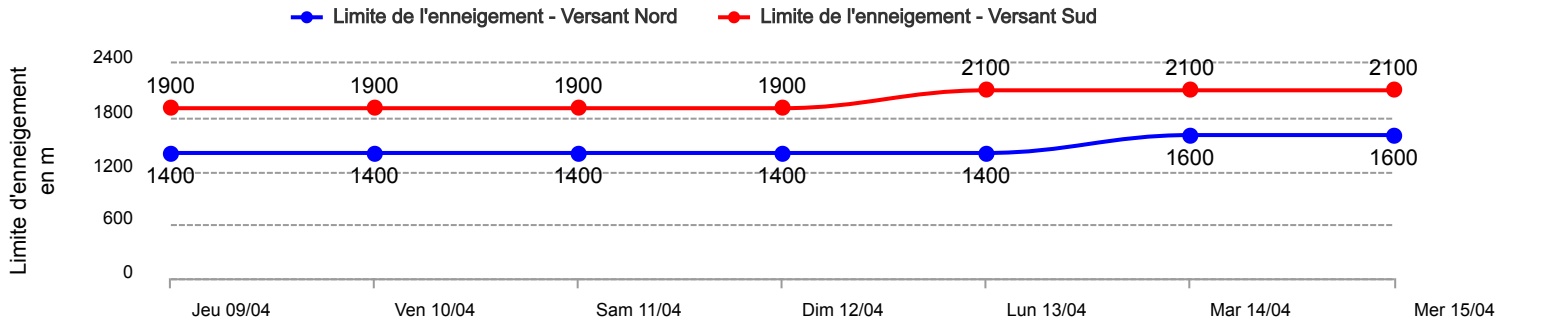

Pour consulter la vigilance en cours, veuillez vous rendre sur le site https://vigilance.meteofrance.fr/fr

Météo-France - 73 avenue de Paris, 94165 Saint-Mandé cedex - Contact : contact@meteo.fr

Bulletin neige & avalanches par téléphone au
0 892 68 10 20 Service 0,35 € / min + prix appel

Rédigé par Météo-France avec la contribution des observateurs du réseau nivo-météorologiques. Partenariat : ANMSM (Maires de Stations de Montagne), DSF (Domaines Skiables de France), ADSP (Directeurs de Pistes et de la Sécurité des Stations de Sports d'Hiver) et autres acteurs de la montagne.