Bulletin d'estimation du risque d'avalanche

(valable en dehors des pistes balisées et ouvertes)

MASSIF : Orlu St-Barthelemy

Rédigé le mercredi 15 avril 2026 à 16h

Estimation des risques pour le : JEUDI 16 AVRIL

ACTIVITÉ EN NEIGE HUMIDE EN JOURNÉE AVEC L'ENSOLEILLEMENT, ENCORE DES PLAQUES EN ALTITUDE.

2

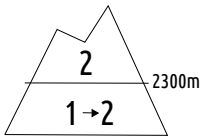

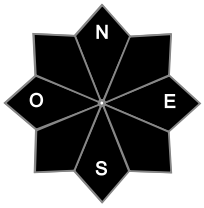

Au-dessus de 2300m indice de risque limité, plus bas indice faible évoluant en limité.

Départs spontanés : Départs plutôt ponctuels en neige humide

Déclenchements provoqués : Persistance de rares plaques en altitude

Indices de risque : 5 très fort - 4 fort - 3 marqué - 2 limité - 1 faible -- En noir : les pentes les plus dangereuses

Stabilité du manteau neigeux

Situation avalancheuse typique : neige humide — neige ventée

Départs spontanés :
- Peu probable en début de journée grâce à un regel efficace. Au fil de la journée, dans les pentes ensoleillées, des départs spontanés d'avalanches de taille petite à moyenne sont attendus avec la douceur et l'ensoleillement. Ces départs emportent la neige récente, et dans de rares cas des couches plus anciennes avec une éventuelle avalanche de moyenne, voire grande taille.
- De nombreuses reptations sont également visibles et signes avant-coureurs de potentielles avalanches de glissement pouvant emporter l'ensemble du manteau neigeux.

Déclenchements provoqués :
- Avalanches de plaques, encore déclenchables par un pratiquant, sur Orlu et au-dessus de 2300/2400m. Des accumulations en neige récente non encore humidifiée subsistent par endroits, plutôt à proximité des crêtes et dans les secteurs ombragés. Ces plaques peu épaisses et plus ou moins friables se sont formées ces derniers jours avec le vent de nord. Les accumulations de neige ventée reposent sur une couche de neige tombée sans vent. *Observables : signe de transport de neige par le vent avec de la neige de surface changeante, fissures devant les skis.*
- Par ailleurs, dans les secteurs en neige humide, un skieur coupant une pente raide pourra également déclencher une coulée sous ses skis.

Autre : Des corniches, parfois imposantes, sont en place et sont susceptibles de céder spontanément.

Qualité de la neige

Enneigement :
Excellent, parmi un des meilleurs des 30 dernières années. Avec le redoux et le soleil, la limite skiable remonte vers 1500 m en nord et 1700 m voire 1800 m en sud pour trouver une sous-couche. L'épaisseur de neige augmente rapidement et dépasse souvent les 2m dès 1900/200m, et 3 à 4 m vers 2500m.

Qualité de la neige :
Conditions printanières avec un bon regel portant jeudi matin sauf en forêt. En journée, reprise de l'humidification avec la neige récente qui s'humidifie rapidement au soleil. Encore de rares endroits en neige sèche et plus légère dans les versants nord raides ou à l'ombre au-dessus de 2300/2400m. Les cols et crêtes restent en neige plus dure et sous souvent moins garnis en neige.

Aperçu météo pour le jeudi 16 avril

nuit	matin	après-midi	soir

Belle journée douce et ensoleillée avec tout au plus quelques nuages l'après-midi. Vent d'ouest à nord-ouest souvent peu sensible.

Pluie-Neige				
Iso 0 °C	3 000 m	3 300 m	3 300 m	3 400 m
Vent 2000 m	→ 20 km/h	↓ 15 km/h	↓ 15 km/h	↗ 15 km/h
Vent 3000 m	↘ 30 km/h	↘ 25 km/h	→ 25 km/h	↘ 30 km/h

Épaisseur de neige hors-piste

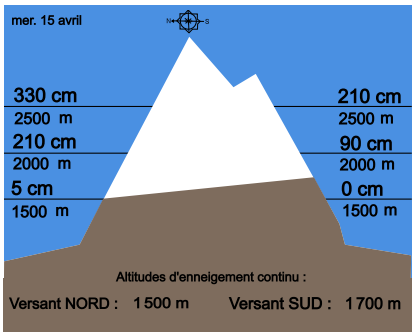

Précipitations à 1800 m

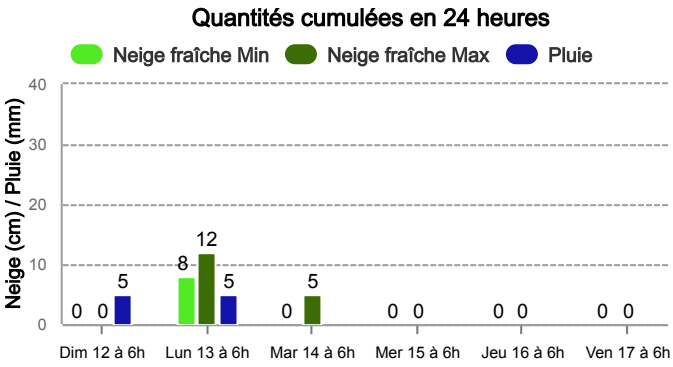

Tendance du vendredi 17 avril

2

Indice de risque limité

Peu d'évolution de la situation nivo-météorologique avec un nouveau cycle de gel-dégel et la poursuite de l'humidification progressive.

Pour consulter la vigilance en cours, veuillez vous rendre sur le site https://vigilance.meteofrance.fr/fr

Météo-France - 73 avenue de Paris, 94165 Saint-Mandé cedex - Contact : contact@meteo.fr

Rédigé par Météo-France avec la contribution des observateurs du réseau nivo-météorologiques. Partenariat : ANMSM (Maires de Stations de Montagne), DSF (Domaines Skiables de France), ADSP (Directeurs de Pistes et de la Sécurité des Stations de Sports d'Hiver) et autres acteurs de la montagne.

Bulletin neige & avalanches par téléphone au 0 892 68 10 20 Service 0,35 € / min + prix appel

RÉPUBLIQUE FRANÇAISE
Liberté Égalité Fraternité

METEO FRANCE
À VOS CÔTÉS, DANS UN CLIMAT QUI CHANGE

Bulletin d'estimation du risque d'avalanche

(valable en dehors des pistes balisées et ouvertes)

MASSIF : Orlu St-Barthelemy

Rédigé le mercredi 15 avril 2026 à 16h

Conditions nivo-météo des 7 derniers jours

	jeu. 09/04				ven. 10/04				sam. 11/04				dim. 12/04				lun. 13/04				mar. 14/04				mer. 15/04			
	03h	09h	15h	21h	03h	09h	15h	21h	03h	09h	15h	21h	03h	09h	15h	21h	03h	09h	15h	21h	03h	09h	15h	21h	03h	09h	15h	21h
Météo																												
Vent (km/h)	15	20	30	30	35	25	25	35	35	35	50	50	45	40	30	25	50	50	55	55	50	50	50	45	35	25	25	25
à 3000m																												
Vent (km/h)	10	15	20	20	20	15	15	20	20	20	35	35	20	15	15	25	35	30	30	25	25	25	25	20	20	15	15	15
à 2000m																												

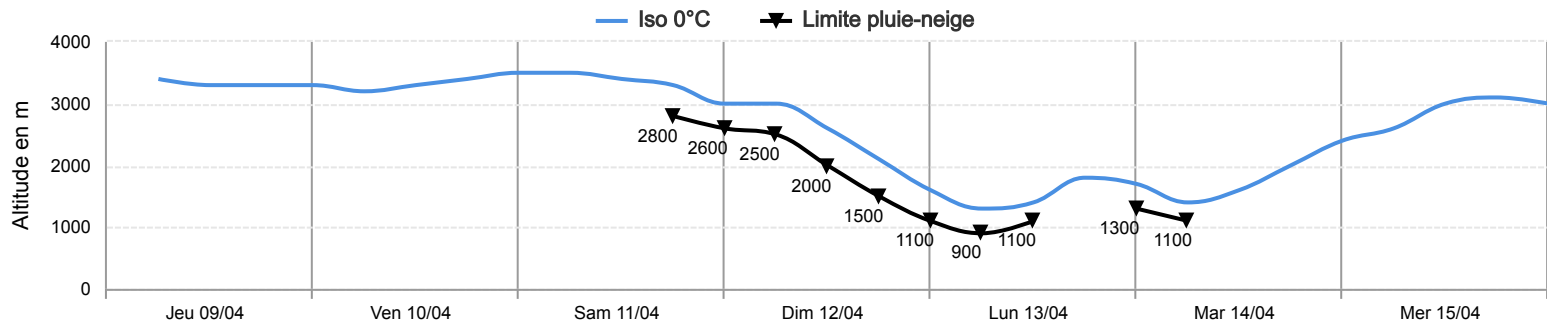

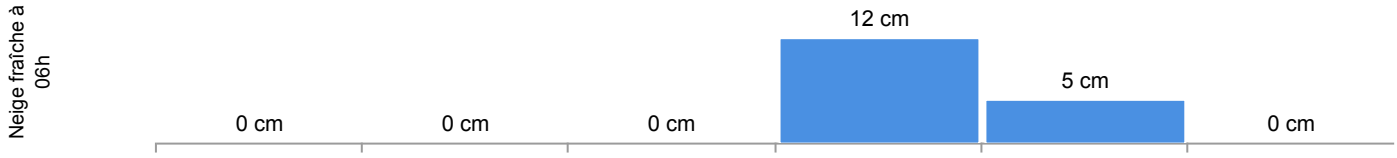

Risque d'avalanche	jeu. 09/04	ven. 10/04	sam. 11/04	dim. 12/04	lun. 13/04	mar. 14/04	mer. 15/04
	2	2	3	2	3	2	2

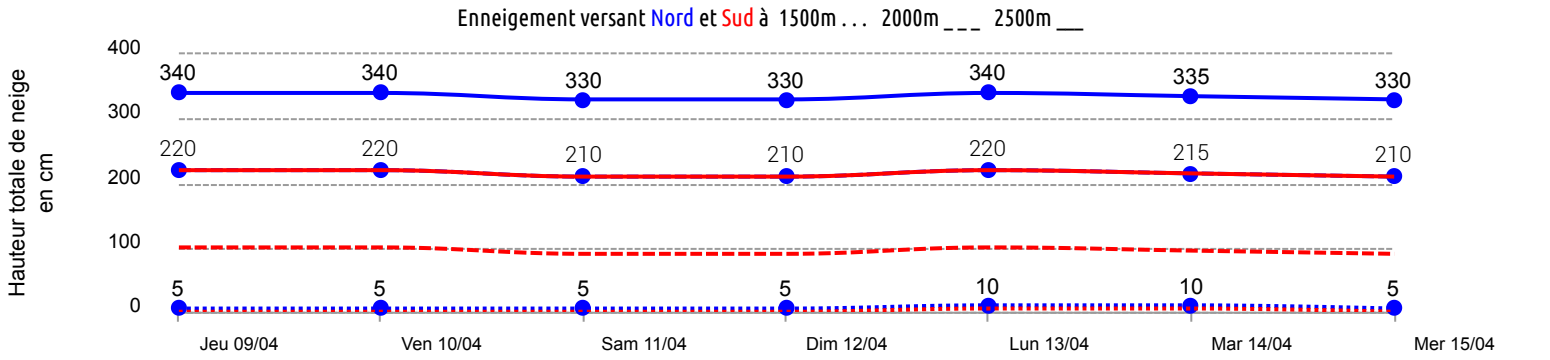

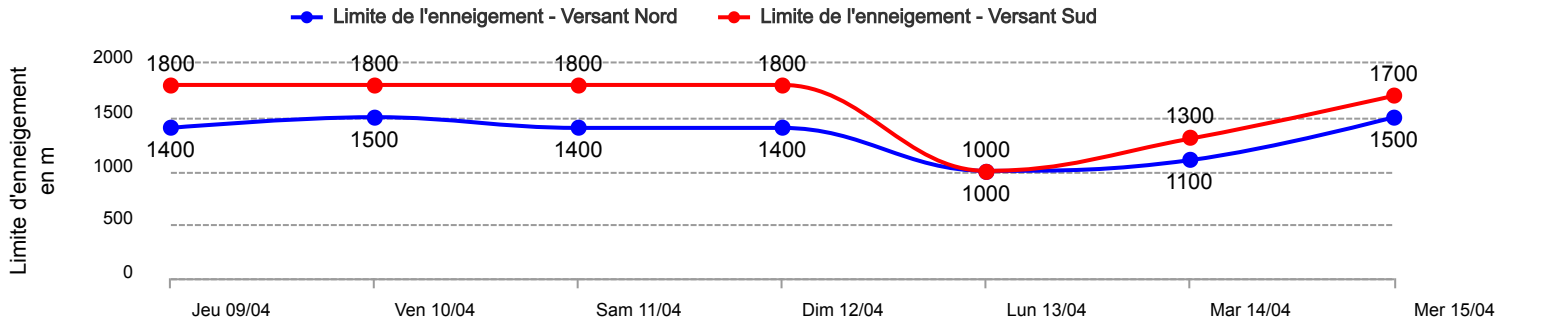

Pour consulter la vigilance en cours, veuillez vous rendre sur le site https://vigilance.meteofrance.fr/fr

Météo-France - 73 avenue de Paris, 94165 Saint-Mandé cedex - Contact : contact@meteo.fr

Bulletin neige & avalanches par téléphone au

0 892 68 10 20 Service 0,35 € / min + prix appel

Rédigé par Météo-France avec la contribution des observateurs du réseau nivo-météorologiques. Partenariat : ANMSM (Maires de Stations de Montagne), DSF (Domaines Skiables de France), ADSP (Directeurs de Pistes et de la Sécurité des Stations de Sports d'Hiver) et autres acteurs de la montagne.