Bulletin d'estimation du risque d'avalanche

(valable en dehors des pistes balisées et ouvertes)

MASSIF : Renoso Incudine

Rédigé le mercredi 15 avril 2026 à 16h

Estimation des risques pour le : JEUDI 16 AVRIL

DÉPARTS EN NEIGE HUMIDE

2

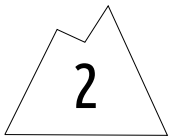

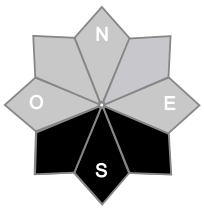

Indice de risque limité.

Départs spontanés : Avalanches de neige humide, surtout en journée, dans les pentes raides et bien ensoleillées

Déclenchements provoqués : Peu probables

Indices de risque : 5 très fort - 4 fort - 3 marqué - 2 limité - 1 faible -- En noir : les pentes les plus dangereuses

Stabilité du manteau neigeux

Situation avalancheuse typique : neige humide

Départs spontanés : Après les fortes pluies des jours passés, la teneur en eau liquide est élevée dans les premières couches, parfois sur toute l'épaisseur du manteau neigeux. Sous l'effet de la douceur et de l'ensoleillement, l'humidification se poursuit, dans toutes les orientations. Des coulées de neige humide et avalanches de taille moyenne se produisent, surtout en journée, dans les pentes raides et bien ensoleillées.
Déclenchements provoqués : Peu probables. Un randonneur peut provoquer un départ ponctuel en surface dans la neige humide en coupant une pente raide très humidifiée.
Autres : Présence de corniches, susceptibles de rompre à cause des conditions printanières. Persistance de surfaces dures et glacées au-dessus de 2000 à 2200 m.

Qualité de la neige

Qualification de l'enneigement : L'enneigement est encore très bon pour la saison. On relève plus de 3m de neige à Ghisoni au-dessus du lac de Bastani, vers 2100 m d'altitude.
Limite d'enneigement skiable : vers 1600 m en Nord, 1800 m en Sud.
État de la neige : Regel nocturne correct en versants Nord en altitude, inexistant en dessous de 2000 à 2200 m. Rapide humidification en matinée. En moyenne montagne, neige très humide à pourrie.
Près des crêtes au-dessus de 2200 m en Nord, surface du manteau neigeux assez hétérogène avec alternance de neige dure et travaillée par le vent, de neige colorée par le sable décaillant à peine l'après-midi et présence d'une vieille neige récente, dense.

Aperçu météo pour le jeudi 16 avril

L'isotherme zéro degré s'élève au-dessus de 3000m. Risque d'une petite averse de pluie l'après-midi.

	nuit	matin	après-midi	soir
Pluie-Neige		2 800 m		
Iso 0 °C	3 000 m	3 100 m	3 100 m	3 200 m
Vent 1500 m	↓ 20 km/h	↓ 15 km/h	↻ 10 km/h	↙ 15 km/h
Vent 2000 m	↓ 20 km/h	↓ 15 km/h	↓ 15 km/h	↙ 20 km/h

Épaisseur de neige hors-piste

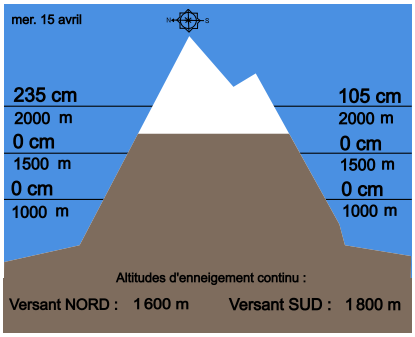

Précipitations à 1800 m

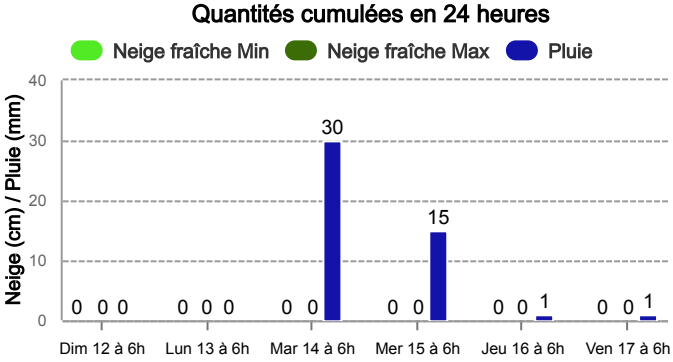

Tendance du vendredi 17 avril

2

Indice de risque limité

Risque stationnaire, toujours lié à la neige humide.

Pour consulter la vigilance en cours, veuillez vous rendre sur le site https://vigilance.meteofrance.fr/fr

Météo-France - 73 avenue de Paris, 94165 Saint-Mandé cedex - Contact : contact@meteo.fr

Rédigé par Météo-France avec la contribution des observateurs du réseau nivo-météorologiques. Partenariat : ANMSM (Maires de Stations de Montagne), DSF (Domaines Skiables de France), ADSP (Directeurs de Pistes et de la Sécurité des Stations de Sports d'Hiver) et autres acteurs de la montagne.

Bulletin neige & avalanches par téléphone au

0 892 68 10 20 Service 0,35 € / min + prix appel

RÉPUBLIQUE FRANÇAISE
Liberté Égalité Fraternité

METEO FRANCE
À VOS CÔTÉS, DANS UN CLIMAT QUI CHANGE

Bulletin d'estimation du risque d'avalanche

(valable en dehors des pistes balisées et ouvertes)

MASSIF : Renoso Incudine

Rédigé le mercredi 15 avril 2026 à 16h

Conditions nivo-météo des 7 derniers jours

	jeu. 09/04				ven. 10/04				sam. 11/04				dim. 12/04				lun. 13/04				mar. 14/04				mer. 15/04			
	03h	09h	15h	21h	03h	09h	15h	21h	03h	09h	15h	21h	03h	09h	15h	21h	03h	09h	15h	21h	03h	09h	15h	21h	03h	09h	15h	21h
Météo																												
Vent (km/h)	15	20	35	35	35	25	15	20	30	15	5	0	10	30	15	45	70	40	25	10	10	10	20	25	30	30	30	25
à 2000m																												
Vent (km/h)	15	20	35	30	30	25	25	15	20	20	20	10	15	40	30	35	55	40	25	10	15	15	20	25	30	30	30	25
à 1500m																												

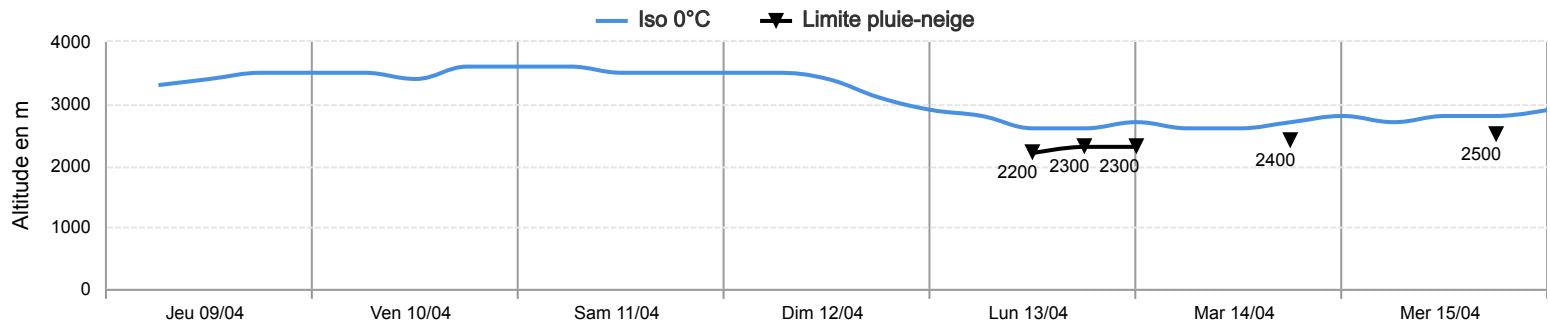

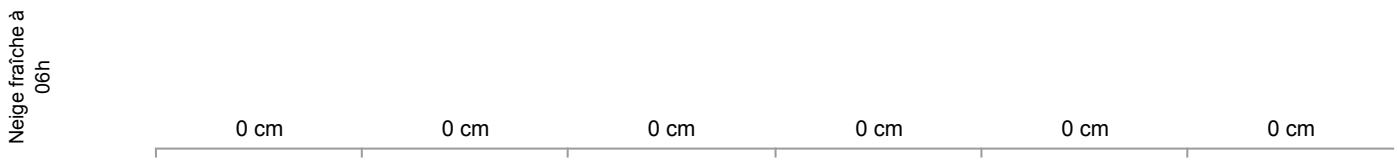

Risque d'avalanche	jeu. 09/04	ven. 10/04	sam. 11/04	dim. 12/04	lun. 13/04	mar. 14/04	mer. 15/04
	2	2	2	2	2	3	3

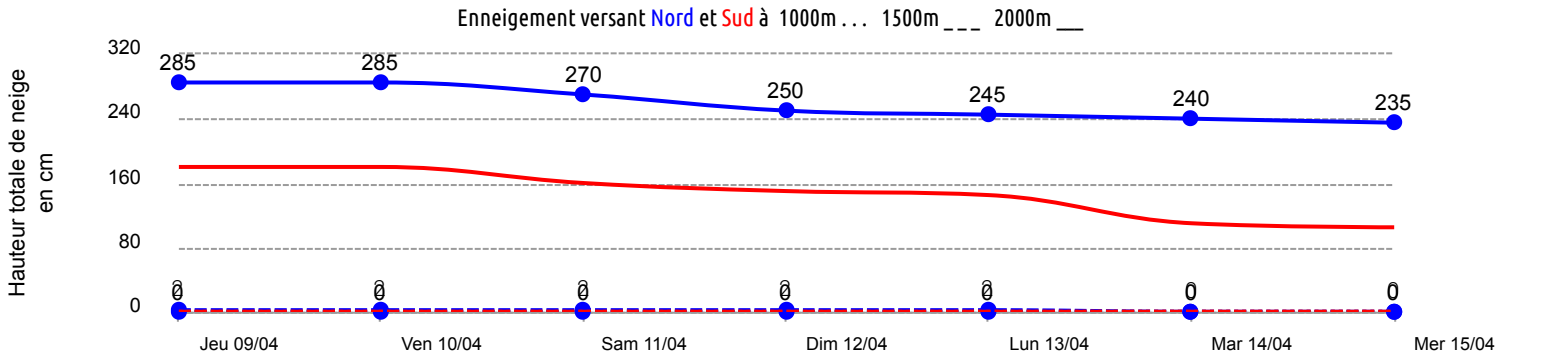

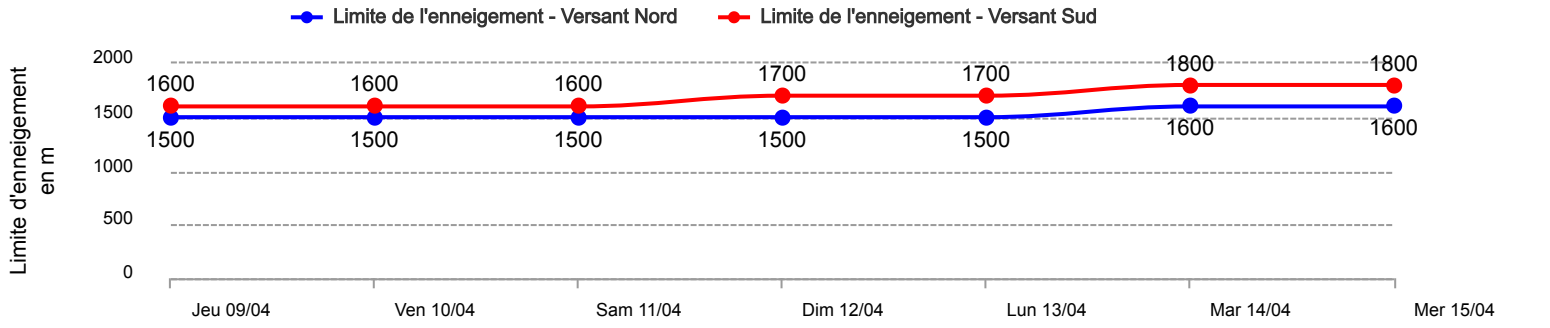

Pour consulter la vigilance en cours, veuillez vous rendre sur le site https://vigilance.meteofrance.fr/fr

Météo-France - 73 avenue de Paris, 94165 Saint-Mandé cedex - Contact : contact@meteo.fr

Bulletin neige & avalanches par téléphone au

0 892 68 10 20 Service 0,35 € / min + prix appel

Rédigé par Météo-France avec la contribution des observateurs du réseau nivo-météorologiques. Partenariat : ANMSM (Maires de Stations de Montagne), DSF (Domaines Skiables de France), ADSP (Directeurs de Pistes et de la Sécurité des Stations de Sports d'Hiver) et autres acteurs de la montagne.