RÉPUBLIQUE FRANÇAISE
Liberté Égalité Fraternité

METEO FRANCE
À VOS CÔTÉS, DANS UN CLIMAT QUI CHANGE

Bulletin d'estimation du risque d'avalanche
(valable en dehors des pistes balisées et ouvertes)

MASSIF : Thabor

Rédigé le mercredi 15 avril 2026 à 16h

Estimation des risques pour le : JEUDI 16 AVRIL

ACTIVITÉ NATURELLE AU SOLEIL - RARES PLAQUES À PROXIMITÉ DE L'ITALIE

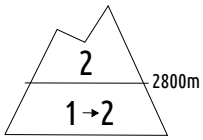

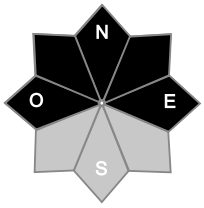

Au-dessus de 2800m indice de risque limité, plus bas indice faible évoluant en limité.

Départs spontanés : en neige humide au soleil, rarement volumineux.

Déclenchements provoqués : en neige humide sous les skis.

Indices de risque : 5 très fort - 4 fort - 3 marqué - 2 limité - 1 faible -- En noir : les pentes les plus dangereuses

Stabilité du manteau neigeux

Situation avalancheuse typique : neige humide neige ventée

Départs spontanés : peu probables au petit matin après un regel nocturne correct, puis reprise rapide de l'activité en neige humide au fil de la course du soleil. Avalanches de taille petite à moyenne (taille 1 à 2). Un rare départ linéaire de plus grande taille (taille 3), est possible, dans les versants d'un large secteur nord au-dessus de 2400/2800 m environ, si l'humidification, gagnant en profondeur, atteint pour la première fois des couches fragiles persistantes enfouies à la base du manteau neigeux.

Déclenchements provoqués : plaques en place surtout sur le secteur frontalier à haute altitude, formées par les chutes de neige de lundi. Elles sont facilement identifiables, présentes en toute orientation et peuvent encore être déclenchées par le passage d'un skieur, générant alors des avalanches de taille petite à moyenne. Sous 2800 m, un pratiquant évoluant tardivement peut déclencher un départ de neige humide sous les skis. Avalanches généralement de taille moyenne, rarement grande, notamment dans les orientations est, nord-est, nord-ouest et ouest.

Qualité de la neige

Enneigement déficitaire pour une mi-avril en adrets, plus proche des normales en ubacs d'altitude.
Hauteurs de neige observées vers 2500 m : 132 cm dans le vallon du Chardonnet, 97 cm aux Rochilles, 50 cm dans le vallon de Roche Noire vers le Galibier.

Limite d'enneigement skiable : vers 1600/1700 m en ubacs favorables (terrains herbeux, pistes forestières), 2100/2200 m en adrets pas trop raides.

État de la neige de surface : neige en cycle printanier. Après un regel nocturne correct, reprise rapide de l'humidification au soleil. Dans les ubacs raides aux plus hautes altitudes du massif, neige encore froide, souvent durcie ou travaillée par le vent dans les secteurs exposés, parfois plus légère dans les combes ou pentes abritées.

Aperçu météo pour le jeudi 16 avril

	nuit	matin	après-midi	soir

Temps calme et doux. 14° à 2000 m et 5° à 3000 m

Pluie-Neige				
Iso 0 °C	3 000 m	3 100 m	3 200 m	3 100 m
Vent 2000 m	↘ 10 km/h	↘ 15 km/h	↘ 15 km/h	↑ 5 km/h
Vent 3000 m	↓ 15 km/h	↓ 15 km/h	↘ 15 km/h	↖ 5 km/h

Épaisseur de neige hors-piste

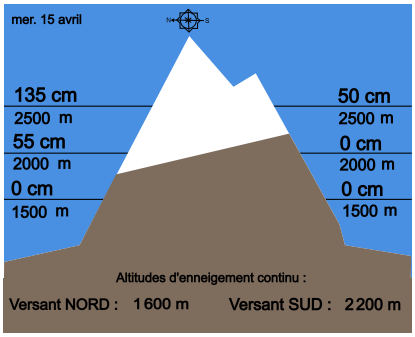

Précipitations à 1800 m

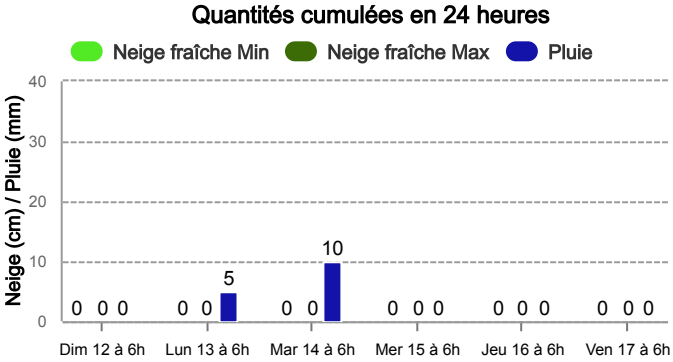

Tendance du vendredi 17 avril

Indice de risque limité

Peu d'évolution du risque qui reste limité.
Après un regel nocturne souvent correct, l'humidification reprend au soleil en journée.

Pour consulter la vigilance en cours, veuillez vous rendre sur le site https://vigilance.meteofrance.fr/fr

Météo-France - 73 avenue de Paris, 94165 Saint-Mandé cedex - Contact : contact@meteo.fr

Rédigé par Météo-France avec la contribution des observateurs du réseau nivo-météorologiques. Partenariat : ANMSM (Maires de Stations de Montagne), DSF (Domaines Skiables de France), ADSP (Directeurs de Pistes et de la Sécurité des Stations de Sports d'Hiver) et autres acteurs de la montagne.

Bulletin neige & avalanches par téléphone au
0 892 68 10 20 Service 0,35 € / min + prix appel

Bulletin d'estimation du risque d'avalanche

(valable en dehors des pistes balisées et ouvertes)

MASSIF : Thabor

Rédigé le mercredi 15 avril 2026 à 16h

Conditions nivo-météo des 7 derniers jours

	jeu. 09/04				ven. 10/04				sam. 11/04				dim. 12/04				lun. 13/04				mar. 14/04				mer. 15/04			
	03h	09h	15h	21h	03h	09h	15h	21h	03h	09h	15h	21h	03h	09h	15h	21h	03h	09h	15h	21h	03h	09h	15h	21h	03h	09h	15h	21h
Météo																												
Vent (km/h)	15	25	30	35	30	30	35	25	20	15	15	20	25	25	30	40	35	30	25	20	15	15	15	15	15	15	15	10
à 3000m																												
Vent (km/h)	10	15	25	25	20	20	25	15	10	10	15	10	15	25	15	15	15	15	20	20	15	15	15	10	10	15	15	10
à 2000m																												

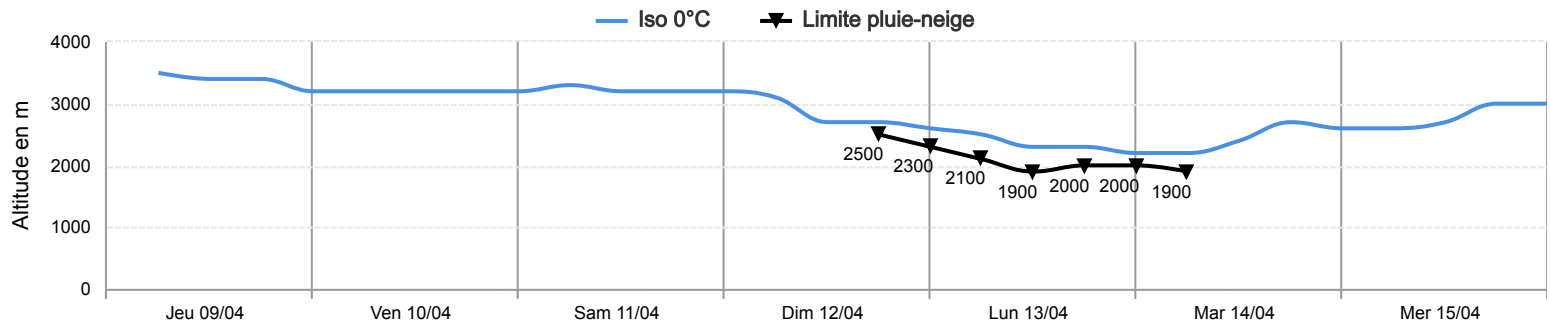

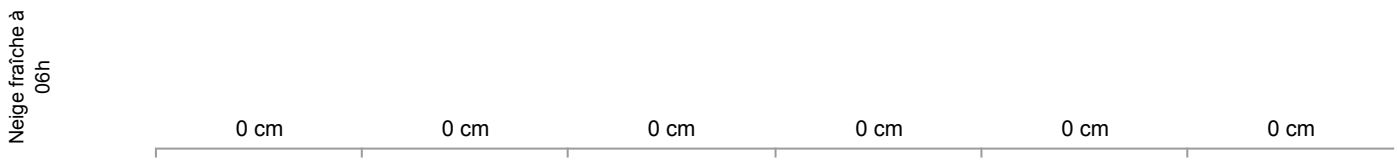

Risque d'avalanche	jeu. 09/04	ven. 10/04	sam. 11/04	dim. 12/04	lun. 13/04	mar. 14/04	mer. 15/04
	3	3	3	2	2	2	2

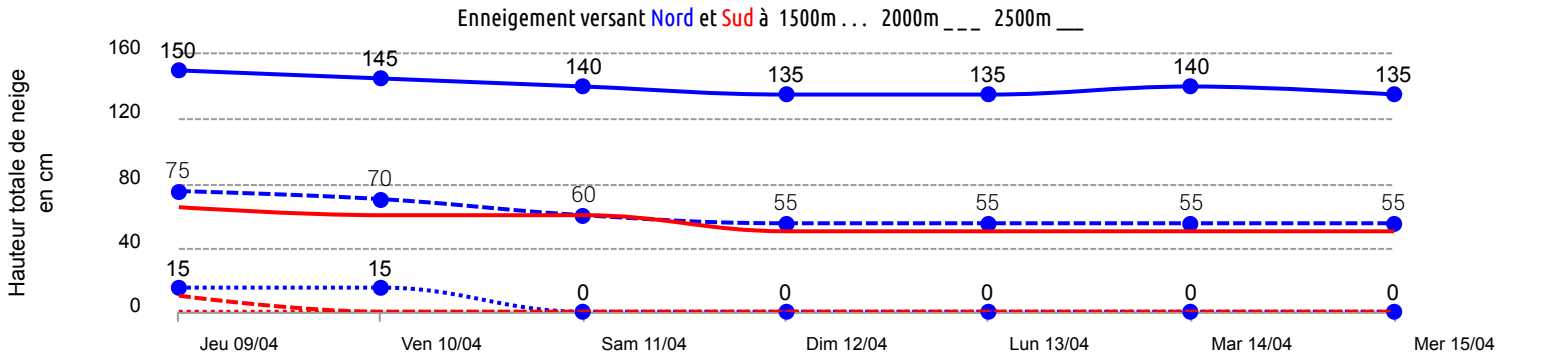

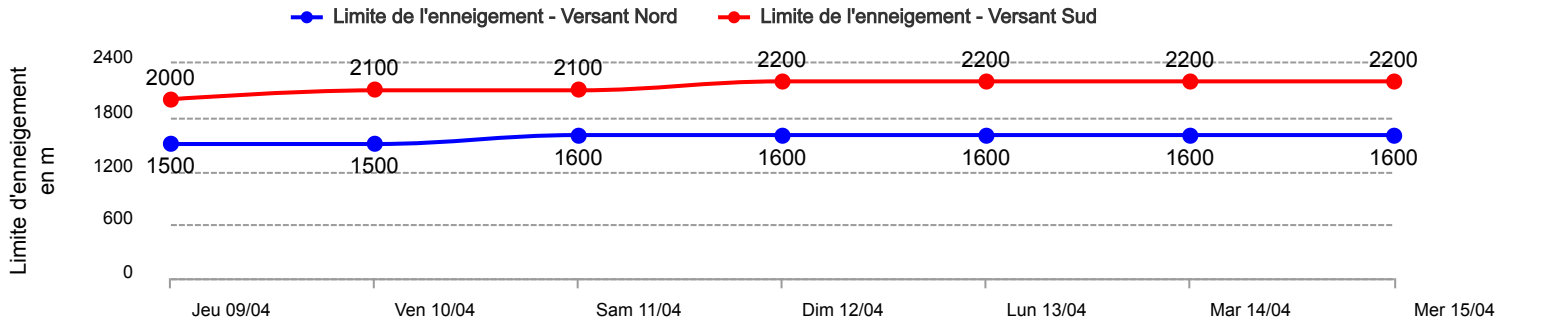

Pour consulter la vigilance en cours, veuillez vous rendre sur le site https://vigilance.meteofrance.fr/fr

Météo-France - 73 avenue de Paris, 94165 Saint-Mandé cedex - Contact : contact@meteo.fr

Rédigé par Météo-France avec la contribution des observateurs du réseau nivo-météorologiques. Partenariat : ANMSM (Maires de Stations de Montagne), DSF (Domaines Skiables de France), ADSP (Directeurs de Pistes et de la Sécurité des Stations de Sports d'Hiver) et autres acteurs de la montagne.

Bulletin neige & avalanches par téléphone au

0 892 68 10 20 Service 0,35 € / min + prix appel