Bulletin d'estimation du risque d'avalanche
(valable en dehors des pistes balisées et ouvertes)

MASSIF : Vercors

Rédigé le mercredi 15 avril 2026 à 16h

Estimation des risques pour le : JEUDI 16 AVRIL

POURSUITE DE L'HUMIDIFICATION, MÊME EN NORD : QUELQUES DÉPARTS HUMIDES POSSIBLES, PARFOIS AU TERRAIN.

2

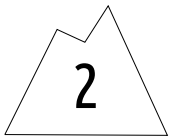

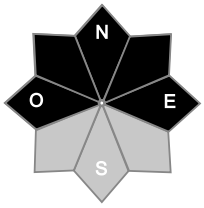

humidification

Indices de risque : 5 très fort - 4 fort - 3 marqué - 2 limité - 1 faible -- En noir : les pentes les plus dangereuses

Indice de risque limité.

Départs spontanés : Quelques avalanches humides de taille 1 à 2, possibles à toute heure. Rare taille 3 non exclue. Départ au terrain non exclu en pente raide herbeuse.

Déclenchements provoqués : Peu probables ou sous les skis en neige très humide.

Stabilité du manteau neigeux

Situation avalancheuse typique : neige humide avalanches de fond

Départs spontanés : Quelques avalanches de neige humide sont possibles sous les nuages qui humidifient tous les versants qu'ils recouvrent, y compris dans la nuit (mauvais regel attendu en général), puis en cours de journée de jeudi dans les pentes réchauffées par le soleil et sous les cumulus. Généralement de taille 1 à 2 (petite à moyenne), on ne peut cependant exclure une rare taille 3 (grande) dans un versant d'un large Nord. Par ailleurs, dans certaines pentes herbeuses / secteurs de reptation, une avalanche de glissement n'est pas exclue. Enfin vers les hautes crêtes, un effondrement spontané de corniche n'est pas exclu. A noter que si les faces d'un large Sud sont également très humides, elles sont en neige plus dense/transformée, et le risque d'avalanche volumineuse y est moindre.

Déclenchements provoqués : Le principal risque pour le pratiquant est de faire couler la neige humide sous les skis, dans une pente raide où la neige est humidifiée jusqu'en profondeur.

Autres : Neige très humide à "soupe" selon le versant/l'altitude, ski parfois difficile...

Qualité de la neige

Qualification de l'enneigement : L'enneigement a nettement régressé depuis une dizaine de jours, et ne reste correct que sur les hauts du massif en pentes peu ensoleillées. Un peu de fraîche lundi sur l'Ouest du massif, saupoudrage ailleurs.
Limites skiables : Vers 1400 à 1800m selon le versant (hors sapins), plein Sud sec...

Qualité de la neige jeudi : Peu ou pas de regel nocturne sous les nuages attendus. Neige humide poursuivant son humidification en profondeur, au soleil en cas d'éclaircies, mais aussi sous les nuages en tous versants (effet "cocotte-minute" sous les cumulus de l'après-midi). En Sud, neige de printemps déjà très densifiée.

Aperçu météo pour le jeudi 16 avril

	nuit	matin	après-midi	soir

Mer de nuages possible jusqu'en matinée de mercredi, puis davantage d'éclaircies. Bourgeonnement de cumulus l'après-midi.

Pluie-Neige				
Iso 0 °C	3 100 m	3 100 m	3 200 m	3 300 m
Vent 1500 m	↓ 20 km/h	↓ 25 km/h	↓ 20 km/h	↙ 10 km/h
Vent 2000 m	↙ 25 km/h	↙ 30 km/h	↙ 25 km/h	↙ 15 km/h

Épaisseur de neige hors-piste

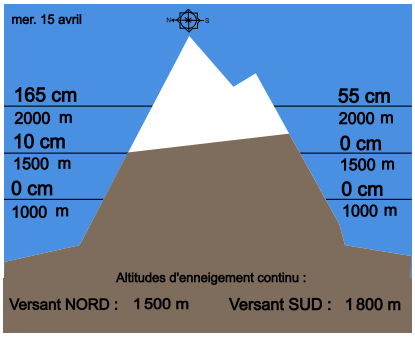

Précipitations à 1800 m

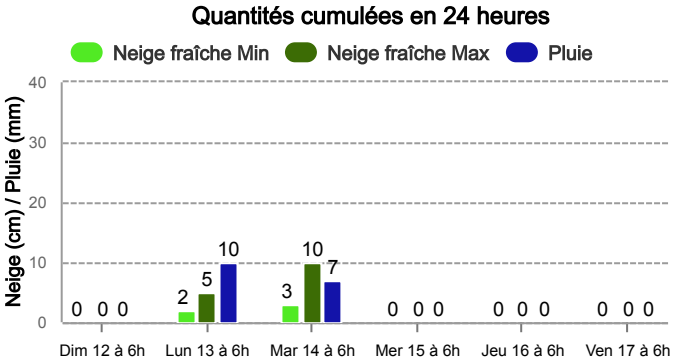

Tendance du vendredi 17 avril

2

Indice de risque limité

Vendredi, risque sans grande évolution. Meilleur regel nocturne (ciel plus dégagé), et nouvelle journée très douce et ensoleillée avec quelques voiles par moments et des cumulus l'après-midi. Isotherme 0°C vers 3300m.

Pour consulter la vigilance en cours, veuillez vous rendre sur le site https://vigilance.meteofrance.fr/fr

Météo-France - 73 avenue de Paris, 94165 Saint-Mandé cedex - Contact : contact@meteo.fr

Rédigé par Météo-France avec la contribution des observateurs du réseau nivo-météorologiques. Partenariat : ANMSM (Maires de Stations de Montagne), DSF (Domaines Skiables de France), ADSP (Directeurs de Pistes et de la Sécurité des Stations de Sports d'Hiver) et autres acteurs de la montagne.

Bulletin neige & avalanches par téléphone au
0 892 68 10 20 Service 0,35 € / min + prix appel

RÉPUBLIQUE FRANÇAISE
Liberté Égalité Fraternité

METEO FRANCE
À VOS CÔTÉS, DANS UN CLIMAT QUI CHANGE

Bulletin d'estimation du risque d'avalanche

(valable en dehors des pistes balisées et ouvertes)

MASSIF : Vercors

Rédigé le mercredi 15 avril 2026 à 16h

Conditions nivo-météo des 7 derniers jours

	jeu. 09/04				ven. 10/04				sam. 11/04				dim. 12/04				lun. 13/04				mar. 14/04				mer. 15/04			
	03h	09h	15h	21h	03h	09h	15h	21h	03h	09h	15h	21h	03h	09h	15h	21h	03h	09h	15h	21h	03h	09h	15h	21h	03h	09h	15h	21h
Météo																												
Vent (km/h)	15	15	25	45	40	35	25	20	20	25	20	15	25	15	15	10	15	20	35	35	35	40	40	35	35	15	20	15
à 2000m																												
Vent (km/h)	10	10	20	25	20	30	20	10	15	15	20	10	15	15	20	15	15	20	30	30	35	35	35	25	20	10	15	15
à 1500m																												

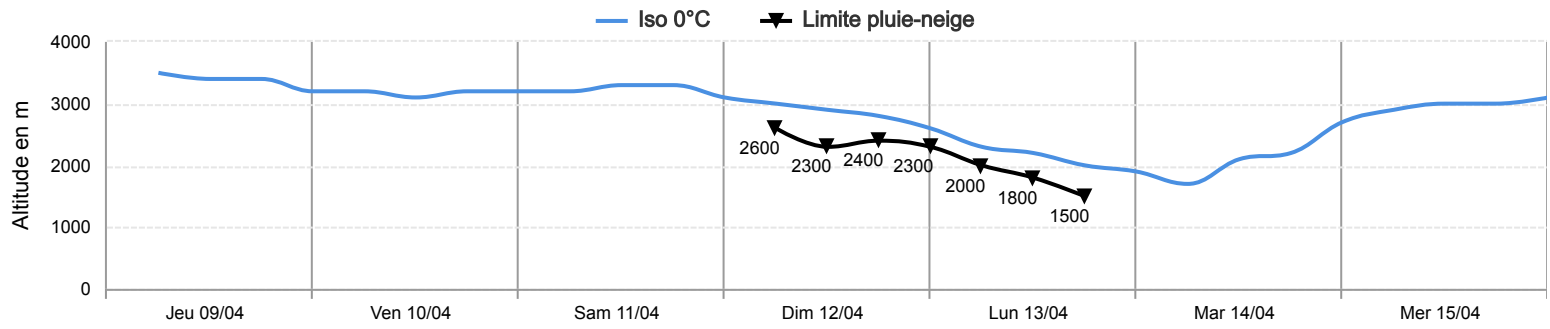

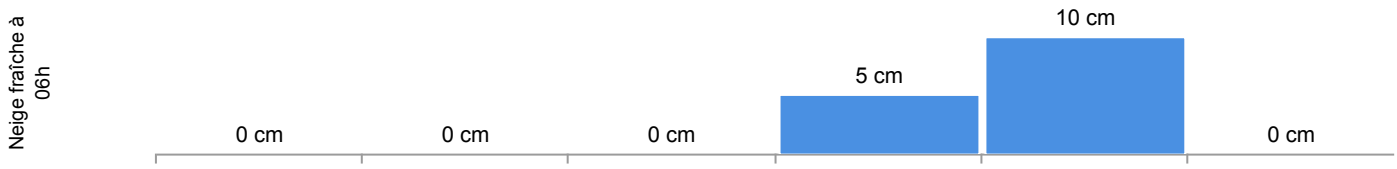

Risque d'avalanche	jeu. 09/04	ven. 10/04	sam. 11/04	dim. 12/04	lun. 13/04	mar. 14/04	mer. 15/04
	2	2	2	2	2	2	2

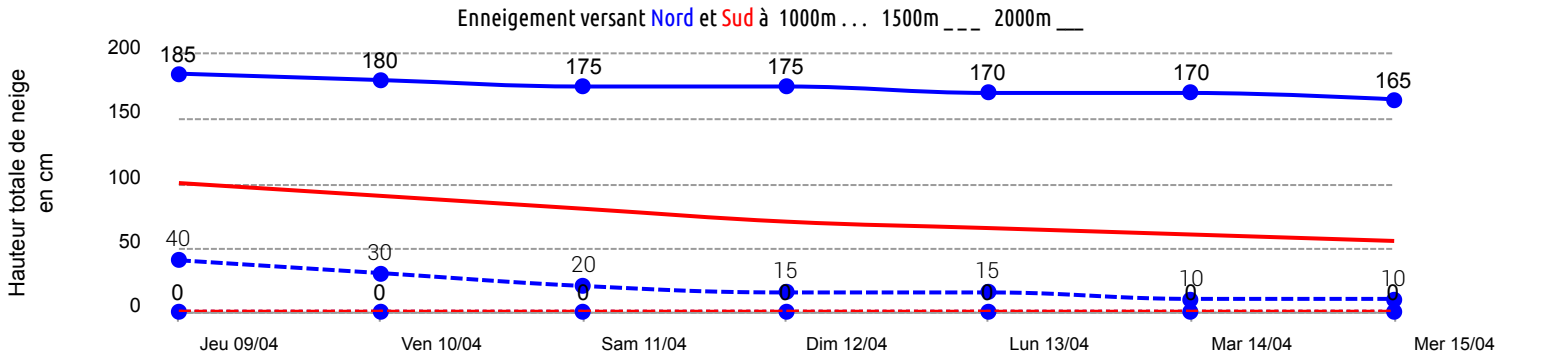

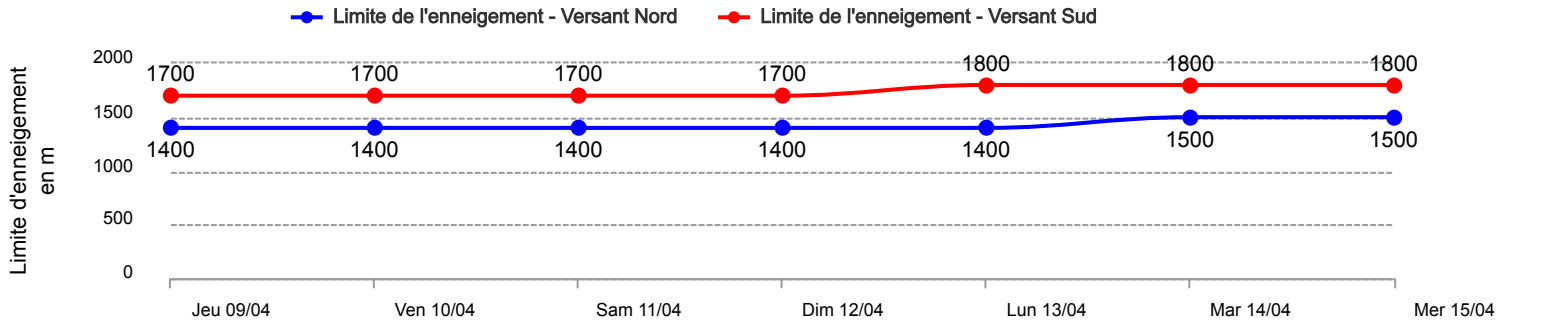

Pour consulter la vigilance en cours, veuillez vous rendre sur le site https://vigilance.meteofrance.fr/fr

Météo-France - 73 avenue de Paris, 94165 Saint-Mandé cedex - Contact : contact@meteo.fr

Rédigé par Météo-France avec la contribution des observateurs du réseau nivo-météorologiques. Partenariat : ANMSM (Maires de Stations de Montagne), DSF (Domaines Skiables de France), ADSP (Directeurs de Pistes et de la Sécurité des Stations de Sports d'Hiver) et autres acteurs de la montagne.

Bulletin neige & avalanches par téléphone au
0 892 68 10 20
Service 0,35 € / min + prix appel