GOBIERNO DE ESPAÑA
VICEPRESIDENCIA TERCERA DEL GOBIERNO
MINISTERIO PARA LA TRANSICIÓN ECOLÓGICA Y EL RETO DEMOGRÁFICO

Boletín de información nivológica y de peligro de aludes

Pirineo Navarro y Aragonés

aemet Agencia Estatal de Meteorología

jueves, 16 de abril de 2026

Pronóstico hasta las 24 horas del viernes, día 17 de abril

(Válido fuera de pistas de esquí balizadas y abiertas)

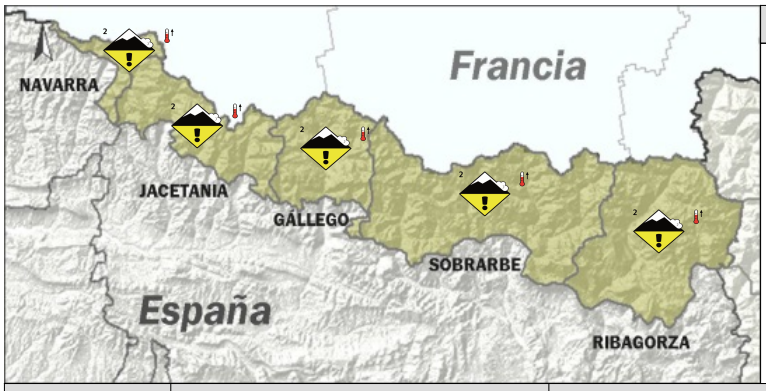

Problemas de aludes

Placas de viento

Nieve húmeda

Macizo	Peligro	Problemas de aludes, cota, orientación, tamaño	Innivación observada (m)
Navarra	2 — 2 — Limitado	Placas de viento: 2400, N O E S, 1 Nieve húmeda: N O E S, 2	2026-04-16 N S Cota más baja caras N
Jacetania	2 — 2 — Limitado	Placas de viento: 2400, N O E S, 1 Nieve húmeda: N O E S, 2	2026-04-16 N S Cota más baja caras N
Gállego	2 — 2 — Limitado	Placas de viento: 2400, N O E S, 1 Nieve húmeda: N O E S, 2	2026-04-16 N S Cota más baja caras N

AEMET. Se autoriza la reproducción de su contenido citando la fuente.

Sobrarbe	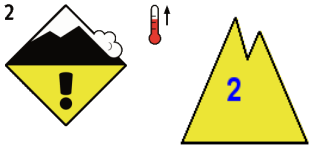 **Limitado**	**Placas de viento** 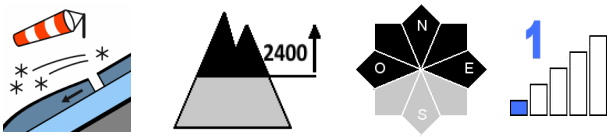 **Nieve húmeda** 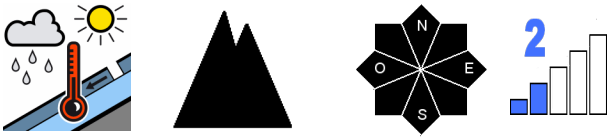	2026-04-16 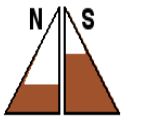 Cota más baja caras N
Ribagorza	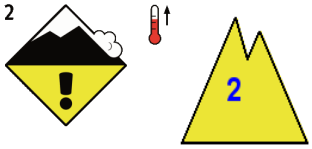 **Limitado**	**Placas de viento** **Nieve húmeda** 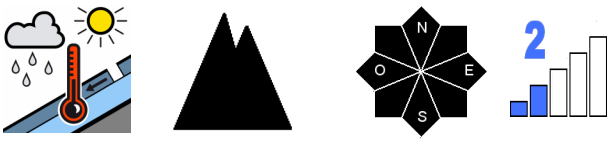	2026-04-16 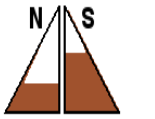 Cota más baja caras N

Estado del manto y observaciones recientes

El ambiente cálido y la abundante insolación están propiciando la humidificación y compactación del manto, que se va intensificando día a día, registrándose pérdidas en la red de observación de hasta 10 cm en las últimas 24 horas. Como consecuencia, la cubierta nivosa ha ido retrocediendo a altitudes más elevadas, siendo más o menos continua a partir de los 1700-1900 metros en umbrías y los 1900-2100 metros en solanas. Los espesores se van incrementando a medida que ascendemos, estando todavía muy por encima de lo que cabría esperar a estas alturas de la temporada. A unos 2200 metros se pueden encontrar entre 60 y 170 cm, aún más en ventisqueros, hoyas y otras zonas propensas a la acumulación.
El manto es de tipo primaveral, está muy humedecido y en proceso de fusión. El rehielo nocturno está restringido a cotas altas y es cada vez más débil y menos efectivo. Las costras superficiales que se forman durante la noche tienden a fundirse rápidamente con el calentamiento diurno. El último episodio de nevadas vino acompañado de vientos intensos de componente sur girando a norte que formaron placas de viento en todas las orientaciones de cotas altas. Aunque estas han ido estabilizándose rápidamente en las solanas, todavía pueden permanecer frágiles en cotas altas, especialmente en umbrías a resguardo del viento y cerca de crestas y collados.

Evolución del manto y peligro de aludes para el viernes, día 17

Problemas de nieve húmeda y deslizamientos basales. Problema de placas de viento en cotas altas.

Mañana volverán a ascender las temperaturas y la fuerte insolación de días anteriores continuará, con un rehielo nocturno que quedará restringido a las cumbres de mayor altitud. Así, los problemas de nieve húmeda se presentarán ya desde el comienzo del día, afectando pronto a todas las orientaciones e incrementándose durante las horas centrales. En laderas

AEMET. Se autoriza la reproducción de su contenido citando la fuente.

suficientemente inclinadas, serán probables las purgas de tamaño pequeño (peligro de caída) o mediano (capaz de enterrar a una persona), más probables y frecuentes en solanas a partir del mediodía y en zonas próximas a afloramientos rocosos, esperándose la mayor cantidad de aludes al final del día.
Además, en zonas de manto delgado sobre laderas herbosas o de roca lisa muy inclinadas, también podrán suceder deslizamientos basales de tamaño generalmente mediano, sin descartar que puedan alcanzar tamaños localmente superiores.
Por encima de unos 2400 metros, especialmente en zonas de acumulación de las umbrías y cerca de crestas y collados, todavía podrán quedar placas de viento algo frágiles. Ante una sobrecarga débil (paso de un esquiador) estas podrán colapsar y provocar aludes de tamaño pequeño o más raramente mediano.

Predicción meteorológica para el viernes, día 17

Poco nuboso, con velos de nubes altas durante el día y algunas nubes bajas y de evolución diurna por la tarde. No se esperan precipitaciones. Temperaturas en ligero o moderado ascenso. Heladas débiles en cumbres. Viento flojo de dirección variable, con intervalos de moderado de componentes norte y oeste en cotas altas.

Datos en la atmósfera libre:

Altitud de la isoterma de 0 ºC: 3400 m
Altitud de la isoterma de -10 ºC: 4900 m

Viento a 1500 m: VRB 5 km/h
Viento a 3000 m: N 10 km/h

Evolución para el sábado día 18

Nivel de peligro con pocos cambios.

(Información elaborada a partir de los datos recibidos de los refugios de Linza, Lizara, Respomuso, Panticosa, Bachimaña, Góriz, Pineta, Estós, Angel Orús, La Renclusa, Cap de Llauset y Belagua, de las estaciones de esquí de Formigal y Panticosa (lagos) y de Ordesa Pradera)

Escala europea de peligro de aludes

Débil | Limitado | Notable | Fuerte | Muy Fuerte

Problemas de aludes

Nieve reciente | Placas de viento | Capas débiles persistentes | Nieve húmeda | Deslizamientos basales | Sin problema evidente

Nota1: Se recuerda que, siempre que haya nieve, la ausencia total de peligro no existe. Hay que tener presente que en circunstancias desfavorables, con aludes de tamaño 1 (alud pequeño o colada) y tamaño 2 (alud mediano), se pueden sufrir severos daños personales.

Nota2: Los BPA se elaboran en base a información meteorológica así como al estado del manto nivoso a través de sondeos puntuales. Se advierte a los usuarios de la variabilidad de esta información al extrapolarla a zonas extensas de montaña. Por ello, AEMET no se hace responsable de su uso para la toma de decisiones que conciernen a la seguridad personal, ni de los riesgos físicos o materiales de ellas derivadas.

AEMET. Se autoriza la reproducción de su contenido citando la fuente.