Freitag 17.04.2026

Veröffentlicht am 16.04.2026 um 17:00

Vormittag

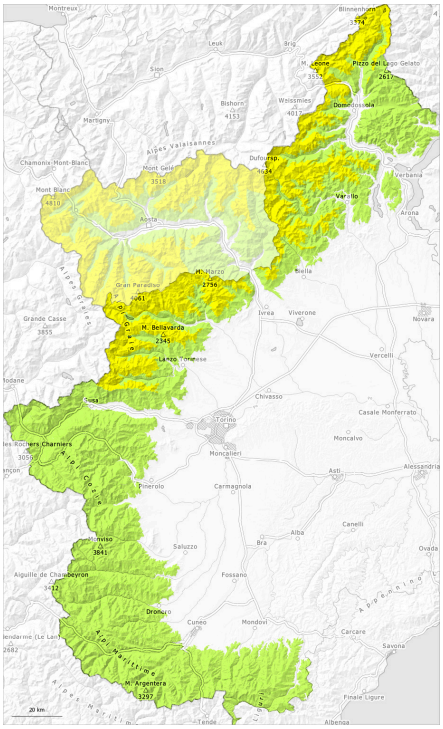

Nachmittag

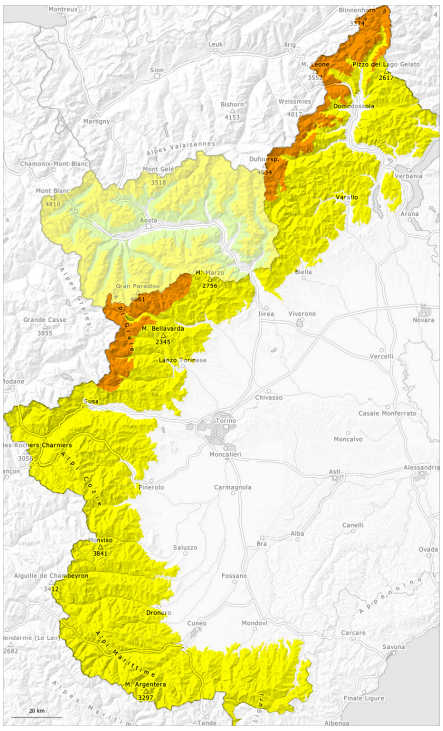

1	2	3	4	5
gering	mäßig	erheblich	groß	sehr groß

Gefahrenstufe 3 - Erheblich

AM:

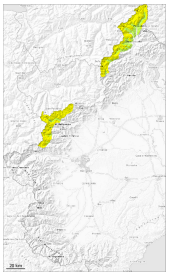

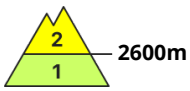

Tendenz: Lawinengefahr nimmt ab
am Samstag, den 18.04.2026

Nassschnee

PM:

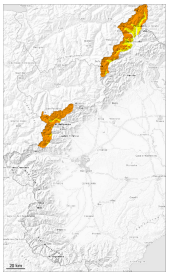

Tendenz: Lawinengefahr nimmt ab
am Samstag, den 18.04.2026

Nassschnee

Nassschnee

Die Gefahr von feuchten und nassen Lawinen steigt bereits am Vormittag an.

Die Wärme führt am Vormittag an Sonnenhängen in hohen Lagen und im Hochgebirge zu einem Festigkeitsverlust innerhalb der Schneedecke. Diese Situation führt an allen Expositionen in tiefen und mittleren Lagen verbreitet zu einer massiven Durchnässung der Schneedecke. Spontane Lawinen und Durchbrechen in den Altschnee zeigen den schwachen Schneedeckenaufbau.

V.a. an sehr steilen Hängen sind mit der tageszeitlichen Erwärmung und der Sonneneinstrahlung weiterhin mittlere und vereinzelt große Gleitschneelawinen und feuchte Rutsche möglich.
Hohe Lagen und Hochgebirge: Lawinen können vereinzelt im Altschnee ausgelöst werden und an steilen Sonnenhängen mittlere Größe erreichen. Dies teilweise schon durch einzelne Wintersportler.

Touren sollten rechtzeitig beendet werden.

Schneedecke

Gefahrenmuster gm.6: lockerer schnee und wind | gm.10: frühjahrssituation

Am Montag fielen oberhalb von rund 2200 m bis zu 60 cm Schnee. Der Neuschnee vom Montag hat sich stark gesetzt.

Unterhalb von rund 3000 m: Die Schneedecke ist feucht, mit einer Schmelzharschkruste an der Oberfläche. Die Schneeoberfläche weicht schon am Vormittag auf.

Sonne und Wärme führen im Tagesverlauf zu einer raschen Anfeuchtung der Schneedecke. Dies vor allem an steilen Sonnenhängen in hohen Lagen und im Hochgebirge und an allen Expositionen in tiefen und mittleren Lagen.
Unterhalb von rund 2400 m liegt an Südhängen nur wenig Schnee.

Gefahrenstufe 2 - Mäßig

AM:

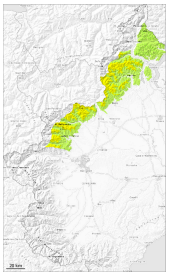

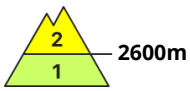

Tendenz: Lawinengefahr bleibt gleich
am Samstag, den 18.04.2026

Nassschnee

2600m

PM:

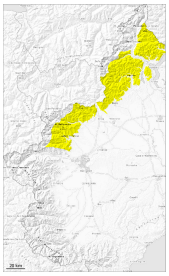

Tendenz: Lawinengefahr bleibt gleich
am Samstag, den 18.04.2026

Nassschnee

Die Gefahr von feuchten und nassen Lawinen steigt bereits am Vormittag an.

Die Wärme führt am Vormittag an Sonnenhängen in hohen Lagen und im Hochgebirge zu einem Festigkeitsverlust innerhalb der Schneedecke. Diese Situation führt an allen Expositionen in tiefen und mittleren Lagen verbreitet zu einer massiven Durchnässung der Schneedecke. Spontane Lawinen und Durchbrechen in den Altschnee zeigen den schwachen Schneedeckenaufbau.

V.a. an sehr steilen Hängen und im felsdurchsetzten Steilgelände sind mit der tageszeitlichen Erwärmung und der Sonneneinstrahlung weiterhin kleine und mittlere Gleitschneelawinen und feuchte Rutsche möglich.
Hohe Lagen und Hochgebirge: Die oberflächennahen Schneeschichten können vereinzelt von einzelnen Wintersportlern ausgelöst werden.
Touren sollten rechtzeitig beendet werden.

Schneedecke

Gefahrenmuster gm.6: lockerer schnee und wind | gm.10: frühjahrssituation

Am Montag fielen oberhalb von rund 2000 m verbreitet 40 bis 60 cm Schnee. Der Neuschnee vom Montag hat sich stark gesetzt.

Unterhalb von rund 3000 m: Die Schneedecke ist feucht, mit einer Schmelzharschkruste an der Oberfläche. Die Schneeoberfläche weicht schon am Vormittag auf.

Sonne und Wärme führen im Tagesverlauf zu einer raschen Anfeuchtung der Schneedecke. Dies vor allem an steilen Sonnenhängen in hohen Lagen und im Hochgebirge und an allen Expositionen in tiefen und

mittleren Lagen.
Unterhalb von rund 2400 m liegt an Südhängen nur wenig Schnee.

Gefahrenstufe 2 - Mäßig

AM:

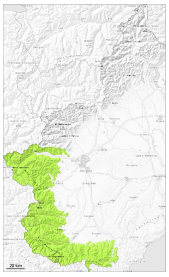

Tendenz: Lawinengefahr bleibt gleich
am Samstag, den 18.04.2026

PM:

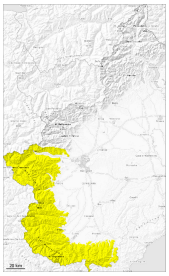

Tendenz: Lawinengefahr bleibt gleich
am Samstag, den 18.04.2026

Nassschnee

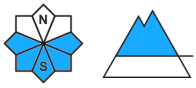

Nassschnee

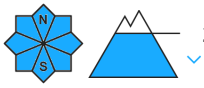

Nach klarer Nacht herrschen am Morgen verbreitet günstige Verhältnisse, dann steigt die Gefahr von nassen Lawinen an.

Die Lawinengefahr steigt bereits am Vormittag an, besonders an Ost-, Süd- und Westhängen in hohen Lagen und im Hochgebirge und an allen Expositionen unterhalb von rund 2500 m.

V.a. an steilen Sonnenhängen sind mit der tageszeitlichen Erwärmung und der Sonneneinstrahlung kleine und mittlere feuchte und nasse Lawinen möglich. Feuchte Lawinen können leicht ausgelöst werden oder spontan abgehen. Spontane Lawinen und Durchbrechen in den Altschnee sind Hinweise für den schwachen Schneedeckenaufbau.

Touren sollten früh gestartet und rechtzeitig beendet werden. Morgen: Auf der harten Schneeoberfläche besteht Absturzgefahr.

Schneedecke

Gefahrenmuster gm.6: lockerer schnee und wind | gm.10: frühjahrssituation

Seit Sonntag fielen oberhalb von rund 2100 m verbreitet 5 bis 30 cm Schnee.
Die Schneeoberfläche ist tragfähig gefroren und weicht schon am Vormittag auf. Dies vor allem an steilen Ost-, Süd- und Westhängen unterhalb von rund 2600 m sowie an Nordhängen unterhalb von rund 2400 m.

Unterhalb von rund 2200 m liegt an Südhängen kein Schnee.