Venerdì 17.04.2026

Pubblicato il 16.04.2026 alle ore 17:00

Mattina

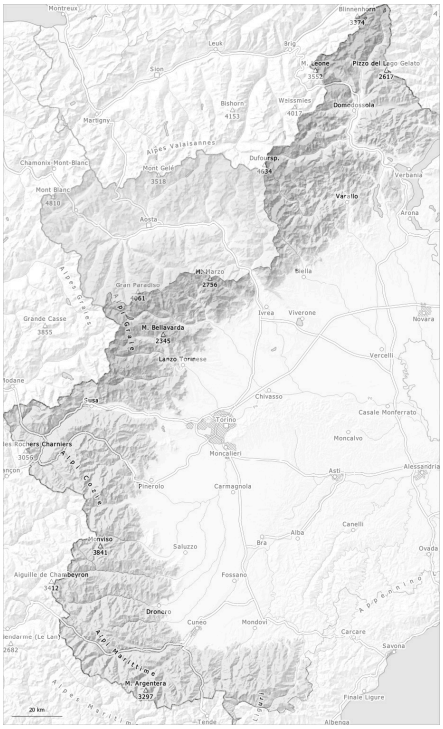

pomeriggio

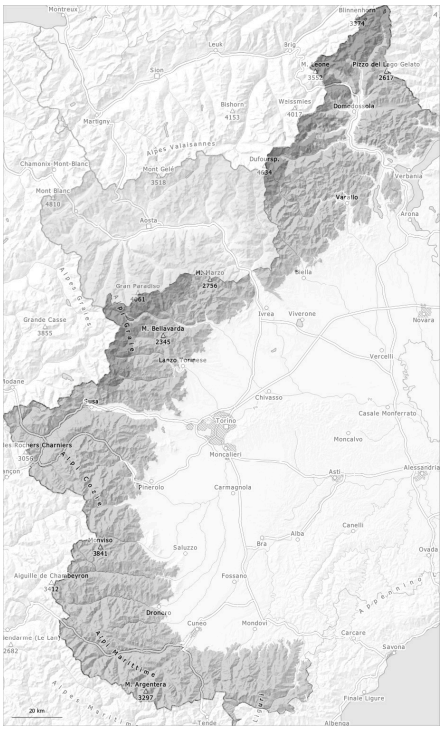

1	2	3	4	5
debole	moderato	marcato	forte	molto forte

Grado di pericolo 3 - Marcato

AM:

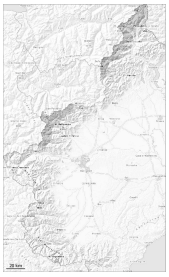

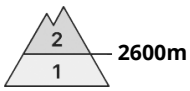

Tendenza: pericolo valanghe in diminuzione
per Sabato il 18.04.2026

Neve bagnata

PM:

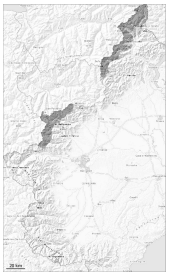

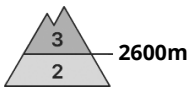

Tendenza: pericolo valanghe in diminuzione
per Sabato il 18.04.2026

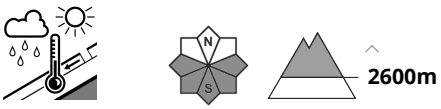

Neve bagnata

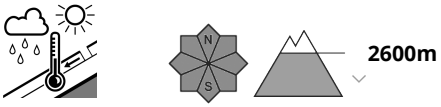

Neve bagnata

Il pericolo di valanghe umide e bagnate aumenterà già durante la mattinata.

Durante la mattinata il calore causerà sui pendii soleggiati ad alta quota e in alta montagna una destabilizzazione all'interno del manto nevoso. Ciò causerà a tutte le esposizioni alle quote di bassa e media montagna diffusamente un massiccio impregnamento del manto nevoso. I distacchi spontanei di valanghe e gli sprofondamenti nel manto di neve vecchia mostrano la debole struttura del manto nevoso.

Con il rialzo termico e l'irradiazione solare diurni, specialmente sui pendii molto ripidi sono ancora possibili valanghe per scivolamento di neve e colate umide di medie e, a livello isolato, di grandi dimensioni.
Ad alta quota e in alta montagna: Le valanghe possono a livello isolato subire un distacco, in alcuni punti già da parte di un singolo appassionato di sport invernali, nella neve vecchia umida soprattutto sui pendii soleggiati ripidi e raggiungere dimensioni medie.

Le escursioni dovrebbero terminare in tempo.

Manto nevoso

Situazione tipo st.6: neve a debole coesione e vento | st.10: situazione primaverile

Lunedì sono caduti sino a 60 cm di neve al di sopra dei 2200 m circa. La neve fresca di lunedì si è fortemente assestata.

Al di sotto dei 3000 m circa: Il manto nevoso è umido, con una crosta da rigelo in superficie. La superficie del manto nevoso si ammorbidirà già al mattino.

Il sole e il calore causeranno nel corso della giornata un rapido inumidimento del manto nevoso. Ciò soprattutto sui pendii soleggiati ripidi ad alta quota e in alta montagna e a tutte le esposizioni alle quote di bassa e media montagna.
Al di sotto dei 2400 m circa è presente solo poca neve sui pendii esposti a sud.

Grado di pericolo 2 - Moderato

AM:

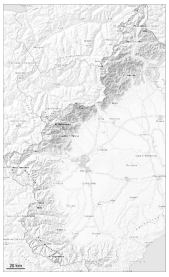

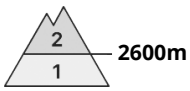

Tendenza: pericolo valanghe stabile
per Sabato il 18.04.2026

Neve bagnata

PM:

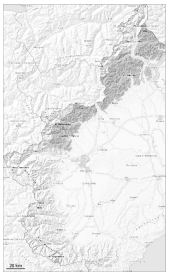

Tendenza: pericolo valanghe stabile
per Sabato il 18.04.2026

Neve bagnata

Il pericolo di valanghe umide e bagnate aumenterà già durante la mattinata.

Durante la mattinata il calore causerà sui pendii soleggiati ad alta quota e in alta montagna una destabilizzazione all'interno del manto nevoso. Ciò causerà a tutte le esposizioni alle quote di bassa e media montagna diffusamente un massiccio impregnamento del manto nevoso. I distacchi spontanei di valanghe e gli sprofondamenti nel manto di neve vecchia mostrano la debole struttura del manto nevoso.

Con il rialzo termico e l'irradiazione solare diurni, specialmente sui pendii molto ripidi e sui pendii ripidi rocciosi sono ancora possibili valanghe per scivolamento di neve e colate umide di piccole e medie dimensioni.
Ad alta quota e in alta montagna: Gli strati superficiali di neve possono distaccarsi a livello isolato in seguito al passaggio di un singolo appassionato di sport invernali.
Le escursioni dovrebbero terminare in tempo.

Manto nevoso

Situazione tipo st.6: neve a debole coesione e vento | st.10: situazione primaverile

Lunedì sono caduti diffusamente da 40 a 60 cm di neve al di sopra dei 2000 m circa. La neve fresca di lunedì si è fortemente assestata.

Al di sotto dei 3000 m circa: Il manto nevoso è umido, con una crosta da rigelo in superficie. La superficie del manto nevoso si ammorbidirà già al mattino.

Il sole e il calore causeranno nel corso della giornata un rapido inumidimento del manto nevoso. Ciò soprattutto sui pendii soleggiati ripidi ad alta quota e in alta montagna e a tutte le esposizioni alle quote di bassa e media montagna.
Al di sotto dei 2400 m circa è presente solo poca neve sui pendii esposti a sud.

Grado di pericolo 2 - Moderato

AM:

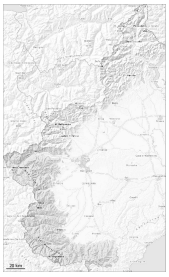

Tendenza: pericolo valanghe stabile
per Sabato il 18.04.2026

PM:

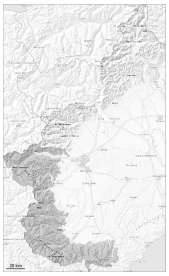

Tendenza: pericolo valanghe stabile
per Sabato il 18.04.2026

Neve bagnata

2600m

Neve bagnata

2600m

Dopo una notte serena, al mattino predominano in molti punti condizioni favorevoli, poi il pericolo di valanghe bagnate aumenterà.

Il pericolo di valanghe aumenterà già durante la mattinata, soprattutto sui pendii esposti a est, sud e ovest ad alta quota e in alta montagna e a tutte le esposizioni al di sotto dei 2500 m circa.

Con il rialzo termico e l'irradiazione solare diurni, specialmente sui pendii soleggiati ripidi sono possibili valanghe umide e bagnate di piccole e medie dimensioni. Le valanghe umide possono distaccarsi in modo provocato o spontaneo. I distacchi spontanei di valanghe e gli sprofondamenti nel manto di neve vecchia indicano la debole struttura del manto nevoso.

Le escursioni dovrebbero iniziare e terminare in tempo. Mattina: Sulla dura superficie del manto nevoso sussiste un pericolo di caduta.

Manto nevoso

Situazione tipo st.6: neve a debole coesione e vento | st.10: situazione primaverile

Da domenica sono caduti diffusamente da 5 a 30 cm di neve al di sopra dei 2100 m circa.
La superficie del manto nevoso si è rigelata ed è portante e si ammorbidirà già al mattino. Ciò soprattutto sui pendii ripidi esposti a est, sud e ovest al di sotto dei 2600 m circa, come pure sui pendii esposti a nord al di sotto dei 2400 m circa.

Al di sotto dei 2200 m circa non c'è neve sui pendii esposti a sud.