Freitag 17.04.2026

Veröffentlicht am 16.04.2026 um 17:00

Vormittag

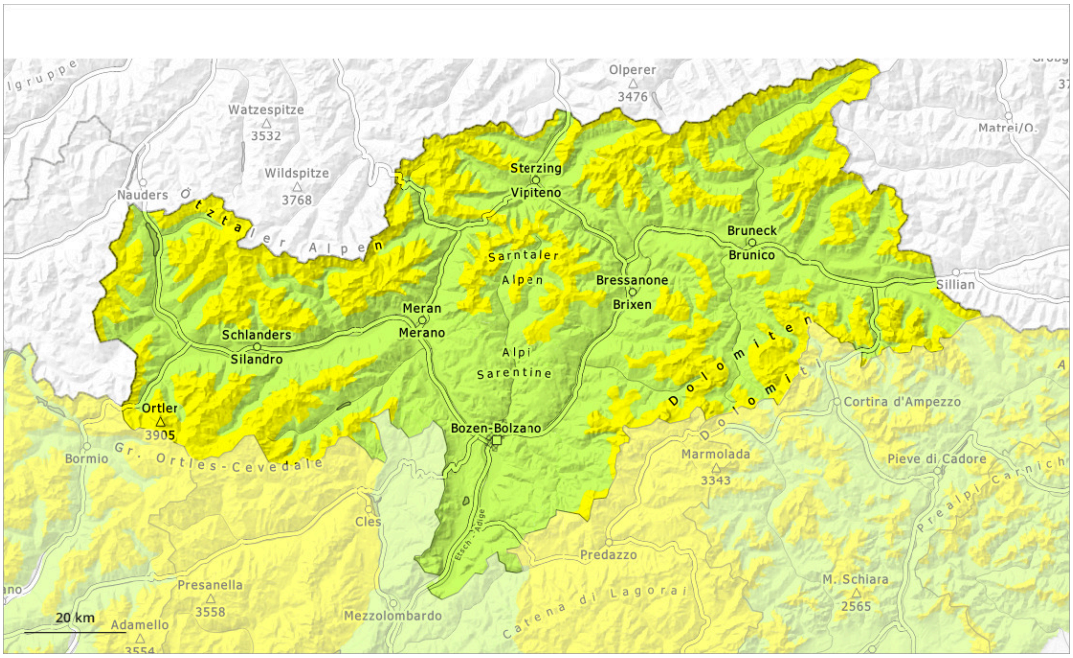

Nachmittag

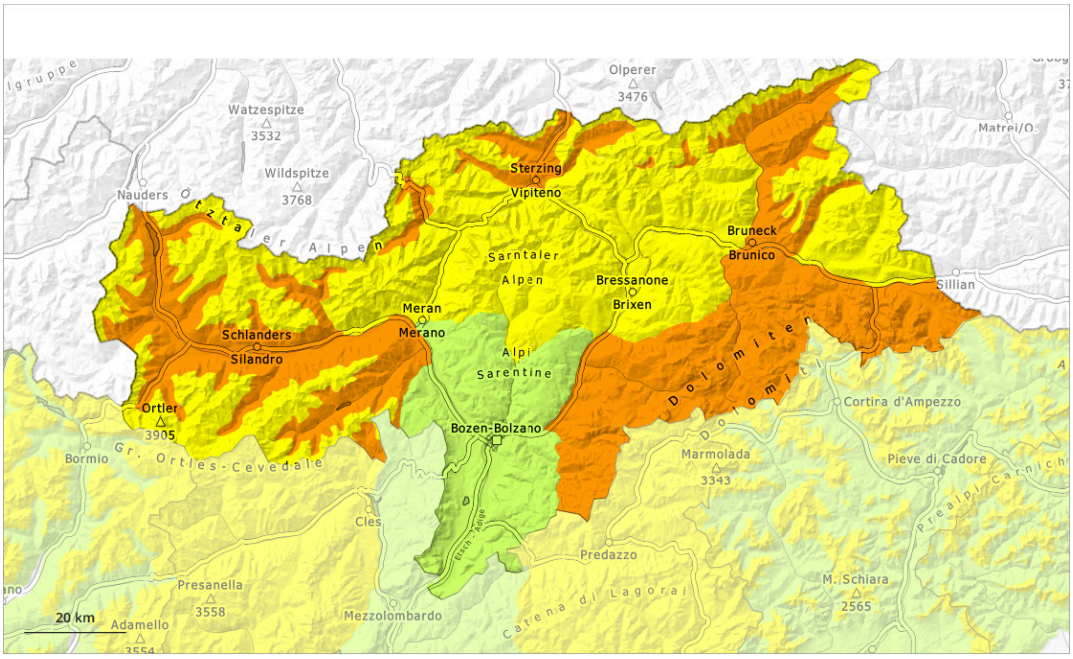

1	2	3	4	5
gering	mäßig	erheblich	groß	sehr groß

Gefahrenstufe 3 - Erheblich

AM:

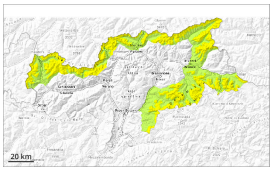

2500m

Tendenz: Lawinengefahr bleibt gleich
am Samstag, den 18.04.2026

Altschnee

2500m

PM:

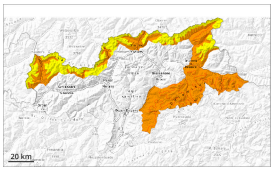

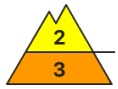

3000m

Tendenz: Lawinengefahr bleibt gleich
am Samstag, den 18.04.2026

Nassschnee

3000m

Altschnee

2500m

Anstieg der Gefahr von nassen Lawinen im Tagesverlauf.

Mit der tageszeitlichen Erwärmung und der Sonneneinstrahlung steigt die Gefahr von nassen Lawinen im Tagesverlauf deutlich an. Nasse Lawinen können stellenweise von einzelnen Wintersportlern ausgelöst werden. Dies an sehr steilen Schattenhängen unterhalb von rund 2500 m sowie an sehr steilen Sonnenhängen in der Höhe. Am Nachmittag sind spontane Lawinen möglich. Lawinen können im schwachen Altschnee anreißen und vereinzelt groß werden.

Zudem können trockene Lawinen vereinzelt schon mit geringer Belastung ausgelöst werden, besonders an sehr steilen West-, Nord- und Osthängen oberhalb von rund 2500 m. Ungünstig sind besonders Übergänge von wenig zu viel Schnee. Die Gefahrenstellen sind schwer zu erkennen.

Schneedecke

Gefahrenmuster gm.10: frühjahrssituation | gm.1: bodennahe schwachschicht

Die Schneeoberfläche gefriert tragfähig und weicht im Tagesverlauf auf. Sonne und Wärme führen unterhalb von rund 3000 m zu einer zunehmenden Durchnässung der Schneedecke.
Steile West-, Nord- und Osthänge: Im unteren Teil der Altschneedecke sind in der Höhe kantig aufgebaute Schwachschichten vorhanden.

Tendenz

Die nächtliche Abstrahlung ist gut. Die Tourenverhältnisse sind am Morgen in der Höhe mehrheitlich

günstig. Mit der tageszeitlichen Erwärmung und der Sonneneinstrahlung steigt die Gefahr von nassen Lawinen im Tagesverlauf an.

Gefahrenstufe 3 - Erheblich

AM:

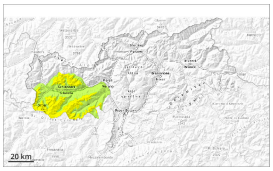

2500m

Tendenz: Lawinengefahr bleibt gleich
am Samstag, den 18.04.2026

Altschnee

2500m

PM:

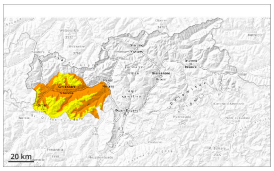

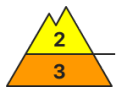

3000m

Tendenz: Lawinengefahr bleibt gleich
am Samstag, den 18.04.2026

Nassschnee

3000m

Altschnee

2500m

Anstieg der Gefahr von nassen Lawinen im Tagesverlauf.

Mit der tageszeitlichen Erwärmung und der Sonneneinstrahlung steigt die Gefahr von nassen Lawinen im Tagesverlauf deutlich an. Nasse Lawinen können stellenweise von einzelnen Wintersportlern ausgelöst werden. Dies an sehr steilen Schattenhängen unterhalb von rund 2500 m sowie an sehr steilen Sonnenhängen in der Höhe. Am Nachmittag sind spontane Lawinen möglich. Lawinen können im schwachen Altschnee anreißen und vereinzelt groß werden.

Zudem können trockene Lawinen vereinzelt schon mit geringer Belastung ausgelöst werden, besonders an sehr steilen West-, Nord- und Osthängen oberhalb von rund 2500 m. Ungünstig sind besonders Übergänge von wenig zu viel Schnee. Die Gefahrenstellen sind schwer zu erkennen.
Die nicht mehr ganz frischen Triebschneeansammlungen können vor allem an sehr steilen Schattenhängen im Hochgebirge vereinzelt von einzelnen Wintersportlern ausgelöst werden.

Schneedecke

Gefahrenmuster gm.10: frühjahrssituation | gm.1: bodennahe schwachschicht

Die Schneeoberfläche gefriert tragfähig und weicht im Tagesverlauf auf. Sonne und Wärme führen unterhalb von rund 3000 m zu einer zunehmenden Durchnässung der Schneedecke.
Steile West-, Nord- und Osthänge: Im unteren Teil der Altschneedecke sind in der Höhe kantig aufgebaute Schwachschichten vorhanden.

Tendenz

Die nächtliche Abstrahlung ist gut. Die Tourenverhältnisse sind am Morgen in der Höhe mehrheitlich günstig. Mit der tageszeitlichen Erwärmung und der Sonneneinstrahlung steigt die Gefahr von nassen Lawinen im Tagesverlauf an.

Gefahrenstufe 2 - Mäßig

AM:

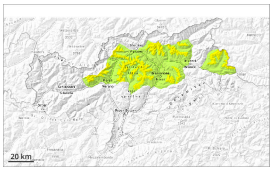

2500m

Tendenz: Lawinengefahr bleibt gleich
am Samstag, den 18.04.2026

Altschnee

2500m

PM:

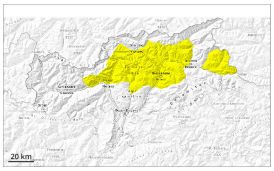

Tendenz: Lawinengefahr bleibt gleich
am Samstag, den 18.04.2026

Nassschnee

3000m

Altschnee

2500m

Anstieg der Gefahr von nassen Lawinen im Tagesverlauf.

Mit der tageszeitlichen Erwärmung und der Sonneneinstrahlung steigt die Gefahr von nassen Lawinen im Tagesverlauf an. Nasse Lawinen können stellenweise von einzelnen Wintersportlern ausgelöst werden. Dies an sehr steilen Schattenhängen unterhalb von rund 2500 m sowie an sehr steilen Sonnenhängen in der Höhe.

Einzelne Gefahrenstellen für trockene Lawinen liegen an sehr steilen Schattenhängen oberhalb von rund 2500 m. Ungünstig sind besonders Übergänge von wenig zu viel Schnee. Die Gefahrenstellen sind schwer zu erkennen.

Schneedecke

Gefahrenmuster gm.10: frühjahrssituation | gm.1: bodennahe schwachschicht

Die Schneeoberfläche ist tragfähig gefroren und weicht im Tagesverlauf auf. Sonne und Wärme führen unterhalb von rund 3000 m zu einer allmählichen Aufweichung der Schneedecke.
Steile West-, Nord- und Osthänge: Im unteren Teil der Altschneedecke sind in der Höhe kantig aufgebaute Schwachschichten vorhanden.

Tendenz

Die nächtliche Abstrahlung ist gut. Die Tourenverhältnisse sind am Morgen in der Höhe mehrheitlich günstig. Mit der tageszeitlichen Erwärmung und der Sonneneinstrahlung steigt die Gefahr von nassen

Lawinen im Tagesverlauf an.

Gefahrenstufe 1 - Gering

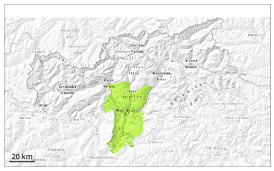

1

Tendenz: Lawinengefahr bleibt gleich
am Samstag, den 18.04.2026

Nassschnee

2000m

Nassschnee beachten.

Es sind nur noch vereinzelt nasse Lawinen möglich. Vorsicht an extrem steilen Schattenhängen. Lawinen sind sehr vereinzelt mittelgroß.

Schneedecke

Gefahrenmuster gm.10: frühjahrssituation | gm.1: bodennahe schwachschicht

Die Schneeoberfläche gefriert tragfähig und weicht im Tagesverlauf auf.

Tendenz

Geringe Lawinengefahr. Nassschnee beachten.