ICGC Institut Cartogràfic i Geològic de Catalunya

Servei Meteorològic de Catalunya meteo.cat

Boletín de peligro de aludes para el Pirineo de Catalunya
Del 16/04/2026 al 17/04/2026

(Válido fuera pistas de esquí y zonas no controladas)

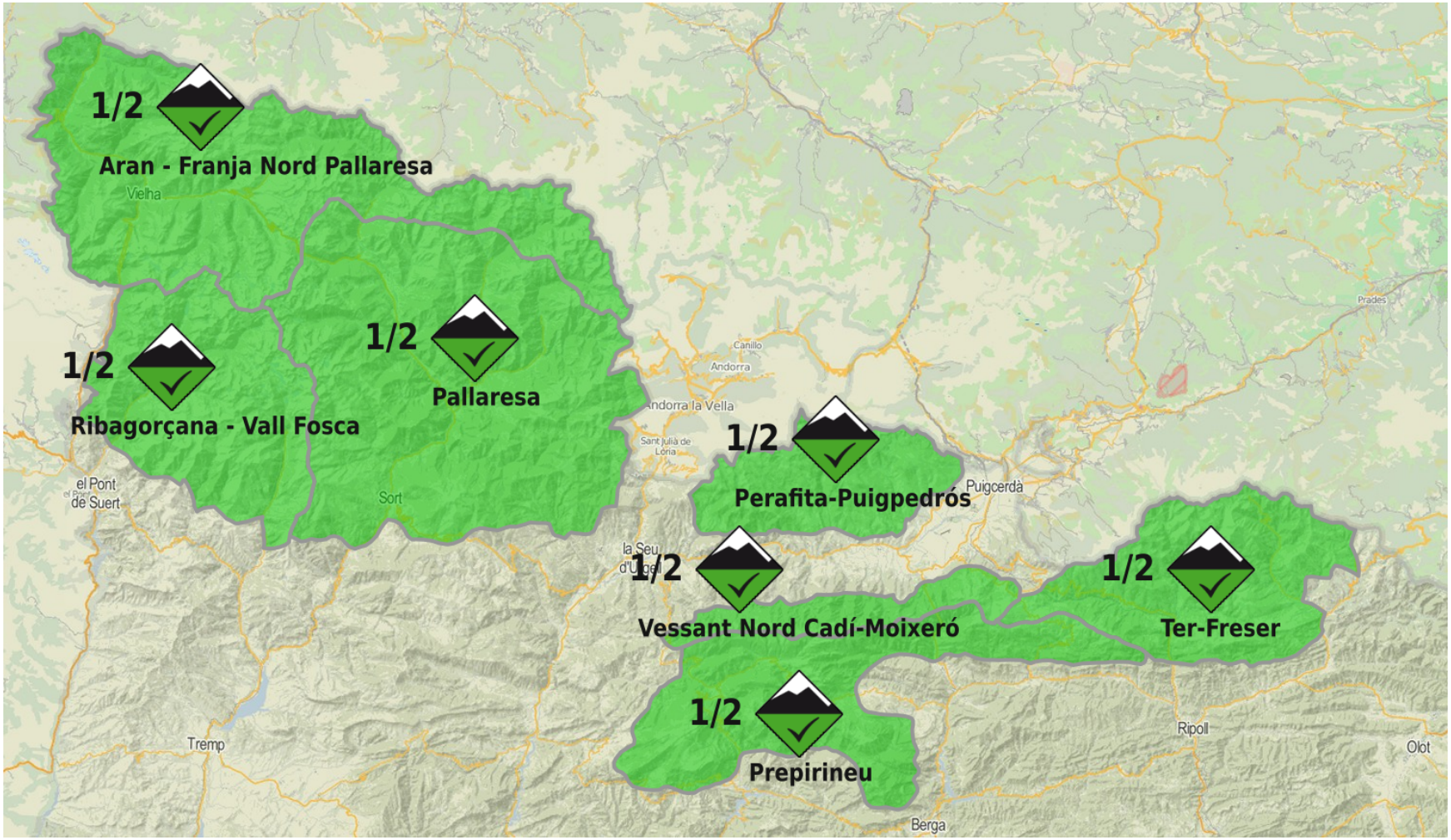

5 MUY FUERTE	4 FUERTE	3 NOTABLE	2 LIMITADO	1 DÉBIL

ICGC Institut Cartogràfic i Geològic de Catalunya

Servei Meteorològic de Catalunya

Boletín de peligro de aludes Aran - Franja Nord Pallaresa Del 16/04/2026 al 17/04/2026

(Válido fuera pistas de esquí y zonas no controladas)

DÉBIL (1). LIMITADO (2) a partir de media mañana.

Situación primaria

Nieve húmeda

Distribución

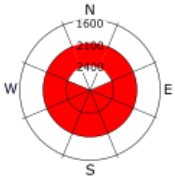

Tamaño

Origen

Tendencia

Situación secundaria

Nieve venteada

Distribución

Tamaño

Origen

Tendencia

Estado del manto nivoso

El manto nivoso se transforma fácilmente a nieve húmeda por la insolación y el ascenso térmico. Pueden crecer nubarrones de tarde que también humedecerán el manto. Son probables las caídas naturales de aludes de fusión, sobre todo junto a puntos oscuros como rocas y árboles a partir de media mañana. Estos aludes son más probables en las solanas por encima de los 2.200 m y hasta las cimas, pero también en umbrías de cotas medias que ya les dé el Sol. Serán por lo general de tamaño 1 (pequeño, con capacidad de arrastrarnos), localmente de tamaño 2 (mediano, con capacidad de cubrir una persona); puede haber también alguna de deslizamiento basal de tamaño 2 (mediano) o más. En umbrías muy altas puede quedar alguna pequeña placa de viento que se podría desprender al pasar por encima en forma de alud de placa de tamaño 1 (pequeño). A primera hora de la mañana encontraremos un manto rehelado. Habrá que tener cuidado con los resbalones.

Distribución del manto nivoso

Hay nieve en el suelo con continuidad por encima de 1.800-1.900 m en umbrías y de 2.000 m en solanas. Los espesores a unos 2.200 m rondan los 140-220 cm. Los valores están por encima de los normales por la época.

Tendencia para las próximas 48-72h

Condiciones primaverales con alta probabilidad de chubascos de tarde sábado y domingo en forma de agua hasta cotas altas, que mantendrán el manto húmedo. Evolución del peligro: EN LIGERO AUMENTO.

El próximo boletín será emitido el día 2026-04-17

5 MUY FUERTE	4 FUERTE	3 NOTABLE	2 LIMITADO	1 DÉBIL

EAWS EUROPEAN AVALANCHE WARNING SERVICES

ICGC Institut Cartogràfic i Geològic de Catalunya

Servei Meteorològic de Catalunya

Boletín de peligro de aludes Ribagorçana - Vall Fosca Del 16/04/2026 al 17/04/2026

(Válido fuera pistas de esquí y zonas no controladas)

DÉBIL (1). LIMITADO (2) a partir de media mañana.

Situación primaria

Nieve húmeda

Distribución

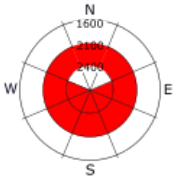

Tamaño

Origen

Tendencia

Estado del manto nivoso

El manto nivoso se transforma fácilmente a nieve húmeda por la insolación y el ascenso térmico. Pueden crecer nubarrones de tarde que también humedecerán el manto. Son probables las caídas naturales de aludes de fusión, sobre todo junto a puntos oscuros como rocas y árboles a partir de media mañana. Estos aludes son más probables en las solanas por encima de los 2.200 m y hasta las cimas, pero también en umbrías de cotas medias que ya les dé el Sol. Serán por lo general de tamaño 1 (pequeño, con capacidad de arrastrarnos); puntualmente puede haber alguna que tenga capacidad de enterrarnos (tamaño 2, mediano). No se descarta que en el límite norte, en umbrías muy altas, quede alguna pequeña placa de viento que pueda desprenderse al pasar por encima en forma de alud de placa de tamaño 1 (pequeño). A primera hora de la mañana encontraremos un manto rehelado. Habrá que tener cuidado con los resbalones.

Distribución del manto nivoso

Hay nieve por encima de 1.800-2.000 m pero esquiable en N por encima de 2.100 m-2.300 m en S. Se alcanzan los 80-100 cm a unos 2.200 m, con frecuentes deflaciones y acumulaciones por encima del nivel del bosque. Estos valores están ligeramente por debajo de los normales para la época.

Tendencia para las próximas 48-72h

Condiciones primaverales con alta probabilidad de chubascos de tarde sábado y domingo en forma de agua hasta cotas altas, que mantendrán el manto húmedo. Evolución del peligro: EN LIGERO AUMENTO.

El próximo boletín será emitido el día 2026-04-17

5 MUY FUERTE	4 FUERTE	3 NOTABLE	2 LIMITADO	1 DÉBIL

EAWS EUROPEAN AVALANCHE WARNING SERVICES

ICGC Institut Cartogràfic i Geològic de Catalunya

Servei Meteorològic de Catalunya

Boletín de peligro de aludes Pallaresa
Del 16/04/2026 al 17/04/2026

(Válido fuera pistas de esquí y zonas no controladas)

DÉBIL (1). LIMITADO (2) a partir de media mañana.

Situación primaria

Nieve húmeda

Distribución

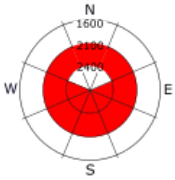

Tamaño

Origen

Tendencia

Estado del manto nivoso

El manto nivoso se transforma fácilmente a nieve húmeda por la insolación y el ascenso térmico. Pueden crecer nubarrones de tarde que también humedecerán el manto. Son probables las caídas naturales de aludes de fusión, sobre todo junto a puntos oscuros como rocas y árboles a partir de media mañana. Estos aludes son más probables en las solanas por encima de los 2.200 m y hasta las cimas, pero también en umbrías de cotas medias que ya les dé el Sol. Serán por lo general de tamaño 1 (pequeño, con capacidad de arrastrarnos); puntualmente puede haber alguna que tenga capacidad de enterrarnos (tamaño 2, mediano). No se descarta que en el límite norte, en umbrías muy altas, quede alguna pequeña placa de viento que pueda desprenderse al pasar por encima en forma de alud de placa de tamaño 1 (pequeño). A primera hora de la mañana encontraremos un manto rehelado. Habrá que tener cuidado con los resbalones.

Distribución del manto nivoso

Hay nieve por encima de 1.800-2.000 m en N por encima de 2.100-2.300 m en S. Se alcanzan los 80-100 cm a unos 2.200 m, con frecuentes deflaciones y acumulaciones por encima del nivel del bosque.

Tendencia para las próximas 48-72h

Condiciones primaverales con alta probabilidad de chubascos de tarde sábado y domingo en forma de agua hasta cotas altas, que mantendrán el manto húmedo. Evolución del peligro: EN LIGERO AUMENTO.

El próximo boletín será emitido el día 2026-04-17

5 MUY FUERTE	4 FUERTE	3 NOTABLE	2 LIMITADO	1 DÉBIL

EAWS EUROPEAN AVALANCHE WARNING SERVICES

ICGC Institut Cartogràfic i Geològic de Catalunya

Servei Meteorològic de Catalunya

Boletín de peligro de aludes Perafita-Puigpedrós Del 16/04/2026 al 17/04/2026

(Válido fuera pistas de esquí y zonas no controladas)

DÉBIL (1). LIMITADO (2) a partir de media mañana.

Situación primaria

Nieve húmeda

Distribución

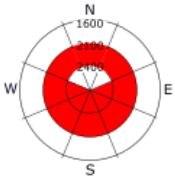

Tamaño

Origen

Tendencia

Estado del manto nivoso

El manto nivoso se transforma fácilmente a nieve húmeda por la insolación y el ascenso térmico. Pueden crecer nubarrones de tarde que también humedecerán el manto. Son probables las caídas naturales de aludes de fusión, sobre todo junto a puntos oscuros como rocas y árboles a partir de media mañana. Estos aludes son más probables en las solanas por encima de los 2.200 m y hasta las cimas, pero también en umbrías de cotas medias que ya les dé el Sol. Serán por lo general de tamaño 1 (pequeño, con capacidad de arrastrarnos); puntualmente puede haber alguna que tenga capacidad de enterrarnos (tamaño 2, mediano). No se descarta que en el extremo norte, en umbrías muy altas, quede alguna pequeña placa de viento que pueda desprenderse al pasar por encima en forma de alud de placa de tamaño 1 (pequeño). A primera hora de la mañana encontraremos un manto rehelado. Habrá que tener cuidado con los resbalones.

Distribución del manto nivoso

Hay nieve por encima de 1.900-2.000 m en orientaciones N y de 2.200 m en S. Se alcanzan los 40-80 cm de espesor a unos 2.400 m, con frecuentes deflaciones y acumulaciones por encima del nivel del bosque. Estos valores están algo por debajo de los normales por la época.

Tendencia para las próximas 48-72h

Condiciones primaverales con alta probabilidad de chubascos de tarde sábado y domingo en forma de agua hasta cotas altas, que mantendrán el manto húmedo. Evolución del peligro: EN LIGERO AUMENTO.

El próximo boletín será emitido el día 2026-04-17

5 MUY FUERTE	4 FUERTE	3 NOTABLE	2 LIMITADO	1 DÉBIL

EAWS EUROPEAN AVALANCHE WARNING SERVICES

ICGC Institut Cartogràfic i Geològic de Catalunya

Servei Meteorològic de Catalunya

Boletín de peligro de aludes
Vessant Nord Cadí-Moixeró
Del 16/04/2026 al 17/04/2026

(Válido fuera pistas de esquí y zonas no controladas)

DÉBIL (1). LIMITADO (2) a partir de media mañana.

Situación primaria

Nieve húmeda

Distribución

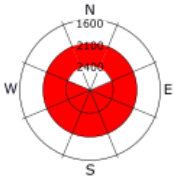

Tamaño

Origen

Tendencia

Estado del manto nivoso

El manto nivoso se transforma fácilmente a nieve húmeda por la insolación y el ascenso térmico. Pueden crecer nubarrones de tarde que también humedecerán el manto. Son probables las caídas naturales de aludes de fusión, sobre todo junto a puntos oscuros como rocas y árboles a partir de media mañana. Estos aludes son más probables en las solanas por encima de los 2.200 m y hasta las cimas, pero también en umbrías de cotas medias que ya les dé el Sol. Serán por lo general de tamaño 1 (pequeño, con capacidad de arrastrarnos); puntualmente puede haber alguna que tenga capacidad de enterrarnos (tamaño 2, mediano). A primera hora de la mañana encontraremos un manto rehelado. Habrá que tener cuidado con los resbalones.

Distribución del manto nivoso

Hay nieve por encima de 1.900 m en N y de 2.100 m en S. Se alcanzan los 130-150 cm a unos 2.200 m, con frecuentes deflaciones y acumulaciones por encima del nivel del bosque. Estos valores están por encima de los normales para la época.

Tendencia para las próximas 48-72h

Condiciones primaverales con alta probabilidad de chubascos de tarde sábado y domingo en forma de agua hasta cotas altas, que mantendrán el manto húmedo. Evolución del peligro: EN LIGERO AUMENTO.

El próximo boletín será emitido el día 2026-04-17

5 MUY FUERTE	4 FUERTE	3 NOTABLE	2 LIMITADO	1 DÉBIL

EAWS EUROPEAN AVALANCHE WARNING SERVICES

ICGC Institut Cartogràfic i Geològic de Catalunya

Servei Meteorològic de Catalunya

Boletín de peligro de aludes Prepirineu
Del 16/04/2026 al 17/04/2026

(Válido fuera pistas de esquí y zonas no controladas)

DÉBIL (1). LIMITADO (2) a partir de media mañana.

Situación primaria

Nieve húmeda

Distribución

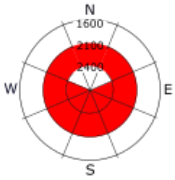

Tamaño

Origen

Tendencia

Estado del manto nivoso

El manto nivoso se transforma fácilmente a nieve húmeda por la insolación y el ascenso térmico. Pueden crecer nubarrones de tarde que también humedecerán el manto. Son probables las caídas naturales de aludes de fusión, sobre todo junto a puntos oscuros como rocas y árboles a partir de media mañana. Estos aludes son más probables en las solanas por encima de los 2.200 m y hasta las cimas, pero también en umbrías de cotas medias que ya les dé el Sol. Serán por lo general de tamaño 1 (pequeño, con capacidad de arrastrarnos); puntualmente puede haber alguna que tenga capacidad de enterrarnos (tamaño 2, mediano). A primera hora de la mañana encontraremos un manto rehelado. Habrá que tener cuidado con los resbalones.

Distribución del manto nivoso

Hay nieve por encima de 1.900 m en N y de 2.100-2.200 m en S. Se alcanzan los 60-80 cm a unos 2.200 m, con frecuentes deflaciones y acumulaciones por encima del nivel del bosque.

Tendencia para las próximas 48-72h

Condiciones primaverales con alta probabilidad de chubascos de tarde sábado y domingo en forma de agua hasta cotas altas, que mantendrán el manto húmedo. Evolución del peligro: EN LIGERO AUMENTO.

El próximo boletín será emitido el día 2026-04-17

5 MUY FUERTE	4 FUERTE	3 NOTABLE	2 LIMITADO	1 DÉBIL

EAWS EUROPEAN AVALANCHE WARNING SERVICES

ICGC Institut Cartogràfic i Geològic de Catalunya

Servei Meteorològic de Catalunya

Boletín de peligro de aludes Ter-Freser
Del 16/04/2026 al 17/04/2026

(Válido fuera pistas de esquí y zonas no controladas)

DÉBIL (1). LIMITADO (2) a partir de media mañana.

Situación primaria

Nieve húmeda

Distribución

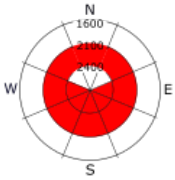

Tamaño

Origen

Tendencia

Estado del manto nivoso

El manto nivoso se transforma fácilmente a nieve húmeda por la insolación y el ascenso térmico. Pueden crecer nubarrones de tarde que también humedecerán el manto. Son probables las caídas naturales de aludes de fusión, sobre todo junto a puntos oscuros como rocas y árboles a partir de media mañana. Estos aludes son más probables en las solanas por encima de los 2.200 m y hasta las cimas, pero también en umbrías de cotas medias que ya les dé el Sol. Serán por lo general de tamaño 1 (pequeña, con capacidad de arrastrarnos); puntualmente puede haber alguna que tenga capacidad de enterrarnos (tamaño 2, mediano). No se descarta que en el extremo norte, en umbrías muy altas, quede alguna pequeña placa de viento que pueda desprenderse al pasar por encima en forma de alud de placa de tamaño 1 (pequeño). A primera hora de la mañana encontraremos un manto rehelado. Habrá que tener cuidado con los resbalones.

Distribución del manto nivoso

Hay nieve por encima de 1.900 m en N y de 2.100-2.200 m en S. Los espesores rondan los 50-80 cm a unos 2.200 m, y más de 130-190 cm por encima de 2.400 m, con frecuentes deflaciones y acumulaciones por encima. Estos valores están por encima de la media.

Tendencia para las próximas 48-72h

Condiciones primaverales con alta probabilidad de chubascos de tarde sábado y domingo en forma de agua hasta cotas altas, que mantendrán el manto húmedo. Evolución del peligro: EN LIGERO AUMENTO.

El próximo boletín será emitido el día 2026-04-17

5 MUY FUERTE	4 FUERTE	3 NOTABLE	2 LIMITADO	1 DÉBIL

EAWS EUROPEAN AVALANCHE WARNING SERVICES