BUTLLETÍ DEL PERILL D'ALLAUS DEL PRINCIPAT D'ANDORRA

Préparé le 16/04/2026 16:00
Prochaine mise à jour le 17/04/2026 à 16h

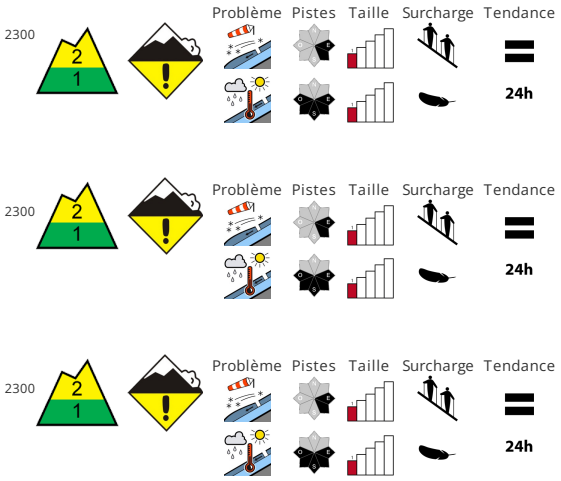

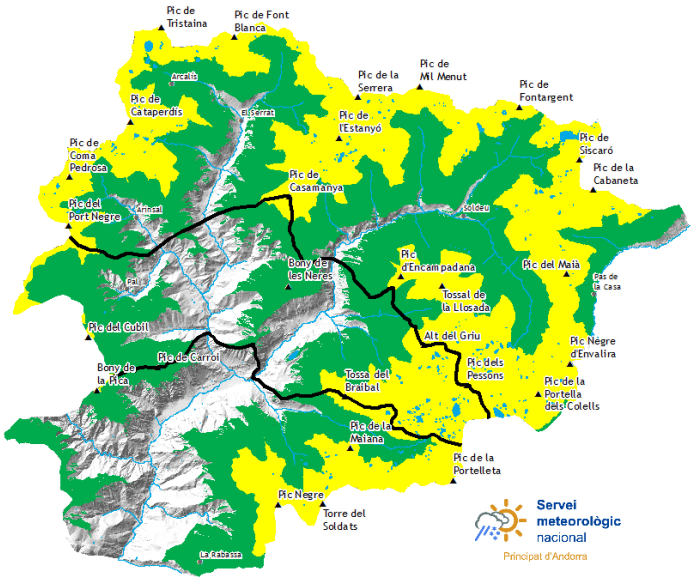

STABILITÉ DU MANTEAU NEIGEUX

Les accumulations de neige soufflée plutôt petites peuvent être déclenchées de manière isolée, et généralement uniquement avec une surcharge importante au sur les pentes très raides exposées à l'est et au sud-est au-dessus d'environ 2300 m , surtout à leur périphérie. Des avalanches et coulées humides sont ils sont à attendre avec le réchauffement diurne et le rayonnement solaire. Explication: "celles-ci" ne peut signifier que "celles-ci avalanches" peuvent se déclencher spontanément et atteindre une taille moyenne de manière isolée.. En outre, des avalanches de glissement isolées sont possibles.. Les endroits dangereux sont facilement identifiables..

QUALITÈ DE LA NEIGE

Le rayonnement nocturne est bon.. Sur la croûte glacée il existe également dans des terrains moyennement raides un risque de chute.. On trouve suivant l'influence du vent des hauteurs de neiges très différentes. Le rayonnement solaire en cours de journée entraîne sur les pentes au soleil une humidification croissante du manteau neigeux. Les zones présentant des fissures de glissement doivent être évitées..

EPAISSEUR DE NEIGE HORS PISTE

Zone nord		Epaisseur de neige			Zone centre		Epaisseur de neige			Zone sud		Epaisseur de neige		
Nival manteau		1500m	2000m	2500m	**Nival manteau**		1500m	2000m	2500m	**Nival manteau**		1500m	2000m	2500m
N	1600 m	0 cm	150 cm	250 cm	N	1600 m	0 cm	120 cm	160 cm	N	1600 m	0 cm	120 cm	160 cm
S	1800 m	0 cm	100 cm	180 cm	S	1800 m	0 cm	60 cm	120 cm	S	1800 m	0 cm	60 cm	120 cm

Govern d'Andorra

Aquest butlletí ha estat elaborat seguint les normes i recomanacions de l'**European Avalanche Warning Services**, del qual el **Servei meteorològic Nacional** n'és membre

BUTLLETÍ DEL PERILL D'ALLAUS DEL PRINCIPAT D'ANDORRA

Servei meteorològic nacional
Principat d'Andorra

Des informations détaillées par espace naturel protégé

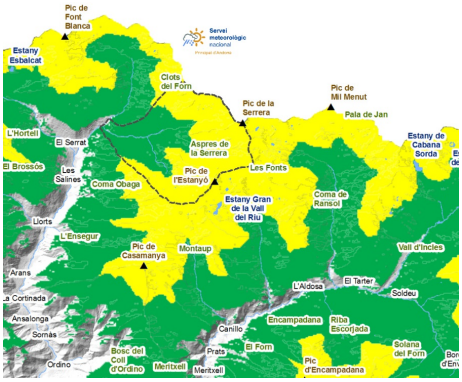

SORTENY

Le soleil humidifie progressivement la neige sur le versant sud, mais il fait encore froid au nord. À basse altitude, le vent a exposé la vieille neige tachée par la boue de la pluie du dimanche matin et elle a gelé. Les ascensions sont techniques à moyenne altitude à cause de la glace. À haute altitude, il est recommandé d'éviter les accumulations de neige venteuses et de rouler sur la neige plus dure et plus brune. , , , , , , ,

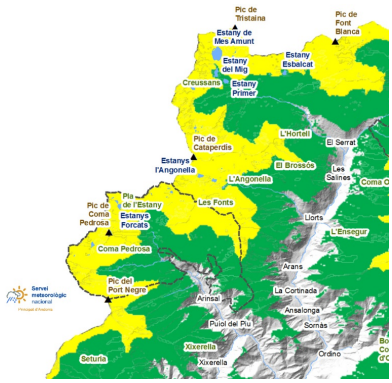

COMAPEDROSA

La neige sera humide sur les versants sud et aux altitudes moyennes, mais le matin nous la trouverons très dure. Des averses de neige mouillée continueront de tomber sur les pentes les plus raides. Au petit matin, avec la neige encore dure, il sera plus difficile et technique de parcourir les moyennes altitudes à vélo que les hautes altitudes, où la neige est plus récente. , , , , ,

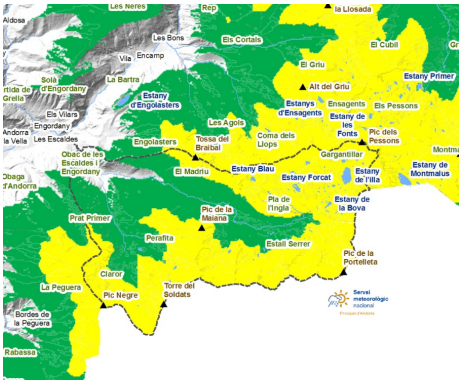

MADRIU-PERAFITA-CLAROR

Le soleil va stabiliser le manteau avec son compactage, mais en journée on s'attend à des purges sur les versants sud. Il sera plus sécuritaire de rouler sur la neige dure et brune pour éviter les plaques de vent. , , ,

Govern d'Andorra

EAWS
EUROPEAN AVALANCHE WARNING SERVICES

Aquest butlletí ha estat elaborat seguint les normes i recomanacions de l'**European Avalanche Warning Services**, del qual el **Servei meteorològic Nacional** n'és membre

BUTLLETÍ DEL PERILL D'ALLAUS DEL PRINCIPAT D'ANDORRA

Servei meteorològic nacional
Principat d'Andorra

Couche de neige fraiche des derniers jours (De 24 h mesurée à 06:00 h UTC)

	12/04/2026	13/04/2026	14/04/2026	15/04/2026
FEDA (Central)	0 cm	0 cm	0 cm	0 cm
Engolasters - FEDA	0 cm	0 cm	0 cm	0 cm
Bony de les Neres	4 cm	0 cm	0 cm	0 cm
Sorteny	0 cm	0 cm	0 cm	0 cm
Les Fonts d'Arinsal	11 cm	0 cm	0 cm	0 cm
Aixàs	0 cm	0 cm	0 cm	0 cm
Perafita	10 cm	0 cm	0 cm	0 cm
Tossa Espiolets	8 cm	1 cm	0 cm	0 cm
Grau Roig - FEDA	3 cm	2 cm	0 cm	0 cm
Fontverd	4 cm	0 cm	0 cm	0 cm
Coll Ordino	2 cm	0 cm	0 cm	0 cm
Ransol - FEDA	0 cm	0 cm	0 cm	0 cm
Setúria	5 cm	0 cm	0 cm	0 cm
Caborreu	0 cm	0 cm	0 cm	0 cm
La Solana	10 cm	4 cm	0 cm	0 cm
Coll Pa	17 cm	0 cm	0 cm	0 cm
Envalira Antenes	0 cm	1 cm	0 cm	0 cm
Vall del Riu FEDA	0 cm	0 cm	1 cm	0 cm