MINISTERO DELLA DIFESA

meteomont
Servizio Nazionale di previsione neve e valanghe

EAWS EUROPEAN AVALANCHE WARNING SERVICES

CARABINIERI

ALPI RETICHE

Bollettino Valanghe N. 408/2026 del 16/04/2026 ore 14.00
Validità 48 ore prossima emissione 17/04/2026

A cura del Servizio METEOMONT dell'ARMA dei CARABINIERI
In collaborazione con Servizio Meteorologico dell'Aeronautica militare

SITUAZIONE alle 14:00 del 16/04/2026

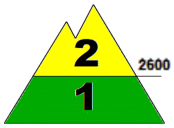

SITUAZIONE TIPO: nessuna situazione tipo evidente.



SITUAZIONE TIPO: situazione primaverile.

Quota neve (mslm)	Nord	Sud
	1900 - 2000	2500 - 2600

Altezza Neve (cm)	Neve al suolo	Neve Fresca	Quota (mslm)
	83	10	2212
	18	0	1860

VALANGHE OSSERVATE: Alcune valanghe di medie dimensioni, Valanghe di neve a debole coesione di superficie.

PREVISIONI 17/04/2026

GRADO DI PERICOLO: MODERATO 2

SITUAZIONE TIPO: nessuna situazione tipo evidente.

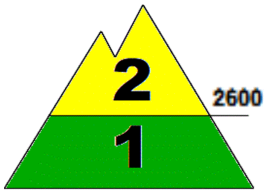

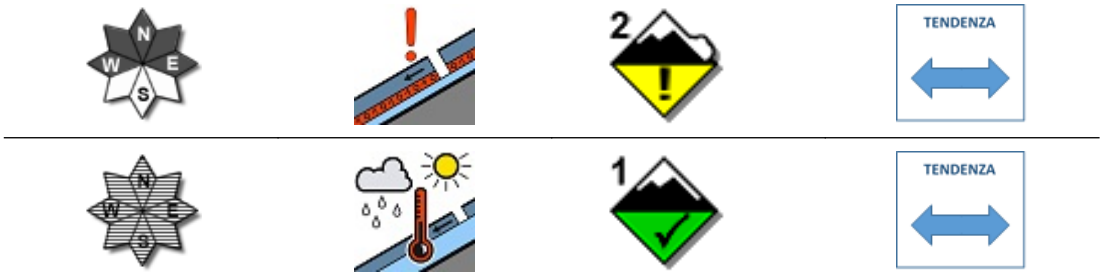

SITUAZIONE TIPO: situazione primaverile.

MANTO NEVOSO: La stabilità del manto nevoso è discreta su alcuni punti (aree) per versanti da ovest a est al di sopra di 2600 mslm, possibili valanghe di dimensioni medie.
La stabilità del manto nevoso è discreta su pochi punti (aree) per isolati pendii al di sotto di 2600 mslm, possibili valanghe di dimensioni medie.

AVVERTENZE

Il rialzo termico diurno richiede un'attenta valutazione temporale dell'escursione che eviti l'attraversamento di pendii ripidi nelle ore più calde della giornata.

SCALA EUROPEA DEL GRADO DI PERICOLO VALANGHE

LEGENDA PROBLEMA

Bollettino realizzato su scala sinottica-regionale (standard EAWS). La sua valutazione non può escludere in alcun modo la necessità di una seria e capace valutazione locale del pericolo (singolo pendio) che può essere anche sensibilmente diverso. Le previsioni meteorologiche sono relative all'orario UTC (per l'Italia +1 in inverno e +2 in estate).

MINISTERO DELLA DIFESA

meteomont
Servizio Nazionale di previsione neve e valanghe

EAWS EUROPEAN AVALANCHE WARNING SERVICES

CARABINIERI

ALPI RETICHE

NEVE FRESCA | LASTRONI DA VENTO | STRATI DEBOLI PERSISTENTI | NEVE BAGNATA | SLITTAMENTO | CORNICI | NESSUN PROBLEMA VALANGHIVO EVIDENTE | NO_INFO

PREVISIONE METEO

Quota		17/04/2026 h6:00	17/04/2026 h12:00	17/04/2026 h18:00
1000	Venti	01 Nodi da Nord	01 nodi da N-Ovest	02 Nodi da Nord
	Temperature	+03 °C	+07 °C	+05 °C
	Temp.percepita	3 °C	7 °C	5 °C
2000	Venti	01 Nodi da Nord	01 nodi da N-Ovest	02 Nodi da Nord
	Temperature	+03 °C	+07 °C	+05 °C
	Temp.percepita	3 °C	7 °C	5 °C
3000	Venti	02 Nodi da Ovest	02 nodi da N-Ovest	01 Nodi da Nord
	Temperature	-02 °C	+00 °C	+01 °C
	Temp.percepita	-2 °C	0 °C	1 °C
Zero termico		2500-2700 m.	2900-3100 m.	3000-3200 m.
Fenomeno		—	—	—
Stato del cielo				

LEGENDA FENOMENI

Assenza Fenomeni | Nebbia | Foschia | Pioggia debole | Pioggia moderata | Pioggia forte | Temporali

Nevicata debole | Nevicata moderata | Nevicata forte

STATO DEL CIELO

Sereno | Poco nuvoloso | Nuvoloso | Molto nuvoloso | Coperto

Parametri meteonivometrici registrati presso i campi di rilevamento il 16/04/2026.

Località	Comune	Quota (m.s.l.m.)	Altezza neve (cm)	Neve caduta nelle 24 ore (cm)	Temp. Min (°C)	Temp. Max (°C)	Condizioni del tempo
LA SASSA *	Sondalo (SO)	1923	40	0	N.P.	N.P.	Assenza di precipitazioni
VALAR	Valdidentro (SO)	1930	16	0	+3	+8	Assenza di precipitazioni
FORNI *	Valfurva (SO)	2207	55	0	-6	+8	Assenza di precipitazioni
CHIAREGGIO *	Chiesa in Valmalenco (SO)	1636	20	0	N.P.	N.P.	Assenza di precipitazioni
VALLE ACQUA SERIA *	Ponte di Legno (BS)	1860	18	0	N.P.	N.P.	Assenza di precipitazioni
VALLACCIA ORIENTALE *	Valdidentro (SO)	2212	83	0	N.P.	N.P.	Assenza di precipitazioni

(*) Rilievi fuori campo

L'INFORMAZIONE E' PREVENZIONE - LEGGI L'ATTUALE GRADO DI PERICOLO VALANGHE!

IL CAPO DEL CENTRO NAZIONALE METEOMONT
(Ten. Col. RFI Emanuela Gini)
FIRMA AUTOGRAFA OMESSA AI SENSI
DELL'ART.3 DEL D.LGS N.39/1993

Bollettino realizzato su scala sinottica-regionale (standard EAWS). La sua valutazione non può escludere in alcun modo la necessità di una seria e capace valutazione locale del pericolo (singolo pendio) che può essere anche sensibilmente diverso. Le previsioni meteorologiche sono relative all'orario UTC (per l'Italia +1 in inverno e +2 in estate).