Bulletin d'estimation du risque d'avalanche

(valable en dehors des pistes balisées et ouvertes)

MASSIF : Cinto Rotondo

Rédigé le jeudi 16 avril 2026 à 15h

Estimation des risques pour le : VENDREDI 17 AVRIL

DÉPARTS EN NEIGE HUMIDE

2

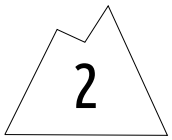

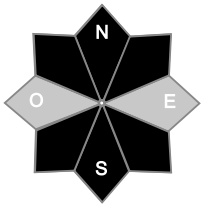

Indice de risque limité.

Départs spontanés : Avalanches de neige humide, surtout en journée, dans les pentes raides

Déclenchements provoqués : Peu probables

Indices de risque : 5 très fort - 4 fort - 3 marqué - 2 limité - 1 faible -- En noir : les pentes les plus dangereuses

Stabilité du manteau neigeux

Situation avalancheuse typique : neige humide

Départs spontanés : Les pluies des jours passés ont bien humidifié le manteau neigeux jusque vers 2200 m. Sous l'effet de la douceur et de l'ensoleillement, l'humidification se poursuit à toutes altitudes, tandis que la consolidation reste limitée, en raison d'un regel nocturne faible ou inexistant. Des coulées ou avalanches de neige humide sont à attendre, surtout en journée, principalement dans les pentes raides et bien ensoleillées, mais aucune orientation ne peut être exclue. En particulier, l'humidification en cours de la neige récente dans les pentes Nord-Ouest à Nord-Est peut donner lieu à des avalanches de taille moyenne. À noter également qu'une avalanche de fond n'est pas exclue sur les dalles rocheuses (apparition de fissures de reptation).

Déclenchements provoqués : Peu probables. Un randonneur peut provoquer un départ superficiel sous les skis, en coupant une pente raide très humidifiée. Quant aux petites plaques formées suite aux dernières chutes de neige, au-dessus de 2300 m, elles sont en voie de stabilisation.

Autres : Présence de nombreuses corniches, susceptibles de rompre à cause des conditions printanières. Persistance de quelques surfaces dures et glacées au-dessus de 2000 à 2200 m.

Qualité de la neige

Qualification de l'enneigement : L'enneigement est encore très bon pour la saison. Sur la Maniccia, à 2400 m d'altitude dans le massif du Rotondo, on relève 2m82 de hauteur de neige totale.

Limite d'enneigement skiable : vers 1600 à 1700 m en Nord, 1800 à 1900 m en Sud.

État de la neige : Regel nocturne correct en versants Nord en altitude, inexistant en dessous de 2000 à 2200 m. Rapide humidification en matinée. En moyenne montagne, neige très humide à pourrie.

Au-dessus de 2200 m en Nord, surface du manteau neigeux assez hétérogène avec alternance de neige dure et travaillée par le vent, de neige colorée par le sable décaillant l'après-midi. Présence d'une neige récente, entre 10 et 20 cm au-dessus de 2300 m, souvent de la neige roulée ou de la neige lourde et humide. Elle peut rester poudreuse au-dessus de 2500m.

Aperçu météo pour le vendredi 17 avril

	nuit	matin	après-midi	soir
Pluie-Neige	2 800 m			
Iso 0 °C	3 100 m	3 100 m	3 200 m	3 300 m
Vent 1500 m	← 10 km/h	↙ 15 km/h	↓ 15 km/h	↙ 15 km/h
Vent 3000 m	↙ 20 km/h	↓ 15 km/h	↓ 15 km/h	↓ 20 km/h

Risque d'averses de pluie l'après-midi sur les sommets et versants occidentaux.

Épaisseur de neige hors-piste

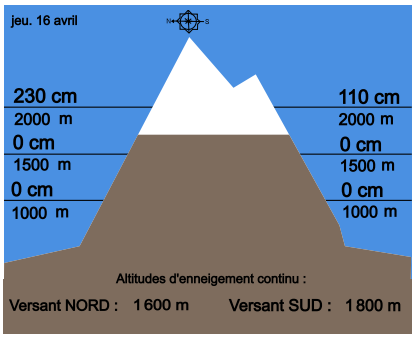

Précipitations à 1800 m

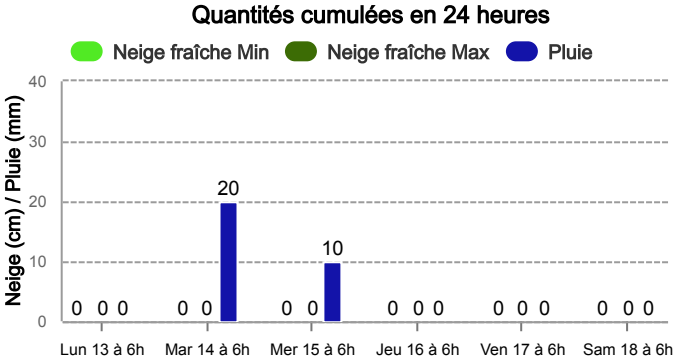

Tendance du samedi 18 avril

2

Indice de risque limité

Départs en neige humide. Risque stationnaire ou en légère baisse, dû à un regel nocturne plus efficace.

Pour consulter la vigilance en cours, veuillez vous rendre sur le site https://vigilance.meteofrance.fr/fr

Météo-France - 73 avenue de Paris, 94165 Saint-Mandé cedex - Contact : contact@meteo.fr

Rédigé par Météo-France avec la contribution des observateurs du réseau nivo-météorologiques. Partenariat : ANMSM (Maires de Stations de Montagne), DSF (Domaines Skiables de France), ADSP (Directeurs de Pistes et de la Sécurité des Stations de Sports d'Hiver) et autres acteurs de la montagne.

Bulletin neige & avalanches par téléphone au 0 892 68 10 20 Service 0,35 € / min + prix appel

RÉPUBLIQUE FRANÇAISE
Liberté Égalité Fraternité

METEO FRANCE
À VOS CÔTÉS, DANS UN CLIMAT QUI CHANGE

Bulletin d'estimation du risque d'avalanche

(valable en dehors des pistes balisées et ouvertes)

MASSIF : Cinto Rotondo

Rédigé le jeudi 16 avril 2026 à 15h

Conditions nivo-météo des 7 derniers jours

	ven. 10/04				sam. 11/04				dim. 12/04				lun. 13/04				mar. 14/04				mer. 15/04				jeu. 16/04			
	03h	09h	15h	21h	03h	09h	15h	21h	03h	09h	15h	21h	03h	09h	15h	21h	03h	09h	15h	21h	03h	09h	15h	21h	03h	09h	15h	21h
Météo																												
Vent (km/h)	35	30	25	20	30	25	15	5	10	25	20	30	80	50	25	15	15	15	20	30	30	30	25	30	30	20	20	20
à 3000m																												
Vent (km/h)	25	25	20	15	20	20	20	5	10	25	20	25	45	35	20	10	15	15	20	25	30	30	25	20	20	15	10	20
à 1500m																												

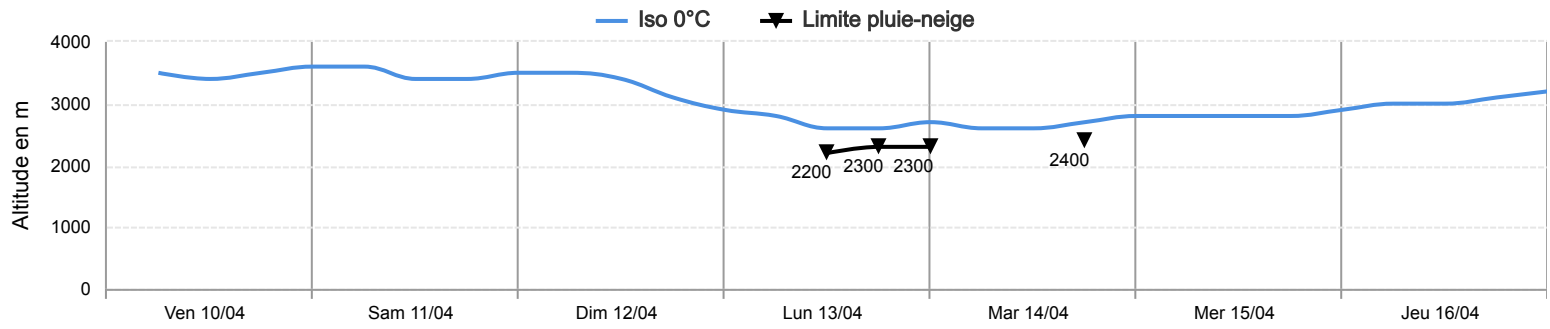

Neige fraîche à 06h

ven. 10/04	sam. 11/04	dim. 12/04	lun. 13/04	mar. 14/04	mer. 15/04	jeu. 16/04
0 cm	0 cm	0 cm	0 cm	0 cm	0 cm	

Risque d'avalanche	ven. 10/04	sam. 11/04	dim. 12/04	lun. 13/04	mar. 14/04	mer. 15/04	jeu. 16/04
	3	3	2	2	3	3	2

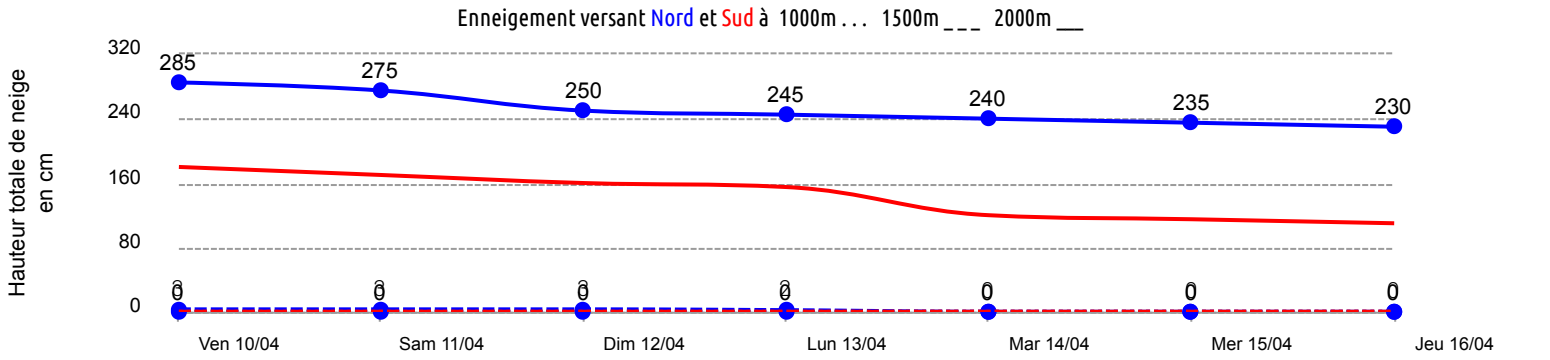

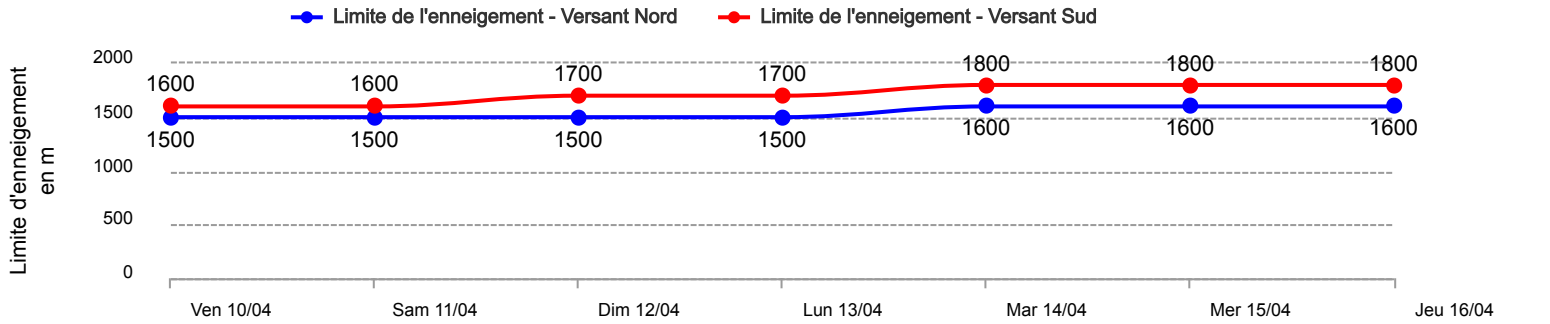

Pour consulter la vigilance en cours, veuillez vous rendre sur le site https://vigilance.meteofrance.fr/fr

Météo-France - 73 avenue de Paris, 94165 Saint-Mandé cedex - Contact : contact@meteo.fr

Rédigé par Météo-France avec la contribution des observateurs du réseau nivo-météorologiques. Partenariat : ANMSM (Maires de Stations de Montagne), DSF (Domaines Skiables de France), ADSP (Directeurs de Pistes et de la Sécurité des Stations de Sports d'Hiver) et autres acteurs de la montagne.

Bulletin neige & avalanches par téléphone au
0 892 68 10 20 Service 0,35 € / min + prix appel