Bulletin d'estimation du risque d'avalanche

(valable en dehors des pistes balisées et ouvertes)

MASSIF : Aspe Ossau

Rédigé le jeudi 16 avril 2026 à 16h

Estimation des risques pour le : VENDREDI 17 AVRIL

STRUCTURES DE PLAQUES EN ZONES OMBRAGÉES D'ALTITUDE, POURSUITE DE L'HUMIDIFICATION PARTOUT AILLEURS.

2

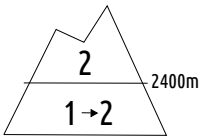

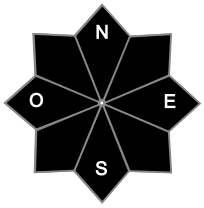

Plaques et soleil.

Au-dessus de 2400m indice de risque limité, plus bas indice faible évoluant en limité.

Départs spontanés : Dans la neige humide au fil de l'ensoleillement, avalanches de fond possibles.

Déclenchements provoqués : Plaques dans les zones ombragées d'altitude, dans la neige humide partout ailleurs.

Indices de risque : 5 très fort - 4 fort - 3 marqué - 2 limité - 1 faible -- En noir : les pentes les plus dangereuses

Stabilité du manteau neigeux

Situation avalancheuse typique : neige humide — neige ventée

Départs spontanés :
L'activité avalancheuse reste limitée tôt le matin par un bon regel. Puis, des départs ponctuels dans la neige humide sont attendus dans les pentes raides des versants au fil de la journée et de l'ensoleillement. De petites avalanches (taille 1), voire parfois des moyennes (taille 2) sont possibles d'abord préférentiellement des versants Est à Sud le matin, puis rapidement des versants Sud à Ouest dans la journée. De grandes avalanches restent parfois possibles (taille 3) dans les zones d'accumulation importantes. Des avalanches de fond peuvent aussi se produire dans les pentes raides, préférentiellement près des fissures et des reptations. Elles peuvent être petites à moyennes (taille 1 à 2), voire grandes (taille 3) en partant d'une zone d'accumulation importante en altitude.

Déclenchements provoqués :
Au-dessus de 2400m environ, des structures de plaques peuvent encore être en place dans les pentes raides des versants ombragés (principalement Nord-Ouest, Nord et Nord-Est) issues des chutes de neige précédentes. Un simple skieur peut déclencher ces plaques, engendrant de petites avalanches (taille 1), parfois moyennes (taille 2).
Partout ailleurs, un skieur peut déclencher des départs ponctuels dans la neige humide et dans les pentes raides des versants au fil de la journée et de l'ensoleillement. Un bon regel devrait limiter cette activité tôt le matin, mais concernera ensuite préférentiellement les versants Est à Sud le matin, puis les versants Sud à Ouest en journée. De petites avalanches ou des moyennes sont possibles (taille 1 à 2), parfois de grandes avalanches (taille 3) dans les zones d'accumulation importantes.

Autres :
Neige dure et glissante au petit matin. Avec la douceur ambiante, les corniches et pont de neige deviennent à nouveau très fragiles.

Qualité de la neige

Enneigement : L'enneigement est plutôt pour la saison, débutant vers 1650m en nord, 1950m environ en sud. Cette limite d'enneigement tend à remonter progressivement avec la douceur ambiante et le soleil.
État de la neige : Neige bien regelée à dure le matin, s'humidifiant progressivement au fil de la journée et de la douceur ambiante. Au-dessus de 2300 à 2400m, dans les pentes raides des versants ombragés (principalement du Nord-Ouest au Nord-Est), on trouve encore parfois une bonne épaisseur de neige sèche à meuble, reposant sur un fond dur à regelé.

Aperçu météo pour le vendredi 17 avril

	nuit	matin	après-midi	soir

Temps sec et bien ensoleillé, ciel voilé en altitude. Quelques nuages accrochant les sommets l'après-midi. Douceur ambiante.

Pluie-Neige				
Iso 0 °C	3 400 m	3 400 m	3 500 m	3 300 m
Vent 1500 m	5 km/h	5 km/h	5 km/h	5 km/h
Vent 3000 m	10 km/h	10 km/h	10 km/h	10 km/h

Épaisseur de neige hors-piste

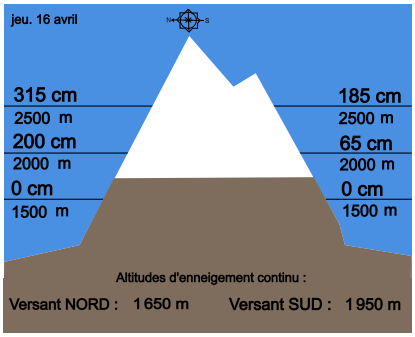

Précipitations à 1800 m

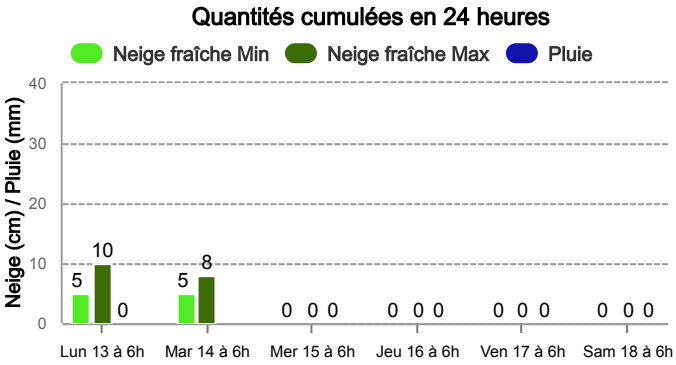

Tendance du samedi 18 avril

2

Indice de risque limité

Maintien d'un risque limité. Poursuite de l'humidification en profondeur du manteau neigeux avec les averses de samedi après-midi et la douceur ambiante, stabilisation progressive des plaques dans les versants ombragés d'altitude.

Pour consulter la vigilance en cours, veuillez vous rendre sur le site https://vigilance.meteofrance.fr/fr

Météo-France - 73 avenue de Paris, 94165 Saint-Mandé cedex - Contact : contact@meteo.fr

Rédigé par Météo-France avec la contribution des observateurs du réseau nivo-météorologiques. Partenariat : ANMSM (Maires de Stations de Montagne), DSF (Domaines Skiables de France), ADSP (Directeurs de Pistes et de la Sécurité des Stations de Sports d'Hiver) et autres acteurs de la montagne.

Bulletin neige & avalanches par téléphone au 0 892 68 10 20 Service 0,35 € / min + prix appel

RÉPUBLIQUE FRANÇAISE
Liberté Égalité Fraternité

METEO FRANCE
À VOS CÔTÉS, DANS UN CLIMAT QUI CHANGE

Bulletin d'estimation du risque d'avalanche

(valable en dehors des pistes balisées et ouvertes)

MASSIF : Aspe Ossau

Rédigé le jeudi 16 avril 2026 à 16h

Conditions nivo-météo des 7 derniers jours

	ven. 10/04				sam. 11/04				dim. 12/04				lun. 13/04				mar. 14/04				mer. 15/04				jeu. 16/04			
	03h	09h	15h	21h	03h	09h	15h	21h	03h	09h	15h	21h	03h	09h	15h	21h	03h	09h	15h	21h	03h	09h	15h	21h	03h	09h	15h	21h
Météo																												
Vent (km/h)	20	35	35	45	40	45	35	60	30	25	20	30	55	45	35	30	30	35	30	20	20	15	15	15	15	15	10	10
à 3000m																												
Vent (km/h)	5	5	10	25	25	25	20	10	15	10	10	10	15	15	10	5	15	20	25	10	10	10	10	5	5	5	5	5
à 1500m																												

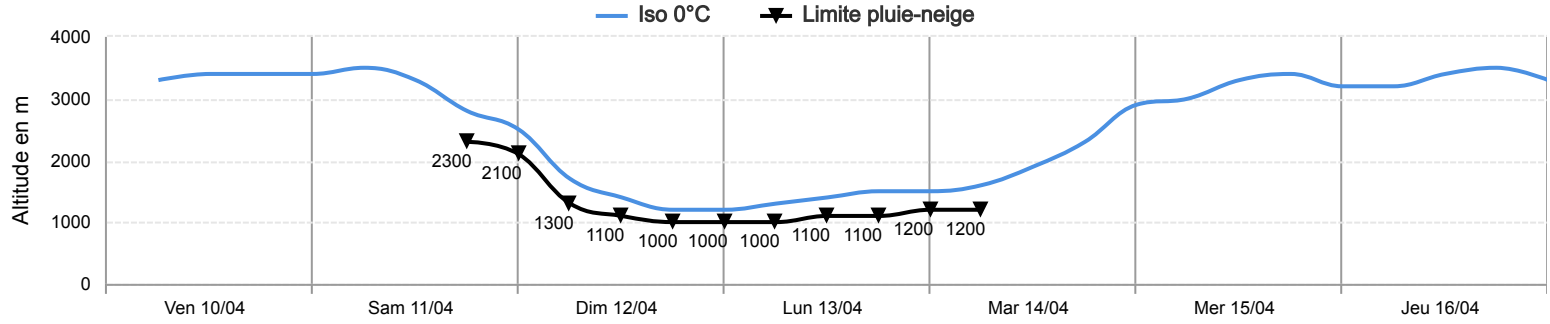

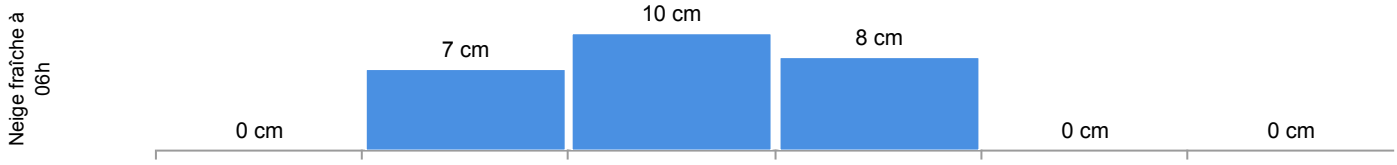

Risque d'avalanche	ven. 10/04	sam. 11/04	dim. 12/04	lun. 13/04	mar. 14/04	mer. 15/04	jeu. 16/04
	2	2	2	3	2	2	2

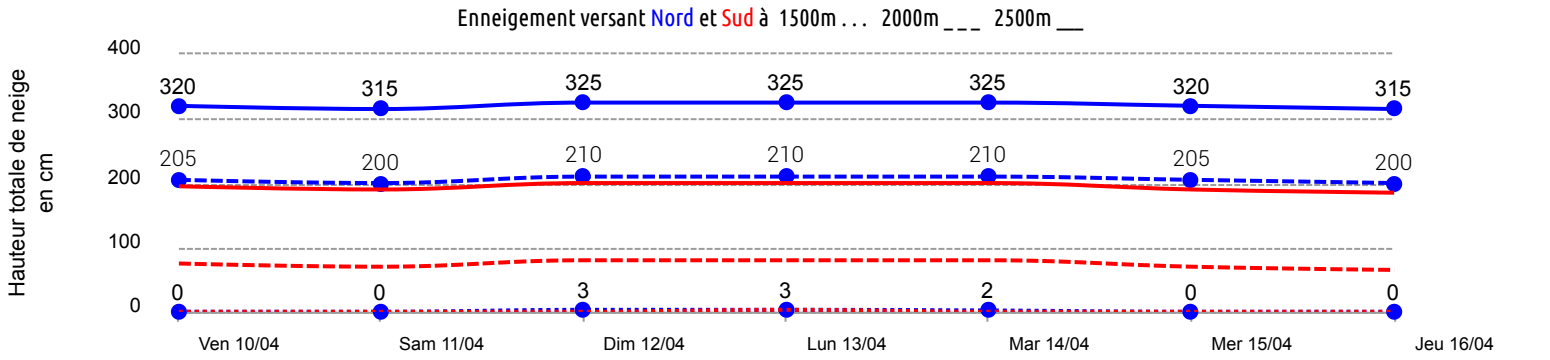

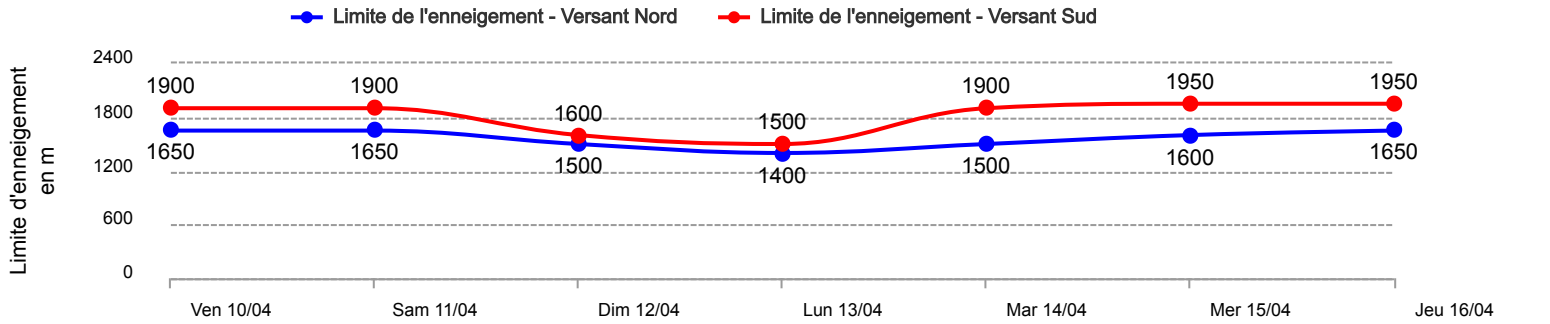

Pour consulter la vigilance en cours, veuillez vous rendre sur le site https://vigilance.meteofrance.fr/fr

Météo-France - 73 avenue de Paris, 94165 Saint-Mandé cedex - Contact : contact@meteo.fr

Rédigé par Météo-France avec la contribution des observateurs du réseau nivo-météorologiques. Partenariat : ANMSM (Maires de Stations de Montagne), DSF (Domaines Skiables de France), ADSP (Directeurs de Pistes et de la Sécurité des Stations de Sports d'Hiver) et autres acteurs de la montagne.

Bulletin neige & avalanches par téléphone au
0 892 68 10 20 Service 0,35 € / min + prix appel