RÉPUBLIQUE FRANÇAISE
Liberté Égalité Fraternité

METEO FRANCE
À VOS CÔTÉS, DANS UN CLIMAT QUI CHANGE

Bulletin d'estimation du risque d'avalanche
(valable en dehors des pistes balisées et ouvertes)

MASSIF : Cerdagne Canigou

Rédigé le jeudi 16 avril 2026 à 16h

Estimation des risques pour le : VENDREDI 17 AVRIL

HUMIDIFICATION QUI PROGRESSE EN JOURNÉE ; RARES INSTABILITÉS EN NEIGE SÈCHE EN ALTITUDE

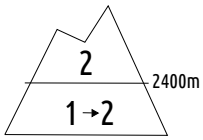

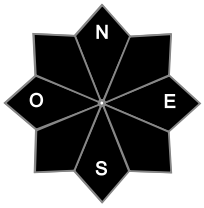

Au-dessus de 2400m indice de risque limité, plus bas indice faible évoluant en limité.

Départs spontanés : Départs plutôt ponctuels en neige humide

Déclenchements provoqués : Persistance de rares plaques en altitude

Indices de risque : 5 très fort - 4 fort - 3 marqué - 2 limité - 1 faible -- En noir : les pentes les plus dangereuses

Stabilité du manteau neigeux

Situation avalancheuse typique : neige humide neige ventée

Départs spontanés :
- Peu probable en début de journée grâce à un regel efficace. Au fil de la journée, dans les pentes ensoleillées, des départs spontanés d'avalanches de taille petite à moyenne sont attendus avec la douceur et l'ensoleillement. Ces départs emportent la neige récente, et dans de rares cas des couches plus anciennes avec une éventuelle avalanche de moyenne, voire grande taille.
- Des reptations peuvent également être présentes, signes avant-coureurs de potentielles avalanches de glissement emportant l'ensemble du manteau neigeux.

Déclenchements provoqués :
- Avalanches de plaques, encore déclenchables par un pratiquant, plutôt au-dessus de 2300/2400m. Des accumulations en neige récente non encore humidifiée subsistent par endroits, plutôt à proximité des crêtes et dans les secteurs ombragés. Ces plaques peu épaisses et plus ou moins friables se sont formées ces derniers jours avec transport de neige par le vent. *Observables : signe de transport de neige par le vent avec de la neige de surface changeante, fissures devant les skis.*
- Par ailleurs, dans les secteurs en neige humide, un skieur coupant une pente raide pourra également déclencher une coulée sous ses skis.

Autre : Des corniches, parfois imposantes, sont en place et sont susceptibles de céder spontanément.

Qualité de la neige

Enneigement :
Excellent enneigement pour avril, parmi les plus importants des 30 dernières années. Malgré le redoux et le soleil, la limite skiable ne remonte que progressivement (1600/1700 m en nord, et 1800/2000 m en sud). L'épaisseur de neige est rapidement conséquente avec 168 cm le 16/04 à 14h à 2160 m à la station du Canigou et plus encore en altitude (> 3m de neige).

Qualité de la neige :
Vendredi matin, regel bien efficace et portant dès 1800/2000 m, moins bon plus bas et dans la forêt. En journée, reprise rapide de l'humidification au soleil, surtout si la couche ocre est visible. Puis la neige devient de plus en plus lourde et collante surtout à basse altitude. Les cols et crêtes les plus hauts peuvent rester en neige dure tassée par le vent.

Aperçu météo pour le vendredi 17 avril

	nuit	matin	après-midi	soir
	Ensoleillé sous des nuages d'altitude et quelques cumulus possibles l'après-midi.			
Pluie-Neige				
Iso 0 °C	3 400 m	3 400 m	3 300 m	3 500 m
Vent 2000 m	↘ 10 km/h	↙ 15 km/h	↗ 15 km/h	↘ 10 km/h
Vent 3000 m	↘ 20 km/h	↓ 20 km/h	↓ 20 km/h	↘ 20 km/h

Épaisseur de neige hors-piste

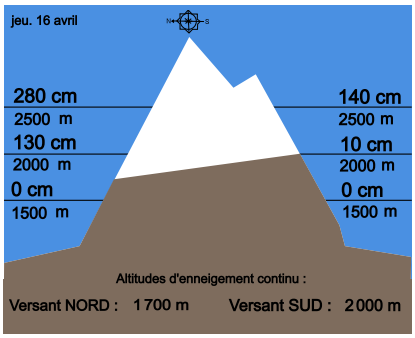

Précipitations à 1800 m

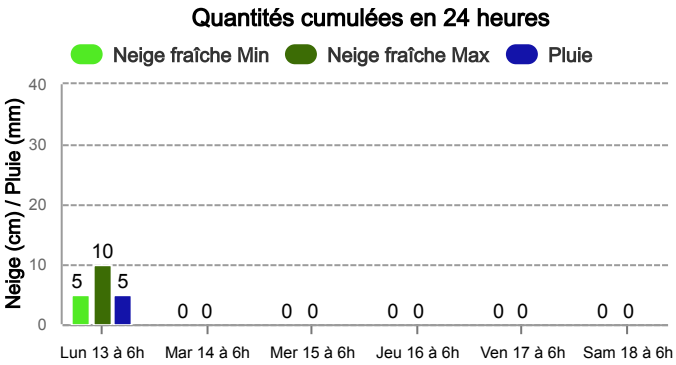

Tendance du samedi 18 avril

Indice de risque limité

Activité principalement en neige humide qui pourrait s'accélérer avec les averses de samedi après-midi.

Pour consulter la vigilance en cours, veuillez vous rendre sur le site https://vigilance.meteofrance.fr/fr

Météo-France - 73 avenue de Paris, 94165 Saint-Mandé cedex - Contact : contact@meteo.fr

Rédigé par Météo-France avec la contribution des observateurs du réseau nivo-météorologiques. Partenariat : ANMSM (Maires de Stations de Montagne), DSF (Domaines Skiables de France), ADSP (Directeurs de Pistes et de la Sécurité des Stations de Sports d'Hiver) et autres acteurs de la montagne.

Bulletin neige & avalanches par téléphone au
0 892 68 10 20 Service 0,35 € / min + prix appel

RÉPUBLIQUE FRANÇAISE
Liberté Égalité Fraternité

METEO FRANCE
À VOS CÔTÉS, DANS UN CLIMAT QUI CHANGE

Bulletin d'estimation du risque d'avalanche
(valable en dehors des pistes balisées et ouvertes)
MASSIF : Cerdagne Canigou

Rédigé le jeudi 16 avril 2026 à 16h

Conditions nivo-météo des 7 derniers jours

	ven. 10/04				sam. 11/04				dim. 12/04				lun. 13/04				mar. 14/04				mer. 15/04				jeu. 16/04			
	03h	09h	15h	21h	03h	09h	15h	21h	03h	09h	15h	21h	03h	09h	15h	21h	03h	09h	15h	21h	03h	09h	15h	21h	03h	09h	15h	21h
Météo																												
Vent (km/h)	30	20	25	25	30	30	45	45	40	30	30	20	50	50	55	55	50	50	50	45	35	25	25	20	35	30	30	25
à 3000m																												
Vent (km/h)	20	15	20	15	20	20	35	35	25	20	20	15	35	30	30	25	25	25	25	20	20	15	15	10	20	15	20	15
à 2000m																												

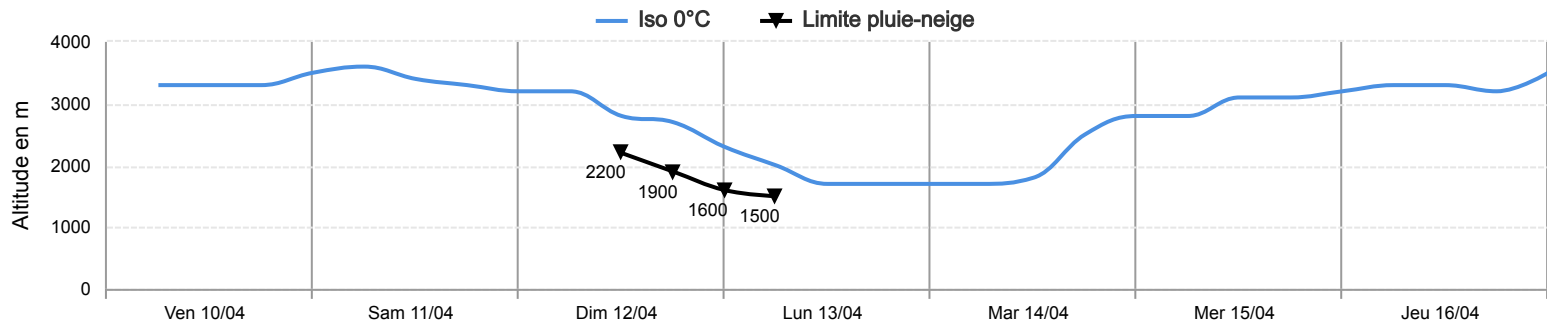

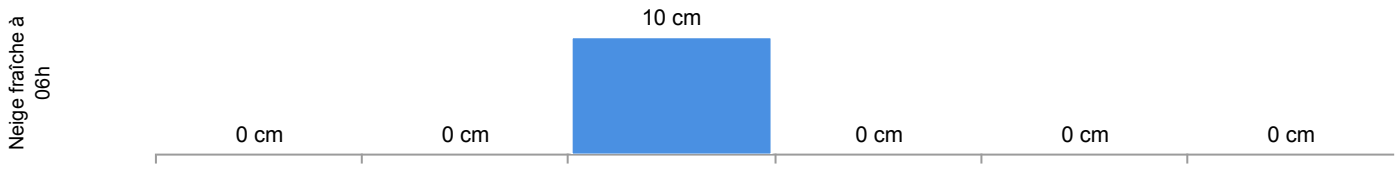

Risque d'avalanche	ven. 10/04	sam. 11/04	dim. 12/04	lun. 13/04	mar. 14/04	mer. 15/04	jeu. 16/04
	2	2	2	2	2	2	2

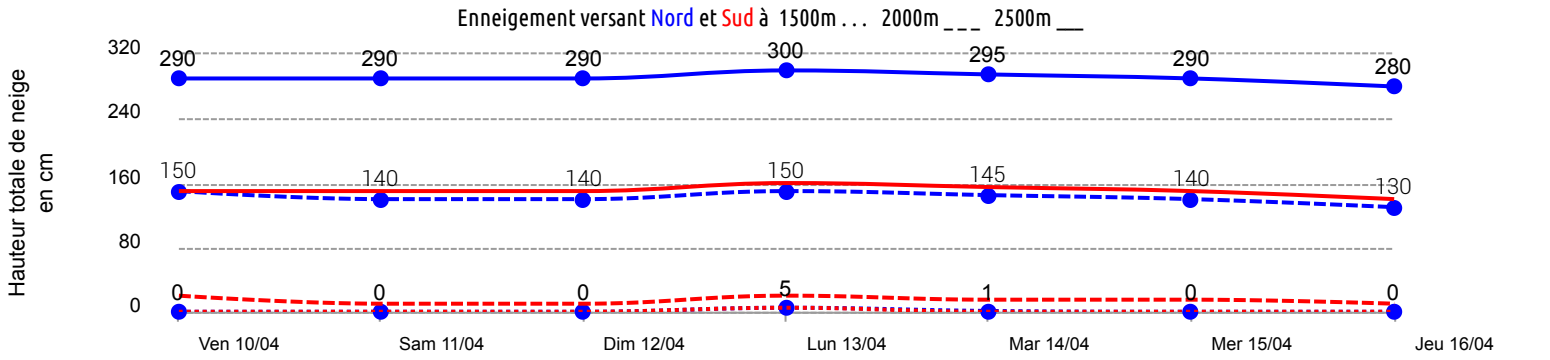

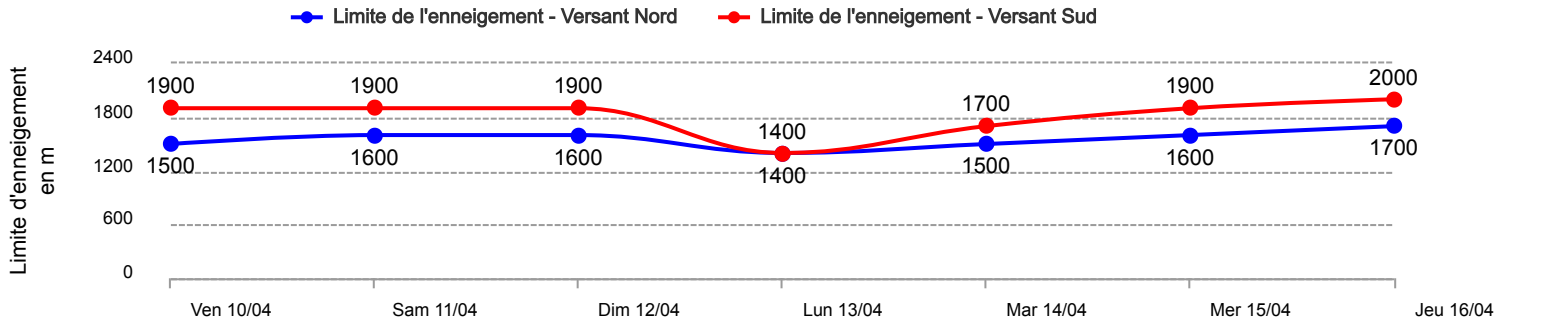

Pour consulter la vigilance en cours, veuillez vous rendre sur le site https://vigilance.meteofrance.fr/fr

Météo-France - 73 avenue de Paris, 94165 Saint-Mandé cedex - Contact : contact@meteo.fr

Bulletin neige & avalanches par téléphone au
0 892 68 10 20 Service 0,35 € / min + prix appel

Rédigé par Météo-France avec la contribution des observateurs du réseau nivo-météorologiques. Partenariat : ANMSM (Maires de Stations de Montagne), DSF (Domaines Skiables de France), ADSP (Directeurs de Pistes et de la Sécurité des Stations de Sports d'Hiver) et autres acteurs de la montagne.