Bulletin d'estimation du risque d'avalanche
(valable en dehors des pistes balisées et ouvertes)
MASSIF : Haute-Ariege

Rédigé le jeudi 16 avril 2026 à 16h

Estimation des risques pour le : VENDREDI 17 AVRIL

HUMIDIFICATION QUI PROGRESSE EN JOURNÉE ; INSTABILITÉS DEVENANT DE PLUS EN PLUS RARE EN NEIGE SÈCHE EN ALTITUDE

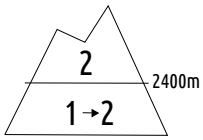

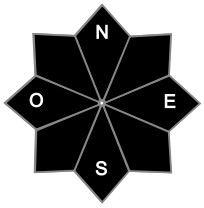

Au-dessus de 2400m indice de risque limité, plus bas indice faible évoluant en limité.

Départs spontanés : Départs plutôt ponctuels en neige humide au fil de la journée et de l'humidification

Déclenchements provoqués : Persistance de rares plaques dans la neige encore froide en altitude

Indices de risque : 5 très fort - 4 fort - 3 marqué - 2 limité - 1 faible -- En noir : les pentes les plus dangereuses

Stabilité du manteau neigeux

Situation avalancheuse typique : neige humide neige ventée

Départs spontanés :
- Peu probable en tout début de journée grâce à un regel efficace. Au fil de la journée, dans les pentes ensoleillées, des départs spontanés d'avalanches de taille petite à moyenne sont attendus avec la douceur et l'ensoleillement. Ces départs emportent la neige récente, et dans de rares cas des couches plus anciennes avec une éventuelle avalanche de moyenne, voire grande taille.
- De nombreuses reptations sont également visibles et signes avant-coureurs de potentielles avalanches de glissement pouvant emporter l'ensemble du manteau neigeux.

Déclenchements provoqués :
- Avalanches de plaques, encore déclenchables par un pratiquant, plutôt au-dessus de 2400/2500 m. Des accumulations en neige récente non encore humidifiée deviennent rares mais peuvent subsister en altitude dans les versants raides et ombragés. Ces plaques peu épaisses se sont formés avec le transport de neige par le vent des derniers jours. *Observables : signe de transport de neige par le vent avec de la neige de surface changeante, fissures devant les skis.*
- Par ailleurs, un skieur coupant une pente raide déjà humidifiée pourra déclencher une coulée sous ses skis, mobilisant parfois de bonnes quantités de neige humide.

Autre : Des corniches encore imposantes sont en place et sont susceptibles de céder spontanément avec le redoux.

Qualité de la neige

Enneigement :
Excellent, parmi un des meilleurs des 30 dernières années. Avec le redoux et le soleil, la limite skiable remonte de jour en jour, surtout en sud. Elle est encore au mieux vers 1500 m en nord et 1800 à 2000 m en sud. On trouve ensuite rapidement une bonne épaisseur de neige qui dépasse souvent les 2 m dès 2000/2200 m, et les 3 m dès 2500m.

Qualité de la neige :
Vendredi matin, regel bien efficace et portant dès 1800/2000 m, parfois moins bon plus bas et dans la forêt. En journée, reprise de l'humidification avec la neige qui s'humidifie au soleil, plus rapidement si la couche ocre est visible, avec de la neige lourde et humide dès la mi-journée. De rares endroits peuvent encore rester en neige sèche et plus légère dans les versants nord raides ou à l'ombre au-dessus de 2400/2500m. Les cols et crêtes ouest à nord-ouest sous souvent moins garnis en neige.

Aperçu météo pour le vendredi 17 avril

	nuit	matin	après-midi	soir
	Encore du beau temps sous un voile d'altitude.			
Pluie-Neige				
Iso 0 °C	3 300 m	3 400 m	3 400 m	3 400 m
Vent 2000 m	↗ 10 km/h	↘ 10 km/h	↘ 10 km/h	↑ 10 km/h
Vent 3000 m	↓ 20 km/h	↓ 20 km/h	↓ 15 km/h	→ 15 km/h

Épaisseur de neige hors-piste

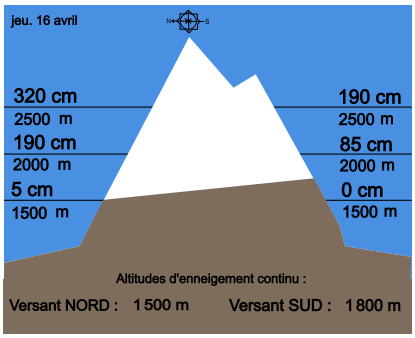

Précipitations à 1800 m

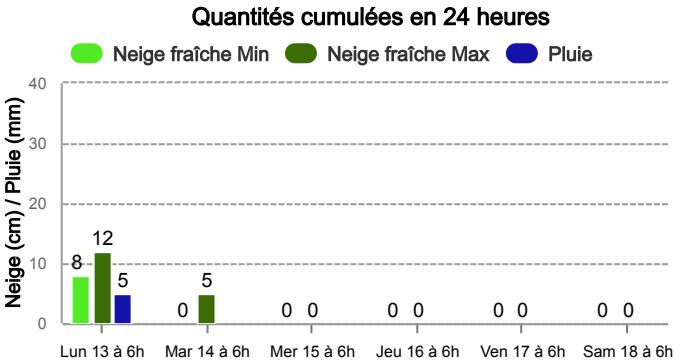

Tendance du samedi 18 avril

Indice de risque limité

Peu d'évolution et activité principalement en neige humide avec des averses samedi après-midi.

Pour consulter la vigilance en cours, veuillez vous rendre sur le site https://vigilance.meteofrance.fr/fr

Météo-France - 73 avenue de Paris, 94165 Saint-Mandé cedex - Contact : contact@meteo.fr

Rédigé par Météo-France avec la contribution des observateurs du réseau nivo-météorologiques. Partenariat : ANMSM (Maires de Stations de Montagne), DSF (Domaines Skiables de France), ADSP (Directeurs de Pistes et de la Sécurité des Stations de Sports d'Hiver) et autres acteurs de la montagne.

Bulletin neige & avalanches par téléphone au
0 892 68 10 20 Service 0,35 € / min + prix appel

RÉPUBLIQUE FRANÇAISE
Liberté Égalité Fraternité

METEO FRANCE
À VOS CÔTÉS, DANS UN CLIMAT QUI CHANGE

Bulletin d'estimation du risque d'avalanche
(valable en dehors des pistes balisées et ouvertes)
MASSIF : Haute-Ariege

Rédigé le jeudi 16 avril 2026 à 16h

Conditions nivo-météo des 7 derniers jours

	ven. 10/04				sam. 11/04				dim. 12/04				lun. 13/04				mar. 14/04				mer. 15/04				jeu. 16/04			
	03h	09h	15h	21h	03h	09h	15h	21h	03h	09h	15h	21h	03h	09h	15h	21h	03h	09h	15h	21h	03h	09h	15h	21h	03h	09h	15h	21h
Météo																												
Vent (km/h)	20	20	20	30	30	35	45	45	45	30	25	20	50	50	55	55	50	50	50	45	35	25	25	25	25	25	25	25
à 3000m																												
Vent (km/h)	10	10	10	20	20	25	35	35	15	15	15	15	35	30	30	25	25	25	25	20	20	15	15	15	15	15	15	15
à 2000m																												

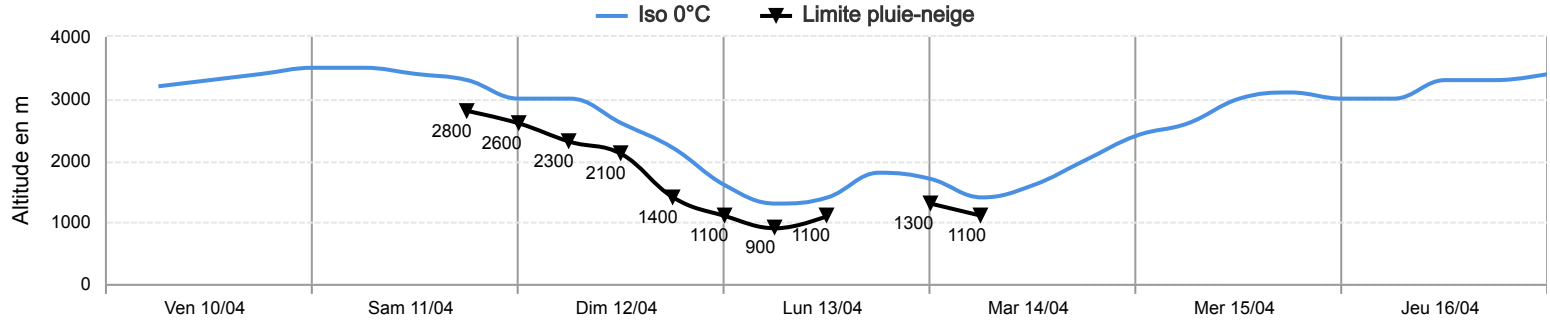

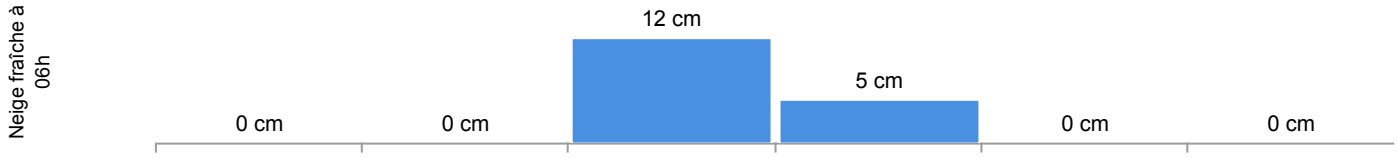

Risque d'avalanche	ven. 10/04	sam. 11/04	dim. 12/04	lun. 13/04	mar. 14/04	mer. 15/04	jeu. 16/04
	2	3	2	3	2	2	2

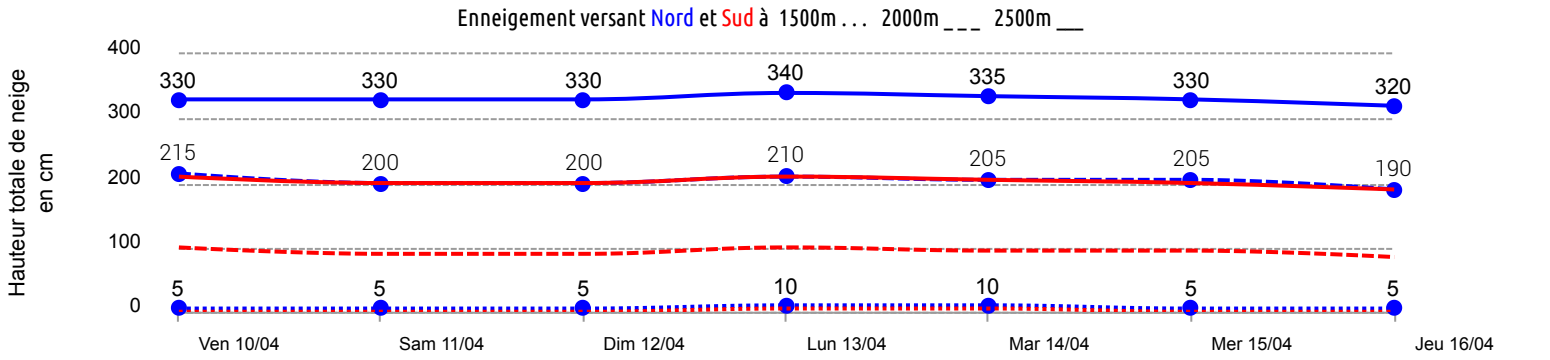

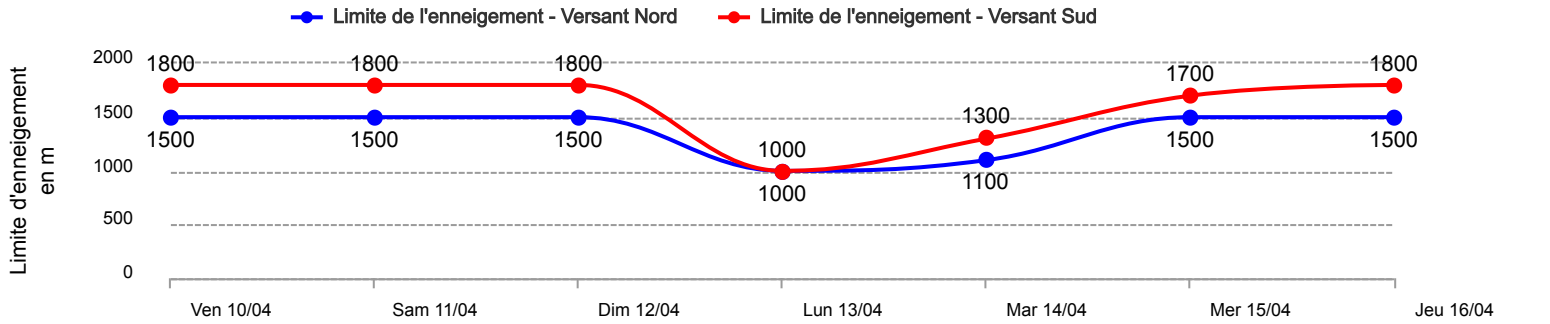

Pour consulter la vigilance en cours, veuillez vous rendre sur le site https://vigilance.meteofrance.fr/fr

Météo-France - 73 avenue de Paris, 94165 Saint-Mandé cedex - Contact : contact@meteo.fr

Bulletin neige & avalanches par téléphone au
0 892 68 10 20 Service 0,35 € / min + prix appel

Rédigé par Météo-France avec la contribution des observateurs du réseau nivo-météorologiques. Partenariat : ANMSM (Maires de Stations de Montagne), DSF (Domaines Skiables de France), ADSP (Directeurs de Pistes et de la Sécurité des Stations de Sports d'Hiver) et autres acteurs de la montagne.