Bulletin d'estimation du risque d'avalanche
(valable en dehors des pistes balisées et ouvertes)

MASSIF : Vanoise

Rédigé le jeudi 16 avril 2026 à 17h

Estimation des risques pour le : VENDREDI 17 AVRIL

MANTEAU PRINTANIER, NEIGE DURE A L'AUBE PUIS QUELQUES DÉPARTS EN NEIGE HUMIDE AU SOLEIL.

2

1 → 2

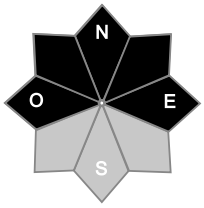

Indice de risque faible évoluant en limité.

Départs spontanés : quelques départs en neige humide.

Déclenchements provoqués : neige humide sous les skis.

Indices de risque : 5 très fort - 4 fort - 3 marqué - 2 limité - 1 faible -- En noir : les pentes les plus dangereuses

Stabilité du manteau neigeux

Situation avalancheuse typique : neige humide — avalanches de fond

Départs spontanés :
- **Quelques avalanches de neige humide** dans les **pentes ensoleillées** au fil de la journée. Ce sont généralement des départs ponctuels (poires), donnant de **petites à moyennes avalanches**. Avec l'avancée dans la saison, les pentes Sud deviennent relativement inertes avec une neige transformée sur toute l'épaisseur du manteau. Par contre, dans les versants Est, Nord et Ouest, l'humidification gagne des couches plus profondes et, si une couche fragile est atteinte, **un départ linéaire est possible**. On peut alors s'attendre, **plus rarement, à une taille 3 (grande)**.
- **Rares avalanches de glissement** (plaques de fond) à toute heure sur terrains propices, notamment en Nord sous 2500/2600 m. Taille 2.

Déclenchements provoqués : avalanche de neige humide (pourrie) sous les skis en coupant une pente trop humidifiée. Exceptionnellement une petite coulée déclenchée peut mobiliser en cascade une plaque en sollicitant une couche fragile du début de saison (grande avalanche envisageable).
Secteur Arpont-Parrachée : en Nord très raide et encaissé, au-dessus de 2800 m, une rare petite plaque d'aspect poudreux peut subsister dans la neige récente.

Autres : chutes de corniches signalées.

Qualité de la neige

Enneigement : à peine correct pour la saison, la montagne subit les assauts répétés de la chaleur excessive...

Limite skiable : vers 1500/1600 m en Nord, 1800/1900 m en Sud.

Qualité de la neige : très bon regel. Neige de printemps sauf dans le Nord raide au-delà de 2800/3000 m où on peut encore trouver un peu de neige froide. Possibilité de faire du très bon ski en trouvant le créneau de "moquette", mais les pentes Est chauffent très vite le matin.

Aperçu météo pour le vendredi 17 avril

nuit	matin	après-midi	soir

Très belle matinée, puis le ciel se voile assez densément l'après-midi : jour blanc temporaire possible. Grande douceur.

Pluie-Neige				
Iso 0 °C	3 200 m	3 200 m	3 200 m	3 200 m
Vent 2500 m	→ 5 km/h	↗ 5 km/h	→ 10 km/h	↘ 10 km/h
Vent 3500 m	↘ 10 km/h	→ 15 km/h	→ 15 km/h	→ 15 km/h

Épaisseur de neige hors-piste

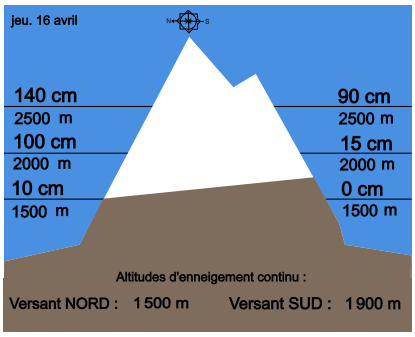

Précipitations à 1800 m

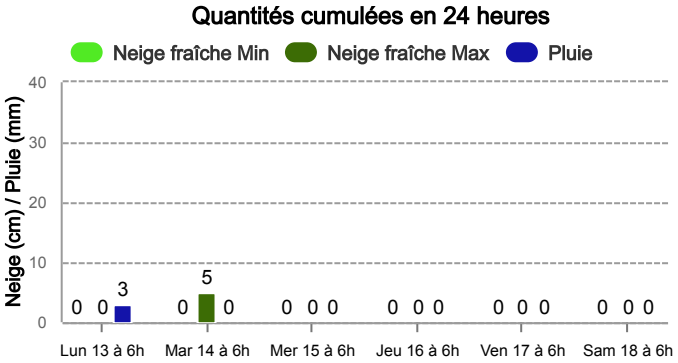

Tendance du samedi 18 avril

2

Indice de risque limité

Très peu d'évolution à attendre, le printemps se poursuit et il convient de "tenir l'horaire".

Pour consulter la vigilance en cours, veuillez vous rendre sur le site https://vigilance.meteofrance.fr/fr

Météo-France - 73 avenue de Paris, 94165 Saint-Mandé cedex - Contact : contact@meteo.fr

Rédigé par Météo-France avec la contribution des observateurs du réseau nivo-météorologiques. Partenariat : ANMSM (Maires de Stations de Montagne), DSF (Domaines Skiables de France), ADSP (Directeurs de Pistes et de la Sécurité des Stations de Sports d'Hiver) et autres acteurs de la montagne.

Bulletin neige & avalanches par téléphone au **0 892 68 10 20** Service 0,35 € / min + prix appel

RÉPUBLIQUE FRANÇAISE
Liberté Égalité Fraternité

METEO FRANCE
À VOS CÔTÉS, DANS UN CLIMAT QUI CHANGE

Bulletin d'estimation du risque d'avalanche
(valable en dehors des pistes balisées et ouvertes)

MASSIF : Vanoise

Rédigé le jeudi 16 avril 2026 à 17h

Conditions nivo-météo des 7 derniers jours

	ven. 10/04				sam. 11/04				dim. 12/04				lun. 13/04				mar. 14/04				mer. 15/04				jeu. 16/04			
	03h	09h	15h	21h	03h	09h	15h	21h	03h	09h	15h	21h	03h	09h	15h	21h	03h	09h	15h	21h	03h	09h	15h	21h	03h	09h	15h	21h
Météo																												
Vent (km/h)	20	20	30	20	30	30	25	25	30	30	35	35	35	30	30	20	15	20	20	15	10	10	10	10	15	15	15	10
à 3500m																												
Vent (km/h)	15	15	25	10	10	10	10	15	15	20	30	30	25	20	20	10	10	15	15	10	5	5	5	5	10	10	10	5
à 2500m																												

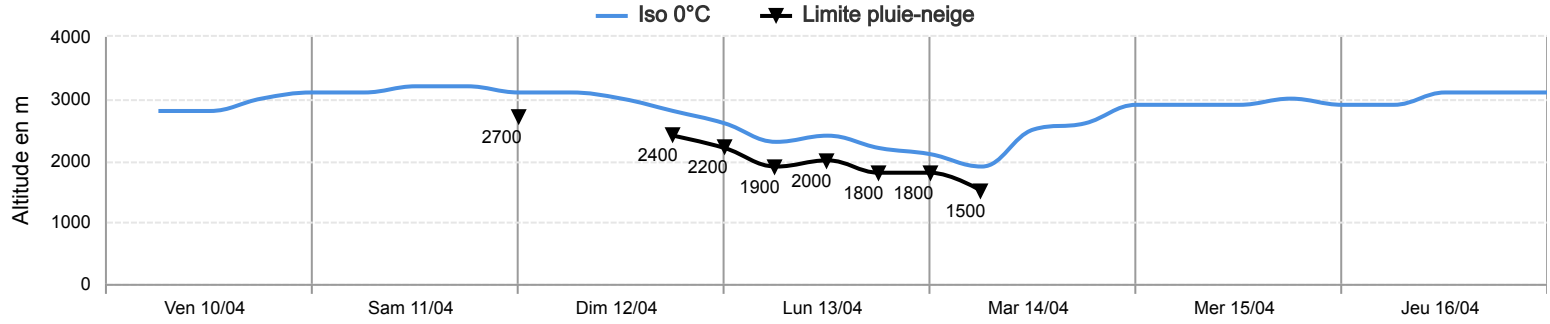

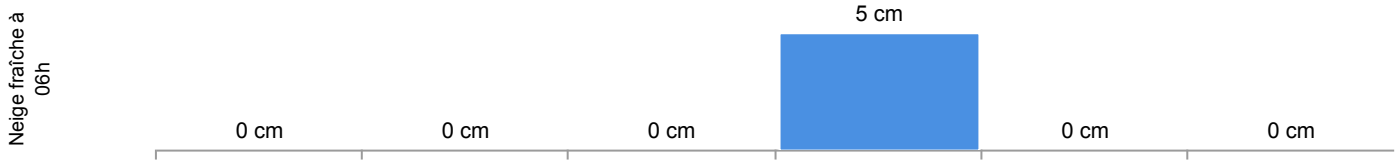

Risque d'avalanche	ven. 10/04	sam. 11/04	dim. 12/04	lun. 13/04	mar. 14/04	mer. 15/04	jeu. 16/04
	3	3	2	2	2	2	2

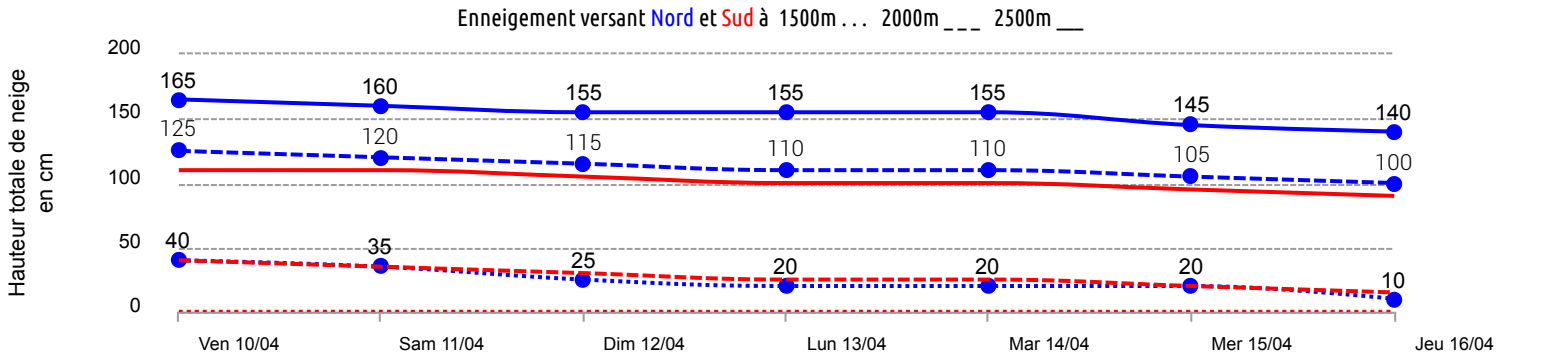

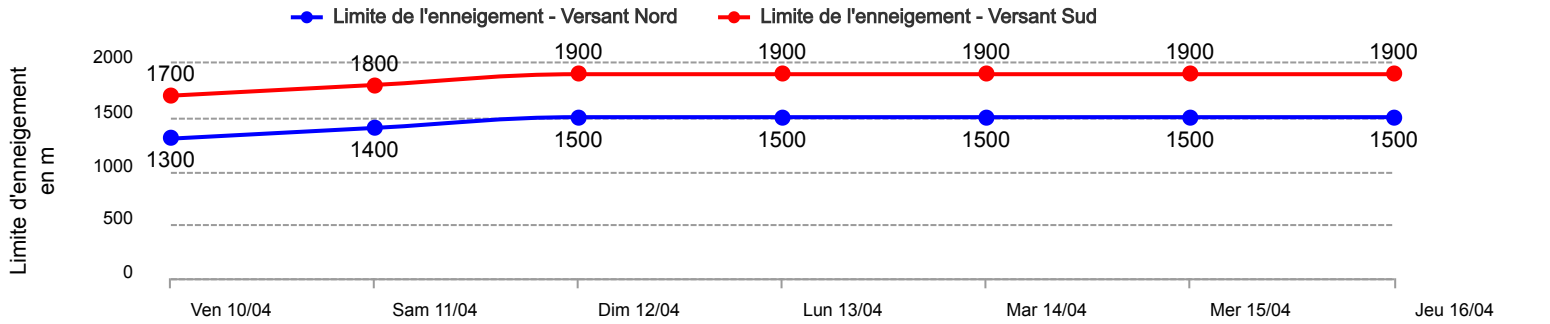

Pour consulter la vigilance en cours, veuillez vous rendre sur le site https://vigilance.meteofrance.fr/fr

Météo-France - 73 avenue de Paris, 94165 Saint-Mandé cedex - Contact : contact@meteo.fr

Rédigé par Météo-France avec la contribution des observateurs du réseau nivo-météorologiques. Partenariat : ANMSM (Maires de Stations de Montagne), DSF (Domaines Skiables de France), ADSP (Directeurs de Pistes et de la Sécurité des Stations de Sports d'Hiver) et autres acteurs de la montagne.

Bulletin neige & avalanches par téléphone au
0 892 68 10 20
Service 0,35 € / min + prix appel