GOBIERNO DE ESPAÑA
VICEPRESIDENCIA TERCERA DEL GOBIERNO
MINISTERIO PARA LA TRANSICIÓN ECOLÓGICA Y EL RETO DEMOGRÁFICO

Boletín de información nivológica y de peligro de aludes

Pirineo Navarro y Aragonés

aemet Agencia Estatal de Meteorología

viernes, 17 de abril de 2026

Pronóstico hasta las 24 horas del sábado, día 18 de abril

(Válido fuera de pistas de esquí balizadas y abiertas)

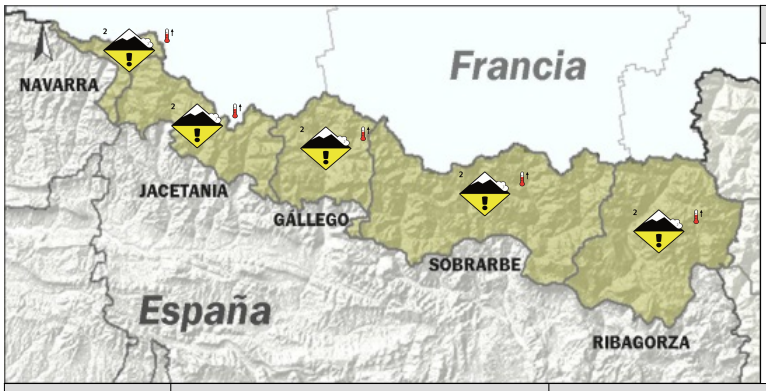

Problemas de aludes

Nieve húmeda

Deslizamientos basales

Macizo	Peligro	Problemas de aludes, cota, orientación, tamaño	Innivación observada (m)
Navarra	2 — 2 — Limitado	Nieve húmeda: 2 — N, O, E, S — 2 Deslizamientos basales: 2 — N, O, E, S — 2	2026-04-17 N / S Cota más baja caras N
Jacetania	2 — 2 — Limitado	Nieve húmeda: 2 — N, O, E, S — 2 Deslizamientos basales: 2 — N, O, E, S — 2	2026-04-17 N / S Cota más baja caras N
Gállego	2 — 2 — Limitado	Nieve húmeda: 2 — N, O, E, S — 2 Deslizamientos basales: 2 — N, O, E, S — 2	2026-04-17 N / S Cota más baja caras N

AEMET. Se autoriza la reproducción de su contenido citando la fuente.

Boletín de información nivológica y de peligro de aludes

Pirineo Navarro y Aragonés

Sobrarbe	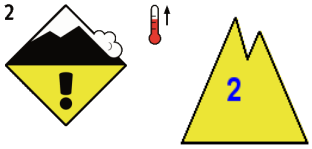 **Limitado**	**Nieve húmeda**  **Deslizamientos basales** 	2026-04-17 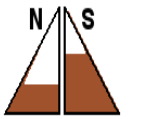 Cota más baja caras N
Ribagorza	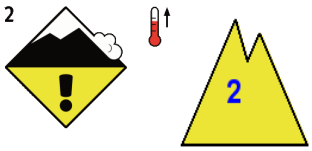 **Limitado**	**Nieve húmeda** **Deslizamientos basales** 	2026-04-17 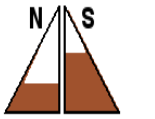 Cota más baja caras N

Estado del manto y observaciones recientes

El tiempo primaveral sigue haciendo merma en un manto en claro retroceso, en el que el proceso de humidificación es cada vez más notable y afecta a todas las altitudes, registrándose pérdidas diarias de 1-10 cm en la red de observación. Como consecuencia, la cubierta nivosa ha ido retrocediendo a altitudes cada vez más elevadas, siendo más o menos continua a partir de los 1700-1900 metros en umbrías y los 1900-2100 metros en solanas. Los espesores se van incrementando a medida que ascendemos, estando todavía muy por encima de lo que cabría esperar a estas alturas de la temporada. A unos 2200 metros todavía se puede superar el metro, aún más en ventisqueros, hoyas y otras zonas propensas a la acumulación.
El manto es de tipo primaveral, está muy humedecido y en proceso de fusión. El rehielo nocturno es débil, cada vez menos efectivo y está restringido a la alta montaña. Las costras superficiales que se forman durante la noche tienden a fundirse rápidamente con el calentamiento diurno.

Evolución del manto y peligro de aludes para el sábado, día 18

Problemas de nieve húmeda y deslizamientos basales. Problema de placas de viento en cotas altas.

Mañana las temperaturas continuarán ascendiendo y las heladas quedarán restringidas a las cumbres. Así mismo se esperan algunas precipitaciones, en forma líquida hasta unos 2800 metros, que podrán contribuir a una humidificación todavía más intensa del manto. Con todo esto, los problemas de nieve húmeda se presentarán ya desde el comienzo del día, afectando pronto a todas las orientaciones e incrementándose durante las horas centrales. En laderas suficientemente inclinadas, serán probables las purgas espontáneas o provocadas de tamaño pequeño (peligro de caída) o mediano (capaz de enterrar a una persona), más probables y frecuentes en solanas a partir del mediodía y en zonas próximas a afloramientos rocosos.

AEMET. Se autoriza la reproducción de su contenido citando la fuente.

Además, en zonas de manto delgado sobre laderas herbosas o de roca lisa muy inclinadas, también se esperan deslizamientos basales de tamaño generalmente mediano, sin descartar que se pueda alcanzar el tamaño localmente grande (capaz de enterrar a un grupo de personas).
Todavía podría quedar alguna placa de viento en umbrías por encima de los 2400 metros que no se haya estabilizado del todo. Ante una sobrecarga débil (paso de un esquiador) estas podrían colapsar y provocar aludes de tamaño pequeño o más raramente mediano.

Predicción meteorológica para el sábado, día 18

Pirineo navarro:
Nuboso o con intervalos de nubes bajas, medias y de evolución diurna, así como velos de nubosidad alta. Probables precipitaciones débiles y chubascos en la segunda mitad del día, sin descartar que en algún caso puedan ser localmente fuertes por la tarde. Se esperan tormentas acompañando a los chubascos. Temperaturas mínimas en ligero ascenso, localmente moderado. Máximas sin apenas cambios. Viento flojo de componente sur, de componente oeste en cotas altas, donde irá acompañado de intervalos de moderado. En áreas de chubasco podrá soplar fuerte y racheado.

Pirineo aragonés:
Nuboso o con intervalos de nubes bajas, medias y de evolución diurna, así como velos de nubosidad alta. Se esperan chubascos a partir de las horas centrales. Cota de nieve en torno a 2700-2900 metros. Se esperan tormentas acompañando a los chubascos. Temperaturas en ligero ascenso, localmente moderado en las mínimas. Heladas débiles en las cumbres de mayor altitud. Viento flojo de dirección variable, de componente oeste en cotas altas, donde irá acompañado de intervalos de moderado. En áreas de chubasco podrá soplar fuerte y racheado.

Datos en la atmósfera libre:

Altitud de la isoterma de 0 ºC: 3300 m
Altitud de la isoterma de -10 ºC: 4800 m

Viento a 1500 m: VRB 5 km/h
Viento a 3000 m: SW 10 km/h

Evolución para el domingo día 19

Nivel de peligro sin cambios o en ligero ascenso.

(Información elaborada a partir de los datos recibidos de los refugios de Linza, Lizara, Respomuso, Panticosa, Bachimaña, Góriz, Pineta, Estós, Angel Orús, La Renclusa, Cap de Llauset y Belagua, de las estaciones de esquí de Formigal y Panticosa (lagos) y de Ordesa Pradera)

Escala europea de peligro de aludes

Débil Limitado Notable Fuerte Muy Fuerte

Problemas de aludes

Nieve reciente Placas de viento Capas débiles persistentes Nieve húmeda Deslizamientos basales Sin problema evidente

Nota1: Se recuerda que, siempre que haya nieve, la ausencia total de peligro no existe. Hay que tener presente que en circunstancias desfavorables, con aludes de tamaño 1 (alud pequeño o colada) y tamaño 2 (alud mediano), se pueden sufrir severos daños personales.

AEMET. Se autoriza la reproducción de su contenido citando la fuente.

Nota2: Los BPA se elaboran en base a información meteorológica así como al estado del manto nivoso a través de sondeos puntuales. Se advierte a los usuarios de la variabilidad de esta información al extrapolarla a zonas extensas de montaña. Por ello, AEMET no se hace responsable de su uso para la toma de decisiones que conciernen a la seguridad personal, ni de los riesgos físicos o materiales de ellas derivadas.

AEMET. Se autoriza la reproducción de su contenido citando la fuente.