Samstag 18.04.2026

Veröffentlicht am 17.04.2026 um 17:00

Vormittag

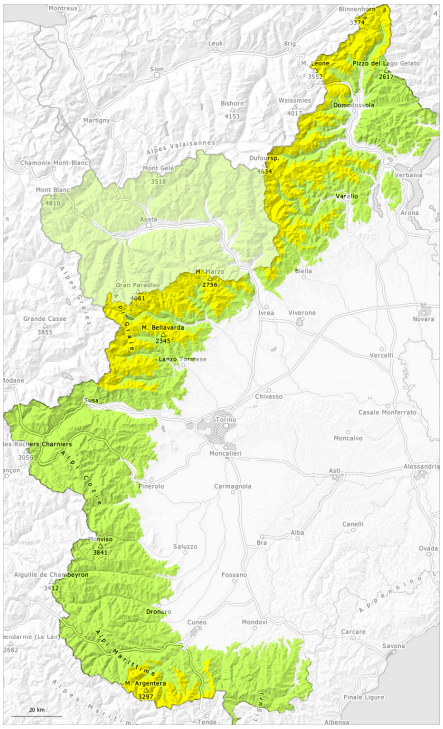

Nachmittag

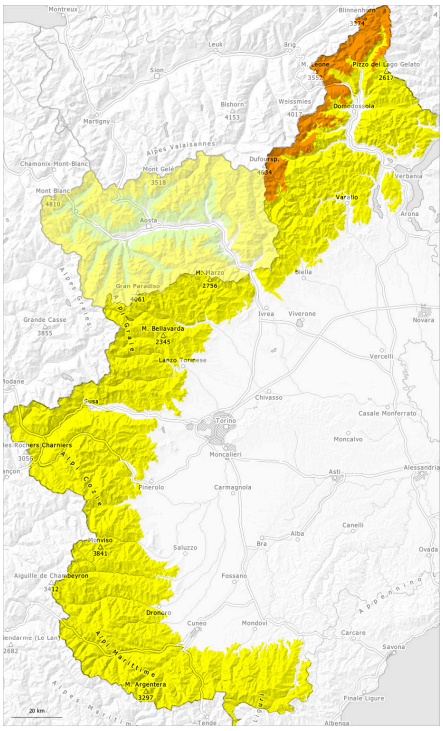

1	2	3	4	5
gering	mäßig	erheblich	groß	sehr groß

Samstag 18.04.2026

Veröffentlicht am 17.04.2026 um 17:00

Gefahrenstufe 3 - Erheblich

AM:

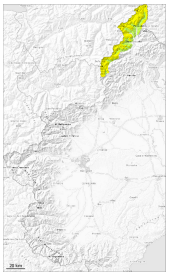

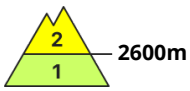

Tendenz: Lawinengefahr nimmt ab
am Sonntag, den 19.04.2026

Altschnee

2600m

PM:

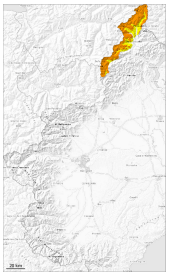

Tendenz: Lawinengefahr nimmt ab
am Sonntag, den 19.04.2026

Altschnee

2600m

Nassschnee

3100m

Die Gefahr von feuchten und nassen Lawinen steigt bereits am Vormittag an.

Nach klarer Nacht herrschen am Morgen günstige Verhältnisse. Die frühlingshaften Wetterbedingungen führen ab dem Vormittag zu einer zunehmenden Anfeuchtung der Schneedecke.

Vor allem aus noch nicht entladenen Einzugsgebieten und an sehr steilen Hängen sind weiterhin mittlere und vereinzelt große spontane nasse Lawinen möglich. Dies vor allem an Nordhängen sowie an steilen Ost-, Süd- und Westhängen zwischen etwa 2500 und 3100 m.

V.a. an sehr steilen Hängen sind mit der tageszeitlichen Erwärmung und der Sonneneinstrahlung weiterhin mittlere und vereinzelt große Gleitschneelawinen und feuchte Rutsche möglich.

Spontane Lawinen und Durchbrechen in den Altschnee zeigen den schwachen Schneedeckenaufbau. Touren sollten rechtzeitig beendet werden.

Schneedecke

Gefahrenmuster gm.10: frühjahrssituation

Mit Neuschnee und teils mäßigem Ostwind entstanden am Montag teils störanfällige Triebschneeansammlungen. Der Neuschnee vom Montag hat sich stark gesetzt.

Unterhalb von rund 3000 m: Die Schneedecke ist feucht, mit einer Schmelzharschkruste an der Oberfläche.

Die Schneeoberfläche weicht schon am Vormittag auf.

Sonne und Wärme führen im Tagesverlauf zu einer raschen Anfeuchtung der Schneedecke. Dies vor allem an steilen Sonnenhängen in hohen Lagen und im Hochgebirge und an allen Expositionen in tiefen und mittleren Lagen.
Unterhalb von rund 2400 m liegt an Südhängen nur wenig Schnee.

Gefahrenstufe 2 - Mäßig

AM:

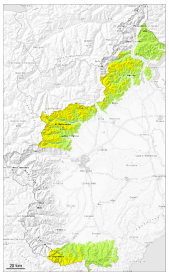

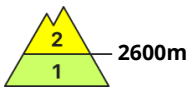

Tendenz: Lawinengefahr bleibt gleich
am Sonntag, den 19.04.2026

Nassschnee

2600m

PM:

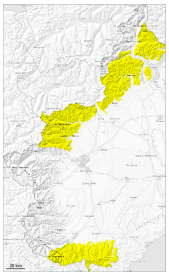

Tendenz: Lawinengefahr bleibt gleich
am Sonntag, den 19.04.2026

Nassschnee

Die Gefahr von feuchten und nassen Lawinen steigt bereits am Vormittag an.

V.a. an sehr steilen Hängen und im felsdurchsetzten Steilgelände sind mit der tageszeitlichen Erwärmung und der Sonneneinstrahlung weiterhin kleine und mittlere Gleitschneelawinen und feuchte Rutsche möglich.
Hohe Lagen und Hochgebirge: Die oberflächennahen Schneeschichten können vereinzelt von einzelnen Wintersportlern ausgelöst werden.
Spontane Lawinen und Durchbrechen in den Altschnee zeigen den schwachen Schneedeckenaufbau.

Am Nachmittag ist es gebietsweise teils bewölkt. Touren sollten rechtzeitig beendet werden.

Schneedecke

Gefahrenmuster gm.10: frühjahrssituation

Am Montag fielen oberhalb von rund 2300 m 30 bis 50 cm Schnee, lokal auch mehr. Der Neuschnee vom Montag hat sich stark gesetzt.

Unterhalb von rund 3000 m: Die Schneedecke ist feucht, mit einer Schmelzharschkruste an der Oberfläche.

Sonne und Wärme führen ab dem Morgen zu einer raschen Anfeuchtung der Schneedecke. Die Wärme führt am Vormittag an Sonnenhängen in hohen Lagen und im Hochgebirge zu einem Festigkeitsverlust innerhalb der Schneedecke. Dies vor allem an steilen Sonnenhängen in hohen Lagen und im Hochgebirge und an allen Expositionen in tiefen und mittleren Lagen.
Unterhalb von rund 2400 m liegt an Südhängen nur wenig Schnee.

Samstag 18.04.2026

Veröffentlicht am 17.04.2026 um 17:00

Gefahrenstufe 2 - Mäßig

AM:

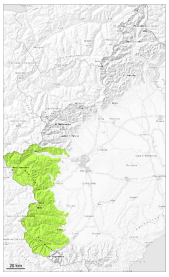

Tendenz: Lawinengefahr bleibt gleich
am Sonntag, den 19.04.2026

PM:

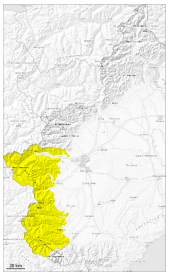

Tendenz: Lawinengefahr bleibt gleich
am Sonntag, den 19.04.2026

Nassschnee

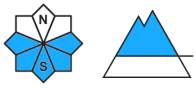

Nassschnee

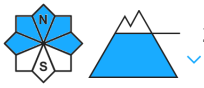

Nach klarer Nacht herrschen am Morgen verbreitet günstige Verhältnisse, dann steigt die Gefahr von nassen Lawinen an.

Morgen: Auf der harten Schneeoberfläche besteht Absturzgefahr. Für Skitouren sind die Verhältnisse mehrheitlich günstig.

Die Gefahr von feuchten und nassen Lawinen steigt im Tagesverlauf an.
V.a. an steilen Sonnenhängen sind mit der tageszeitlichen Erwärmung und der Sonneneinstrahlung kleine und mittlere feuchte und nasse Lawinen möglich. Spontane Lawinen und Durchbrechen in den Altschnee sind Hinweise für den schwachen Schneedeckenaufbau.

Touren sollten frühzeitig beendet werden. Am Nachmittag ist es gebietsweise teils bewölkt.

Schneedecke

Gefahrenmuster gm.6: lockerer schnee und wind | gm.10: frühjahrssituation

Seit Sonntag fielen oberhalb von rund 2100 m verbreitet 5 bis 30 cm Schnee.
Die Schneeoberfläche ist tragfähig gefroren und weicht schon am Vormittag auf. Dies vor allem an steilen Ost-, Süd- und Westhängen unterhalb von rund 2600 m sowie an Nordhängen unterhalb von rund 2400 m.

Unterhalb von rund 2200 m liegt an Südhängen kein Schnee.