Samstag 18.04.2026

Veröffentlicht am 17.04.2026 um 17:00

Vormittag

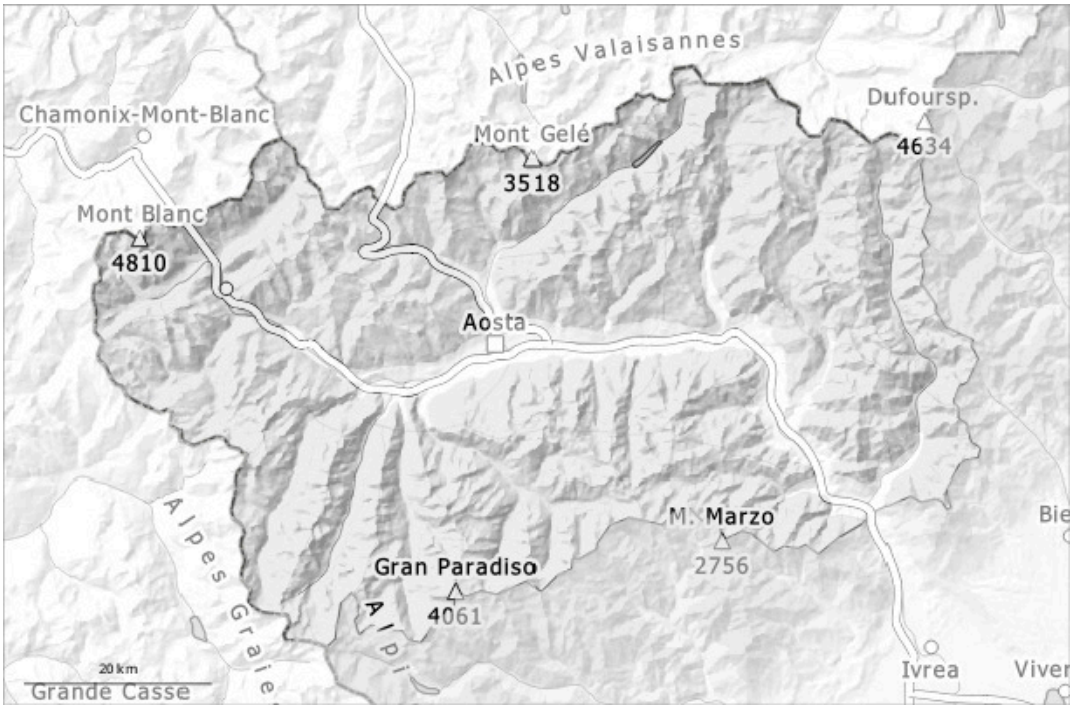

Nachmittag

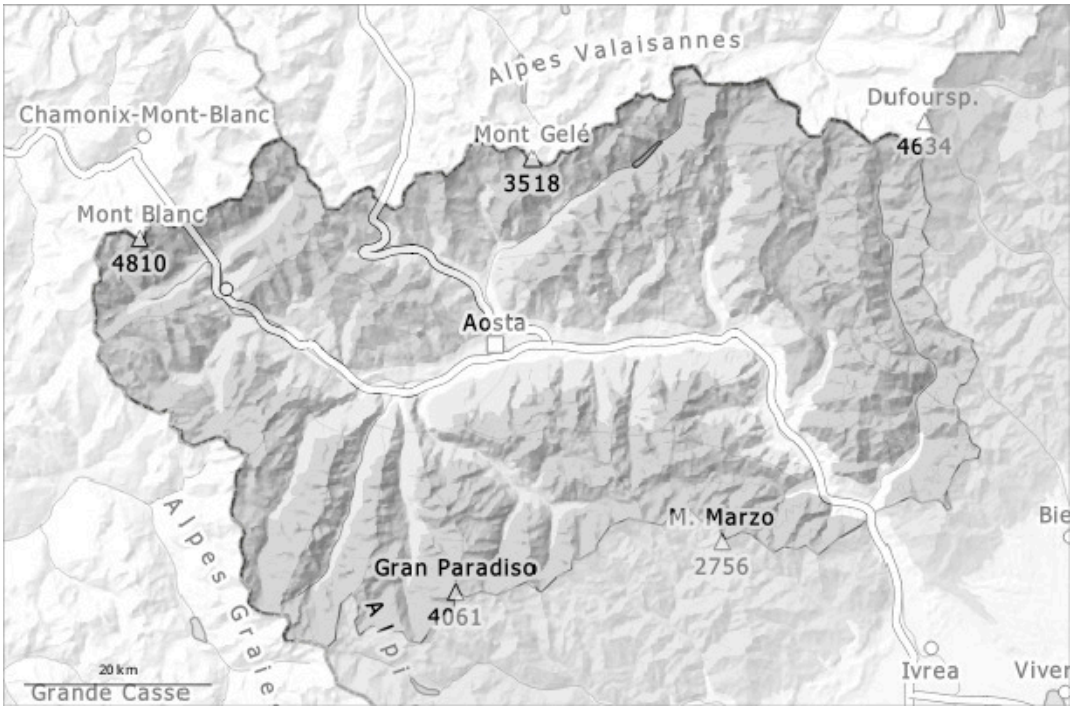

1	2	3	4	5
gering	mäßig	erheblich	groß	sehr groß

Gefahrenstufe 2 - Mäßig

AM:

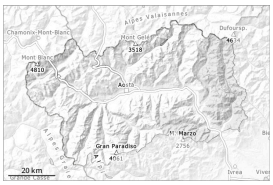

1

Tendenz: Lawinengefahr bleibt gleich
am Sonntag, den 19.04.2026

Nassschnee

N S

2500m

PM:

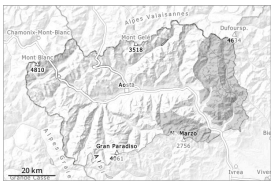

2

Tendenz: Lawinengefahr bleibt gleich
am Sonntag, den 19.04.2026

Nassschnee

N S

3200m
2200m

Die Gefahr von feuchten und nassen Lawinen steigt im Tagesverlauf an.

Morgen: Die Schneeoberfläche gefriert tragfähig. Für Skitouren sind die Verhältnisse mehrheitlich günstig. Die spontane Aktivität von Lawinen nimmt ab dem Mittag zu. Vor allem aus noch nicht entladenen Einzugsgebieten und an sehr steilen Hängen sind weiterhin mittlere und vereinzelt große spontane nasse Lawinen möglich.
Touren und Hüttenaufstiege sollten rechtzeitig beendet werden.

Schneedecke

Gefahrenmuster gm.10: frühjahrssituation

Am Montag fielen oberhalb von rund 2300 m 20 bis 40 cm Schnee, lokal auch mehr. Die Wetterbedingungen führten zu einer raschen Setzung der Schneedecke. Neu- und Triebschnee liegen auf einer nassen Altschneedecke.
In höheren Lagen nimmt die Schneedecke ab und wird ungleichmäßig; in mittleren Höhenlagen, die weniger vom Wind betroffen sind, ist sie besser. Unterhalb von rund 1900 m liegt kaum Schnee.
In der Schneedecke sind v.a. an steilen Schattenhängen Schwachschichten vorhanden.

Tendenz

Die nächtliche Abstrahlung ist teilweise reduziert. Mit der Anfeuchtung sind weiterhin feuchte und nasse Lawinen möglich.

Gefahrenstufe 2 - Mäßig

AM:

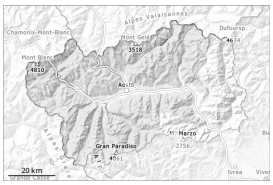

Tendenz: Lawinengefahr bleibt gleich
am Sonntag, den 19.04.2026

Nassschnee

2500m

PM:

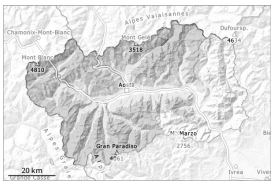

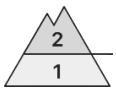

2200m

Tendenz: Lawinengefahr bleibt gleich
am Sonntag, den 19.04.2026

Nassschnee

3200m
2200m

Die Gefahr von feuchten und nassen Lawinen steigt im Tagesverlauf an.

Für Skitouren sind die Verhältnisse mehrheitlich günstig.
Die Schneeoberfläche gefriert tragfähig und weicht schon am Vormittag auf.
Mit der tageszeitlichen Erwärmung und der Sonneneinstrahlung steigt die Gefahr von feuchten und nassen Lawinen allmählich an. Aus noch nicht entladenen Einzugsgebieten und an sehr steilen Hängen sind weiterhin kleine und vereinzelt mittlere feuchte Rutsche und Lawinen möglich.
Touren und Hüttenaufstiege sollten rechtzeitig beendet werden.

Schneedecke

Gefahrenmuster gm.10: frühjahrssituation

Die Schneeoberfläche ist tragfähig gefroren. Neu- und Triebschnee liegen auf einer nassen Altschneedecke. In höheren Lagen nimmt die Schneedecke ab und wird ungleichmäßig; in mittleren Höhenlagen, die weniger vom Wind betroffen sind, ist sie besser. Unterhalb von rund 1900 m liegt kaum Schnee.
In der Schneedecke sind v.a. an steilen Schattenhängen Schwachschichten vorhanden.
Mit stabilisieren sich die Triebschneeansammlungen in den nächsten Tagen.

Tendenz

Die nächtliche Abstrahlung ist teilweise reduziert. Es sind weiterhin feuchte und nasse Lawinen möglich.