aineva.it

Samstag 18.04.2026

Veröffentlicht am 17.04.2026 um 17:00

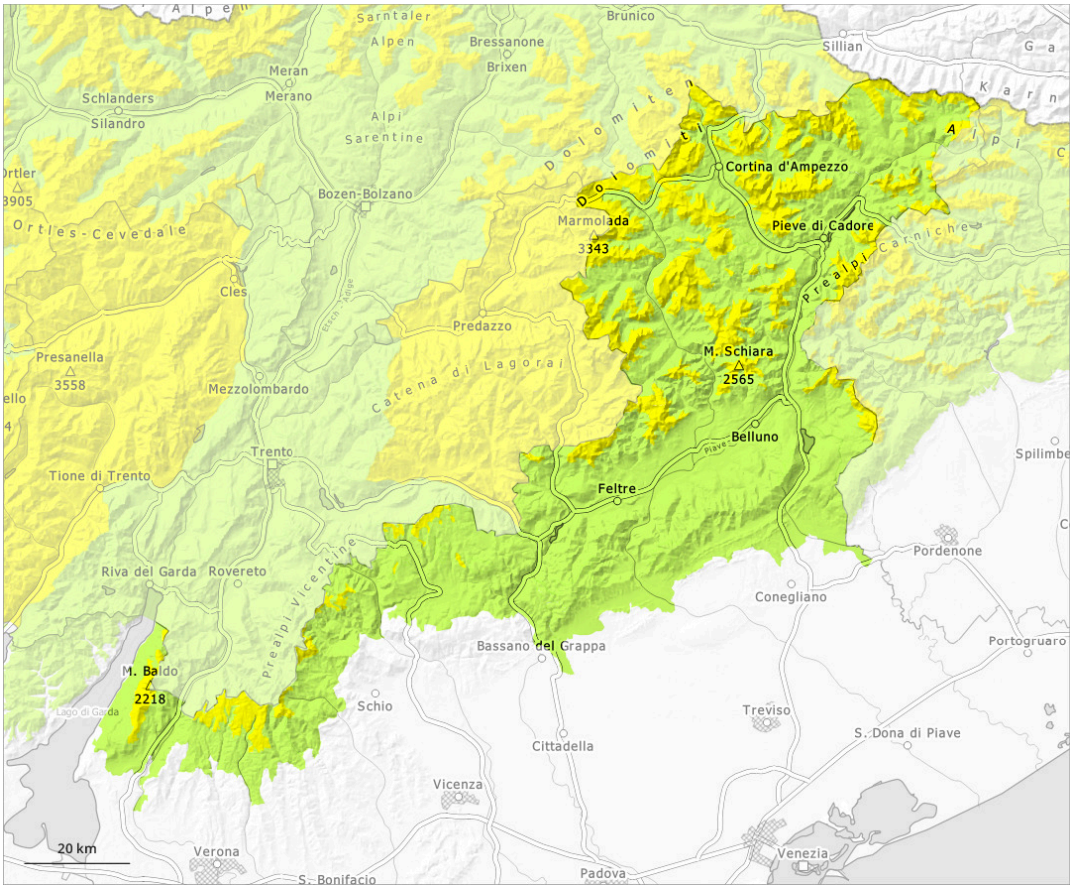

1	2	3	4	5
gering	mäßig	erheblich	groß	sehr groß

Gefahrenstufe 2 - Mäßig

1900m

Tendenz: Lawinengefahr bleibt gleich
am Sonntag, den 19.04.2026

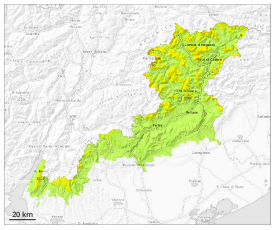

Nassschnee

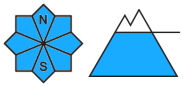

1900m

Nassschnee

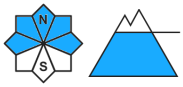

2700m

Triebschnee

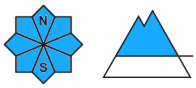

2700m

Mit Erwärmung und Sonneneinstrahlung lokal teils heimtückische Lawinensituation.

Die Gefahrenstellen für feuchte Lawinen liegen v.a. an Böschungen unterhalb von rund 2800 m. Besonders gefährlich sind Felswandfüße. Feuchte Lawinen können an sehr steilen Schattenhängen aus noch nicht vollständig entladenen Einzugsgebieten sehr vereinzelt groß werden. Mit Wind entstanden besonders oberhalb von rund 2600 m teils störanfällige Triebschneeansammlungen. Die Gefahrenstellen liegen vor allem in Kammlagen, Rinnen und Mulden der Expositionen Nordwest über Nord bis Nordost oberhalb von rund 2500 m. Besonders gefährlich sind Übergänge von wenig zu viel Schnee, wo Schwachstellen im Altschnee vorhanden sind.
Allmählicher Anstieg der Gefahr von feuchten und nassen Lawinen mit der tageszeitlichen Erwärmung und der Sonneneinstrahlung.

Schneedecke

Gefahrenmuster gm.10: frühjahrssituation | gm.1: bodennahe schwachschicht

In der Schneedecke sind an Nordwest-, Nord- und Nordosthängen heikle Schwachschichten vorhanden. Sonne und Wärme führen im Tagesverlauf vor allem an steilen Hängen unterhalb von rund 2700 m verbreitet zu einem Festigkeitsverlust innerhalb der Schneedecke. Der Neuschnee vom Dienstag ist oberhalb von rund 2800 m locker. Die Triebschneeansammlungen sind oberhalb von rund 2700 m schlecht mit dem Altschnee verbunden.