ICGC Institut Cartogràfic i Geològic de Catalunya

Servei Meteorològic de Catalunya meteo.cat

Boletín de peligro de aludes para el Pirineo de Catalunya
Del 17/04/2026 al 18/04/2026

(Válido fuera pistas de esquí y zonas no controladas)

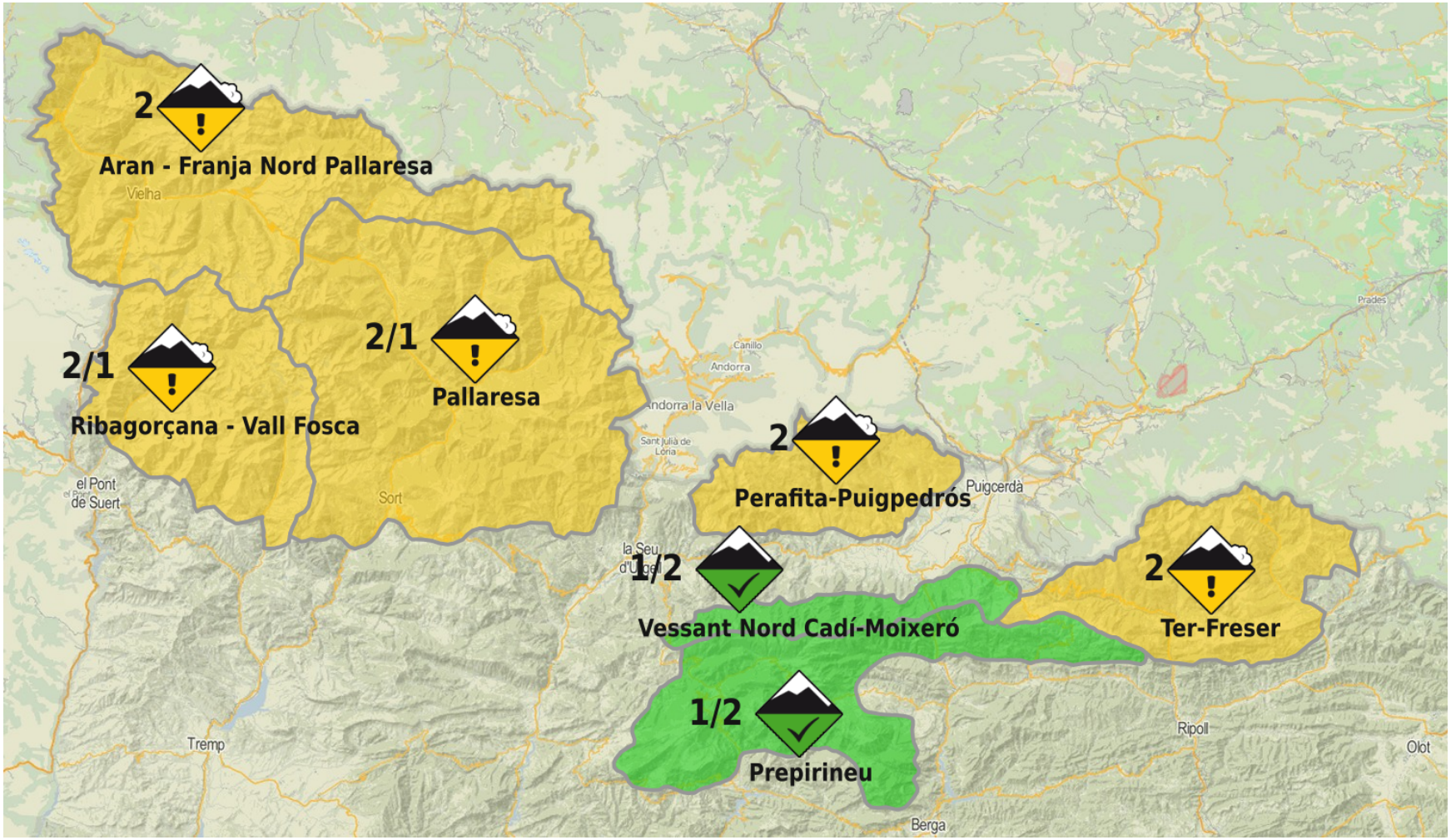

5 MUY FUERTE	4 FUERTE	3 NOTABLE	2 LIMITADO	1 DÉBIL

ICGC Institut Cartogràfic i Geològic de Catalunya

Servei Meteorològic de Catalunya

Boletín de peligro de aludes Aran - Franja Nord Pallaresa Del 17/04/2026 al 18/04/2026

(Válido fuera pistas de esquí y zonas no controladas)

Limitado (2)

Situación primaria

Deslizamientos basales **Distribución** **Tamaño** **Origen** **Tendencia**

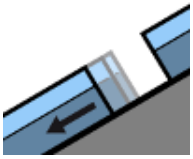

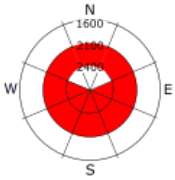

Situación secundaria

Nieve húmeda **Distribución** **Tamaño** **Origen** **Tendencia**

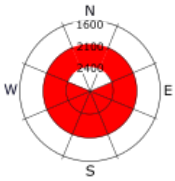

Estado del manto nivoso

El manto nivoso se encuentra húmedo por la insolación y el ascenso térmico. Además las precipitaciones previstas de mañana sábado hasta cotas altas lo humedecerá aún más. El rehielo nocturno es cada vez menor y menos eficiente. Se esperan caídas de deslizamiento basal de tamaño 2 (mediano) que incluso, de forma puntual, puedan ser de tamaño suficiente para enterrar un grupo. Los lugares más proclives son las vertientes herbosas donde ya da el Sol. Hay que prestar atención a la aparición de grietas para evitar este riesgo. Además son probables las caídas naturales de aludes de fusión, sobre todo junto a puntos oscuros como rocas y árboles. Estos aludes son más probables en las solanas por encima de los 2.200 m y hasta las cimas, pero también en umbrías de cotas medias que también les dé el Sol. Serán por lo general de tamaño 1 (pequeño, con capacidad de arrastrarnos), localmente de tamaño 2 (mediano, con capacidad de cubrir una persona).

Distribución del manto nivoso

Hay nieve en el suelo con continuidad por encima de 1.800-1.900 m en umbrías y de 2.000 m en solanas. Los espesores a unos 2.200 m rondan los 140-220 cm. Los valores están por encima de los normales por la época.

Tendencia para las próximas 48-72h

Condiciones primaverales con alta probabilidad de chubascos hasta cotas altas, que mantendrán el manto húmedo. Evolución del peligro: EN LIGERO AUMENTO.

El próximo boletín será emitido el día 2026-04-18

5 MUY FUERTE	4 FUERTE	3 NOTABLE	2 LIMITADO	1 DÉBIL

EAWS EUROPEAN AVALANCHE WARNING SERVICES

ICGC Institut Cartogràfic i Geològic de Catalunya

Servei Meteorològic de Catalunya

Boletín de peligro de aludes Ribagorçana - Vall Fosca Del 17/04/2026 al 18/04/2026

(Válido fuera pistas de esquí y zonas no controladas)

LIMTADO (2) en la mitad norte, DÉBIL (1) en la mitad sur.

Situación primaria

Deslizamientos basales **Distribución** **Tamaño** **Origen** **Tendencia**

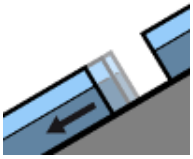

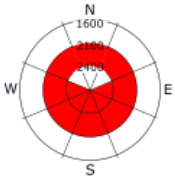

Situación secundaria

Nieve húmeda **Distribución** **Tamaño** **Origen** **Tendencia**

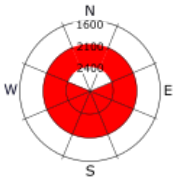

Estado del manto nivoso

El manto nivoso se humedece muy fácilmente. El rehielo nocturno es cada día menor. Con las precipitaciones del sábado hasta cotas altas se humedecerá aún más. En la mitad norte se esperan deslizamientos basales de tamaño suficiente para enterrarnos. No se descarta que en algún sitio sobreacumulado sean de tamaño suficiente para tapar un grupo. Las vertientes más proclives son donde ya toca el Sol, y de suelo herboso. Hay que prestar atención a la aparición de grietas para evitar este riesgo. También se esperan aludes de nieve húmeda, sobre todo junto a puntos oscuros (rocas y árboles). Los lugares más probables son solanas por encima de los 2200 m y hasta las cimas, también umbrías de cotas medias que ya les dé el Sol. En la mitad sur, el manto se encuentra más rehelado y duro, sobre todo en la Vall Fosca. Durante el día también pasa a fusión y se prevéN caídas naturales de aludes de fusión en general de tamaño 1 sobre todo en momentos de chubasco y en horas centrales del día.

Distribución del manto nivoso

Hay nieve por encima de 1.800-2.000 m pero esquiable en N por encima de 2.100 m-2.300 m en S. Se alcanzan los 80-100 cm a unos 2.200 m, con frecuentes deflaciones y acumulaciones por encima del nivel del bosque. Estos valores están ligeramente por debajo de los normales para la época.

Tendencia para las próximas 48-72h

Condiciones primaverales con alta probabilidad de chubascos de tarde sábado y domingo en forma de agua hasta cotas altas, que mantendrán el manto húmedo. Evolución del peligro: EN LIGERO AUMENTO.

El próximo boletín será emitido el día 2026-04-18

5 MUY FUERTE	4 FUERTE	3 NOTABLE	2 LIMITADO	1 DÉBIL

EAWS EUROPEAN AVALANCHE WARNING SERVICES

ICGC Institut Cartogràfic i Geològic de Catalunya

Servei Meteorològic de Catalunya

Boletín de peligro de aludes Pallaresa
Del 17/04/2026 al 18/04/2026

(Válido fuera pistas de esquí y zonas no controladas)

LIMITADO (2) en la mitad norte, DÉBIL (1) en la mitad sur.

Situación primaria

Deslizamientos basales | **Distribución** | **Tamaño** | **Origen** | **Tendencia**

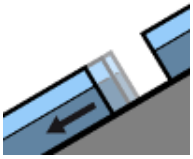

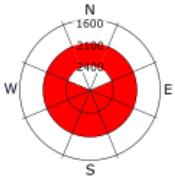

Situación secundaria

Nieve húmeda | **Distribución** | **Tamaño** | **Origen** | **Tendencia**

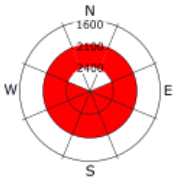

Estado del manto nivoso

El manto nivoso se humedece muy fácilmente. El rehielo nocturno es cada día menor. Con las precipitaciones del sábado hasta cotas altas se humedecerá aún más. En la mitad norte se esperan deslizamientos basales de tamaño suficiente para enterrarnos. No se descarta que en algún sitio sobreacumulado sean de tamaño suficiente para tapar un grupo. Las vertientes más proclives son donde ya toca el Sol, y de suelo herboso. Hay que prestar atención a la aparición de grietas para evitar este riesgo. También se esperan aludes de nieve húmeda, sobre todo junto a puntos oscuros (rocas y árboles). Los lugares más probables son solanas por encima de los 2200 m y hasta las cimas, también umbrías de cotas medias que ya les dé el Sol. En la mitad sur, el manto se encuentra más rehelado y duro, sobre todo en la Vall Fosca. Durante el día también pasa a fusión y se prevéN caídas naturales de aludes de fusión en general de tamaño 1 sobre todo en momentos de chubasco y en horas centrales del día.

Distribución del manto nivoso

Hay nieve por encima de 1.800-2.000 m en N por encima de 2.100-2.300 m en S. Se alcanzan los 80-100 cm a unos 2.200 m, con frecuentes deflaciones y acumulaciones por encima del nivel del bosque.

Tendencia para las próximas 48-72h

Condiciones primaverales con alta probabilidad de chubascos de tarde sábado y domingo en forma de agua hasta cotas altas, que mantendrán el manto húmedo. Evolución del peligro: EN LIGERO AUMENTO.

El próximo boletín será emitido el día 2026-04-18

5 MUY FUERTE	4 FUERTE	3 NOTABLE	2 LIMITADO	1 DÉBIL

EAWS EUROPEAN AVALANCHE WARNING SERVICES

ICGC Institut Cartogràfic i Geològic de Catalunya

Servei Meteorològic de Catalunya

Boletín de peligro de aludes Perafita-Puigpedrós Del 17/04/2026 al 18/04/2026

(Válido fuera pistas de esquí y zonas no controladas)

LIMITADO (2).

Situación primaria

Nieve húmeda

Distribución

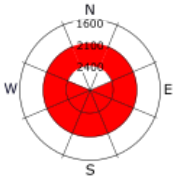

Tamaño

Origen

Tendencia

Situación secundaria

Deslizamientos basales

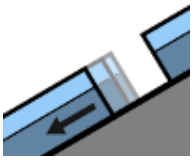

Distribución

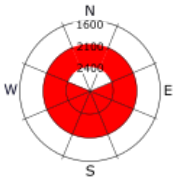

Tamaño

Origen

Tendencia

Estado del manto nivoso

El manto nivoso se humedece muy fácilmente y el rehielo nocturno es cada día menor. Se espera que continúe la caída de deslizamientos basales así como también las caídas naturales de aludes de fusión. Los deslizamientos basales serán de tamaño suficiente para enterrarnos y no se descarta que en algún lugar sobreacumulado puedan tener tamaño para tapar un grupo. Las vertientes más proclives son las vertientes de suelo herboso y todas las orientaciones donde ya toca el Sol. Hay que prestar atención a la aparición de grietas para evitar este riesgo. Los aludes de nieve húmeda se darán sobre todo junto a puntos oscuros como rocas y árboles a partir de la mañana. Los lugares más probables son las solanas por encima de los 2.200 m y hasta las cimas, pero también a umbrías de cotas medias que ya les dé el Sol. De noche y madrugada puede haber un cierto rehielo pero las costras que se formen, transforman rápidamente a fusión.

Distribución del manto nivoso

Hay nieve por encima de 1.900-2.000 m en orientaciones N y de 2.200 m en S. Se alcanzan los 40-80 cm de espesor a unos 2.400 m, con frecuentes deflaciones y acumulaciones por encima del nivel del bosque. Estos valores están algo por debajo de los normales por la época.

Tendencia para las próximas 48-72h

Condiciones primaverales con alta probabilidad de chubascos hasta cotas altas, que mantendrán el manto húmedo. Evolución del peligro: EN LIGERO AUMENTO.

El próximo boletín será emitido el día 2026-04-18

5 MUY FUERTE	4 FUERTE	3 NOTABLE	2 LIMITADO	1 DÉBIL

EAWS EUROPEAN AVALANCHE WARNING SERVICES

ICGC Institut Cartogràfic i Geològic de Catalunya

Servei Meteorològic de Catalunya

Boletín de peligro de aludes Vessant Nord Cadí-Moixeró Del 17/04/2026 al 18/04/2026

(Válido fuera pistas de esquí y zonas no controladas)

DÉBIL (1). LIMITADO (2) a partir de media mañana.

Situación primaria

Nieve húmeda

Distribución

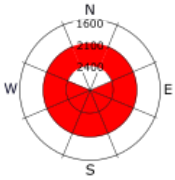

Tamaño

Origen

Tendencia

Estado del manto nivoso

El manto nivoso se transforma fácilmente a nieve húmeda por la insolación y el ascenso térmico. Pueden crecer nubarrones de tarde que también humedecerán el manto. Son probables las caídas naturales de aludes de fusión, sobre todo junto a puntos oscuros como rocas y árboles a partir de media mañana. Estos aludes son más probables en las solanas por encima de los 2.200 m y hasta las cimas, pero también en umbrías de cotas medias que ya les dé el Sol. Serán por lo general de tamaño 1 (pequeño, con capacidad de arrastrarnos); puntualmente puede haber alguna que tenga capacidad de enterrarnos (tamaño 2, mediano). De noche y madrugada pueden formarse costras, que favorecerán la estabilización, pero se transforman rápidamente en fusión desde la mañana.

Distribución del manto nivoso

Hay nieve por encima de 1.900 m en N y de 2.100 m en S. Se alcanzan los 130-150 cm a unos 2.200 m, con frecuentes deflaciones y acumulaciones por encima del nivel del bosque. Estos valores están por encima de los normales para la época.

Tendencia para las próximas 48-72h

Condiciones primaverales con alta probabilidad de chubascos hasta cotas altas, que mantendrán el manto húmedo. Evolución del peligro: EN LIGERO AUMENTO.

El próximo boletín será emitido el día 2026-04-18

5 MUY FUERTE	4 FUERTE	3 NOTABLE	2 LIMITADO	1 DÉBIL

EAWS EUROPEAN AVALANCHE WARNING SERVICES

ICGC Institut Cartogràfic i Geològic de Catalunya

Servei Meteorològic de Catalunya

Boletín de peligro de aludes Prepirineu
Del 17/04/2026 al 18/04/2026

(Válido fuera pistas de esquí y zonas no controladas)

DÉBIL (1). LIMITADO (2) a partir de media mañana.

Situación primaria

Nieve húmeda

Distribución

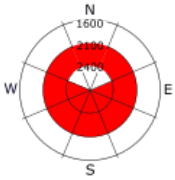

Tamaño

Origen

Tendencia

Estado del manto nivoso

El manto nivoso se transforma fácilmente a nieve húmeda por la insolación y el ascenso térmico. Pueden crecer nubarrones de tarde que también humedecerán el manto. Son probables las caídas naturales de aludes de fusión, sobre todo junto a puntos oscuros como rocas y árboles a partir de media mañana. Estos aludes son más probables en las solanas por encima de los 2.200 m y hasta las cimas, pero también en umbrías de cotas medias que ya les dé el Sol. Serán por lo general de tamaño 1 (pequeño, con capacidad de arrastrarnos); puntualmente puede haber alguna que tenga capacidad de enterrarnos (tamaño 2, mediano). De noche y madrugada pueden formarse costras, que favorecerán la estabilización, pero se transforman rápidamente en fusión desde la mañana.

Distribución del manto nivoso

Hay nieve por encima de 1.900 m en N y de 2.100-2.200 m en S. Se alcanzan los 60-80 cm a unos 2.200 m, con frecuentes deflaciones y acumulaciones por encima del nivel del bosque.

Tendencia para las próximas 48-72h

Condiciones primaverales con alta probabilidad de chubascos hasta cotas altas, que mantendrán el manto húmedo. Evolución del peligro: EN LIGERO AUMENTO.

El próximo boletín será emitido el día 2026-04-18

5 MUY FUERTE	4 FUERTE	3 NOTABLE	2 LIMITADO	1 DÉBIL

EAWS EUROPEAN AVALANCHE WARNING SERVICES

ICGC Institut Cartogràfic i Geològic de Catalunya

Servei Meteorològic de Catalunya

Boletín de peligro de aludes Ter-Freser Del 17/04/2026 al 18/04/2026

(Válido fuera pistas de esquí y zonas no controladas)

LIMITADO (2)

Situación primaria

Deslizamientos basales **Distribución** **Tamaño** **Origen** **Tendencia**

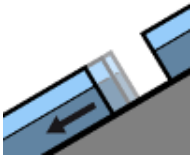

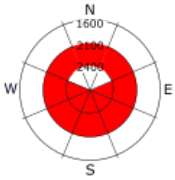

Situación secundaria

Nieve húmeda **Distribución** **Tamaño** **Origen** **Tendencia**

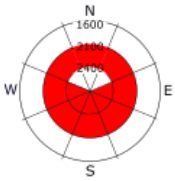

Estado del manto nivoso

El manto nivoso se humedece muy fácilmente y el rehielo nocturno es cada día menor. Ha habido actividad de deslizamientos basales en la zona. Se espera que continúe la caída de deslizamientos basales así como también las caídas naturales de aludes de fusión. Los deslizamientos basales serán de tamaño suficiente para enterrarnos y no se descarta que en algún lugar sobreacumulado puedan tener tamaño para tapar un grupo. Las vertientes más proclives son las vertientes de suelo herboso y todas las orientaciones donde ya toca el Sol. Hay que prestar atención a la aparición de grietas para evitar este riesgo. Los aludes de nieve húmeda se darán sobre todo junto a puntos oscuros como rocas y árboles a partir de la mañana. Los lugares más probables son las solanas por encima de los 2.200 m y hasta las cimas, pero también a umbrías de cotas medias que ya les dé el Sol. De noche y madrugada puede haber un cierto rehielo pero las costras que se formen, transforman rápidamente a fusión.

Distribución del manto nivoso

Hay nieve por encima de 1.900 m en N y de 2.100-2.200 m en S. Los espesores rondan los 45-75 cm a unos 2.200 m, y más de 130-190 cm por encima de 2.400 m, con frecuentes deflaciones y acumulaciones por encima. Estos valores están por encima de la media.

Tendencia para las próximas 48-72h

Condiciones primaverales con alta probabilidad de chubascos hasta cotas altas, que mantendrán el manto húmedo. Evolución del peligro: EN LIGERO AUMENTO.

El próximo boletín será emitido el día 2026-04-18

5 MUY FUERTE	4 FUERTE	3 NOTABLE	2 LIMITADO	1 DÉBIL

EAWS EUROPEAN AVALANCHE WARNING SERVICES